# Danger d'avalanche

actualisé le 10.2.2026, 08:00

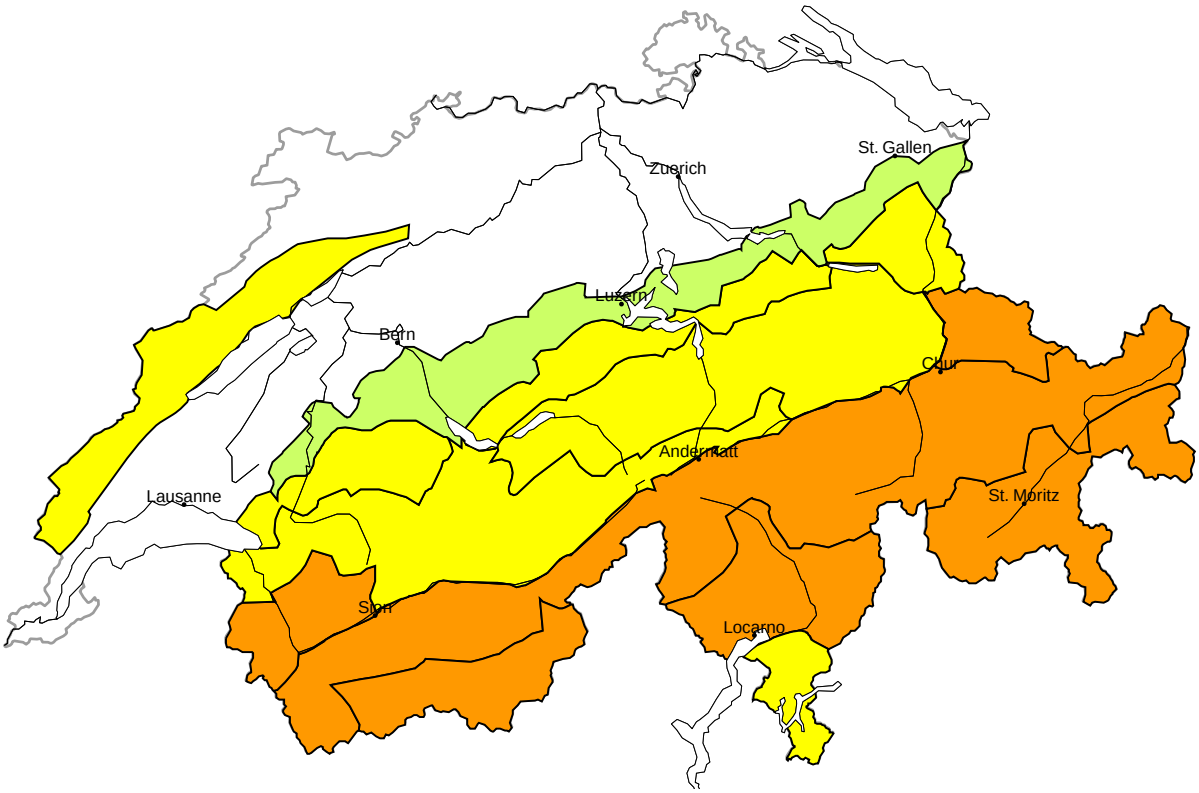


## région A — Marqué (3+)

### Couche fragile persistante

**Endroits dangereux**

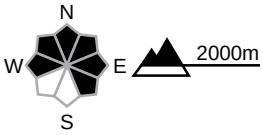


**Description des dangers**

Des couches fragiles marquées dans la neige ancienne demandent prudence et retenue. Des avalanches peuvent se déclencher dans les couches profondes du manteau neigeux et atteindre une grande taille de manière isolée. Les endroits dangereux sont fréquents. Des déclenchements à distance sont à attendre. Des bruits sourds et des fissures lors du passage sur le manteau neigeux ainsi que des avalanches récentes attirent l'attention sur le danger.
Les randonnées et descentes hors-piste demandent beaucoup d' expérience dans l'évaluation du danger d'avalanche et de la retenue.

**Degrés de danger** 1 faible | 2 limité | 3 marqué | 4 fort | 5 très fort

**Bulletin d'avalanches jusqu'à mardi, 10. février 2026**

## région B — Marqué (3=)

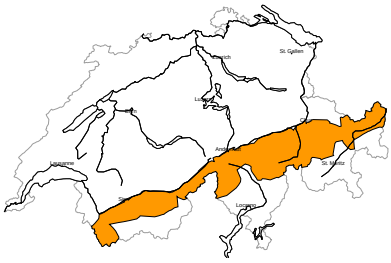

### Couche fragile persistante

**Endroits dangereux**

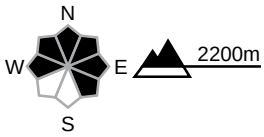


**Description des dangers**
Des couches fragiles dans la neige ancienne demandent de la prudence. Des adeptes des sports de neige même seuls peuvent déclencher des avalanches. Celles-ci peuvent se déclencher dans les couches profondes du manteau neigeux et atteindre une grande taille de manière isolée. Des déclenchements à distance sont possibles. Des bruits sourds et des fissures lors du passage sur le manteau neigeux ainsi que des avalanches récentes peuvent attirer l'attention sur le danger.
Les randonnées et descentes hors-piste demandent beaucoup d'expérience dans l'évaluation du danger d'avalanche.

## région C — Marqué (3=)

### Neige fraîche, Couche fragile persistante

**Endroits dangereux**

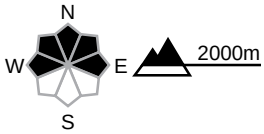


**Description des dangers**
La neige fraîche repose en général sur un manteau neigeux ancien fragile. Des adeptes des sports de neige même seuls peuvent déclencher des avalanches. Celles-ci peuvent se déclencher dans les couches profondes du manteau neigeux et atteindre une grande taille de manière isolée. Des déclenchements à distance sont possibles. Des bruits sourds et des fissures lors du passage sur le manteau neigeux ainsi que des avalanches récentes peuvent attirer l'attention sur le danger.
Les randonnées et descentes hors-piste demandent beaucoup d'expérience dans l'évaluation du danger d'avalanche.

## région D — Marqué (3-)

### Neige soufflée, Couche fragile persistante

**Endroits dangereux**

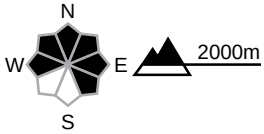


**Description des dangers**
La neige fraîche et la neige soufflée reposent sur une couche fragile de neige ancienne. Des avalanches peuvent être déjà déclenchées par un seul amateur de sports d'hiver. Des avalanches peuvent aussi par endroits être déclenchées aussi dans les couches plus profondes du manteau neigeux. Ces endroits dangereux se situent surtout aux transitions entre les endroits peu enneigés et les endroits très enneigés ainsi que dans les terrains de randonnée faiblement fréquentés. Des avalanches sont généralement de taille moyenne.
Les randonnées demandent un choix prudent des itinéraires.

## région E — Marqué (3-)

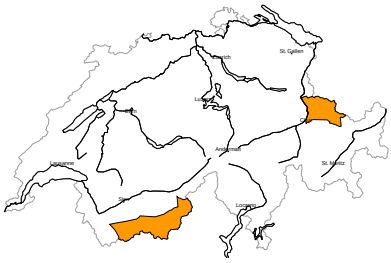

### Couche fragile persistante

**Endroits dangereux**

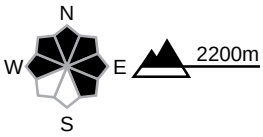


**Description des dangers**
Des couches fragiles dans la neige ancienne demandent de la prudence. Des adeptes des sports de neige même seuls peuvent par endroits déclencher des avalanches. Celles-ci peuvent se déclencher dans les couches profondes du manteau neigeux et atteindre une grande taille de manière isolée. Des déclenchements à distance sont possibles de manière isolée. Des bruits sourds et des fissures lors du passage sur le manteau neigeux peuvent attirer l'attention sur le danger.
Les randonnées et descentes hors-piste demandent beaucoup d'expérience dans l'évaluation du danger d'avalanche.

## région F — Limité (2+)

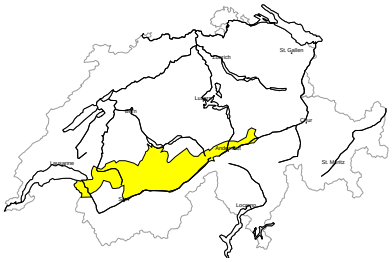

### Neige soufflée, Couche fragile persistante

**Endroits dangereux**

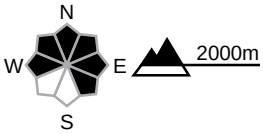


**Description des dangers**
Les accumulations récentes et anciennes de neige soufflée sont partiellement fragiles. Des avalanches peuvent aussi par endroits être déclenchées aussi dans la neige ancienne. Ces endroits dangereux se situent surtout aux transitions entre les endroits peu enneigés et les endroits très enneigés ainsi que dans les terrains de randonnée faiblement fréquentés. Des avalanches peuvent atteindre une taille moyenne.
Les randonnées demandent un choix prudent des itinéraires.

## région G — Limité (2+)

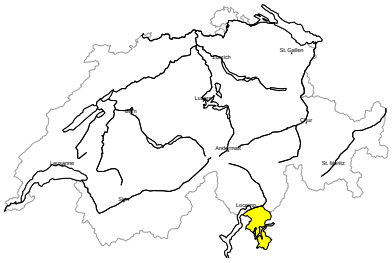

### Neige fraîche, Couche fragile persistante

**Endroits dangereux**

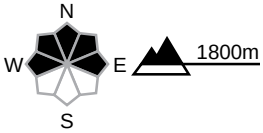


**Description des dangers**
La neige fraîche repose sur une couche fragile de neige ancienne. Des avalanches peuvent par endroits être déclenchées par un seul amateur de sports d'hiver. Des avalanches peuvent se déclencher dans les couches profondes du manteau neigeux et atteindre une taille moyenne.
Les randonnées et descentes hors-piste demandent un choix très prudent d'itinéraires.

## région H — Limité (2=)

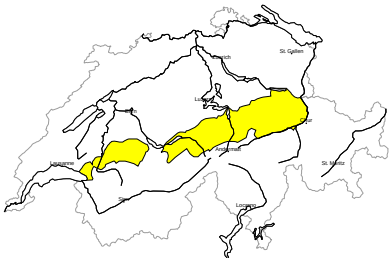

### Neige soufflée, Couche fragile persistante

**Endroits dangereux**

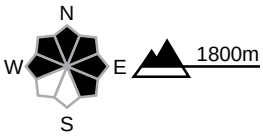


**Description des dangers**
Les accumulations récentes et déjà plus anciennes de neige soufflée sont partiellement fragiles. Les endroits dangereux se situent surtout dans les combes, couloirs et derrière les ruptures de terrain. Des avalanches peuvent aussi de manière isolée être déclenchées aussi dans la neige ancienne. Ces endroits dangereux se situent surtout aux transitions entre les endroits peu enneigés et les endroits très enneigés. Des avalanches de petite et rarement moyenne taille sont possibles. Un choix prudent des itinéraires est recommandé.

## région I — Limité (2-)

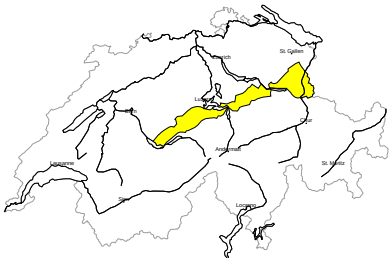

### Aucune situation avalancheuse typique prédominante

**Endroits dangereux**

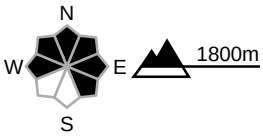


**Description des dangers**
Les couches de neige proches de la surface peuvent être déclenchées par endroits, surtout aux transitions entre les endroits peu enneigés et les endroits très enneigés, notamment à l'entrée des combes et des couloirs. Des avalanches sont généralement plutôt petites. Un choix prudent des itinéraires est recommandé.

## région J — Limité (2-)

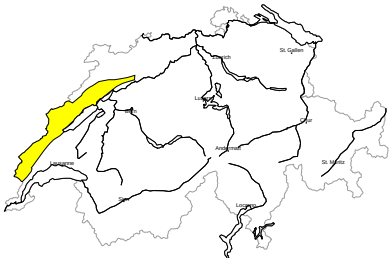

### Neige soufflée

**Endroits dangereux**

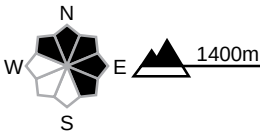


**Description des dangers**
Des accumulations de neige soufflée en général petites se forment avec la neige fraîche et le vent de sud-ouest partiellement fort. Elles devraient être évaluées avec prudence en terrain très raide. A côté du danger d'ensevelissement, il faut surtout penser au danger d'être emporté et de chuter.

## région K — Faible (1)

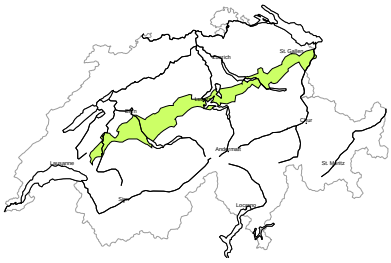

### Aucune situation avalancheuse typique prédominante

**Endroits dangereux**

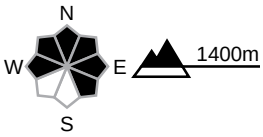


**Description des dangers**
Quelques endroits dangereux se situent sur les pentes extrêmement raides. Des avalanches sont généralement uniquement petites mais de manière isolée déclenchables par un seul amateur de sports d'hiver. Il convient de tenir compte du danger d'être emporté et entraîné dans une chute.

# Manteau neigeux et météo

actualisé le 9.2.2026, 17:00

## Manteau neigeux

Dans le sud du Valais, dans le Tessin et dans les Grisons, la constitution du manteau neigeux est souvent mauvaise. Dans les parties centrale et inférieure du manteau neigeux, on trouve des couches fragiles et instables marquées. Des bruits sourds et des avalanches déclenchées par des personnes, souvent à distance, continuent d'être signalés dans ces régions. Sur le versant nord des Alpes et dans le nord du Valais, la constitution du manteau neigeux est un peu meilleure, mais dans ces régions également, le manteau neigeux renferme des couches fragiles en profondeur. Celles-ci peuvent encore se décrocher, surtout aux endroits peu enneigés ainsi qu'aux passages de zones peu enneigées vers des zones très enneigées.

## Rétrospective météo de ce lundi

Dans le sud, le ciel était très nuageux et il est tombé un peu de neige au-dessus de 1400 m environ. Ailleurs, le temps était partiellement ensoleillé en montagne avec des nuages de plus en plus denses à partir de l'ouest.

**Neige fraîche**
Sur le centre du versant sud des Alpes, quelques centimètres au-dessus de 1400 m

**Température**
À la mi-journée à 2000 m, -3 °C

**Vent**
Sur la crête nord des Alpes, vent du sud-est temporairement modéré, mais ailleurs généralement faible

## Prévisions météorologiques jusqu'à mardi

Dans le nord, la nébulosité sera variable à forte. Des éclaircies seront possibles, surtout dans les vallées de la Viège et dans les Grisons. Dans le sud, le ciel sera très nuageux. Quelques précipitations sont attendues, surtout dans l'ouest et le sud. La limite pluie-neige se situera entre 1000 et 1500 m.

**Neige fraîche**
- Jura, extrême ouest du Bas-Valais, nord du Valais, centre du versant sud des Alpes : de 5 à 15 cm
- Ailleurs quelques centimètres, sec dans le centre des Grisons et en Engadine

**Température**
À la mi-journée à 2000 m, entre -2 °C dans le nord et -5 °C dans le sud

**Vent**
De plus en plus modéré, dans l'ouest fort du sud-ouest

## Tendance pour mercredi et jeudi

Sur le versant sud des Alpes, les deux journées seront caractérisées par une nébulosité variable avec des éclaircies et de faibles précipitations. Dans le nord, le ciel sera très nuageux avec des précipitations répétées. Le centre des précipitations se situera dans l'ouest et sur le versant nord des Alpes. Dans l'extrême ouest et le nord du Bas-Valais, on attend plus d'un mètre de neige fraîche, ailleurs 70 à 100 cm sur le versant nord des Alpes à l'ouest de la Reuss et dans le Bas-Valais, 40 à 70 cm sur le versant nord des Alpes à l'est de la Reuss et dans le Haut-Valais, ailleurs moins. La limite pluie-neige s'abaissera de 1800 m à 1200 m dans le nord et se situera à 1300 m dans le sud. Le vent d'ouest soufflera souvent fort à tempétueux. Mercredi, le danger d'avalanches augmentera rapidement et de manière marquée jusqu'au degré 4 (fort) sur l'ouest du versant nord des Alpes et dans le Valais. Le danger d'avalanches augmentera également dans les autres régions, le plus nettement sur le reste du versant nord des Alpes, dans la région du Gothard et dans le nord des Grisons.