Lawinengefahr

Aktualisiert am 10.2.2026, 17:00

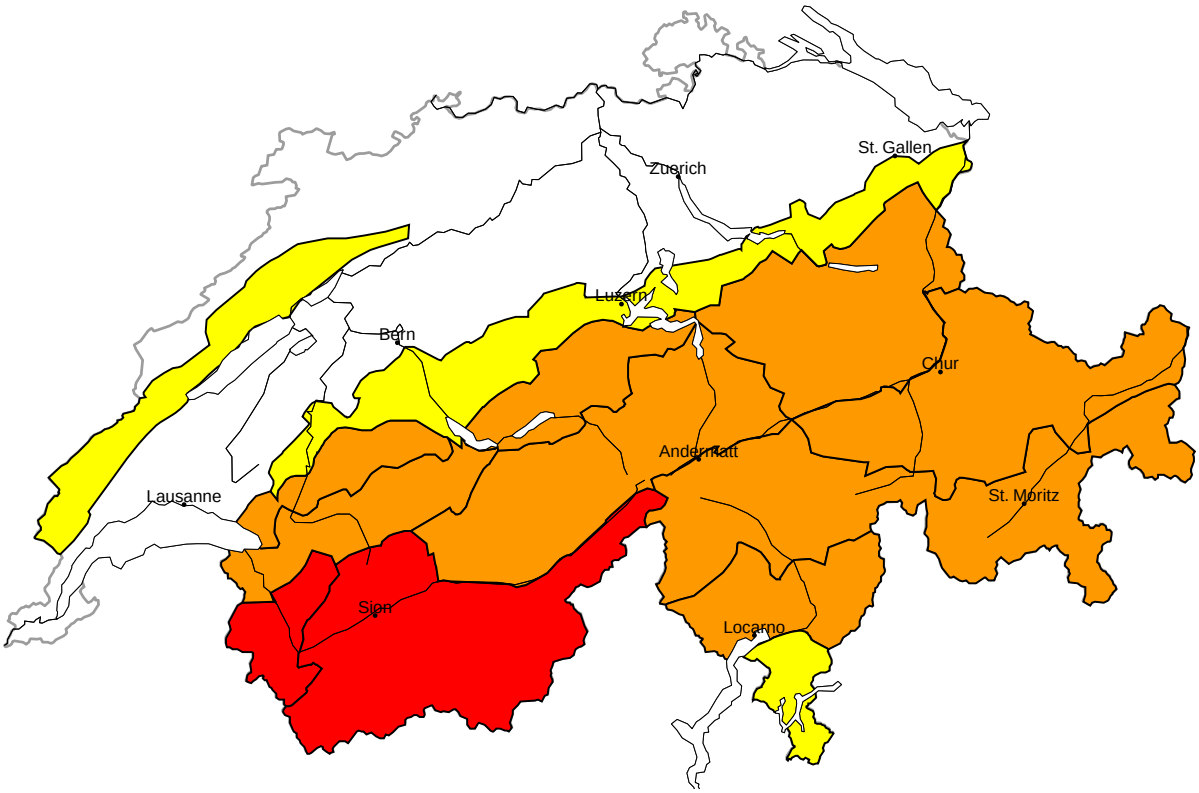

Gebiet A

Gross (4-)

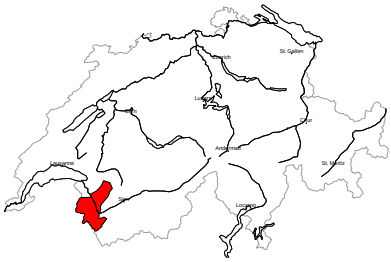

Neuschnee, Altschnee

Gefahrenstellen

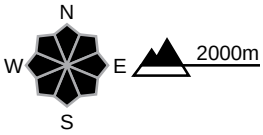

Gefahrenbeschrieb

Viel Neuschnee und Triebschnee werden auf eine schwache Altschneedecke abgelagert. Lawinen können an vielen Stellen leicht ausgelöst werden oder spontan abgehen. Mit Neuschnee und starkem Wind steigt die Lawinengefahr im Tagesverlauf innerhalb der Gefahrenstufe an. Es sind vermehrt sehr grosse Lawinen zu erwarten. Exponierte Teile von Verkehrswegen sind zunehmend gefährdet. Für Touren und Variantenabfahrten abseits gesicherter Pisten sind die Verhältnisse ungünstig.

Mässig (2)

Nassschnee

Gefahrenstellen

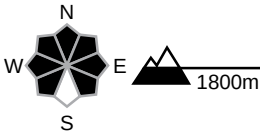

Gefahrenbeschrieb

Mit dem Regen sind nasse Rutsche und Lawinen zu erwarten. Diese können mittlere Grösse erreichen. Die Gefahrenstellen liegen in Rinnen und Mulden. Nebst der Verschüttungsgefahr sollte vor allem die Mitreiss- und Absturzgefahr beachtet werden.

Gefahrenstufen 1 gering | 2 mässig | 3 erheblich | 4 gross | 5 sehr gross

Gebiet B — Gross (4-)

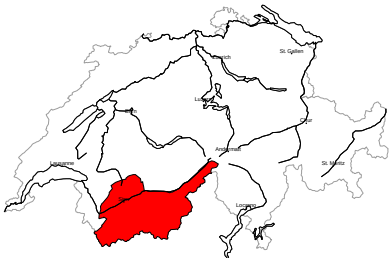

Neuschnee, Altschnee

Gefahrenstellen

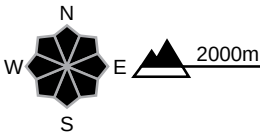

Gefahrenbeschrieb
Viel Neuschnee und Triebschnee werden auf eine schwache Altschneedecke abgelagert. Lawinen können an vielen Stellen leicht ausgelöst werden oder spontan abgehen. Mit Neuschnee und starkem Wind steigt die Lawinengefahr im Tagesverlauf innerhalb der Gefahrenstufe an. Es sind vermehrt sehr grosse Lawinen zu erwarten. Exponierte Teile von Verkehrswegen sind zunehmend gefährdet. Für Touren und Variantenabfahrten abseits gesicherter Pisten sind die Verhältnisse ungünstig.

Gebiet C — Erheblich (3+)

Neuschnee, Altschnee

Gefahrenstellen

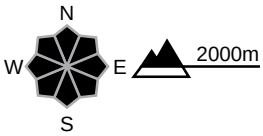

Gefahrenbeschrieb
Viel Neuschnee und Triebschnee überlagern eine schwache Altschneedecke. Lawinen können von einzelnen Wintersportlern ausgelöst werden. Sie können teilweise in tiefe Schichten durchreissen und gross werden. Es sind vermehrt spontane Lawinen möglich. Lawinen können gross werden.
Touren und Variantenabfahrten erfordern Vorsicht und Zurückhaltung.

Mässig (2)

Nassschnee

Gefahrenstellen

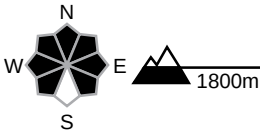

Gefahrenbeschrieb
Mit dem Regen sind nasse Rutsche und Lawinen zu erwarten. Diese können mittlere Grösse erreichen. Die Gefahrenstellen liegen in Rinnen und Mulden. Nebst der Verschüttungsgefahr sollte vor allem die Mitreiss- und Absturzgefahr beachtet werden.

Gebiet D — Erheblich (3+)

Neuschnee, Altschnee

Gefahrenstellen

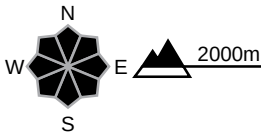

Gefahrenbeschrieb
Viel Neuschnee und Triebschnee überlagern eine schwache Altschneedecke. Lawinen können von einzelnen Wintersportlern ausgelöst werden. Sie können teilweise in tiefe Schichten durchreissen und gross werden. Es sind vermehrt spontane Lawinen möglich. Lawinen können gross werden.
Touren und Variantenabfahrten erfordern Vorsicht und Zurückhaltung.

Gebiet E — Erheblich (3+)

Altschnee

Gefahrenstellen

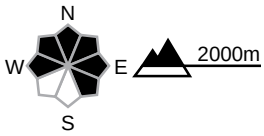

Gefahrenbeschrieb
Ausgeprägte Schwachschichten im Altschnee erfordern Vorsicht. Lawinen können in tiefen Schichten anreissen und vereinzelt gross werden. Die Gefahrenstellen sind häufig. Fernauslösungen sind zu erwarten. Wummgeräusche und Risse beim Betreten der Schneedecke sowie frische Lawinen weisen auf die Gefahr hin.
Touren und Variantenabfahrten erfordern viel Erfahrung in der Beurteilung der Lawinengefahr und Zurückhaltung.

Gebiet F

Erheblich (3=)

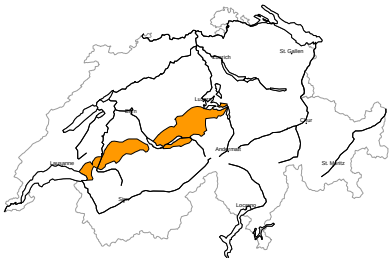

Neuschnee, Altschnee

Gefahrenstellen

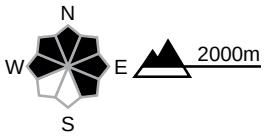

Gefahrenbeschrieb
Neu- und Triebschnee sind störanfällig. Lawinen können von einzelnen Wintersportlern ausgelöst werden. Sie können teilweise in tiefe Schichten durchreissen und gross werden.
Mit dem Schneefall steigt die Gefahr im Tagesverlauf weiter an. Es sind einzelne spontane Lawinen möglich. Touren erfordern Erfahrung in der Beurteilung der Lawinengefahr.

Mässig (2)

Nassschnee

Gefahrenstellen

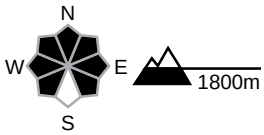

Gefahrenbeschrieb
Mit dem Regen sind nasse Rutsche und Lawinen zu erwarten. Diese können mittlere Grösse erreichen. Die Gefahrenstellen liegen in Rinnen und Mulden. Nebst der Verschüttungsgefahr sollte vor allem die Mitreiss- und Absturzgefahr beachtet werden.

Gebiet G

Erheblich (3=)

Neuschnee, Altschnee

Gefahrenstellen

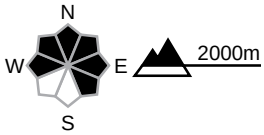

Gefahrenbeschrieb
Neu- und Triebschnee sind störanfällig. Lawinen können von einzelnen Wintersportlern ausgelöst werden. Sie können teilweise in tiefe Schichten durchreissen und gross werden.
Mit dem Schneefall steigt die Gefahr im Tagesverlauf weiter an. Es sind einzelne spontane Lawinen möglich. Touren erfordern Erfahrung in der Beurteilung der Lawinengefahr.

Gebiet H

Erheblich (3=)

Altschnee

Gefahrenstellen

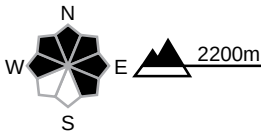

Gefahrenbeschrieb
Schwachschichten im Altschnee erfordern Vorsicht. Schon einzelne Schneesportler können Lawinen auslösen. Diese können in tiefen Schichten anreissen und vereinzelt gross werden. Fernauslösungen sind zu erwarten. Wummgeräusche und Risse beim Betreten der Schneedecke sowie frische Lawinen können auf die Gefahr hinweisen.
Touren und Variantenabfahrten erfordern viel Erfahrung in der Beurteilung der Lawinengefahr.

Gebiet I — Erheblich (3=)

Altschnee

Gefahrenstellen

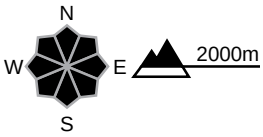

Gefahrenbeschrieb
Schwachschichten im Altschnee erfordern Vorsicht. Schon einzelne Schneesportler können Lawinen auslösen. Diese können in tiefen Schichten anreissen und vereinzelt gross werden. Fernauslösungen sind möglich. Wummgeräusche und Risse beim Betreten der Schneedecke sowie frische Lawinen können auf die Gefahr hinweisen.
Touren und Variantenabfahrten erfordern viel Erfahrung in der Beurteilung der Lawinengefahr.

Gebiet J — Mässig (2+)

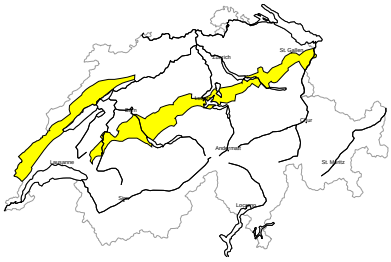

Triebschnee

Gefahrenstellen

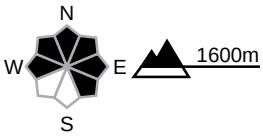

Gefahrenbeschrieb
Mit Neuschnee und starkem Westwind entstehen teils störanfällige Triebschneeansammlungen. Lawinen können mittlere Grösse erreichen. Die frischen Triebschneeansammlungen sollten vor allem im sehr steilen Gelände vorsichtig beurteilt werden.

Mässig (2)

Nassschnee

Gefahrenstellen

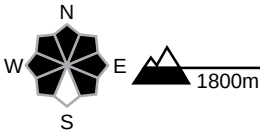

Gefahrenbeschrieb
Mit dem Regen sind nasse Rutsche und Lawinen zu erwarten. Diese können mittlere Grösse erreichen. Die Gefahrenstellen liegen in Rinnen und Mulden. Nebst der Verschüttungsgefahr sollte vor allem die Mitreiss- und Absturzgefahr beachtet werden.

Gebiet K — Mässig (2+)

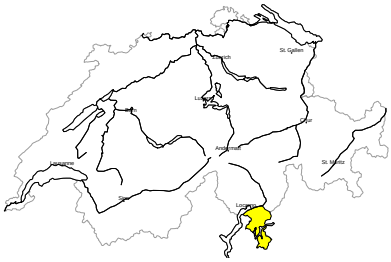

Altschnee

Gefahrenstellen

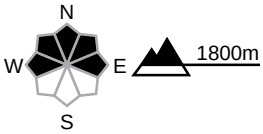

Gefahrenbeschrieb
In der Altschneedecke sind ausgeprägte Schwachschichten vorhanden. Stellenweise können Lawinen von einzelnen Wintersportlern ausgelöst werden. Lawinen können in tiefen Schichten anreissen und mittlere Grösse erreichen.
Touren und Variantenabfahrten erfordern eine defensive Routenwahl.

Schneedecke und Wetter

Aktualisiert am 10.2.2026, 17:00

Schneedecke

Es liegt in allen Gebieten deutlich weniger Schnee als sonst um diese Jahreszeit üblich, vor allem in tiefen und mittleren Lagen. Die während der nächsten Tage erwarteten, im Westen und Norden grossen Neuschneemengen fallen auf eine verbreitet ungünstig aufgebaute Schneedecke: Die Schneeoberflächen sind verbreitet aufbauend umgewandelt und locker. Zudem befinden sich im mittleren und unteren Teil der Schneedecke besonders an West-, Nord- und Osthängen ausgeprägte, störanfällige Schwachschichten, vor allem südlich einer Linie Rhone-Rhein. Nördlich davon ist der Schneedeckenaufbau etwas günstiger, aber es existieren auch in diesen Gebieten Schwachschichten tiefer in der Schneedecke. Mit dieser Ausgangslage steht vor allem im Westen und Norden ein rascher und markanter Anstieg der Lawinengefahr bevor.

Wetter Rückblick auf Dienstag

Am Dienstag war es bedeckt. In fast allen Gebieten fiel wenig Niederschlag bei einer Schneefallgrenze zwischen 1000 und 1500 m.

Neuschnee
Bis am Montagnachmittag fielen:
- Jura, westlichstes Unterwallis, nördliches Unterwallis, Tessin: 5 bis 15 cm
- sonst weniger oder trocken

Temperatur
am Mittag auf 2000 m zwischen -2 °C im Norden und -4 °C im Süden

Wind
zunehmender West- bis Südwestwind, am Nachmittag:
- im Jura und am Alpennordhang mässig bis stark
- sonst schwach bis mässig

Wetter Prognose bis Mittwoch

Im Norden ist es stark bewölkt mit Niederschlägen. Diese fallen im westlichsten und nördlichen Unterwallis sowie in den Waadtländer Alpen am intensivsten aus. Die Schneefallgrenze steigt im Westen in der Nacht auf Mittwoch gegen 2000 m und sinkt dann gegen 1300 m. Im Wallis liegt sie zeitweise tiefer. Im Süden ist es in der Nacht auf Mittwoch stark bewölkt und es fällt etwas Niederschlag. Tagsüber wird es ziemlich sonnig.

Neuschnee
Oberhalb von 2200 m fallen:
- westlichstes und nördliches Unterwallis, Waadtländer Alpen: 50 bis 80 cm
- übriger westlicher und zentraler Alpennordhang, übriges Wallis: 30 bis 50 cm
- östlicher Alpennordhang, südliches Simplongebiet, nördliches Tessin, Surselva und Prättigau: 15 bis 30 cm
- übriges Tessin und übriges Graubünden: 5 bis 15 cm

Temperatur
am Mittag auf 2000 m zwischen -2 °C im Norden und 0 °C im Süden

Wind
- entlang der Voralpen, im Westen und Norden in der Höhe starker bis stürmischer West- bis Südwestwind
- im Tessin und in Graubünden meist mässiger Wind zuerst aus Südwest, dann aus Nordwest

Tendenz für Donnerstag und Freitag

Donnerstag
Im Norden ist es weiterhin stark bewölkt mit zum Teil anhaltenden und ergiebigen Niederschlägen. Der Westwind bläst vor allem am Alpennordhang und im Westen weiterhin stark bis stürmisch. Es sind nochmals ähnliche Neuschneemengen wie am Vortrag zu erwarten. Die Schneefallgrenze liegt zwischen 1100 bis 1300 m.
Die Lawinengefahr steigt allgemein weiter an, in den Hauptniederschlagsgebieten innerhalb der Stufe 4. Dort sind vermehrt sehr grosse Lawinen zu erwarten, die in den üblichen Lawinenzügen bis in die Täler vorstossen und exponierte Verkehrswege gefährden können.

Freitag
In der Nacht zum Freitag fallen am Alpennordhang, im Unterwallis und im Prättigau nochmals 20 bis 40 cm Schnee, im übrigen Wallis und in Graubünden weniger. Die Schneefallgrenze liegt zwischen 1000 und 1200 m. Am Alpensüdhang ist es trocken. Tagsüber ist es am Alpennordhang wechselnd bewölkt, im Wallis und im Süden meist sonnig. Der Westwind flaut deutlich ab.
Die Lawinengefahr steigt in der Nacht zum Freitag nochmals etwas an und kann auch am östlichen Alpennordhang und in Nordbünden die Gefahrenstufe 4 erreichen. Am Alpennordhang sind sehr grosse Lawinen möglich sind, die bis in die Täler vorstossen und exponierte Verkehrswege gefährden können. In Graubünden bezieht sich die Gefährdung hingegen vor allem auf alpines Schneesportgelände.