GOBIERNO DE ESPAÑA
VICEPRESIDENCIA TERCERA DEL GOBIERNO
MINISTERIO PARA LA TRANSICIÓN ECOLÓGICA Y EL RETO DEMOGRÁFICO

Boletín de información nivológica y de peligro de aludes

Pirineo Navarro y Aragonés

aemet Agencia Estatal de Meteorología

miércoles, 11 de febrero de 2026

Pronóstico hasta las 24 horas del jueves, día 12 de febrero

(Válido fuera de pistas de esquí balizadas y abiertas)

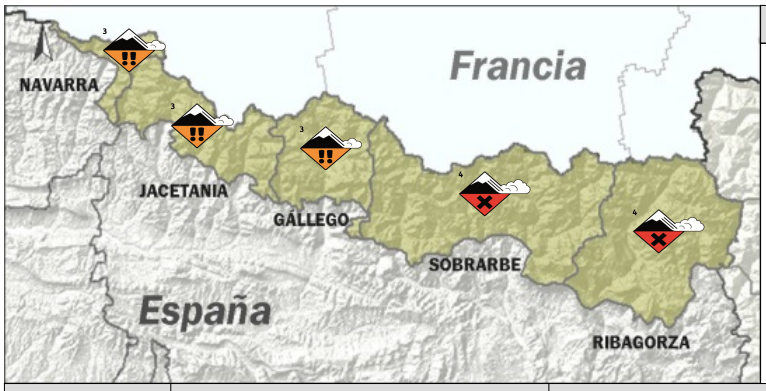

Problemas de aludes

Nieve húmeda

Placas de viento

Macizo	Peligro	Problemas de aludes, cota, orientación, tamaño	Innivación observada (m)
Navarra	3 Notable	Nieve húmeda: 2400 ↓; N O E S; 2	2026-02-11: N S Cotas bajas
Jacetania	3 Notable	Nieve húmeda: 2400 ↓; N O E S; 2 Placas de viento: 2000 ↑; N O E S; 2	2026-02-11: N S Cotas bajas
Gállego	3 Notable	Nieve húmeda: 2400 ↓; N O E S; 2 Placas de viento: 2000 ↑; N O E S; 2	2026-02-11: N S Cotas bajas
Sobrarbe	4 / 3 (2700) Fuerte	Nieve húmeda: 2400 ↓; N O E S; 2 Placas de viento: 2000 ↑; N O E S; 3	2026-02-11: N S Cotas bajas

AEMET. Se autoriza la reproducción de su contenido citando la fuente.

Boletín de información nivológica y de peligro de aludes

Pirineo Navarro y Aragonés

Ribagorza	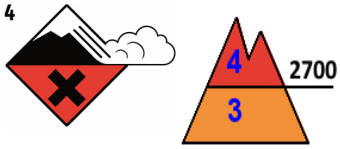 **Fuerte**	**Nieve húmeda** 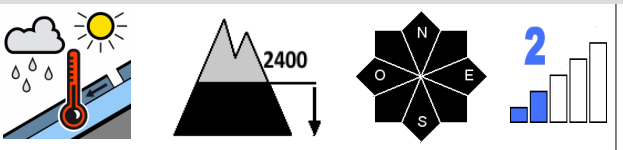 **Placas de viento** 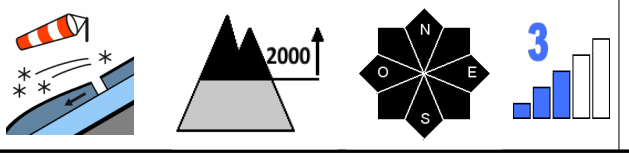	2026-02-11	Cotas bajas

Estado del manto y observaciones recientes

Las precipitaciones fueron abundantes ayer, con la lluvia afectando a cotas altas. Como resultado, se observaron gran cantidad de aludes naturales de nieve húmeda, así como algunos deslizamientos basales, en su gran mayoría de tamaño mediano.

Hoy miércoles se presenta una situación muy similar, con cantidades de precipitación algo inferiores. Como consecuencia, se está produciendo una importante humidificación de la nieve, al menos hasta los 2500 metros, que aunque en cotas bajas haya alcanzado la base del manto, en las altas ha quedado restringida a la capa superficial. Por encima de unos 2700-2800 metros, la nieve se ha mantenido más seca, al tiempo que se han sumado cantidades importantes de nieve nueva.

La otra consecuencia de las lluvias ha sido la merma de espesores, contabilizándose en algunos casos reducciones de hasta 30 cm. A pesar de ello, el manto sigue iniciándose en cotas bajas con espesores que se van incrementando conforme ascendemos, de manera que en torno a 2.100 metros se superan fácilmente los 180 a 200 cm, aún más en ventisqueros, hoyas y otras zonas propensas a la acumulación.

Evolución del manto y peligro de aludes para el jueves, día 12

Problema de nieve húmeda. Problema de placas de viento en cotas altas.

Durante la madrugada, los problemas de nieve húmeda asociados a la lluvia irán limitándose a las cotas bajas a medida que descienda la cota de nieve. Conforme avance el día, la radiación solar los reactivará en cotas medias, e incluso altas, y serán de esperar algunas purgas de tamaño mediano en laderas con la suficiente inclinación, sobre todo solanas. No se descarta algún deslizamiento basal que pueda alcanzar un tamaño mayor.

Las nevadas darán lugar a nuevas placas de viento en cotas altas, preferentemente en orientaciones este. Estas se depositarán generalmente sobre nieve húmeda o costra de rehielo, y su desencadenamiento, posible ante sobrecargas débiles, podrá dar lugar a aludes de tamaño pequeño o mediano. A partir de 2700-2800 metros, es posible que estas nuevas placas se depositen sobre otras recientes todavía frágiles. Además, las capas débiles persistentes todavía podrían ser activadas en umbrías en zonas con manto delgado. De este modo, a dichas altitudes son de esperar aludes de tamaños superiores.

AEMET. Se autoriza la reproducción de su contenido citando la fuente.

Predicción meteorológica para el jueves, día 12

Pirineo navarro:
Nuboso o muy nuboso, con apertura de claros por la tarde y tendencia a cubrirse a últimas horas. Se esperan precipitaciones débiles o localmente moderadas, principalmente durante la primera mitad del día. Cota de nieve: fluctuante, entre 1200 y 1600 metros aproximadamente. Temperaturas en ligero o moderado descenso. Heladas débiles o localmente moderadas en cotas altas. Soplarán vientos fuertes o muy fuertes de componente oeste, con rachas que podrán superar los 100km/h en cotas altas y zonas expuestas.

Pirineo aragonés:
Nuboso o muy nuboso, especialmente en la divisoria fronteriza, con apertura de algunos claros por la tarde y tendencia a cubrirse a últimas horas. Se esperan precipitaciones débiles o localmente moderadas, especialmente en el entorno de la divisoria fronteriza, más frecuentes en la Jacetania y Alto Gállego y con tendencia remitir al final del día. Cota de nieve: fluctuante, bajando de 1700 a unos 1100 metros, para volver a subir en torno a 1400 a últimas horas. Temperaturas en ligero o moderado descenso. Heladas débiles, moderadas y generalizadas en cotas altas, donde podrán ser localmente fuertes y persistentes. Soplarán vientos fuertes de componente oeste, con rachas muy fuertes en cotas altas y zonas expuestas, donde no se descarta que puedan llegar a ser huracanadas.

Datos en la atmósfera libre:

Altitud de la isoterma de 0 ºC: 1600 m
Altitud de la isoterma de -10 ºC: 3000 m

Viento a 1500 m: NW 90 km/h
Viento a 3000 m: NW 120 km/h

Evolución para el viernes día 13

Nivel de peligro en ligero ascenso, por aumento de los problemas de nieve seca.

(Información elaborada a partir de los datos recibidos de los refugios de Linza, Lizara, Panticosa, Bachimaña, Góriz, Pineta, Estós, Angel Orús, La Renclusa, Cap de Llauset y Belagua, de las estaciones de esquí de Astún, Formigal y Panticosa (lagos) y de la estación de esquí de fondo de Llanos del Hospital)

Escala europea de peligro de aludes

Débil | Limitado | Notable | Fuerte | Muy Fuerte

Problemas de aludes

Nieve reciente | Placas de viento | Capas débiles persistentes | Nieve húmeda | Deslizamientos basales | Sin problema evidente

Nota1: Se recuerda que, siempre que haya nieve, la ausencia total de peligro no existe. Hay que tener presente que en circunstancias desfavorables, con aludes de tamaño 1 (alud pequeño o colada) y tamaño 2 (alud mediano), se pueden sufrir severos daños personales.

Nota2: Los BPA se elaboran en base a información meteorológica así como al estado del manto nivoso a través de sondeos puntuales. Se advierte a los usuarios de la variabilidad de esta información al extrapolarla a zonas extensas de montaña. Por ello, AEMET no se hace responsable de su uso para la toma de decisiones que conciernen a la seguridad personal, ni de los riesgos físicos o materiales de ellas derivadas.

AEMET. Se autoriza la reproducción de su contenido citando la fuente.