aineva.it

# Donnerstag 12.02.2026

Veröffentlicht am 11.02.2026 um 17:00

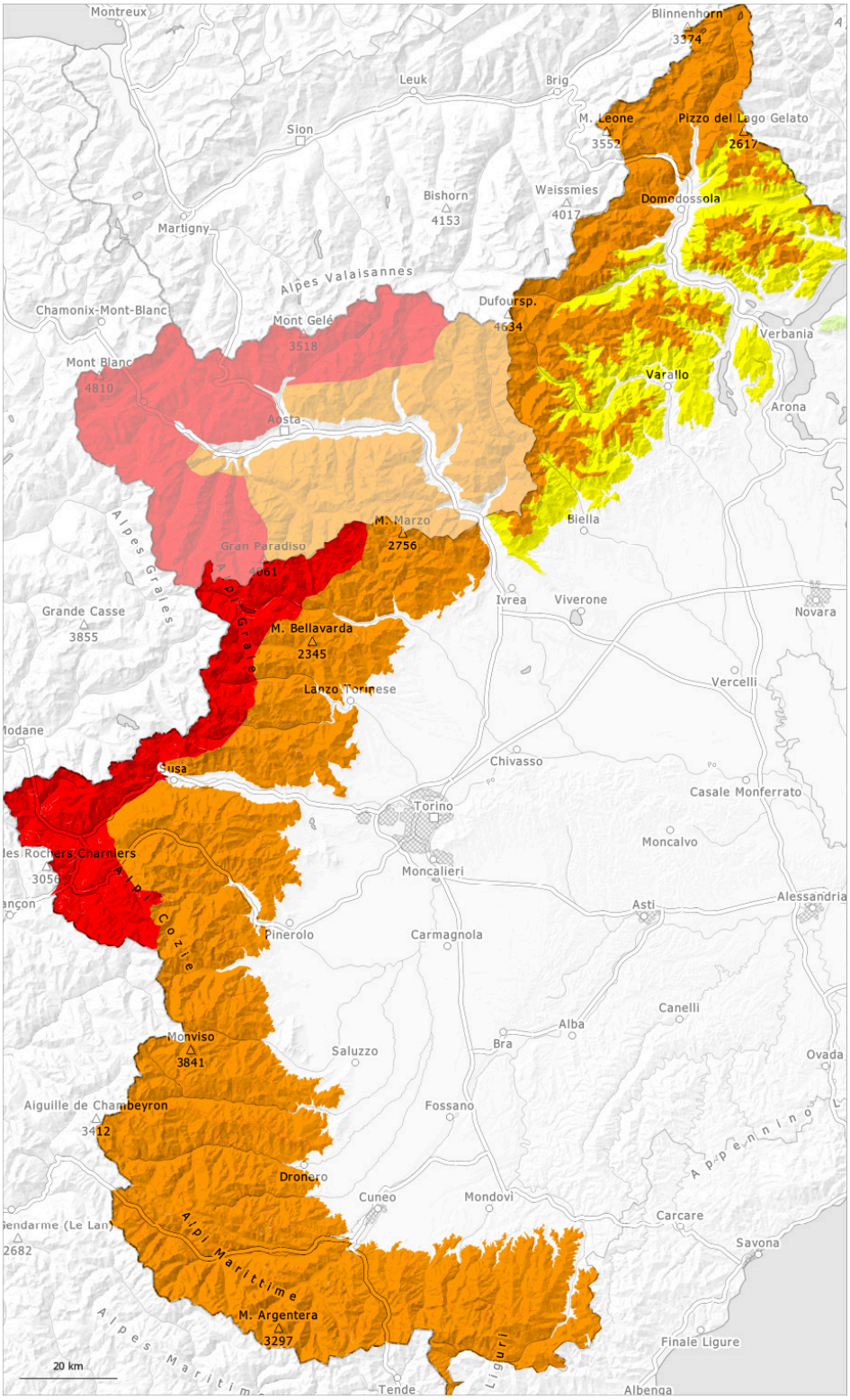


| 1 | 2 | 3 | 4 | 5 |
|---|---|---|---|---|
| gering | mäßig | erheblich | groß | sehr groß |

## Gefahrenstufe 4 - Groß

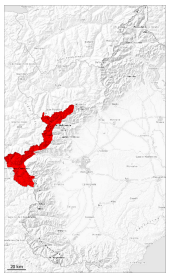

**Tendenz: Lawinengefahr nimmt ab**
am Freitag, den 13.02.2026

Neuschnee

Triebschnee

**1800m**

### Neu- und Triebschnee: Aus hoch gelegenen Einzugsgebieten muss mit spontanen großen Lawinen gerechnet werden.

Mit Neuschnee und Sturm wachsen die Triebschneeansammlungen im Tagesverlauf stark an. Dies vor allem in Rinnen, Mulden und hinter Geländekanten sowie kammfern oberhalb der Waldgrenze.

Neu- und Triebschnee können an vielen Stellen leicht ausgelöst werden und groß werden.
Entlang der Grenze zu Frankreich sind die Gefahrenstellen häufiger und größer. Diese Stellen sind bei der schlechten Sicht kaum zu erkennen.

Zudem können Lawinen auch tiefere Schichten der Schneedecke mitreißen und sehr groß werden. Exponierte Teile von Verkehrswegen können dann lokal gefährdet sein.

## Schneedecke

**Gefahrenmuster** gm.6: lockerer schnee und wind

Am Mittwoch fielen oberhalb von rund 1800 m 15 bis 25 cm Schnee. Am Donnerstag fallen oberhalb von rund 2000 m verbreitet 25 bis 50 cm Schnee. Mit Neuschnee und mäßigem bis starkem Wind aus nordwestlichen Richtungen entstanden vor allem oberhalb der Waldgrenze weitere Triebschneeansammlungen. Neu- und Triebschnee liegen an windgeschützten Schattenhängen auf weichen Schichten.

Mittlere und hohe Lagen: Im unteren Teil der Altschneedecke sind vor allem an Schattenhängen grobkörnige Schwachschichten vorhanden.

## Tendenz

Die spontane Lawinenaktivität nimmt mit dem Ende der Niederschläge allmählich ab. Entlang der Grenze zu Frankreich und an Triebschneehängen ist die Auslösebereitschaft hoch. Die Lawinen können vor allem aus noch nicht entladenen Einzugsgebieten abgehen.

## Gefahrenstufe 3 - Erheblich

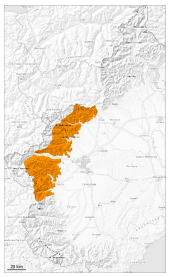

**Tendenz: Lawinengefahr bleibt gleich**
am Freitag, den 13.02.2026

Triebschnee

2000m

Neuschnee

Mit Neuschnee und Wind nehmen die Gefahrenstellen im Tagesverlauf zu. In den an die Gefahrenstufe 4, "groß" angrenzenden Gebieten sind die Gefahrenstellen häufiger.

Der Neuschnee sowie die während dem Schneefall entstehenden Triebschneeansammlungen müssen an allen Expositionen oberhalb der Waldgrenze vorsichtig beurteilt werden. Die Gefahrenstellen liegen besonders in Kammlagen, Rinnen und Mulden sowie an Triebschneehängen.
In der Höhe sind diese Gefahrenstellen häufiger. Sie sind bei der schlechten Sicht kaum zu erkennen.

Neu- und Triebschnee können schon von einzelnen Wintersportlern ausgelöst werden oder spontan abgehen. Zudem können Lawinen auch im Altschnee anbrechen und groß werden.

Eine vorsichtige Routenwahl und Entlastungsabstände werden empfohlen.

## Schneedecke

**Gefahrenmuster** gm.6: lockerer schnee und wind

Am Mittwoch fielen oberhalb von rund 1800 m 5 bis 15 cm Schnee. Es fallen gebietsweise oberhalb von rund 2000 m 10 bis 20 cm Schnee.
Der teilweise stürmische Wind verfrachtet den Neuschnee intensiv. Die Triebschneeansammlungen liegen vor allem an Schattenhängen auf weichen Schichten.

Die ungewöhnlichen Wetterbedingungen führen zu einem ungünstigen Aufbau der Schneedecke.
Mittlere und hohe Lagen: Im unteren Teil der Schneedecke sind vor allem an Schattenhängen grobkörnige Schwachschichten vorhanden.
Hohe Lagen und Hochgebirge: Der teilweise starke Wind hat Neu- und Altschnee intensiv verfrachtet.

## Gefahrenstufe 3 - Erheblich

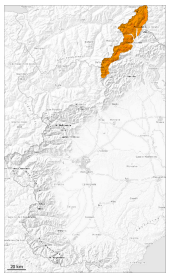

**Tendenz: Lawinengefahr bleibt gleich**
am Freitag, den 13.02.2026

Neuschnee

Triebschnee

**1700m**

### Allmählicher Anstieg der Lawinengefahr mit Neuschnee und starkem Wind. Dies vor allem in den Hauptniederschlagsgebieten.

Mit Neuschnee und starkem Wind aus nordwestlichen Richtungen entstehen verbreitet Triebschneeansammlungen. Dies vor allem in Rinnen, Mulden und hinter Geländekanten besonders oberhalb der Waldgrenze.

Neu- und Triebschnee können schon von einzelnen Wintersportlern ausgelöst werden und groß werden.

Zudem können Lawinen auch in tiefen Schichten ausgelöst werden und v.a. an Schattenhängen vereinzelt sehr groß werden. Die Gefahrenstellen sind bei der schlechten Sicht kaum zu erkennen.

Eine überlegte Routenwahl ist nötig. Entlastungsabstände und Einzelabfahrten werden empfohlen.

## Schneedecke

**Gefahrenmuster** gm.6: lockerer schnee und wind

Am Mittwoch fielen oberhalb von rund 1500 m 10 bis 20 cm Schnee. Am Donnerstag fallen oberhalb von rund 1800 m verbreitet 15 bis 30 cm Schnee. Mit Neuschnee und mäßigem bis starkem Wind aus nordwestlichen Richtungen entstanden vor allem oberhalb der Waldgrenze weitere Triebschneeansammlungen. Neu- und Triebschnee liegen an windgeschützten Schattenhängen auf weichen Schichten.

Mittlere und hohe Lagen: Im unteren Teil der Schneedecke sind vor allem an Schattenhängen grobkörnige Schwachschichten vorhanden.
Hohe Lagen und Hochgebirge: Der teilweise starke Wind hat Neu- und Altschnee intensiv verfrachtet.

## Tendenz

Die Lawinengefahr nimmt noch nicht ab. Entlang der Grenze zwischen dem Wallis und Italien und an

> Triebschneehängen ist die Auslösebereitschaft hoch.

## Gefahrenstufe 3 - Erheblich

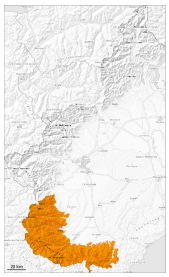

**Tendenz: Lawinengefahr nimmt ab**
am Freitag, den 13.02.2026

Triebschnee

1500m

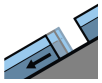

Gleitschnee

Die Triebschneeansammlungen bleiben in mittleren und hohen Lagen bis auf weiteres störanfällig. Entlang der Grenze zu Frankreich sind die Gefahrenstellen häufiger.

Entlang der Grenze zu Frankreich leichter Niederschlag.

Frischere Triebschneeansammlungen können an allen Expositionen und allgemein in der Höhe von einzelnen Wintersportlern ausgelöst werden. Dies vor allem an steilen Hängen und in Kammlagen, Rinnen und Mulden.
Die Lawinen können in den verschiedenen Neu- und Triebschneeschichten anreißen und groß werden. Zudem sind einzelne Gleitschneelawinen möglich.

Eine vorsichtige Routenwahl und Entlastungsabstände werden empfohlen.

### Schneedecke

**Gefahrenmuster** gm.6: lockerer schnee und wind | gm.2: gleitschnee

Es fielen vor allem entlang der Grenze zu Frankreich oberhalb von rund 2200 m lokal bis zu 15 cm Schnee. Mit hohen Temperaturen und Regen bis in mittlere Lagen konnte sich die Schneedecke in den letzten Tagen nicht verfestigen.
Oberhalb von rund 1500 m liegt viel Schnee.
Die ungewöhnlichen Wetterbedingungen führen zu einem ungünstigen Aufbau der Schneedecke.

### Tendenz

Die spontane Lawinenaktivität nimmt mit dem Abflauen des Windes allmählich ab.

## Gefahrenstufe 3 - Erheblich

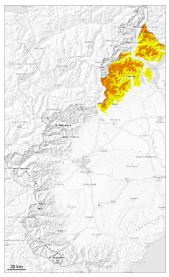

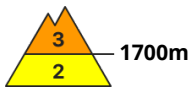


**Tendenz: Lawinengefahr bleibt gleich**
am Freitag, den 13.02.2026

Triebschnee

Neuschnee

### Mit Neuschnee und Wind nehmen die Gefahrenstellen im Tagesverlauf zu. Oberhalb der Waldgrenze erhebliche Lawinengefahr.

Der Neuschnee sowie die während dem Schneefall entstehenden Triebschneeansammlungen müssen an allen Expositionen oberhalb der Waldgrenze vorsichtig beurteilt werden. Die Gefahrenstellen liegen besonders in Kammlagen, Rinnen und Mulden sowie an steilen Hängen.
In der Höhe sind diese Gefahrenstellen häufiger. Sie sind bei der schlechten Sicht kaum zu erkennen.

Neu- und Triebschnee können schon von einzelnen Wintersportlern ausgelöst werden oder spontan abgehen. Zudem können Lawinen auch im Altschnee anbrechen und groß werden.

Eine vorsichtige Routenwahl und Entlastungsabstände werden empfohlen.

## Schneedecke

**Gefahrenmuster** gm.6: lockerer schnee und wind

Es fielen verbreitet oberhalb von rund 1800 m 10 bis 20 cm Schnee. Am Donnerstag fällt Schnee oberhalb von rund 1200 m. Der starke Wind verfrachtet den Neuschnee und teilweise auch Altschnee.
Die Triebschneeansammlungen liegen vor allem an Schattenhängen auf weichen Schichten.

Im unteren Teil der Schneedecke sind an Schattenhängen einzelne Schwachschichten vorhanden. Dies vor allem in der Höhe.