Donnerstag 12.02.2026

Veröffentlicht am 11.02.2026 um 17:00

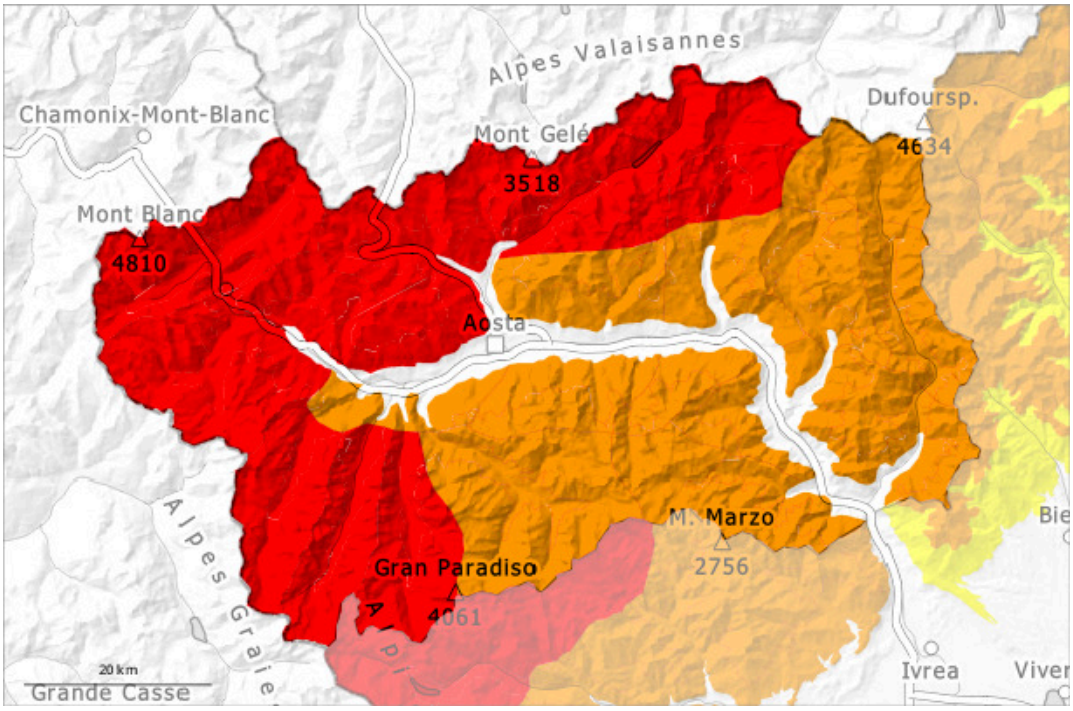

1	2	3	4	5
gering	mäßig	erheblich	groß	sehr groß

Gefahrenstufe 4 - Groß

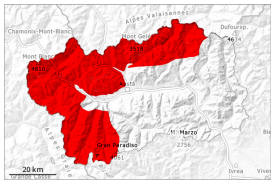

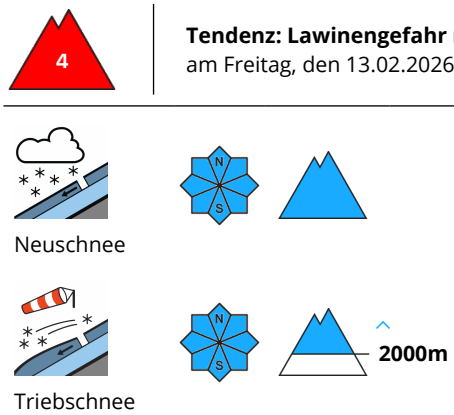

Die Lawinengefahr liegt in allen Gebieten im oberen Bereich der Gefahrenstufe 4, "groß". Verbreitet kritische Lawinensituation. V.a. entlang der Grenze zu Frankreich und entlang der Grenze zur Schweiz sind die Gefahrenstellen weiter verbreitet.

Sehr gefährliche Lawinensituation mit drei sich überschneidenden Lawinenproblemen: Neuschnee, Triebschnee und anhaltende schwache Schichten.
Viel Neuschnee und Triebschnee überlagern eine schwache Altschneedecke. Lawinen können an vielen Stellen sehr leicht ausgelöst werden. Mit Neuschnee und starkem Wind sind spontane Lawinen zu erwarten, auch große. Die Lawinen können in tiefen Schichten ausgelöst werden und sehr groß werden. Die Lawinen können in den typischen Lawinenzügen bis in Tallagen vorstoßen und exponierte Verkehrswege gefährden. Die bereits entleerten Einzugsgebiete werden mit Schneefall und Wind wieder aufgefüllt.

Für Touren und Variantenabfahrten abseits gesicherter Pisten sind die Verhältnisse sehr kritisch.

Schneedecke

Gefahrenmuster gm.6: lockerer schnee und wind | gm.1: bodennahe schwachschicht

Mittwoch: Am Vormittag fielen oberhalb von rund 1600 m 40 bis 60 cm Schnee, lokal auch mehr.
Bis Donnerstag fallen oberhalb von rund 2000 m 40 bis 80 cm Schnee, lokal auch mehr.
Die Wetterbedingungen führen zu einem ungünstigen Aufbau der Schneedecke. Der viele Neuschnee und die während dem Schneefall entstehenden Triebschneeansammlungen verbinden sich in mittleren und hohen Lagen schlecht mit dem Altschnee.

Tendenz

Der viele Neuschnee sowie die an allen Expositionen entstehenden Triebschneeansammlungen bilden die Hauptgefahr. Die spontane Lawinenaktivität nimmt mit dem Ende der intensiven Niederschläge ab.

Gefahrenstufe 3 - Erheblich

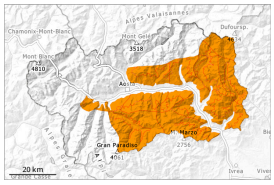

Tendenz: Lawinengefahr nimmt ab
am Freitag, den 13.02.2026

Neuschnee

2100m

Altschnee

2000m

In den an die Gefahrenstufe 4, "groß" angrenzenden Gebieten sind die Gefahrenstellen häufiger.

Mit Neuschnee und starkem Wind entstehen am Donnerstag störanfällige Triebschneeansammlungen. Es sind spontane Lawinen möglich. Die Lawinen können besonders an sehr steilen Hängen im Altschnee ausgelöst werden und recht groß werden.
Schon einzelne Wintersportler können Lawinen auslösen. Fernauslösungen sind möglich.
Schwachschichten im Altschnee erfordern Vorsicht. Wummgeräusche und Risse beim Betreten der Schneedecke sind Alarmzeichen.

Schneedecke

Gefahrenmuster gm.6: lockerer schnee und wind | gm.1: bodennahe schwachschicht

Bis Donnerstag fallen oberhalb von rund 1800 m 5 bis 20 cm Schnee, lokal auch mehr.
Die Wetterbedingungen führen zu einem ungünstigen Aufbau der Schneedecke. Der starke Wind verfrachtet den Neuschnee.
In der Altschneedecke sind v.a. an West-, Nord- und Osthängen kantig aufgebaute Schwachschichten vorhanden.

Tendenz

Der Neuschnee sowie die an allen Expositionen entstehenden Triebschneeansammlungen bilden die Hauptgefahr. Die spontane Lawinenaktivität nimmt mit dem Ende der Niederschläge ab.