ICGC Institut Cartogràfic i Geològic de Catalunya

Servei Meteorològic de Catalunya meteo.cat

Boletín de peligro de aludes para el Pirineo de Catalunya
Del 11/02/2026 al 12/02/2026

(Válido fuera pistas de esquí y zonas no controladas)

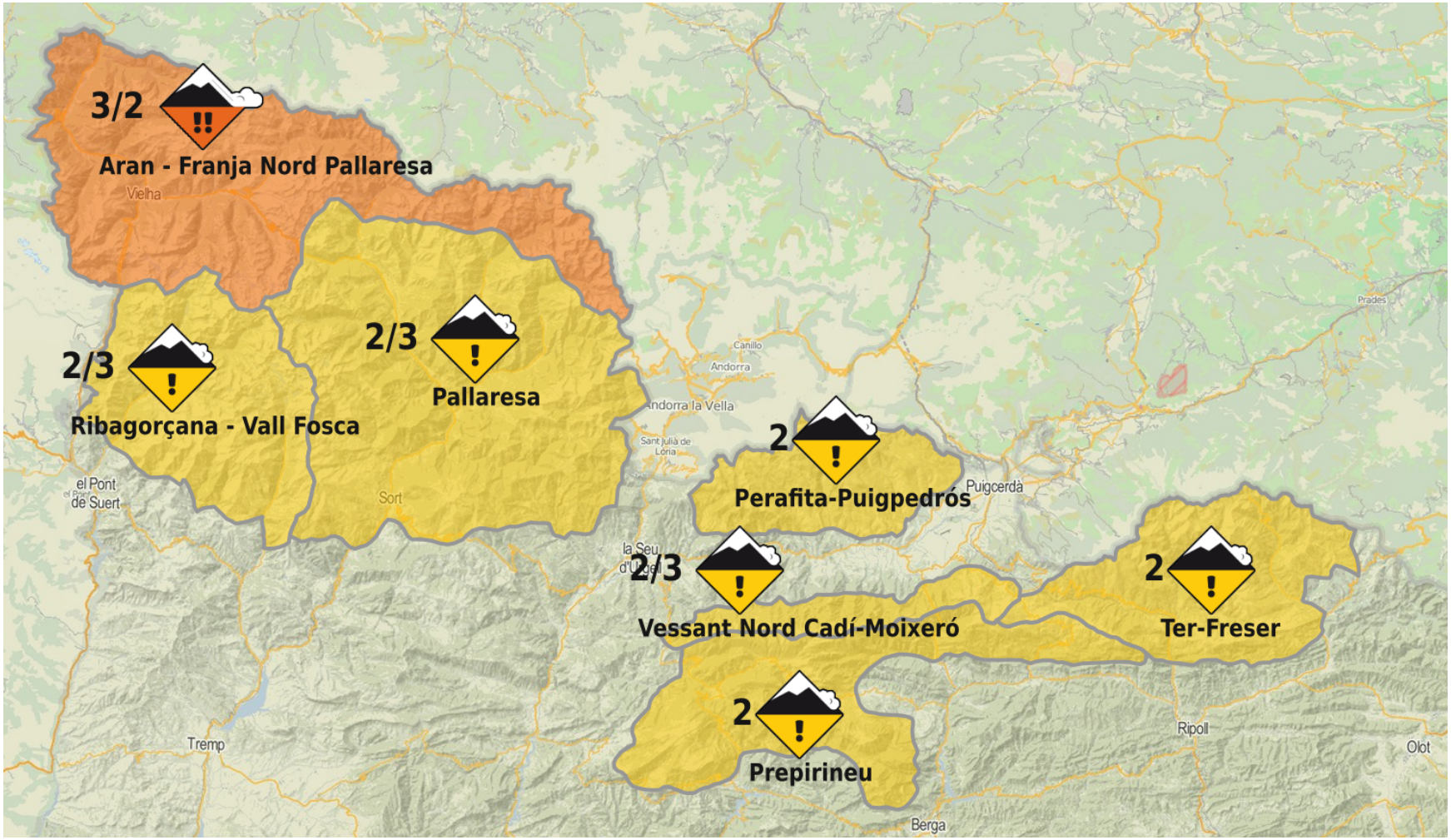

5 MUY FUERTE	4 FUERTE	3 NOTABLE	2 LIMITADO	1 DÉBIL

ICGC Institut Cartogràfic i Geològic de Catalunya

Servei Meteorològic de Catalunya meteo.cat

Boletín de peligro de aludes Aran - Franja Nord Pallaresa Del 11/02/2026 al 12/02/2026

(Válido fuera pistas de esquí y zonas no controladas)

NOTABLE (3), por encima del límite del bosque. LIMITADO (2), en el resto.

Situación primaria

Nieve venteada

Distribución

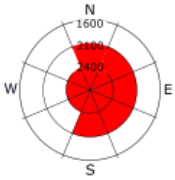

Tamaño

Origen

Tendencia

Situación secundaria

Nieve húmeda

Distribución

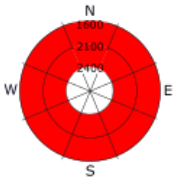

Tamaño

Origen

Tendencia

Estado del manto nivoso

La actividad de aludes ha sido numerosa en las últimas horas, con la caída natural de aludes de nieve húmeda y deslizamientos, de tamaño medio y grande. El patrón de nieve húmeda se restringirá por la tarde y noche del miércoles, dejando paso a un problema por placa de viento y nieve seca, con el descenso térmico previsto para el jueves. Con los chubascos y el viento fuerte del noroeste previsto se formarán nuevas placas de viento. Estas placas las encontraremos por encima del límite del bosque, bajo collados y cordales, en cualquier orientación, preferentemente, en Este. Podrán romperse fácilmente con el paso de un montañero y generar aludes de hasta tamaño medio, con capacidad de enterrar a una persona. Los aludes húmedos caerán, sobre todo, en pendientes fuertemente inclinadas como canales, pasillos o cubetas. No se descarta algún deslizamiento basal que, localmente, podrá llegar a ser de gran tamaño.

Distribución del manto nivoso

Hay nieve en el suelo a 1.300 m. El manto es esquiable por encima de unos 1.400 m. Los espesores a unos 2.200 m rondan los 110-140 cm en el norte de Arán y 140-190 cm en la Franja Nord Pallaresa y en el sur de Aran, y son superiores a los normales por estas fechas.

Tendencia para las próximas 48-72h

El fuerte viento del NW y las nuevas nevadas previstas mantendrán muy reactivas las placas. Peligro EN LEVE ASCENSO.

El próximo boletín será emitido el día 2026-02-12

5 MUY FUERTE	4 FUERTE	3 NOTABLE	2 LIMITADO	1 DÉBIL

EAWS EUROPEAN AVALANCHE WARNING SERVICES

ICGC Institut Cartogràfic i Geològic de Catalunya

Servei Meteorològic de Catalunya meteo.cat

Boletín de peligro de aludes Ribagorçana - Vall Fosca Del 11/02/2026 al 12/02/2026

(Válido fuera pistas de esquí y zonas no controladas)

LIMITADO (2), por debajo de 2.500 m. NOTABLE (3), por encima.

Situación primaria

Nieve venteada

Distribución

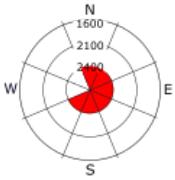

Tamaño

Origen

Tendencia

Situación secundaria

Nieve húmeda

Distribución

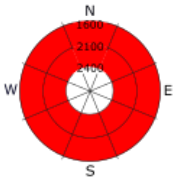

Tamaño

Origen

Tendencia

Estado del manto nivoso

Se ha observado la caída natural de aludes de nieve húmeda, después del último episodio de lluvia en cota alta. El manto aparece con costras internas y grano fino, con una nieve densa debido a su humedecimiento. El patrón de nieve húmeda se restringirá por la tarde y noche del miércoles, dejando paso a un problema por placa de viento y nieve más seca, con el descenso térmico previsto para el jueves. Con los chubascos y el viento fuerte del noroeste previsto se formarán nuevas placas de viento. Estas placas las encontraremos por encima de los 2.500 m y al romperse al paso de un montañero podrán generar aludes de pequeño tamaño, aunque, localmente, podrá caer alguno de tamaño medio (con capacidad de enterrar a una persona). Las placas se formarán, en especial en vertiente E y SE, bajo collados y cordales.

Distribución del manto nivoso

Hay nieve en el suelo a 1.500 m. El manto es esquiable por encima de unos 1500-1600 m. Los grosores alcanzan los 130-160 cm. Estos valores son muy superiores a los normales en la época.

Tendencia para las próximas 48-72h

El fuerte viento del NW y las nuevas nevadas previstas mantendrán muy reactivas las placas. Peligro EN ASCENSO.

El próximo boletín será emitido el día 2026-02-12

5 MUY FUERTE	4 FUERTE	3 NOTABLE	2 LIMITADO	1 DÉBIL

EAWS EUROPEAN AVALANCHE WARNING SERVICES

ICGC Institut Cartogràfic i Geològic de Catalunya

Servei Meteorològic de Catalunya

Boletín de peligro de aludes Pallaresa
Del 11/02/2026 al 12/02/2026

(Válido fuera pistas de esquí y zonas no controladas)

LIMITADO (2), por encima de 2.500 m.
MARCADO (3), por encima.

Situación primaria

Nieve venteada

Distribución

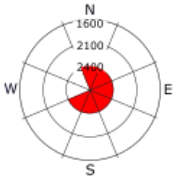

Tamaño

Origen

Tendencia

Situación secundaria

Nieve húmeda

Distribución

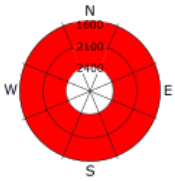

Tamaño

Origen

Tendencia

Estado del manto nivoso

Se ha observado la caída natural de aludes de nieve húmeda, después del último episodio de lluvia en cota alta. El manto aparece con costras internas y grano fino, con una nieve densa debido a su humedecimiento. El patrón de nieve húmeda se restringirá por la tarde y noche del miércoles, dejando paso a un problema por placa de viento y nieve más seca, con el descenso térmico previsto para el jueves. Con los chubascos y el viento fuerte del noroeste previsto se formarán nuevas placas de viento. Estas placas las encontraremos por encima de los 2.500 m y al romperse al paso de un montañero podrán generar aludes de pequeño tamaño, aunque, localmente, podrá caer alguno de tamaño medio (con capacidad de enterrar a una persona). Las placas se formarán, en especial en vertiente E y SE, bajo collados y cordales.

Distribución del manto nivoso

Hay nieve desde los 1600 m. Los espesores en cotas altas y medias superan los 140-150 cm. Estos valores son superiores a los normales para la época.

Tendencia para las próximas 48-72h

El fuerte viento del NW y las nuevas nevadas previstas mantendrán muy reactivas las placas. Peligro EN ASCENSO.

El próximo boletín será emitido el día 2026-02-12

5 MUY FUERTE	4 FUERTE	3 NOTABLE	2 LIMITADO	1 DÉBIL

EAWS EUROPEAN AVALANCHE WARNING SERVICES

ICGC Institut Cartogràfic i Geològic de Catalunya

Servei Meteorològic de Catalunya

Boletín de peligro de aludes Perafita-Puigpedrós Del 11/02/2026 al 12/02/2026

(Válido fuera pistas de esquí y zonas no controladas)

LIMITADO (2).

Situación primaria

Nieve venteada

Distribución

Tamaño

Origen

Tendencia

Situación secundaria

Nieve húmeda

Distribución

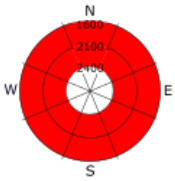

Tamaño

Origen

Tendencia

Estado del manto nivoso

El manto aparece con una costra superficial de lluvia y por debajo encontramos formas húmedas, grano fino y más costras. Los problemas por nieve húmeda se restringirán por la tarde y noche del miércoles, dejando paso a un problema por placa de viento y nieve más seca, con los chubascos y el descenso térmico previsto para el jueves. Con la nevada y el fuerte viento del noroeste previsto se formarán nuevas placas de viento. Estas placas las encontraremos por encima de los 2.500 my al romperse al paso de un montañero podrán generar aludes de pequeño tamaño, aunque, localmente, podrá caer alguno de tamaño medio (con capacidad de enterrar a una persona). Las placas se formarán, en especial en vertiente E y SE, bajo collados y cordales.

Distribución del manto nivoso

Hay nieve en el suelo por encima de 1.400-1500 m. Sin embargo, el manto es esquiable por encima de 1.500-1.600 m. Los grosores alcanzan los 130-150 cm a 2.200 m. Son grosores muy por encima de los habituales por la época.

Tendencia para las próximas 48-72h

El fuerte viento del NW y las nuevas nevadas previstas mantendrán muy reactivas las placas. Peligro EN ASCENSO.

El próximo boletín será emitido el día 2026-02-12

5 MUY FUERTE	4 FUERTE	3 NOTABLE	2 LIMITADO	1 DÉBIL

EAWS EUROPEAN AVALANCHE WARNING SERVICES

ICGC Institut Cartogràfic i Geològic de Catalunya

Servei Meteorològic de Catalunya

Boletín de peligro de aludes Vessant Nord Cadí-Moixeró Del 11/02/2026 al 12/02/2026

(Válido fuera pistas de esquí y zonas no controladas)

LIMITADO (2), en el Moixeró. NOTABLE (3), en la parte superior de las Canales del Cadí.

Situación primaria

Nieve húmeda

Distribución

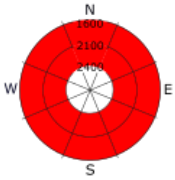

Tamaño

Origen

Tendencia

Estado del manto nivoso

En el Cadí se han observado varios aludes de nieve húmeda, especialmente en los canales, con tamaños medios e, incluso, alguno grande. En la superficie del manto encontramos una costra de lluvia, dura, y por debajo aparecen formas húmedas, grano fino y formas mixtas, intercaladas con más costras. El patrón de nieve húmeda se restringirá por la tarde y noche del miércoles, dejando paso a un problema por placa de viento y nieve más seca, con el descenso térmico previsto para el jueves. Sin embargo, en pendientes fuertemente inclinadas, como en lo alto de las Canales del Cadí podremos encontrar todavía alguna placa húmeda que podrá caer al paso de un esquiador y alcanzar tamaño medio, suficiente para enterrar a una persona. Por lo general, las encontraremos en vertientes Este y Norte. De forma local, alguna placa desatada podría implicar más manto y generar un alud de gran tamaño (con capacidad de enterrar a un grupo de personas).

Distribución del manto nivoso

Hay nieve desde 1.300 m en Norte y desde 1.400 a 1500 m en Sur, esquiable por encima de unos 1.500 m. Los grosores están alrededor de 150-170 cm a 2.200 m. Estos valores son muy excedentarios para la época del año.

Tendencia para las próximas 48-72h

Con el descenso térmico disminuye el problema de nieve húmeda. Peligro ESTACIONARIO.

El próximo boletín será emitido el día 2026-02-12

5 MUY FUERTE	4 FUERTE	3 NOTABLE	2 LIMITADO	1 DÉBIL

EAWS EUROPEAN AVALANCHE WARNING SERVICES

ICGC Institut Cartogràfic i Geològic de Catalunya

meteo.cat Servei Meteorològic de Catalunya

Boletín de peligro de aludes Prepirineu
Del 11/02/2026 al 12/02/2026

(Válido fuera pistas de esquí y zonas no controladas)

LIMITADO (2).

Situación primaria

Nieve húmeda

Distribución

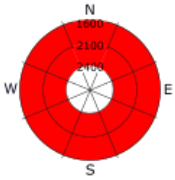

Tamaño

Origen

Tendencia

Estado del manto nivoso

Con el humedecimiento del manto, después del último frente cálido y la lluvia en cota alta, el problema predominante será el de la nieve húmeda. Los aludes caerán de forma natural y llegarán hasta tamaño medio (con capacidad de enterrar a una persona). Se darán, sobre todo, en pendientes fuertemente inclinadas. En cota alta, cerca de las cimas, encontraremos placas de viento, bajo collados y cordales, que pueden caer al paso de un montañero y alcanzar tamaño suficiente para enterrar a una persona. Por lo general, se encuentran en laderas Este y Sureste.

Distribución del manto nivoso

Hay nieve desde 1400-1500 m. El manto es esquiable a partir de 1600 m. Los grosores están alrededor de 110-130 cm a unos 2.200 m y son superiores a los habituales.

Tendencia para las próximas 48-72h

Con el descenso térmico disminuye el problema de nieve húmeda. Peligro ESTACIONARIO.

El próximo boletín será emitido el día 2026-02-12

5 MUY FUERTE	4 FUERTE	3 NOTABLE	2 LIMITADO	1 DÉBIL

EAWS EUROPEAN AVALANCHE WARNING SERVICES

ICGC Institut Cartogràfic i Geològic de Catalunya

Servei Meteorològic de Catalunya meteo.cat

Boletín de peligro de aludes Ter-Freser
Del 11/02/2026 al 12/02/2026

(Válido fuera pistas de esquí y zonas no controladas)

LIMITADO (2).

Situación primaria

Nieve venteada

Distribución

Tamaño

Origen

Tendencia

Situación secundaria

Nieve húmeda

Distribución

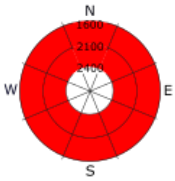

Tamaño

Origen

Tendencia

Estado del manto nivoso

En el manto encontramos formas húmedas, grano fino y costras internas, duras. Se ha observado actividad avalanchosa, con el humedecimiento asociado a la lluvia hasta cota alta. Los problemas por nieve húmeda se restringirán por la tarde y noche del miércoles, dejando paso a un problema por placa de viento y nieve más seca, con los chubascos y el descenso térmico previsto para el jueves. Con la leve nevada y el viento fuerte del noroeste previsto, el jueves se formarán nuevas placas de viento, pequeñas. Estas placas las encontraremos por encima de los 2.500 m y al romperse al paso de un montañero podrán generar aludes de pequeño tamaño, aunque, localmente, podrá caer alguno de tamaño medio (con capacidad de enterrar a una persona). Las placas se formarán, en especial en vertiente E y SE, bajo collados y cordales.

Distribución del manto nivoso

El manto nivoso presenta grosores muy excedentarios para la época del año. En lugares no afectados por el viento, los espesores oscilan entre 100-140 cm a unos 2.000 m, siendo esquiable a partir de unos 1.500 m.

Tendencia para las próximas 48-72h

Con el fuerte viento del NW y las nuevas nevadas previstas seguirá el problema por placa de viento. Peligro EN ASCENSO.

El próximo boletín será emitido el día 2026-02-12

5 MUY FUERTE	4 FUERTE	3 NOTABLE	2 LIMITADO	1 DÉBIL

EAWS EUROPEAN AVALANCHE WARNING SERVICES