BUTLLETÍ DEL PERILL D'ALLAUS DEL PRINCIPAT D'ANDORRA

Servei meteorològic nacional
Principat d'Andorra

Elaborat el 11/02/2026 16:00
Propera actualització 12/02/2026 a les 16h

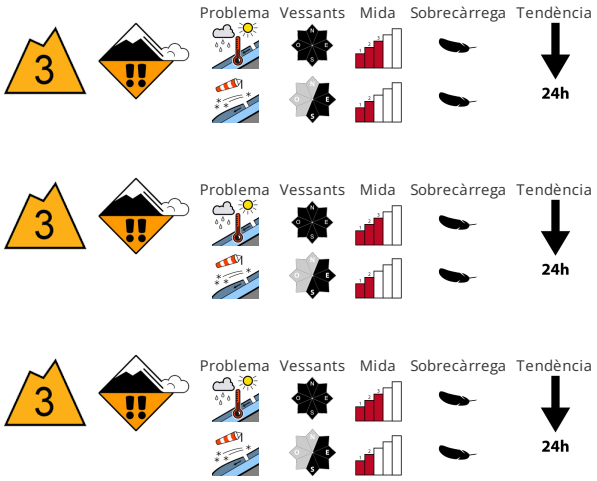

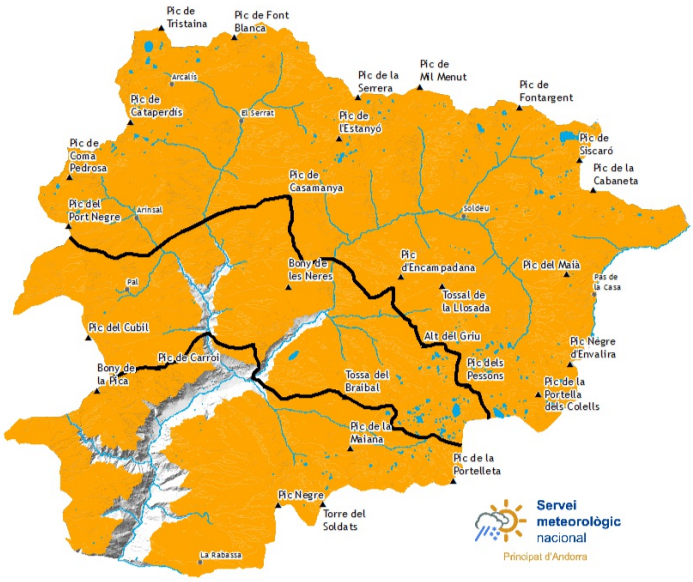

ESTABILITAT DEL MANTELL NIVAL

Amb les precipitacions, augment provisional del perill d'allaus de neu humida. Aquestes poden implicar les capes més profundes del mantell de neu i arribar localment a mida gran. El vent amb ratxes fortes transportarà intensament la neu recent. Especialment prop dels cims a partir de la segona meitat de la nit les plaques de vent, fins ara petites, augmentaran de mida. Els indrets perillosos són nombrosos i difícils de reconèixer amb mala visibilitat. Les excursions de muntanya fora de les pistes controlades són desaconsellables.

QUALITAT DE LA NEU

Durant la nit caurà pluja fins a cotes altes. La pluja causarà en una àrea extensa una clara humidificació del mantell de neu en totes les orientacions. A partir de la matinada caurà una mica de neu especialment als al nord. La superfície del mantell de neu es regelarà per formar una crosta portant. El vent serà, prop dels cims, fort. Amb la neu recent i el fort vent les plaques de vent augmentaran de mida.

GRUIXOS DEL MANTELL NIVAL FORA DE PISTA

Zona nord		Gruix neu		
Mantell Nival		1500m	2000m	2500m
N	1300 m	50 cm	150 cm	200 cm
S	1300 m	30 cm	100 cm	130 cm

Zona centre		Gruix neu		
Mantell Nival		1500m	2000m	2500m
N	1300 m	50 cm	150 cm	200 cm
S	1300 m	30 cm	100 cm	130 cm

Zona sud		Gruix neu		
Mantell Nival		1500m	2000m	2500m
N	1300 m	50 cm	100 cm	100 cm
S	1300 m	30 cm	70 cm	70 cm

Govern d'Andorra

EAWS
EUROPEAN AVALANCHE WARNING SERVICES

Aquest butlletí ha estat elaborat seguint les normes i recomanacions de l'**European Avalanche Warning Services**, del qual el **Servei meteorològic Nacional** n'és membre

BUTLLETÍ DEL PERILL D'ALLAUS DEL PRINCIPAT D'ANDORRA

Servei meteorològic nacional
Principat d'Andorra

Informació detallada per espais naturals protegits

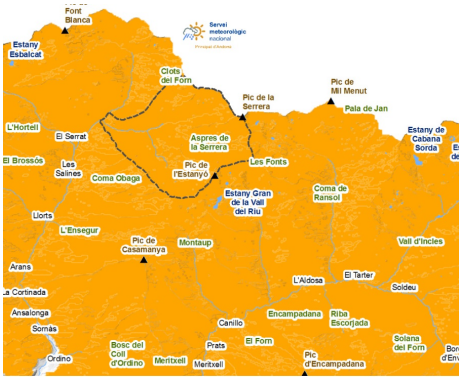

SORTENY

La pluja fins a cotes altes humidificarà les capes febles de la part superficial del mantell, acumulades en les febles nevades dels darrers dies. La previsió d´allaus humides naturals ens han de fer extremar les precaucions. De matinada, amb el descens de la cota de neu i l´augment del vent es formaran noves plaques als vessants amb component est. La mala visibilitat i el fort vent fan desaconsellar l´accés a la muntanya.

COMAPEDROSA

Les noves pluges encara poden provocar que baixin allaus humides per les canals que creuen els camins. A més, encara que ja hi hagi hagut allaus durant l´hivern que hagin purgat alguns vessants, no podem descartar que tornin a baixar allaus grans. Les ràfegues de vent generaran torb i fan desaconsellable les excursions fora de les zones controlades.

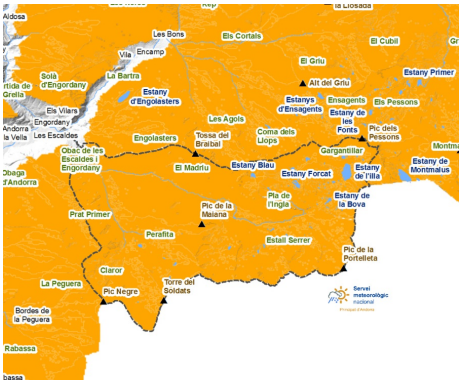

MADRIU-PERAFITA-CLAROR

La pluja causarà una fosa del mantell a les cotes més baixes, dificultant els accessos a la Vall. La neu molla i tova no suporta el pes d´un excursionista. El vent crearà noves acumulacions als vessants est.

Govern d'Andorra

EAWS
EUROPEAN AVALANCHE WARNING SERVICES

Aquest butlletí ha estat elaborat seguint les normes i recomanacions de l'**European Avalanche Warning Services**, del qual el **Servei meteorològic Nacional** n'és membre

BUTLLETÍ DEL PERILL D'ALLAUS DEL PRINCIPAT D'ANDORRA

Servei meteorològic nacional
Principat d'Andorra

Gruixos de neu nova dels darrers dies (de les últimes 24h mesurat a les 06:00h UTC)

	07/02/2026	08/02/2026	09/02/2026	10/02/2026
FEDA (Central)	0 cm	0 cm	0 cm	0 cm
Engolasters - FEDA	0 cm	0 cm	0 cm	0 cm
Bony de les Neres	0 cm	0 cm	11 cm	0 cm
Sorteny	3 cm	2 cm	22 cm	0 cm
Les Fonts d'Arinsal	0 cm	10 cm	15 cm	12 cm
Perafita	0 cm	0 cm	8 cm	0 cm
Tossa Espiolets	0 cm	4 cm	5 cm	0 cm
Grau Roig - FEDA	0 cm	0 cm	13 cm	0 cm
Fontverd	0 cm	0 cm	7 cm	0 cm
Ransol - FEDA	1 cm	0 cm	4 cm	0 cm
Setúria	4 cm	6 cm	12 cm	0 cm
Caborreu	0 cm	0 cm	6 cm	0 cm
Coll Pa	2 cm	3 cm	13 cm	0 cm
Envalira Antenes	0 cm	4 cm	18 cm	0 cm
Vall del Riu FEDA	9 cm	0 cm	7 cm	7 cm