BUTLLETÍ DEL PERILL D'ALLAUS DEL PRINCIPAT D'ANDORRA

Elaborado el 11/02/2026 16:00
Proxima actualización 12/02/2026 a las 16h

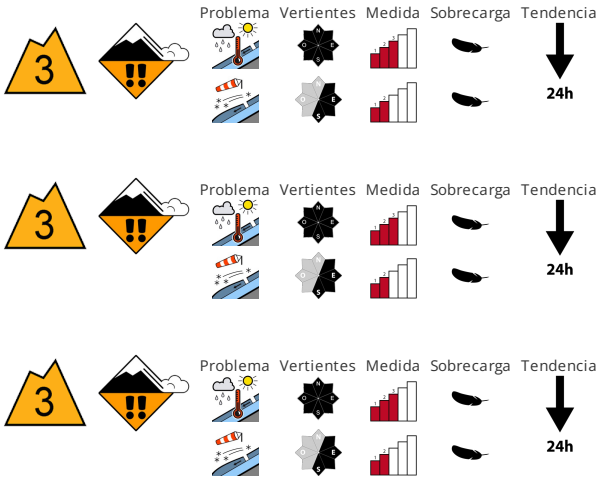

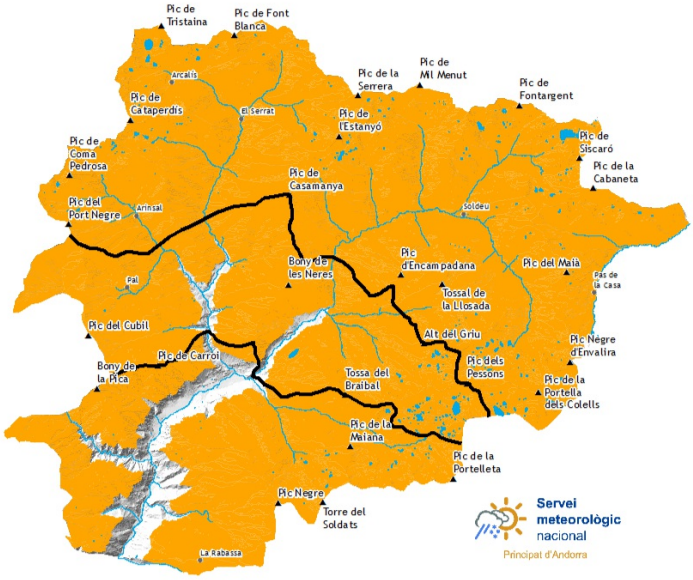

CALIDAD DE LA NIEVE

Con las precipitaciones, temporal aumento del peligro de aludes de nieve húmeda. Estos pueden implicar las capas más profundas del manto de nieve y llegar localmente a tamaño grande. El viento con rachas fuertes transportará intensamente la nieve reciente. Especialmente cerca de las cumbres a partir de la segunda mitad de la noche las placas de viento, hasta ahora pequeñas, aumentarán de tamaño. Los lugares peligrosos son numerosos y resultan difíciles de reconocer con poca visibilidad. Las excursiones de montaña fuera de las pistas controladas están desaconsejadas.

ESTABILIDAD DEL MANTO NIVOSO

Durante la noche caerá lluvia hasta en cotas altas. La lluvia causará en un área extensa una clara humidificación del manto de nieve en todas las orientaciones. A partir de la madrugada caerá un poco de nieve especialmente en los norte. La superficie del manto de nieve se volverá a helar para formar una costra portante. El viento soplará, cerca de las cumbres, fuerte. Con la nieve reciente y el fuerte viento las placas de viento aumentarán de tamaño.

ESPESORES DEL MANTO NIVOSO FUERA DE PISTA

Zona norte		Espesor nieve		
Manto Nival		1500m	2000m	2500m
N	1300 m	50 cm	150 cm	200 cm
S	1300 m	30 cm	100 cm	130 cm

zona centro		Espesor nieve		
Manto Nival		1500m	2000m	2500m
N	1300 m	50 cm	150 cm	200 cm
S	1300 m	30 cm	100 cm	130 cm

Zona sur		Espesor nieve		
Manto Nival		1500m	2000m	2500m
N	1300 m	50 cm	100 cm	100 cm
S	1300 m	30 cm	70 cm	70 cm

Govern d'Andorra

EAWS EUROPEAN AVALANCHE WARNING SERVICES

Aquest butlletí ha estat elaborat seguint les normes i recomanacions de l'**European Avalanche Warning Services**, del qual el **Servei meteorològic Nacional** n'és membre

BUTLLETÍ DEL PERILL D'ALLAUS DEL PRINCIPAT D'ANDORRA

Servei meteorològic nacional
Principat d'Andorra

Información detallada por espacios naturales protegidos

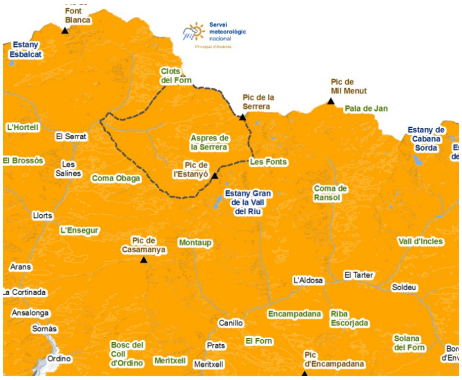

SORTENY

Las lluvias que llegarán a gran altura humedecerán las capas débiles de la parte superficial del manto, acumuladas en las nieves débiles de los últimos días. La previsión de aludes naturales húmedos debería hacernos extremar las precauciones. Por la mañana, con el descenso de la cota de nieve y el aumento del viento, se formarán nuevas placas en las laderas con componente este. La mala visibilidad y el fuerte viento desaconsejan el acceso a la montaña. , , , , , , ,

COMAPEDROSA

Las nuevas lluvias aún pueden provocar la caída de avalanchas de agua por los canales que cruzan las carreteras. Además, aunque ya se han producido durante el invierno aludes que han despejado algunas laderas, no podemos descartar que vuelvan a caer grandes aludes. Las rachas de viento generarán turbidez y desaconsejarán las excursiones fuera de las zonas controladas. , , , , ,

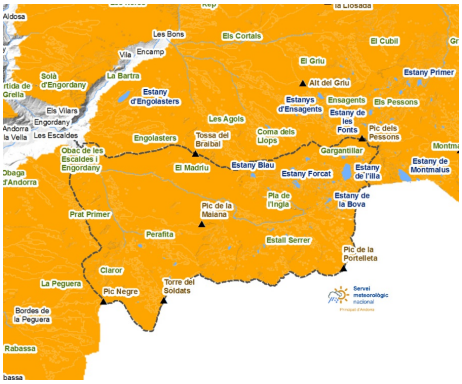

MADRIU-PERAFITA-CLAROR

Las lluvias provocarán un derretimiento del manto en las cotas más bajas, dificultando el acceso al Valle. La nieve blanda y blanda no puede soportar el peso de un excursionista. El viento creará nuevas acumulaciones en las vertientes orientales. , , , , ,

Govern d'Andorra

EAWS
EUROPEAN AVALANCHE WARNING SERVICES

Aquest butlletí ha estat elaborat seguint les normes i recomanacions de l'**European Avalanche Warning Services**, del qual el **Servei meteorològic Nacional** n'és membre

BUTLLETÍ DEL PERILL D'ALLAUS DEL PRINCIPAT D'ANDORRA

Servei meteorològic nacional
Principat d'Andorra

Espesores de nieve nueva de los últimos días (de las ultimas 24h mesurado a las 06:00h UTC)

	07/02/2026	08/02/2026	09/02/2026	10/02/2026
FEDA (Central)	0 cm	0 cm	0 cm	0 cm
Engolasters - FEDA	0 cm	0 cm	0 cm	0 cm
Bony de les Neres	0 cm	0 cm	11 cm	0 cm
Sorteny	3 cm	2 cm	22 cm	0 cm
Les Fonts d'Arinsal	0 cm	10 cm	15 cm	12 cm
Perafita	0 cm	0 cm	8 cm	0 cm
Tossa Espiolets	0 cm	4 cm	5 cm	0 cm
Grau Roig - FEDA	0 cm	0 cm	13 cm	0 cm
Fontverd	0 cm	0 cm	7 cm	0 cm
Ransol - FEDA	1 cm	0 cm	4 cm	0 cm
Setúria	4 cm	6 cm	12 cm	0 cm
Caborreu	0 cm	0 cm	6 cm	0 cm
Coll Pa	2 cm	3 cm	13 cm	0 cm
Envalira Antenes	0 cm	4 cm	18 cm	0 cm
Vall del Riu FEDA	9 cm	0 cm	7 cm	7 cm