# BUTLLETÍ DEL PERILL D'ALLAUS DEL PRINCIPAT D'ANDORRA

Préparé le 11/02/2026 16:00
Prochaine mise à jour le 12/02/2026 à 16h

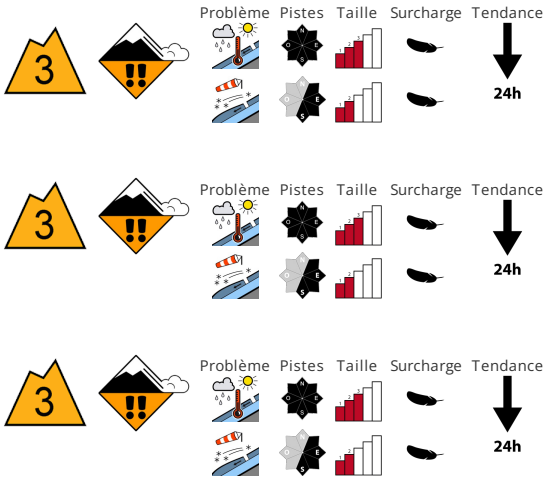


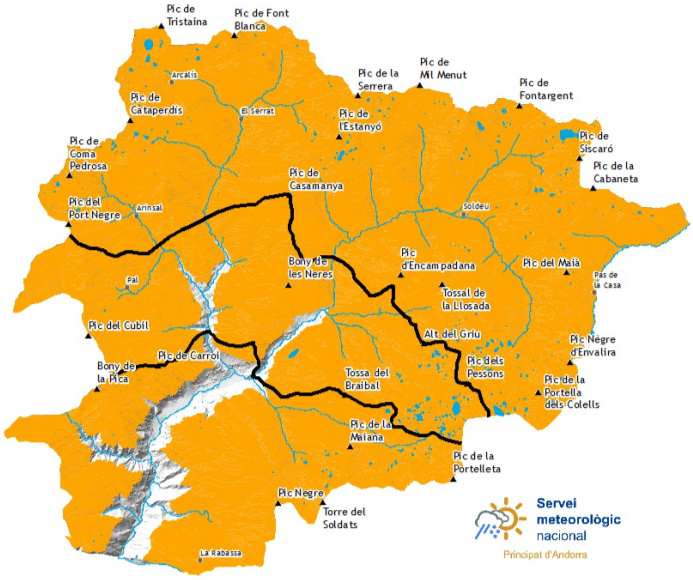


## STABILITÉ DU MANTEAU NEIGEUX

Augmentation temporaire du danger d'avalanches humides avec les précipitations. Explication: celles-ci ne peut signifier que celles-ci avalanches peuvent se déclencher dans les couches profondes et parfois atteindre une grande taille.. Le vent parfois fort transporte intensivement la neige fraîche.. À partir de la seconde moitié de nuit les accumulations de neige soufflée auparavant petites se développent spécialement à proximité des sommets. Les endroits dangereux sont nombreux et à peine identifiables par mauvaise visibilité.. Il est déconseillé d'effectuer des randonnées en dehors des pistes sécurisées.

## QUALITÈ DE LA NEIGE

Pendant la nuit il tombera de la pluie jusqu'à haute altitude. La pluie entraîne à toutes les expositions généralement une humidification nette du manteau neigeux. À partir de la matinée il tombera un peu de neige spécialement au nord. La surface de la neige regèle et devient porteuse. Le vent souffle à proximité des sommets fortement. Les accumulations de neige soufflée se développent avec la neige fraîche et le vent fort.

## EPAISSEUR DE NEIGE HORS PISTE

| Zone nord | | Epaisseur de neige | | |
|---|---|---|---|---|
| **Nival manteau** | | 1500m | 2000m | 2500m |
| N | 1300 m | 50 cm | 150 cm | 200 cm |
| S | 1300 m | 30 cm | 100 cm | 130 cm |

| Zone centre | | Epaisseur de neige | | |
|---|---|---|---|---|
| **Nival manteau** | | 1500m | 2000m | 2500m |
| N | 1300 m | 50 cm | 150 cm | 200 cm |
| S | 1300 m | 30 cm | 100 cm | 130 cm |

| Zone sud | | Epaisseur de neige | | |
|---|---|---|---|---|
| **Nival manteau** | | 1500m | 2000m | 2500m |
| N | 1300 m | 50 cm | 100 cm | 100 cm |
| S | 1300 m | 30 cm | 70 cm | 70 cm |

Govern d'Andorra

Aquest butlletí ha estat elaborat seguint les normes i recomanacions de l'**European Avalanche Warning Services**, del qual el **Servei meteorològic Nacional** n'és membre

# BUTLLETÍ DEL PERILL D'ALLAUS DEL PRINCIPAT D'ANDORRA

Servei meteorològic nacional
Principat d'Andorra

## Des informations détaillées par espace naturel protégé

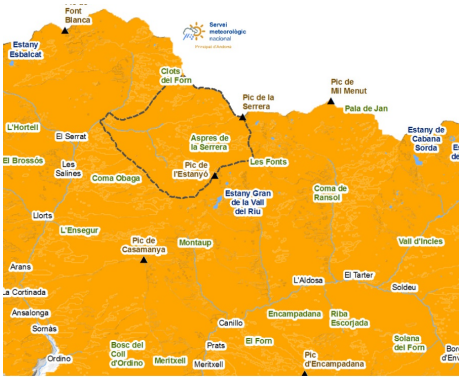


### SORTENY

La pluie jusqu'aux hautes altitudes humidifiera les couches fragiles de la partie superficielle du manteau, accumulées dans les faibles neiges des derniers jours. La prévision d'avalanches mouillées naturelles devrait nous inciter à prendre des précautions extrêmes. Le matin, avec la diminution du niveau de neige et l'augmentation du vent, de nouvelles plaques se formeront sur les pentes avec une composante orientale. La mauvaise visibilité et le vent fort rendent l'accès à la montagne déconseillé. , , , , , , ,

### COMAPEDROSA

Les nouvelles pluies pourraient encore provoquer des avalanches mouillées dans les canaux qui traversent les routes. De plus, même s'il y a déjà eu des avalanches au cours de l'hiver qui ont dégagé certaines pentes, on ne peut pas exclure que de grosses avalanches redescendent. Les rafales de vent généreront de la turbidité et rendront déconseillées les sorties en dehors des zones contrôlées. , , , , ,

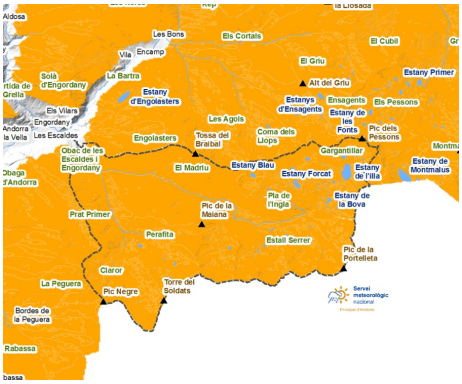


### MADRIU-PERAFITA-CLAROR

La pluie provoquera une fonte du manteau aux niveaux les plus bas, rendant l'accès à la Vallée difficile. La neige molle et molle ne peut supporter le poids d'un randonneur. Le vent créera de nouvelles accumulations sur les versants Est. , , , , ,

Govern d'Andorra

EAWS
EUROPEAN AVALANCHE WARNING SERVICES

Aquest butlletí ha estat elaborat seguint les normes i recomanacions de l'**European Avalanche Warning Services**, del qual el **Servei meteorològic Nacional** n'és membre

# BUTLLETÍ DEL PERILL D'ALLAUS DEL PRINCIPAT D'ANDORRA

Servei meteorològic nacional
Principat d'Andorra

## Couche de neige fraiche des derniers jours (De 24 h mesurée à 06:00 h UTC)

| | 07/02/2026 | 08/02/2026 | 09/02/2026 | 10/02/2026 |
|---|---|---|---|---|
| **FEDA (Central)** | 0 cm | 0 cm | 0 cm | 0 cm |
| **Engolasters - FEDA** | 0 cm | 0 cm | 0 cm | 0 cm |
| **Bony de les Neres** | 0 cm | 0 cm | 11 cm | 0 cm |
| **Sorteny** | 3 cm | 2 cm | 22 cm | 0 cm |
| **Les Fonts d'Arinsal** | 0 cm | 10 cm | 15 cm | 12 cm |
| **Perafita** | 0 cm | 0 cm | 8 cm | 0 cm |
| **Tossa Espiolets** | 0 cm | 4 cm | 5 cm | 0 cm |
| **Grau Roig - FEDA** | 0 cm | 0 cm | 13 cm | 0 cm |
| **Fontverd** | 0 cm | 0 cm | 7 cm | 0 cm |
| **Ransol - FEDA** | 1 cm | 0 cm | 4 cm | 0 cm |
| **Setúria** | 4 cm | 6 cm | 12 cm | 0 cm |
| **Caborreu** | 0 cm | 0 cm | 6 cm | 0 cm |
| **Coll Pa** | 2 cm | 3 cm | 13 cm | 0 cm |
| **Envalira Antenes** | 0 cm | 4 cm | 18 cm | 0 cm |
| **Vall del Riu FEDA** | 9 cm | 0 cm | 7 cm | 7 cm |