MINISTERO DELLA DIFESA

meteomont
Servizio Nazionale di previsione neve e valanghe

EAWS EUROPEAN AVALANCHE WARNING SERVICES

CARABINIERI

AERONAUTICA MILITARE SERVIZIO METEOROLOGICO

ALPI LIGURI SUD

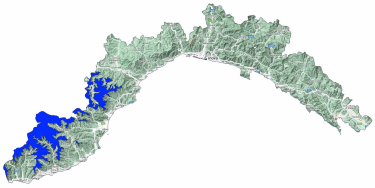

Bollettino Valanghe N. 294/2026 del 11/02/2026 ore 14.00
Validità 48 ore prossima emissione 12/02/2026

A cura del Servizio METEOMONT dell'ARMA dei CARABINIERI
In collaborazione con Servizio Meteorologico dell'Aeronautica militare

SITUAZIONE alle 14:00 del 11/02/2026

SITUAZIONE TIPO: situazione primaverile.

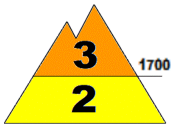



SITUAZIONE TIPO: situazione primaverile.

Quota neve (mslm)	Nord	Sud
	700 - 1500	1200 - 1600

Altezza Neve (cm)	Neve al suolo	Neve Fresca	Quota (mslm)
	140	0	1900
	113	0	1400

VALANGHE OSSERVATE: Valanghe di piccole dimensioni, Valanghe a lastroni di fondo.

PREVISIONI 12/02/2026

GRADO DI PERICOLO: MARCATO 3

SITUAZIONE TIPO: situazione primaverile.

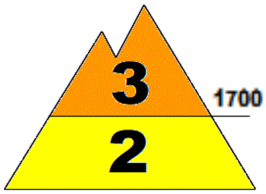

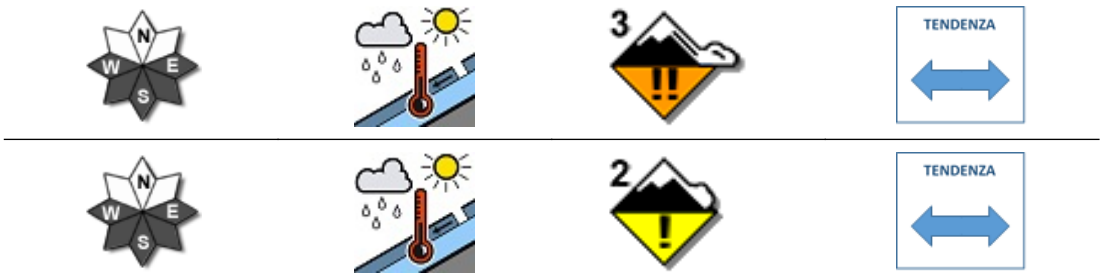

SITUAZIONE TIPO: situazione primaverile.

MANTO NEVOSO: La stabilità del manto nevoso è molto scarsa su alcuni punti (aree) per versanti da est a ovest al di sopra di 1700 mslm, possibili valanghe di dimensioni medie.
La stabilità del manto nevoso è scarsa su alcuni punti (aree) per versanti da est a ovest al di sotto di 1700 mslm, possibili valanghe di dimensioni piccole.

AVVERTENZE

Il rialzo termico diurno richiede un'attenta valutazione temporale dell'escursione che eviti l'attraversamento di pendii ripidi nelle ore più calde della giornata.

SCALA EUROPEA DEL GRADO DI PERICOLO VALANGHE

LEGENDA PROBLEMA

Bollettino realizzato su scala sinottica-regionale (standard EAWS). La sua valutazione non può escludere in alcun modo la necessità di una seria e capace valutazione locale del pericolo (singolo pendio) che può essere anche sensibilmente diverso. Le previsioni meteorologiche sono relative all'orario UTC (per l'Italia +1 in inverno e +2 in estate).

MINISTERO DELLA DIFESA

meteomont
Servizio Nazionale di previsione neve e valanghe

EAWS EUROPEAN AVALANCHE WARNING SERVICES

CARABINIERI

ALPI LIGURI SUD

PREVISIONE METEO

Quota		12/02/2026 h6:00	12/02/2026 h12:00	12/02/2026 h18:00
1000	Venti	04 nodi da N-Ovest	03 nodi da N-Ovest	04 nodi da N-Ovest
	Temperature	+00 °C	+02 °C	+01 °C
	Temp.percepita	-3 °C	0 °C	-1 °C
2000	Venti	16 nodi da N-Ovest	18 nodi da N-Ovest	22 nodi da N-Ovest
	Temperature	+00 °C	-01 °C	-01 °C
	Temp.percepita	-6 °C	-8 °C	-9 °C
3000	Venti	22 nodi da N-Ovest	29 nodi da N-Ovest	32 nodi da N-Ovest
	Temperature	-06 °C	-07 °C	-07 °C
	Temp.percepita	-15 °C	-18 °C	-18 °C
Zero termico		1900-2100 m.	1800-2000 m.	1800-2000 m.
Fenomeno		—	—	—
Stato del cielo				

LEGENDA FENOMENI

— Assenza Fenomeni · Nebbia · Foschia · Pioggia debole · Pioggia moderata · Pioggia forte · Temporali

Nevicata debole · Nevicata moderata · Nevicata forte

STATO DEL CIELO

Sereno · Poco nuvoloso · Nuvoloso · Molto nuvoloso · Coperto

Parametri meteonivometrici registrati presso i campi di rilevamento il 11/02/2026.

Località	Comune	Quota (m.s.l.m.)	Altezza neve (cm)	Neve caduta nelle 24 ore (cm)	Temp. Min (°C)	Temp. Max (°C)	Condizioni del tempo
MONESI *	Triora (IM)	1440	113	0	N.P.	N.P.	Assenza di precipitazioni
MONESI DI TRIORA *	Triora (IM)	1420	113	0	N.P.	N.P.	Assenza di precipitazioni

(*) Rilievi fuori campo

L'INFORMAZIONE E' PREVENZIONE - LEGGI L'ATTUALE GRADO DI PERICOLO VALANGHE!

IL CAPO DEL CENTRO NAZIONALE METEOMONT
(Ten. Col. RFI Emanuela Gini)
FIRMA AUTOGRAFA OMESSA AI SENSI
DELL'ART.3 DEL D.LGS N.39/1993

Bollettino realizzato su scala sinottica-regionale (standard EAWS). La sua valutazione non può escludere in alcun modo la necessità di una seria e capace valutazione locale del pericolo (singolo pendio) che può essere anche sensibilmente diverso. Le previsioni meteorologiche sono relative all'orario UTC (per l'Italia +1 in inverno e +2 in estate).