MINISTERO DELLA DIFESA

meteomont Servizio Nazionale di previsione neve e valanghe

EAWS EUROPEAN AVALANCHE WARNING SERVICES

CARABINIERI

ALPI APUANE - APPENNINO TOSCANO SETTENTRIONALE

Bollettino Valanghe N. 254/2026 del 10/02/2026 ore 14.00
Validità 48 ore prossima emissione 11/02/2026

A cura del Servizio METEOMONT dell'ARMA dei CARABINIERI
In collaborazione con Servizio Meteorologico dell'Aeronautica militare

SITUAZIONE alle 14:00 del 10/02/2026

SITUAZIONE TIPO: pioggia su neve.

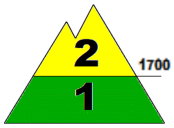



SITUAZIONE TIPO: pioggia su neve.

Quota neve (mslm)	Nord	Sud
	1300	1400

Altezza Neve (cm)	Neve al suolo	Neve Fresca	Quota (mslm)
	184	001	1800
	046	000	1340

VALANGHE OSSERVATE: Nessuna valanga.

PREVISIONI 11/02/2026

GRADO DI PERICOLO: MODERATO 2

SITUAZIONE TIPO: pioggia su neve.

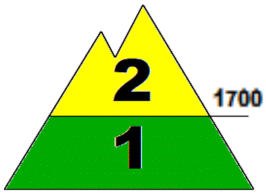



SITUAZIONE TIPO: pioggia su neve.

MANTO NEVOSO: La stabilità del manto nevoso è discreta su molti punti (aree) per tutte le esposizioni al di sopra di 1700 mslm, possibili valanghe di dimensioni medie.
La stabilità del manto nevoso è buona su pochi punti (aree) per versanti settentrionali al di sotto di 1700 mslm, possibili valanghe di dimensioni medie.

AVVERTENZE

Il previsto rialzo termico potrebbe causare il distacco di cornici con conseguente sovraccarico dei pendii sottostanti.

SCALA EUROPEA DEL GRADO DI PERICOLO VALANGHE

LEGENDA PROBLEMA

Bollettino realizzato su scala sinottica-regionale (standard EAWS). La sua valutazione non può escludere in alcun modo la necessità di una seria e capace valutazione locale del pericolo (singolo pendio) che può essere anche sensibilmente diverso. Le previsioni meteorologiche sono relative all'orario UTC (per l'Italia +1 in inverno e +2 in estate).

MINISTERO DELLA DIFESA

meteomont
Servizio Nazionale di previsione neve e valanghe

EAWS EUROPEAN AVALANCHE WARNING SERVICES

CARABINIERI

ALPI APUANE - APPENNINO TOSCANO SETTENTRIONALE

PREVISIONE METEO

Quota		11/02/2026 h6:00	11/02/2026 h12:00	11/02/2026 h18:00
1000	Venti	05 Nodi da S-Ovest	01 Nodi da Ovest	03 nodi da Ovest
	Temperature	+03 °C	+06 °C	+05 °C
	Temp.percepita	0 °C	6 °C	4 °C
2000	Venti	18 Nodi da S-Ovest	09 nodi da Ovest	13 nodi da N-Ovest
	Temperature	+01 °C	+02 °C	+02 °C
	Temp.percepita	-5 °C	-2 °C	-3 °C
3000	Venti	17 Nodi da Ovest	14 nodi da N-Ovest	12 nodi da N-Ovest
	Temperature	-04 °C	-04 °C	-05 °C
	Temp.percepita	-12 °C	-11 °C	-12 °C
Zero termico		2000-2200 m.	2400-2600 m.	2100-2300 m.
Fenomeno			—	—
Stato del cielo				

LEGENDA FENOMENI

Assenza Fenomeni — Nebbia — Foschia — Pioggia debole — Pioggia moderata — Pioggia forte — Temporali

Nevicata debole — Nevicata moderata — Nevicata forte

STATO DEL CIELO

Sereno — Poco nuvoloso — Nuvoloso — Molto nuvoloso — Coperto

Parametri meteonivometrici registrati presso i campi di rilevamento il 10/02/2026.

Località	Comune	Quota (m.s.l.m.)	Altezza neve (cm)	Neve caduta nelle 24 ore (cm)	Temp. Min (°C)	Temp. Max (°C)	Condizioni del tempo
PONTE ALLE LIME	Abetone Cutigliano (PT)	1340	46	0	N.P.	N.P.	Assenza di precipitazioni
ORECCHIELLA	San Romano in Garfagnana (LU)	1240	0	0	+2	+5	Pioggia debole continua
ALPE DI SAN PELLEGRINO	Castiglione di Garfagnana (LU)	1651	51	N.P.	N.P.	N.P.	Nevicata debole intermittente
BOCCA DI MASSA *	Villa Collemandina (LU)	1800	184	1	N.P.	N.P.	Assenza di precipitazioni
RIFUGIO CELLA *	Villa Collemandina (LU)	1692	73	1	N.P.	N.P.	Nevicata debole intermittente
RIFUGIO CELLA *	Villa Collemandina (LU)	1692	73	1	N.P.	N.P.	Nevicata debole intermittente

(*) Rilievi fuori campo

L'INFORMAZIONE E' PREVENZIONE - LEGGI L'ATTUALE GRADO DI PERICOLO VALANGHE!

IL CAPO DEL CENTRO NAZIONALE METEOMONT
(Ten. Col. RFI Emanuela Gini)
FIRMA AUTOGRAFA OMESSA AI SENSI
DELL'ART.3 DEL D.LGS N.39/1993