MINISTERO DELLA DIFESA

meteomont Servizio Nazionale di previsione neve e valanghe

EAWS EUROPEAN AVALANCHE WARNING SERVICES

CARABINIERI

GRAN SASSO EST - LAGA EST

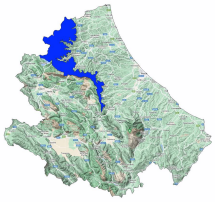

Bollettino Valanghe N. 331/2026 del 11/02/2026 ore 14.00
Validità 48 ore prossima emissione 12/02/2026

A cura del Servizio METEOMONT dell'ARMA dei CARABINIERI
In collaborazione con Servizio Meteorologico dell'Aeronautica militare

SITUAZIONE alle 14:00 del 11/02/2026

SITUAZIONE TIPO: neve da slittamento.

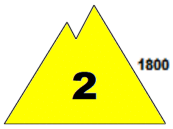



SITUAZIONE TIPO: situazione primaverile.

Quota neve (mslm)	Nord	Sud
	1400 - 1500	1600 - 1800

Altezza Neve (cm)	Neve al suolo	Neve Fresca	Quota (mslm)
	010	000	1400
	000	000	1016

VALANGHE OSSERVATE: Valanghe di piccole dimensioni, Valanghe di slittamento.

PREVISIONI 12/02/2026

GRADO DI PERICOLO: MODERATO 2

SITUAZIONE TIPO: neve da slittamento.

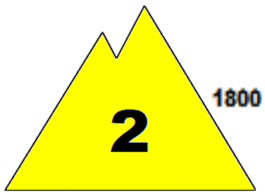

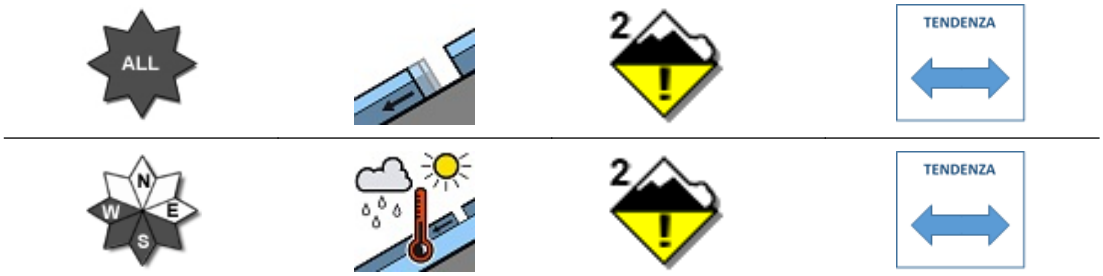

SITUAZIONE TIPO: situazione primaverile.

MANTO NEVOSO: La stabilità del manto nevoso è discreta su alcuni punti (aree) per tutte le esposizioni al di sopra di 1800 mslm, possibili valanghe di dimensioni grandi.
La stabilità del manto nevoso è discreta su alcuni punti (aree) per versanti al sole al di sotto di 1800 mslm, possibili valanghe di dimensioni medie.

AVVERTENZE

In considerazione delle avverse condizioni meteorologiche previste , le attività al di fuori delle piste battute e segnalate sono sconsigliate.

SCALA EUROPEA DEL GRADO DI PERICOLO VALANGHE

5 - MOLTO FORTE | 4 - FORTE | 3 - MARCATO | 2 - MODERATO | 1 - DEBOLE | NO NEVE | NO INFO

LEGENDA PROBLEMA

NEVE FRESCA | LASTRONI DA VENTO | STRATI DEBOLI PERSISTENTI | NEVE BAGNATA | SLITTAMENTO | CORNICI | NESSUN PROBLEMA VALANGHIVO EVIDENTE | NO_INFO

Bollettino realizzato su scala sinottica-regionale (standard EAWS). La sua valutazione non può escludere in alcun modo la necessità di una seria e capace valutazione locale del pericolo (singolo pendio) che può essere anche sensibilmente diverso. Le previsioni meteorologiche sono relative all'orario UTC (per l'Italia +1 in inverno e +2 in estate).

MINISTERO DELLA DIFESA

meteomont
Servizio Nazionale di previsione neve e valanghe

EAWS EUROPEAN AVALANCHE WARNING SERVICES

CARABINIERI

GRAN SASSO EST - LAGA EST

PREVISIONE METEO

Quota		12/02/2026 h6:00	12/02/2026 h12:00	12/02/2026 h18:00
1000	Venti	05 Nodi da S-Ovest	07 Nodi da Ovest	06 Nodi da Ovest
	Temperature	+02 °C	+01 °C	+01 °C
	Temp.percepita	-1 °C	-3 °C	-2 °C
2000	Venti	14 Nodi da S-Ovest	16 Nodi da Ovest	15 Nodi da Ovest
	Temperature	+00 °C	-03 °C	-02 °C
	Temp.percepita	-6 °C	-10 °C	-9 °C
3000	Venti	14 Nodi da Ovest	19 nodi da Ovest	15 nodi da N-Ovest
	Temperature	-04 °C	-09 °C	-07 °C
	Temp.percepita	-11 °C	-19 °C	-15 °C
Zero termico		1800-2000 m.	1500-1700 m.	1600-1800 m.
Fenomeno			—	—
Stato del cielo				

LEGENDA FENOMENI

— Assenza Fenomeni · Nebbia · Foschia · Pioggia debole · Pioggia moderata · Pioggia forte · Temporali

Nevicata debole · Nevicata moderata · Nevicata forte

STATO DEL CIELO

Sereno · Poco nuvoloso · Nuvoloso · Molto nuvoloso · Coperto

Parametri meteonivometrici registrati presso i campi di rilevamento il 11/02/2026.

Località	Comune	Quota (m.s.l.m.)	Altezza neve (cm)	Neve caduta nelle 24 ore (cm)	Temp. Min (°C)	Temp. Max (°C)	Condizioni del tempo
FAVACCHIOLE	Crognaleto (TE)	1016	0	0	+4	+9	Assenza di precipitazioni
PRATO SELVA	Fano Adriano (TE)	1355	0	0	+3	+6	Pioggia debole intermittente
RIGOPIANO	Farindola (PE)	1135	0	0	-1	+10	Assenza di precipitazioni
PRATI DI TIVO	Pietracamela (TE)	1380	10	0	0	+8	Assenza di precipitazioni
CEPPO	Rocca Santa Maria (TE)	1349	0	0	+2	+6	Pioggia debole intermittente
SAN PAOLO	Acquasanta Terme (AP)	960	0	0	+3	+11	Assenza di precipitazioni
COLLE SAN GIACOMO	Civitella del Tronto (TE)	1075	0	0	+2	+10	Assenza di precipitazioni

(*) Rilievi fuori campo

L'INFORMAZIONE E' PREVENZIONE - LEGGI L'ATTUALE GRADO DI PERICOLO VALANGHE!

IL CAPO DEL CENTRO NAZIONALE METEOMONT
(Ten. Col. RFI Emanuela Gini)
FIRMA AUTOGRAFA OMESSA AI SENSI
DELL'ART.3 DEL D.LGS N.39/1993

Bollettino realizzato su scala sinottica-regionale (standard EAWS). La sua valutazione non può escludere in alcun modo la necessità di una seria e capace valutazione locale del pericolo (singolo pendio) che può essere anche sensibilmente diverso. Le previsioni meteorologiche sono relative all'orario UTC (per l'Italia +1 in inverno e +2 in estate).