MAJELLA

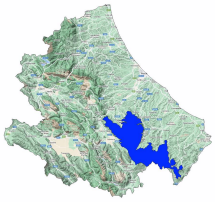

Bollettino Valanghe N. 330/2026 del 11/02/2026 ore 14.00
Validità 48 ore prossima emissione 12/02/2026
A cura del Servizio METEOMONT dell'ARMA dei CARABINIERI
In collaborazione con Servizio Meteorologico dell'Aeronautica militare

SITUAZIONE alle 14:00 del 11/02/2026

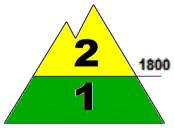

SITUAZIONE TIPO: passaggio da poca a molta neve.



SITUAZIONE TIPO: situazione primaverile.

Quota neve (mslm)	Nord	Sud
	1500 - 1600	1800 - 1900

Altezza Neve (cm)	Neve al suolo	Neve Fresca	Quota (mslm)
	014	000	1650
	000	000	1270

VALANGHE OSSERVATE: Nessuna valanga.

PREVISIONI 12/02/2026

GRADO DI PERICOLO: MODERATO 2

SITUAZIONE TIPO: passaggio da poca a molta neve.

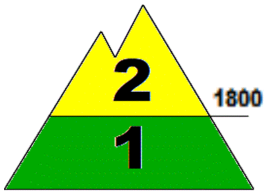

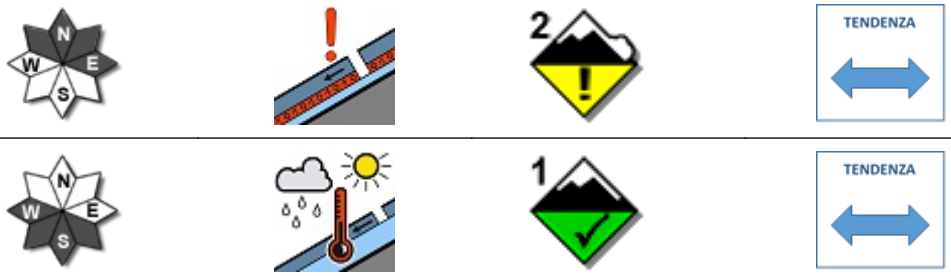

SITUAZIONE TIPO: situazione primaverile.

MANTO NEVOSO: La stabilità del manto nevoso è discreta su alcuni punti (aree) per versanti in ombra al di sopra di 1800 mslm, possibili valanghe di dimensioni medie.
La stabilità del manto nevoso è discreta su molti punti (aree) per versanti al sole al di sotto di 1800 mslm, possibili valanghe di dimensioni piccole.

AVVERTENZE

In considerazione delle avverse condizioni meteorologiche previste , le attività al di fuori delle piste battute e segnalate sono sconsigliate.

SCALA EUROPEA DEL GRADO DI PERICOLO VALANGHE

5 - MOLTO FORTE | 4 - FORTE | 3 - MARCATO | 2 - MODERATO | 1 - DEBOLE | NO NEVE | NO NEVE | NO INFO

LEGENDA PROBLEMA

NEVE FRESCA | LASTRONI DA VENTO | STRATI DEBOLI PERSISTENTI | NEVE BAGNATA | SLITTAMENTO | CORNICI | NESSUN PROBLEMA VALANGHIVO EVIDENTE | NO_INFO

Bollettino realizzato su scala sinottica-regionale (standard EAWS). La sua valutazione non può escludere in alcun modo la necessità di una seria e capace valutazione locale del pericolo (singolo pendio) che può essere anche sensibilmente diverso. Le previsioni meteorologiche sono relative all'orario UTC (per l'Italia +1 in inverno e +2 in estate).

MINISTERO DELLA DIFESA

meteomont
Servizio Nazionale di previsione neve e valanghe

EAWS EUROPEAN AVALANCHE WARNING SERVICES

CARABINIERI

MAJELLA

PREVISIONE METEO

Quota		12/02/2026 h6:00	12/02/2026 h12:00	12/02/2026 h18:00
1000	Venti	02 Nodi da Sud	04 Nodi da Ovest	04 Nodi da Ovest
	Temperature	+02 °C	+01 °C	+00 °C
	Temp.percepita	2 °C	-1 °C	-3 °C
2000	Venti	06 Nodi da S-Ovest	08 Nodi da Ovest	08 nodi da Ovest
	Temperature	+01 °C	-01 °C	-02 °C
	Temp.percepita	-2 °C	-6 °C	-7 °C
3000	Venti	17 Nodi da Ovest	19 nodi da Ovest	14 nodi da N-Ovest
	Temperature	-05 °C	-08 °C	-09 °C
	Temp.percepita	-13 °C	-18 °C	-18 °C
Zero termico		2100-2300 m.	1700-1900 m.	1700-1900 m.
Fenomeno		—		—
Stato del cielo				

LEGENDA FENOMENI

— Assenza Fenomeni · Nebbia · Foschia · Pioggia debole · Pioggia moderata · Pioggia forte · Temporali

Nevicata debole · Nevicata moderata · Nevicata forte

STATO DEL CIELO

Sereno · Poco nuvoloso · Nuvoloso · Molto nuvoloso · Coperto

Parametri meteonivometrici registrati presso i campi di rilevamento il 11/02/2026.

Località	Comune	Quota (m.s.l.m.)	Altezza neve (cm)	Neve caduta nelle 24 ore (cm)	Temp. Min (°C)	Temp. Max (°C)	Condizioni del tempo
QUARTARANA	Campo di Giove (AQ)	1200	0	0	-1	+11	Assenza di precipitazioni
PASSOLANCIANO	Lettomanoppello (PE)	1300	0	0	0	+6	Assenza di precipitazioni
VALICO DELLA FORCHETTA	Palena (CH)	1270	0	0	+2	+6	Assenza di precipitazioni
VALLE DEL SOLE	Pizzoferrato (CH)	1440	0	0	+1	+8	Nebbia con cielo non visibile
MAIELETTA MAMMA ROSA	Pretoro (CH)	1650	14	0	-1	+4	Assenza di precipitazioni
PASSO SAN LEONARDO	Sant'Eufemia a Maiella (PE)	1145	0	0	+4	+9	Assenza di precipitazioni

(*) Rilievi fuori campo

L'INFORMAZIONE E' PREVENZIONE - LEGGI L'ATTUALE GRADO DI PERICOLO VALANGHE!

IL CAPO DEL CENTRO NAZIONALE METEOMONT
(Ten. Col. RFI Emanuela Gini)
FIRMA AUTOGRAFA OMESSA AI SENSI
DELL'ART.3 DEL D.LGS N.39/1993

Bollettino realizzato su scala sinottica-regionale (standard EAWS). La sua valutazione non può escludere in alcun modo la necessità di una seria e capace valutazione locale del pericolo (singolo pendio) che può essere anche sensibilmente diverso. Le previsioni meteorologiche sono relative all'orario UTC (per l'Italia +1 in inverno e +2 in estate).