MINISTERO DELLA DIFESA

meteomont
Servizio Nazionale di previsione neve e valanghe

EAWS EUROPEAN AVALANCHE WARNING SERVICES

CARABINIERI

P.N. ABRUZZO

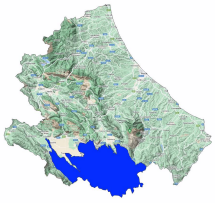

Bollettino Valanghe N. 298/2026 del 11/02/2026 ore 14.00
Validità 48 ore prossima emissione 12/02/2026

A cura del Servizio METEOMONT dell'ARMA dei CARABINIERI
In collaborazione con Servizio Meteorologico dell'Aeronautica militare

SITUAZIONE alle 14:00 del 11/02/2026

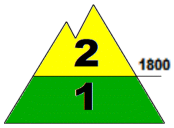

SITUAZIONE TIPO: neve a debole coesione e vento.



SITUAZIONE TIPO: pioggia su neve.

Quota neve (mslm)	Nord	Sud
	1500 - 1600	1800 - 1900

Altezza Neve (cm)	Neve al suolo	Neve Fresca	Quota (mslm)
	016	000	1520
	000	000	1495

VALANGHE OSSERVATE: Valanghe di piccole dimensioni, Valanghe di neve a debole coesione di superficie.

PREVISIONI 12/02/2026

GRADO DI PERICOLO: MODERATO 2

SITUAZIONE TIPO: neve a debole coesione e vento.

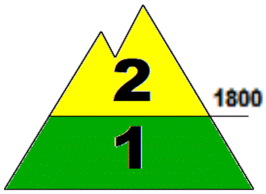

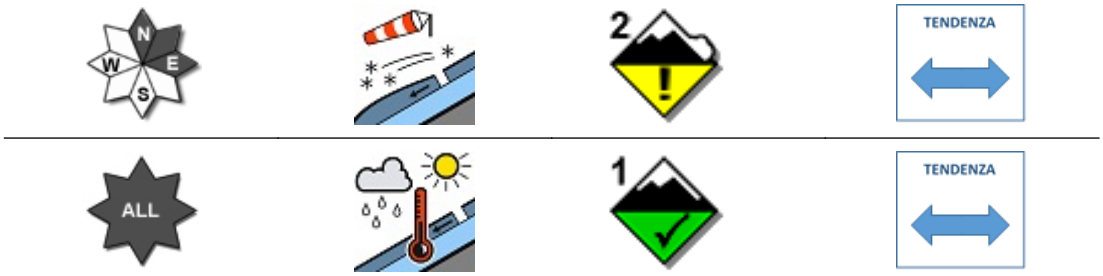

SITUAZIONE TIPO: pioggia su neve.

MANTO NEVOSO: La stabilità del manto nevoso è discreta su alcuni punti (aree) per versanti nord orientali al di sopra di 1800 mslm, possibili valanghe di dimensioni medie.
La stabilità del manto nevoso è discreta su pochi punti (aree) per tutte le esposizioni al di sotto di 1800 mslm, possibili valanghe di dimensioni piccole.

AVVERTENZE

In considerazione delle avverse condizioni meteorologiche previste , le attività al di fuori delle piste battute e segnalate sono sconsigliate.

SCALA EUROPEA DEL GRADO DI PERICOLO VALANGHE

5 - MOLTO FORTE | 4 - FORTE | 3 - MARCATO | 2 - MODERATO | 1 - DEBOLE | NO NEVE | NO INFO

LEGENDA PROBLEMA

NEVE FRESCA | LASTRONI DA VENTO | STRATI DEBOLI PERSISTENTI | NEVE BAGNATA | SLITTAMENTO | CORNICI | NESSUN PROBLEMA VALANGHIVO EVIDENTE | NO_INFO

Bollettino realizzato su scala sinottica-regionale (standard EAWS). La sua valutazione non può escludere in alcun modo la necessità di una seria e capace valutazione locale del pericolo (singolo pendio) che può essere anche sensibilmente diverso. Le previsioni meteorologiche sono relative all'orario UTC (per l'Italia +1 in inverno e +2 in estate).

MINISTERO DELLA DIFESA

meteomont
Servizio Nazionale di previsione neve e valanghe

EAWS EUROPEAN AVALANCHE WARNING SERVICES

CARABINIERI

P.N. ABRUZZO

PREVISIONE METEO

Quota		12/02/2026 h6:00	12/02/2026 h12:00	12/02/2026 h18:00
1000	Venti	03 Nodi da S-Ovest	05 Nodi da Ovest	05 nodi da N-Ovest
	Temperature	+02 °C	+04 °C	+02 °C
	Temp.percepita	0 °C	2 °C	-1 °C
2000	Venti	10 Nodi da S-Ovest	12 Nodi da Ovest	19 nodi da N-Ovest
	Temperature	+00 °C	-02 °C	-02 °C
	Temp.percepita	-5 °C	-8 °C	-10 °C
3000	Venti	17 Nodi da Ovest	17 nodi da Ovest	18 nodi da N-Ovest
	Temperature	-04 °C	-08 °C	-07 °C
	Temp.percepita	-12 °C	-17 °C	-16 °C
Zero termico		1900-2100 m.	1700-1900 m.	1600-1800 m.
Fenomeno				—
Stato del cielo				

LEGENDA FENOMENI

— Assenza Fenomeni · Nebbia · Foschia · Pioggia debole · Pioggia moderata · Pioggia forte · Temporali

Nevicata debole · Nevicata moderata · Nevicata forte

STATO DEL CIELO

Sereno · Poco nuvoloso · Nuvoloso · Molto nuvoloso · Coperto

Parametri meteonivometrici registrati presso i campi di rilevamento il 11/02/2026.

Località	Comune	Quota (m.s.l.m.)	Altezza neve (cm)	Neve caduta nelle 24 ore (cm)	Temp. Min (°C)	Temp. Max (°C)	Condizioni del tempo
FORCA D'ACERO	Pescasseroli (AQ)	1480	35	0	+1	+6	Pioggia debole continua
VALLE GELATA	Pescocostanzo (AQ)	1466	0	0	+2	+8	Assenza di precipitazioni
COPPO DELL'ORSO	Villetta Barrea (AQ)	1520	16	0	-2	+3	Pioggia debole intermittente
LA PESCINA	Rivisondoli (AQ)	1470	17	0	0	+5	Assenza di precipitazioni
PIANO AREMOGNA	Roccaraso (AQ)	1456	0	0	+5	+7	Assenza di precipitazioni
MIMOLA	Scanno (AQ)	1495	0	0	-1	+8	Pioggia debole intermittente
CUCCHIAIO MONTE PRATELLO *	Rivisondoli (AQ)	2069	88	0	N.P.	N.P.	Assenza di precipitazioni
PENDICI MONTE SCALONE *	Scanno (AQ)	1795	134	N.P.	N.P.	N.P.	Pioggia che gela

(*) Rilievi fuori campo

L'INFORMAZIONE E' PREVENZIONE - LEGGI L'ATTUALE GRADO DI PERICOLO VALANGHE!

IL CAPO DEL CENTRO NAZIONALE METEOMONT
(Ten. Col. RFI Emanuela Gini)
FIRMA AUTOGRAFA OMESSA AI SENSI
DELL'ART.3 DEL D.LGS N.39/1993

Bollettino realizzato su scala sinottica-regionale (standard EAWS). La sua valutazione non può escludere in alcun modo la necessità di una seria e capace valutazione locale del pericolo (singolo pendio) che può essere anche sensibilmente diverso. Le previsioni meteorologiche sono relative all'orario UTC (per l'Italia +1 in inverno e +2 in estate).