# TERMINILLO MONTI REATINI E LAGA OVEST

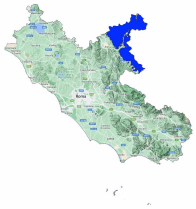

Bollettino Valanghe N. 283/2026 del 10/02/2026 ore 14.00
Validità 48 ore prossima emissione 11/02/2026

**A cura del Servizio METEOMONT dell'ARMA dei CARABINIERI**
**In collaborazione con Servizio Meteorologico dell'Aeronautica militare**

## SITUAZIONE alle 14:00 del 10/02/2026

**SITUAZIONE TIPO: neve pallottolare sepolta.**

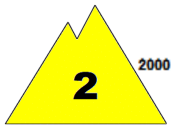




**SITUAZIONE TIPO: neve da slittamento.**

| Quota neve (mslm) | Nord | Sud |
|---|---|---|
| | 1400 - 1600 | 1600 |

| Altezza Neve (cm) | Neve al suolo | Neve Fresca | Quota (mslm) |
|---|---|---|---|
| | 058 | 003 | 1770 |
| | 014 | 000 | 1350 |

**VALANGHE OSSERVATE: Valanghe di piccole dimensioni, Valanghe di neve a debole coesione di superficie.**

## PREVISIONI 11/02/2026

## GRADO DI PERICOLO: MODERATO 2

## SITUAZIONE TIPO: neve pallottolare sepolta.

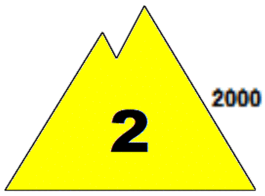


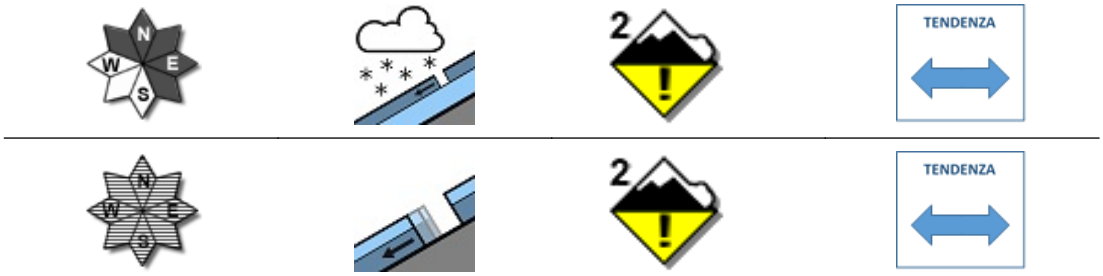


## SITUAZIONE TIPO: neve da slittamento.

**MANTO NEVOSO: La stabilità del manto nevoso è scarsa su molti punti (aree) per versanti da nord ovest a sud est compresi al di sopra di 2000 mslm, possibili valanghe di dimensioni medie.**
**La stabilità del manto nevoso è scarsa su alcuni punti (aree) per isolati pendii al di sotto di 2000 mslm, possibili valanghe di dimensioni medie.**

## AVVERTENZE

In considerazione delle avverse condizioni meteorologiche previste, e della scarsa visibilità, risulterà difficoltosa l'individuazione dell'itinerario e della valutazione del singolo pendio.

## SCALA EUROPEA DEL GRADO DI PERICOLO VALANGHE

## LEGENDA PROBLEMA

**Bollettino realizzato su scala sinottica-regionale (standard EAWS). La sua valutazione non può escludere in alcun modo la necessità di una seria e capace valutazione locale del pericolo (singolo pendio) che può essere anche sensibilmente diverso. Le previsioni meteorologiche sono relative all'orario UTC (per l'Italia +1 in inverno e +2 in estate).**

MINISTERO DELLA DIFESA

meteomont
Servizio Nazionale di previsione neve e valanghe

EAWS EUROPEAN AVALANCHE WARNING SERVICES

CARABINIERI

# TERMINILLO MONTI REATINI E LAGA OVEST

## PREVISIONE METEO

| Quota | | 11/02/2026 h6:00 | 11/02/2026 h12:00 | 11/02/2026 h18:00 |
|---|---|---|---|---|
| 1000 | Venti | 06 Nodi da S-Ovest | 06 Nodi da Ovest | 04 Nodi da Ovest |
| | Temperature | +01 °C | +04 °C | +02 °C |
| | Temp.percepita | -2 °C | 1 °C | -0 °C |
| 2000 | Venti | 16 Nodi da S-Ovest | 15 Nodi da Ovest | 11 nodi da Ovest |
| | Temperature | -01 °C | +00 °C | -01 °C |
| | Temp.percepita | -8 °C | -6 °C | -7 °C |
| 3000 | Venti | 17 Nodi da Ovest | 19 Nodi da Ovest | 17 Nodi da Ovest |
| | Temperature | -04 °C | -06 °C | -05 °C |
| | Temp.percepita | -12 °C | -15 °C | -13 °C |
| Zero termico | | 1600-1800 m. | 1900-2100 m. | 1800-2000 m. |
| Fenomeno | | | | — |
| Stato del cielo | | | | |

## LEGENDA FENOMENI

— Assenza Fenomeni · Nebbia · Foschia · Pioggia debole · Pioggia moderata · Pioggia forte · Temporali

Nevicata debole · Nevicata moderata · Nevicata forte

## STATO DEL CIELO

Sereno · Poco nuvoloso · Nuvoloso · Molto nuvoloso · Coperto

## Parametri meteonivometrici registrati presso i campi di rilevamento il 10/02/2026.

| Località | Comune | Quota (m.s.l.m.) | Altezza neve (cm) | Neve caduta nelle 24 ore (cm) | Temp. Min (°C) | Temp. Max (°C) | Condizioni del tempo |
|---|---|---|---|---|---|---|---|
| PESCHIERE | Amatrice (RI) | 1270 | 0 | 0 | +1 | +6 | Assenza di precipitazioni |
| M. CAIDURO | Cittareale (RI) | 1300 | 5 | 0 | 0 | +5 | Assenza di precipitazioni |
| VALLONINA | Leonessa (RI) | 1350 | 14 | 0 | -1 | +7 | Assenza di precipitazioni |
| GIRO DELL'ANELLO - VILLA CHIGI * | Rieti (RI) | 1770 | 58 | 3 | -2 | 0 | Assenza di precipitazioni |
| TERMINILLO - PISTA CINZANO * | Cantalice (RI) | 1710 | 78 | 4 | N.P. | N.P. | Nevicata debole intermittente |

(*) Rilievi fuori campo

**L'INFORMAZIONE E' PREVENZIONE - LEGGI L'ATTUALE GRADO DI PERICOLO VALANGHE!**

**IL CAPO DEL CENTRO NAZIONALE METEOMONT**
**(Ten. Col. RFI Emanuela Gini)**
**FIRMA AUTOGRAFA OMESSA AI SENSI**
**DELL'ART.3 DEL D.LGS N.39/1993**

Bollettino realizzato su scala sinottica-regionale (standard EAWS). La sua valutazione non può escludere in alcun modo la necessità di una seria e capace valutazione locale del pericolo (singolo pendio) che può essere anche sensibilmente diverso. Le previsioni meteorologiche sono relative all'orario UTC (per l'Italia +1 in inverno e +2 in estate).