Bulletin d'estimation du risque d'avalanche

(valable en dehors des pistes balisées et ouvertes)

MASSIF : Aure Louron

Rédigé le mercredi 11 février 2026 à 16h

Estimation des risques pour le : JEUDI 12 FÉVRIER

HUMIDIFICATION EN PROFONDEUR ET PLAQUES A VENT EN FORMATION JEUDI

3

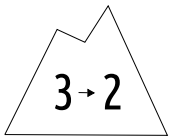

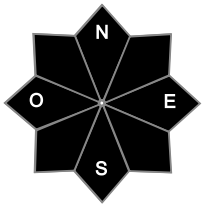

Manteau humide

Indice de risque marqué évoluant en limité.

Départs spontanés : En neige humide ce mercredi soir

Déclenchements provoqués : Fines plaques à vent à toutes altitudes

Indices de risque : 5 très fort - 4 fort - 3 marqué - 2 limité - 1 faible -- En noir : les pentes les plus dangereuses

Stabilité du manteau neigeux

Situation avalancheuse typique : avalanches de fond — neige ventée

Déclenchements provoqués :
De fines plaques à vent sont en formation jeudi avec les chutes de neige ventée en nord-ouest. Elles peuvent se former même loin des crêtes et des sommets. Risque limité à un large secteur Est, Sud-Est. Elles deviennent de plus en plus facilement déclenchables au fil des chutes de neige de la journée

Départs spontanés : Dans quelques pentes, des départs en neige humide sont encore possibles ce mercredi soir, sous les fortes pluies. Ils peuvent se produire en toutes orientations et sont souvent de taille moyenne à grande, mais localement, un très grand restent possibles. Elles se produisent généralement dans les pentes les plus chargés, dans un large secteur Est et Nord, et partent du sol, ou, localement, d'une couche fragile enfouit n'ayant pas encore été humidifié. Le déclenchement de ces avalanches devient de plus en plus difficile au fil de la nuit avec un net refroidissement.

Autres : Vigilance orange **vent** jeudi matin.

Qualité de la neige

Enneigement : Bon pour la saison, malgré une fonte importantes ces derniers jours. Les crêtes, cols et sommets en expositions ouest sont souvent pelés. De petites accumulations sont présentes dans un large secteur Est.
Limites skiables : Manteau neigeux skiable à partir de 1600 m.
État de la neige : Sous 2500 m, le manteau neigeux est bien humidifié jusqu'en profondeur. Un saupoudrage peut être présent au petit matin, mais il repose généralement sur un manteau neigeux dur sous 2500 m. Au-dessus, la neige est très travaillée par le vent.

Aperçu météo pour le jeudi 12 février

	nuit	matin	après-midi	soir
Pluie-Neige	1 300 m	1 200 m	1 400 m	
Iso 0 °C	1 600 m	1 500 m	1 700 m	1 800 m
Vent 1500 m	→ 90 km/h	↘ 80 km/h	↘ 60 km/h	↘ 25 km/h
Vent 3000 m	→ 120 km/h	↘ 120 km/h	↘ 100 km/h	↘ 55 km/h

Après le passage pluvio instable de ce mercredi soir, de faibles averses de neige tombent la nuit et la journée de jeudi, sous un vent tempétueux.

Épaisseur de neige hors-piste

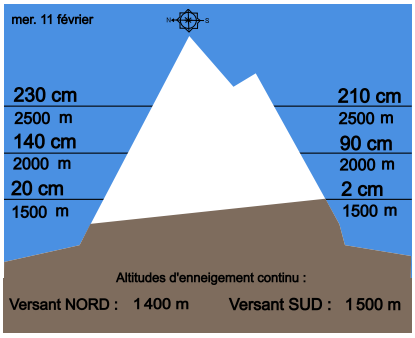

Précipitations à 1800 m

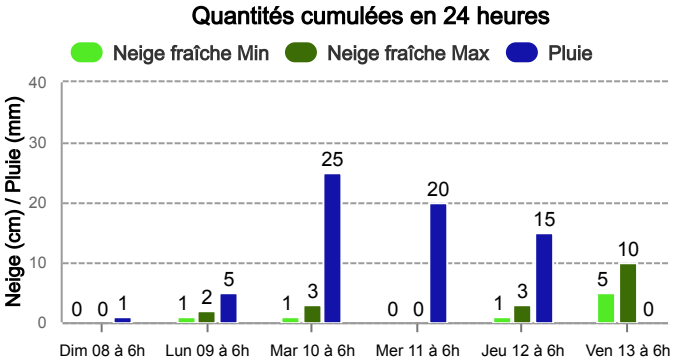

Tendance du vendredi 13 février

2

Indice de risque limité

Nouvelles plaques en formation sous les quelques chutes de neiges ventées, surtout en fond de chaine.

Pour consulter la vigilance en cours, veuillez vous rendre sur le site https://vigilance.meteofrance.fr/fr

Météo-France - 73 avenue de Paris, 94165 Saint-Mandé cedex - Contact : contact@meteo.fr

Rédigé par Météo-France avec la contribution des observateurs du réseau nivo-météorologiques. Partenariat : ANMSM (Maires de Stations de Montagne), DSF (Domaines Skiables de France), ADSP (Directeurs de Pistes et de la Sécurité des Stations de Sports d'Hiver) et autres acteurs de la montagne.

Bulletin neige & avalanches par téléphone au 0 892 68 10 20 Service 0,35 € / min + prix appel

RÉPUBLIQUE FRANÇAISE
Liberté Égalité Fraternité

METEO FRANCE
À VOS CÔTÉS, DANS UN CLIMAT QUI CHANGE

Bulletin d'estimation du risque d'avalanche
(valable en dehors des pistes balisées et ouvertes)

MASSIF : Aure Louron

Rédigé le mercredi 11 février 2026 à 16h

Conditions nivo-météo des 7 derniers jours

	jeu. 05/02				ven. 06/02				sam. 07/02				dim. 08/02				lun. 09/02				mar. 10/02				mer. 11/02			
	03h	09h	15h	21h	03h	09h	15h	21h	03h	09h	15h	21h	03h	09h	15h	21h	03h	09h	15h	21h	03h	09h	15h	21h	03h	09h	15h	21h
Météo																												
Vent (km/h)	75	110	95	70	60	60	60	50	40	35	35	45	50	35	50	40	45	50	55	80	75	90	100	100	90	110	110	120
à 3000m																												
Vent (km/h)	45	70	65	40	30	35	25	25	20	10	15	25	30	10	20	15	15	15	15	20	40	50	50	40	30	40	60	90
à 1500m																												

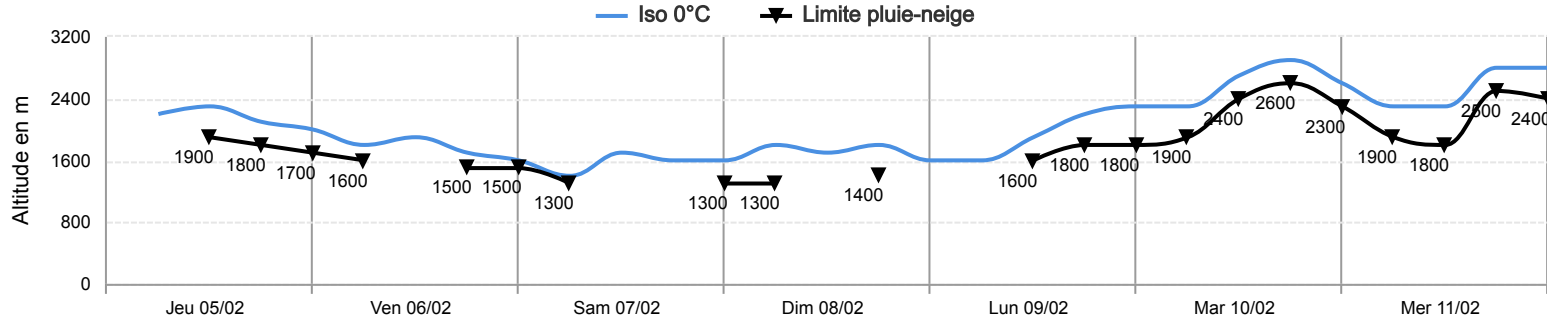

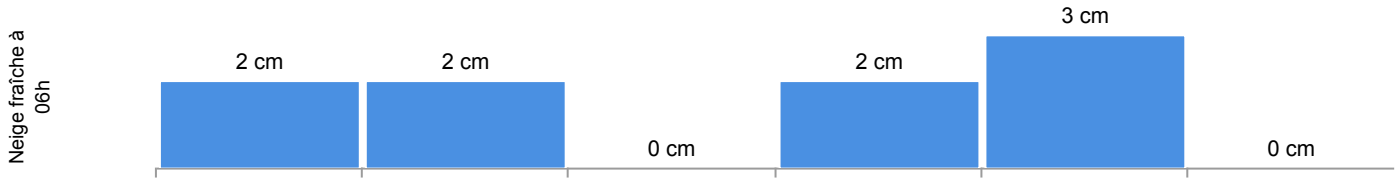

Risque d'avalanche	jeu. 05/02	ven. 06/02	sam. 07/02	dim. 08/02	lun. 09/02	mar. 10/02	mer. 11/02
	3	3	2	2	2	3	3

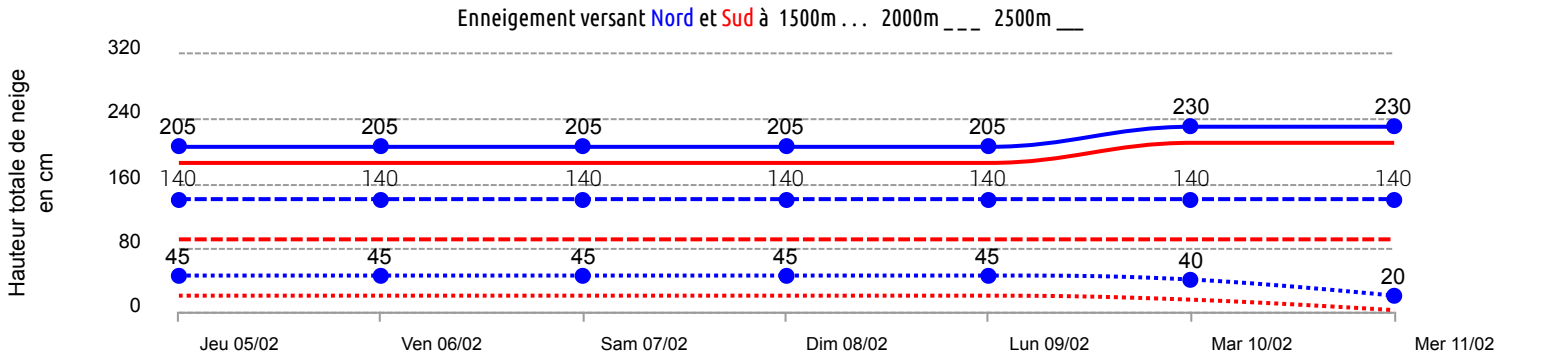

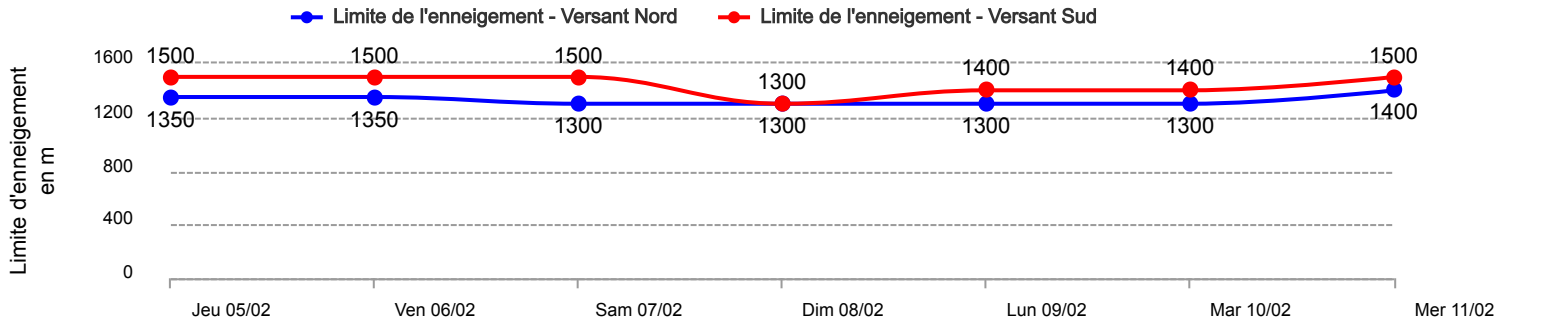

Pour consulter la vigilance en cours, veuillez vous rendre sur le site https://vigilance.meteofrance.fr/fr

Météo-France - 73 avenue de Paris, 94165 Saint-Mandé cedex - Contact : contact@meteo.fr

Rédigé par Météo-France avec la contribution des observateurs du réseau nivo-météorologiques. Partenariat : ANMSM (Maires de Stations de Montagne), DSF (Domaines Skiables de France), ADSP (Directeurs de Pistes et de la Sécurité des Stations de Sports d'Hiver) et autres acteurs de la montagne.

Bulletin neige & avalanches par téléphone au
0 892 68 10 20 Service 0,35 € / min + prix appel