RÉPUBLIQUE FRANÇAISE
Liberté Égalité Fraternité

METEO FRANCE
À VOS CÔTÉS, DANS UN CLIMAT QUI CHANGE

Bulletin d'estimation du risque d'avalanche
(valable en dehors des pistes balisées et ouvertes)

MASSIF : Bauges

Rédigé le mercredi 11 février 2026 à 16h

Estimation des risques pour le : JEUDI 12 FÉVRIER

ÉPISODE D'AMPLEUR EXCEPTIONNEL

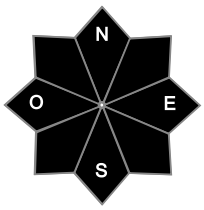

Indice de risque fort.

Départs spontanés : très grandes avalanches pouvant parcourir de grande dénivellation

Déclenchements provoqués : risque maximal

Indices de risque : 5 très fort - 4 fort - 3 marqué - 2 limité - 1 faible -- En noir : les pentes les plus dangereuses

Stabilité du manteau neigeux

Situation avalancheuse typique : neige fraîche — neige humide

Situation exceptionnelle avec des cumuls de neige fraiche en fin de journée jeudi de plus d'1 m à 2000 m.

Départs spontanés :
* **très nombreuses avalanches de neige fraîche, risque fort jeudi en journée.** Taille 2 à 3 (moyenne à grande), rarement 4 (très grande). Ces très grandes avalanches pourraient parcourir d'importante dénivellation.
* avalanches de neige humide, sous la pluie mercredi en soirée/début de nuit sous 1700 m. Taille 1 à 2 (petite à moyenne).

Déclenchements provoqués :
* **nombreuses plaques friables** dans la neige fraîche, **plus nombreuses et épaisses au fil de la journée. Très facilement déclenchable. Généralisées à toutes les pentes** et a fortiori dans les secteurs exposés au fort vent de sud-ouest. Taille 2 à 3 (moyenne à grande), plus rarement 4 (très grande) proche des plus hauts sommets.

Qualité de la neige

Enneigement : Pour la saison, l'enneigement est correct. On peut chausser les skis vers 1300/1400 m.
Nombreuses congères et grosses corniches.

Qualité de la neige ce jeudi matin :
En début de matinée :
* 50/100 cm de neige fraîche au-dessus de 1800 m.
* 30/60 cm de neige fraîche humide vers 1500 m.
* neige mouillée sous 1200 m.

Au fil de la journée, les quantités de neige fraîche augmentent (30/50 cm supplémentaires en journée au-dessus de 1800 m)

Aperçu météo pour le jeudi 12 février

Poursuite des averses de neige avec une limite pluie-neige autour de 1300 m. Vent en altitude.

	nuit	matin	après-midi	soir
Pluie-Neige	1 400 m	1 200 m	1 200 m	1 100 m
Iso 0 °C	1 800 m	1 600 m	1 600 m	1 500 m
Vent 1500 m	↗ 45 km/h	↗ 40 km/h	→ 40 km/h	→ 30 km/h
Vent 2000 m	↗ 50 km/h	↗ 50 km/h	→ 50 km/h	→ 35 km/h

Épaisseur de neige hors-piste

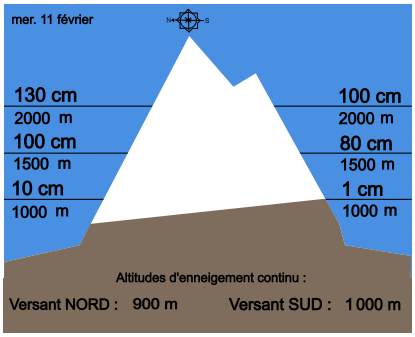

Précipitations à 1800 m

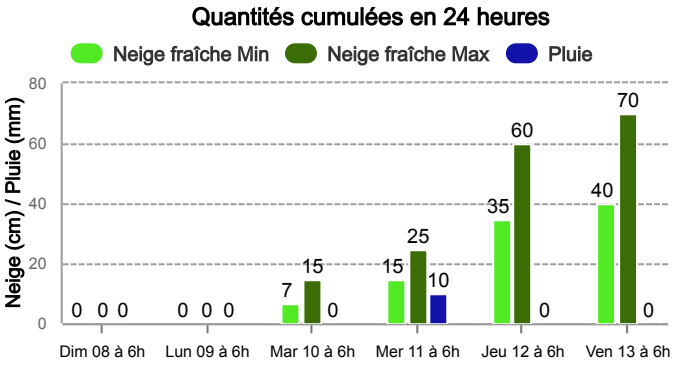

Tendance du vendredi 13 février

Indice de risque fort

Risque spontané en nette baisse, mais risque accidentel encore fort.

Pour consulter la vigilance en cours, veuillez vous rendre sur le site https://vigilance.meteofrance.fr/fr

Météo-France - 73 avenue de Paris, 94165 Saint-Mandé cedex - Contact : contact@meteo.fr

Rédigé par Météo-France avec la contribution des observateurs du réseau nivo-météorologiques. Partenariat : ANMSM (Maires de Stations de Montagne), DSF (Domaines Skiables de France), ADSP (Directeurs de Pistes et de la Sécurité des Stations de Sports d'Hiver) et autres acteurs de la montagne.

Bulletin neige & avalanches par téléphone au
0 892 68 10 20 Service 0,35 € / min + prix appel

RÉPUBLIQUE FRANÇAISE
Liberté Égalité Fraternité

METEO FRANCE
À VOS CÔTÉS, DANS UN CLIMAT QUI CHANGE

Bulletin d'estimation du risque d'avalanche

(valable en dehors des pistes balisées et ouvertes)

MASSIF : Bauges

Rédigé le mercredi 11 février 2026 à 16h

Conditions nivo-météo des 7 derniers jours

	jeu. 05/02				ven. 06/02				sam. 07/02				dim. 08/02				lun. 09/02				mar. 10/02				mer. 11/02			
	03h	09h	15h	21h	03h	09h	15h	21h	03h	09h	15h	21h	03h	09h	15h	21h	03h	09h	15h	21h	03h	09h	15h	21h	03h	09h	15h	21h
Météo																												
Vent (km/h)	30	30	30	25	30	30	25	20	20	10	10	10	10	10	15	10	10	15	25	45	45	55	40	50	65	50	45	65
à 2000m																												
Vent (km/h)	20	20	20	20	25	25	20	10	10	5	5	5	5	5	10	5	5	10	15	35	35	40	30	40	50	40	35	55
à 1500m																												

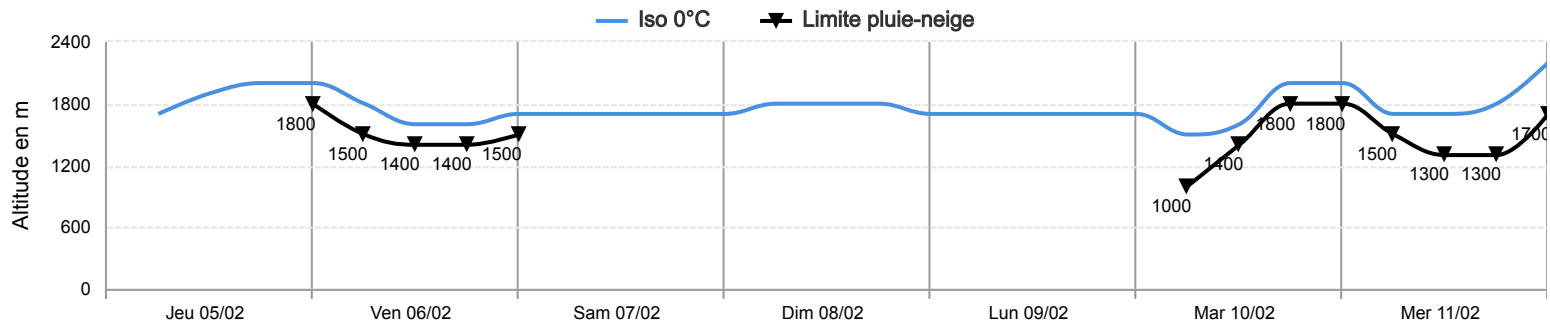

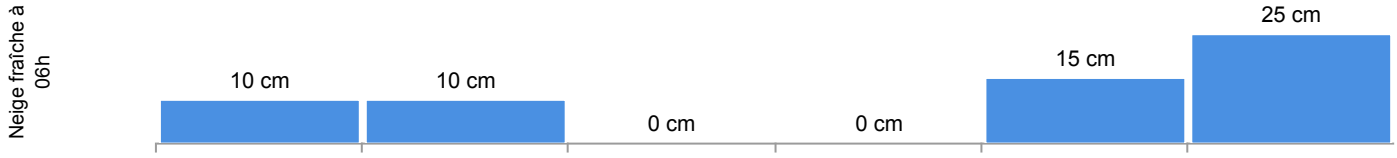

Risque d'avalanche	jeu. 05/02	ven. 06/02	sam. 07/02	dim. 08/02	lun. 09/02	mar. 10/02	mer. 11/02
	3	3	2	2	2	3	4

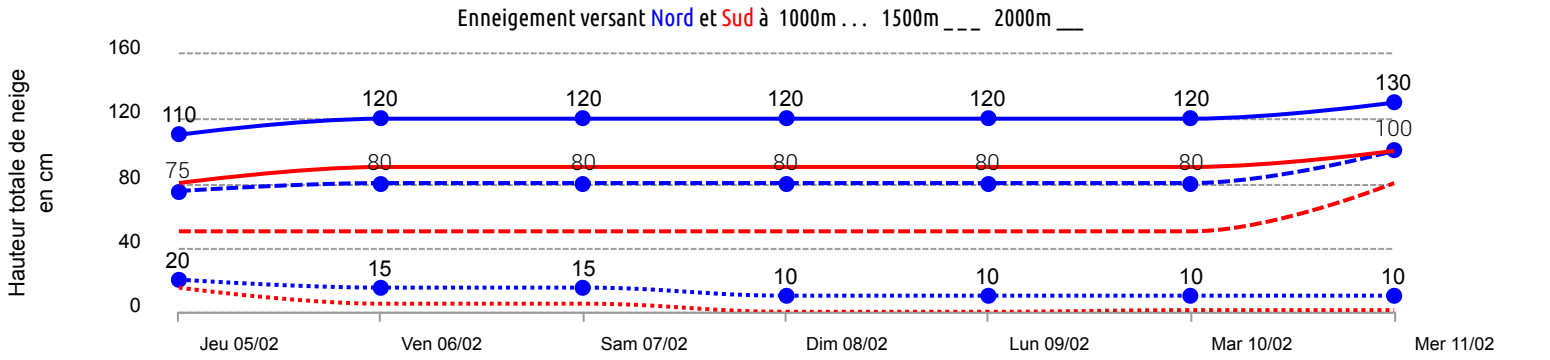

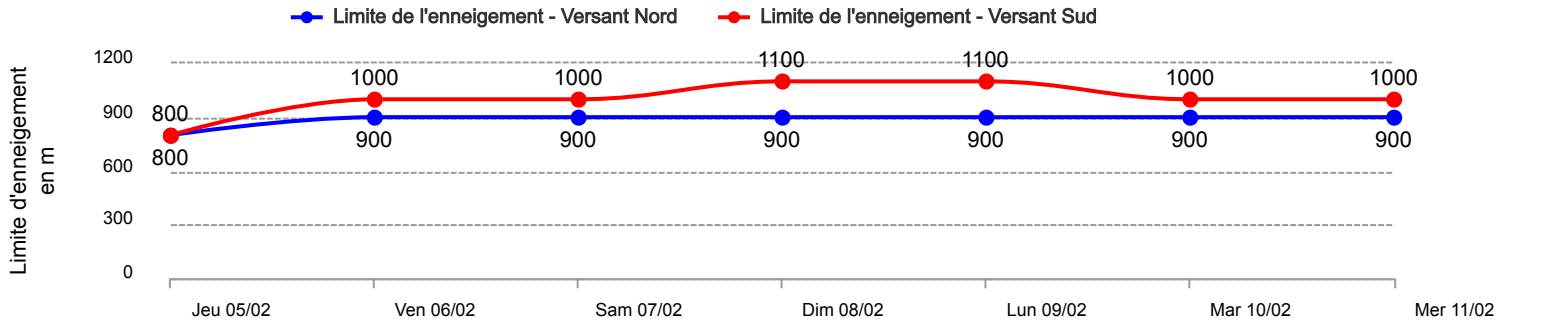

Pour consulter la vigilance en cours, veuillez vous rendre sur le site https://vigilance.meteofrance.fr/fr

Météo-France - 73 avenue de Paris, 94165 Saint-Mandé cedex - Contact : contact@meteo.fr

Rédigé par Météo-France avec la contribution des observateurs du réseau nivo-météorologiques. Partenariat : ANMSM (Maires de Stations de Montagne), DSF (Domaines Skiables de France), ADSP (Directeurs de Pistes et de la Sécurité des Stations de Sports d'Hiver) et autres acteurs de la montagne.

Bulletin neige & avalanches par téléphone au
0 892 68 10 20 Service 0,35 € / min + prix appel