Bulletin d'estimation du risque d'avalanche

(valable en dehors des pistes balisées et ouvertes)

MASSIF : Belledonne

Rédigé le mercredi 11 février 2026 à 16h

Estimation des risques pour le : JEUDI 12 FÉVRIER

FORTES CHUTES DE NEIGE ATTENDUES EN JOURNEE DE JEUDI... DE NOMBREUSES NOMBREUSES GRANDES AVALANCHES, ARRIVANT PARFOIS EN MOYENNE MONTAGNE...

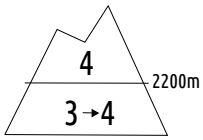

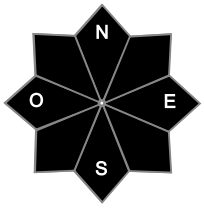

Altitude/ couloirs

Au-dessus de 2200m indice de risque fort, plus bas indice marqué évoluant en fort.

Départs spontanés : Vers de nombreuses grandes avalanches/cassures de plaques en altitude, atteignant parfois les forêts/la moyenne montagne. Très grande avalanche non exclue...

Déclenchements provoqués : Très faciles en altitude, puis sous 2000m en journée de jeudi

Indices de risque : 5 très fort - 4 fort - 3 marqué - 2 limité - 1 faible -- En noir : les pentes les plus dangereuses

Stabilité du manteau neigeux

Situation avalancheuse typique : neige fraîche couche fragile persistante

Conditions très perturbées, ventées, neigeuses en altitude puis en moyenne montagne... Situation nivologique évoluant défavorablement, particulièrement à haute altitude et dans tous les couloirs. Vers 2500m, on attend jusqu'à 1m de neige récente ventée...

Départs spontanés :

En altitude, dès mercredi soir, on s'attend à de possibles grandes avalanches sous le vent de Sud-Ouest, parfois à quelques larges et épaisses cassures spontanées (présence de sous couche fragiles enfouies au dessus de 2200m environ).

Jeudi en journée, l'épaisseur de neige récente atteindrait 40/60 cm vers 1800m et plus d'1m vers 2500m avec du vent d'Ouest puis Nord-Ouest.... De nombreuses grandes avalanches sont attendues, balayant couloirs et pentes raides. Celles ci peuvent parfois atteindre la moyenne montagne en dépôts plus humides (route du Rivier par exemple ?). En haute montagne, la présence de sous couche fragile enfouie pourrait faciliter une avalanche d'ampleur et trajectoire peu habituelle.

Déclenchements provoqués :

Haute montagne infréquentable. Ruptures très faciles au passage du moindre skieur. Sous 2000/2200m, risque accidentel marqué puis fort même loin des crêtes, vu l'intensité de la chute de neige et le vent sensible à fort...

En moyenne montagne, éviter bas de couloirs et clairières raides (risque de coulée humide).

Qualité de la neige

Qualification de l'enneigement : L'enneigement s'améliore encore en haute-montagne, dans les combes, où il devient excellent pour la saison. Il est en revanche médiocre à basse altitude, et plus bas que 1500/1700m...

Limites skiables : vers 1200/1500 m (hors sapins).

Qualité de la neige jeudi : Plus bas que 1300m, neige dense très humide. Entre 1300 et 1500/1600m neige fraîche collante... Au dessus couche de neige de plus importante au fil des heures et sèche, bien ventée en altitude.

Fortes épaisseurs au dessus de 2200m environ avec plus d'1m de neige récente vers 2500m, de grosses congères/corniches, des croupes plus dégarnies...

Aperçu météo pour le jeudi 12 février

	nuit	matin	après-midi	soir

Redoux temporaire mercredi soir, jeudi plus froid et très neigeux dès la moyenne montagne... Forts vents de Sud-Ouest puis Ouest à Nord-Ouest...

Pluie-Neige	1 600 m	1 300 m	1 300 m	1 100 m
Iso 0 °C	2 100 m	1 600 m	1 600 m	1 500 m
Vent 2000 m	↗ 80 km/h	→ 70 km/h	↘ 70 km/h	↘ 55 km/h
Vent 3000 m	→ 100 km/h	↘ 100 km/h	↘ 90 km/h	↘ 75 km/h

Épaisseur de neige hors-piste

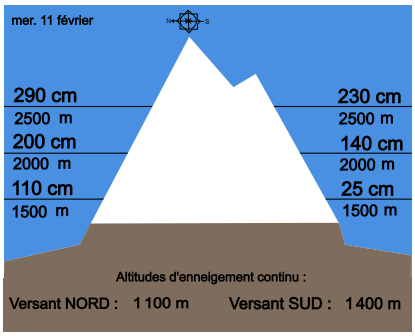

Précipitations à 1800 m

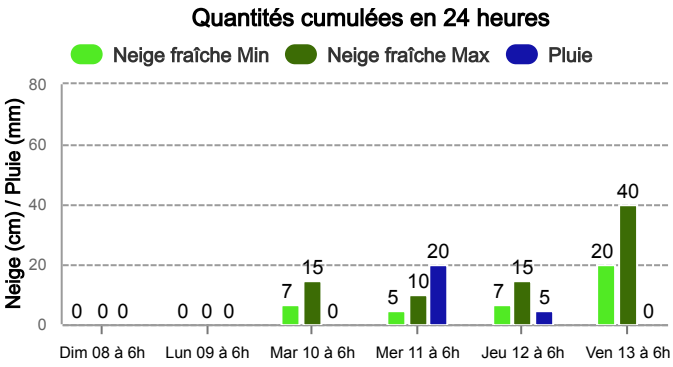

Tendance du vendredi 13 février

Indice de risque marqué

Risque d'avalanche en très légère baisse (pause de la "crue" avalancheuse)

Vendredi temporairement plus calme et sec, des éclaircies.

Au soleil/près des rochers des avalanches de neige récente ; en altitude risque accidentel de plaque encore marqué, voire fort ...

Pour consulter la vigilance en cours, veuillez vous rendre sur le site https://vigilance.meteofrance.fr/fr

Météo-France - 73 avenue de Paris, 94165 Saint-Mandé cedex - Contact : contact@meteo.fr

Rédigé par Météo-France avec la contribution des observateurs du réseau nivo-météorologiques. Partenariat : ANMSM (Maires de Stations de Montagne), DSF (Domaines Skiables de France), ADSP (Directeurs de Pistes et de la Sécurité des Stations de Sports d'Hiver) et autres acteurs de la montagne.

Bulletin neige & avalanches par téléphone au 0 892 68 10 20 Service 0,35 € / min + prix appel

RÉPUBLIQUE FRANÇAISE
Liberté Égalité Fraternité

METEO FRANCE
À VOS CÔTÉS, DANS UN CLIMAT QUI CHANGE

Bulletin d'estimation du risque d'avalanche
(valable en dehors des pistes balisées et ouvertes)
MASSIF : Belledonne

Rédigé le mercredi 11 février 2026 à 16h

Conditions nivo-météo des 7 derniers jours

	jeu. 05/02				ven. 06/02				sam. 07/02				dim. 08/02				lun. 09/02				mar. 10/02				mer. 11/02			
	03h	09h	15h	21h	03h	09h	15h	21h	03h	09h	15h	21h	03h	09h	15h	21h	03h	09h	15h	21h	03h	09h	15h	21h	03h	09h	15h	21h
Météo																												
Vent (km/h)	35	30	45	40	40	30	25	20	15	10	5	5	15	25	20	25	30	30	35	40	50	40	50	70	100	85	85	100
à 3000m																												
Vent (km/h)	15	15	30	20	25	25	20	10	10	5	10	10	10	10	10	15	20	10	15	20	35	25	40	50	80	55	55	90
à 2000m																												

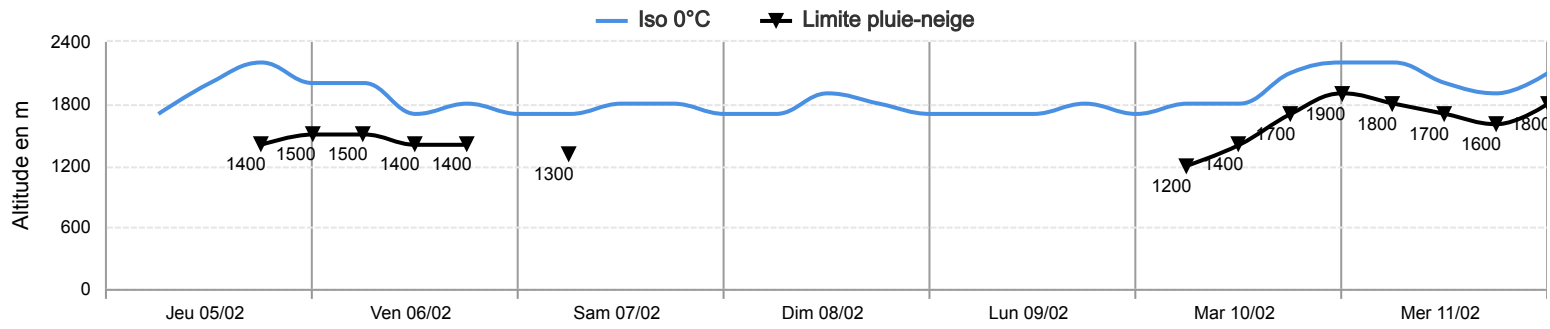

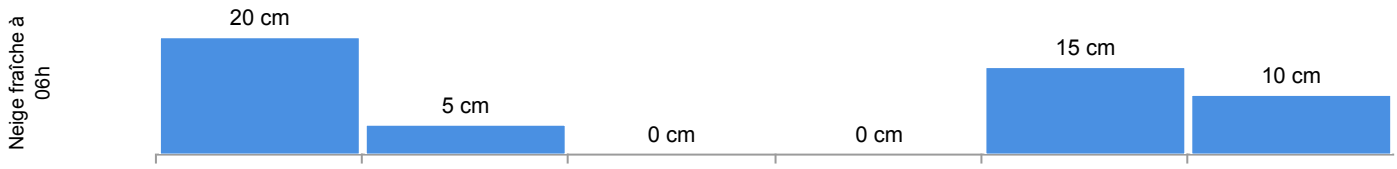

Risque d'avalanche	jeu. 05/02	ven. 06/02	sam. 07/02	dim. 08/02	lun. 09/02	mar. 10/02	mer. 11/02
	3	3	3	3	2	3	4

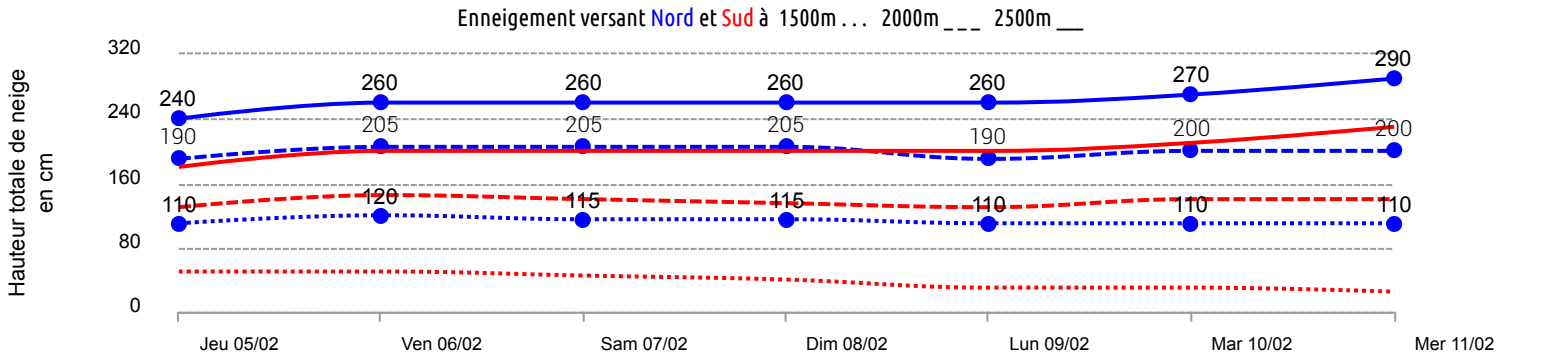

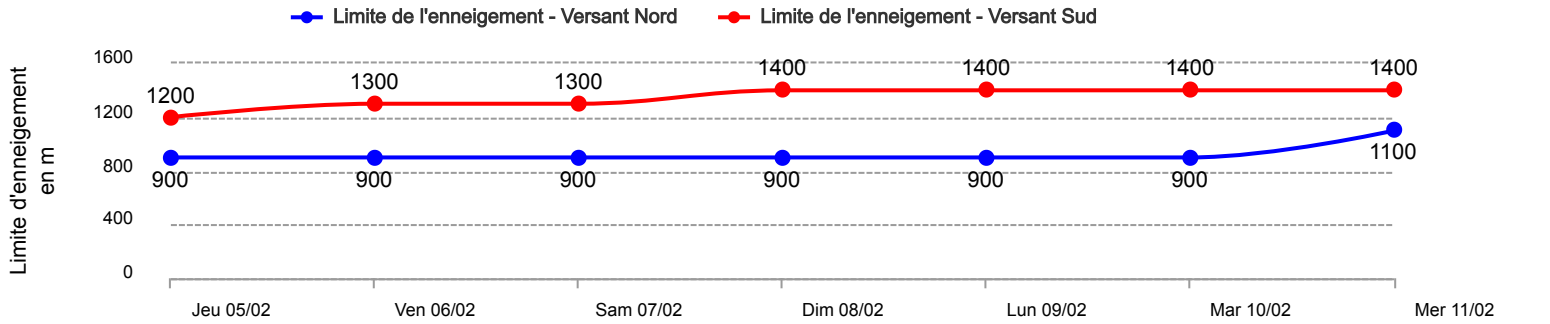

Pour consulter la vigilance en cours, veuillez vous rendre sur le site https://vigilance.meteofrance.fr/fr

Météo-France - 73 avenue de Paris, 94165 Saint-Mandé cedex - Contact : contact@meteo.fr

Rédigé par Météo-France avec la contribution des observateurs du réseau nivo-météorologiques. Partenariat : ANMSM (Maires de Stations de Montagne), DSF (Domaines Skiables de France), ADSP (Directeurs de Pistes et de la Sécurité des Stations de Sports d'Hiver) et autres acteurs de la montagne.

Bulletin neige & avalanches par téléphone au
0 892 68 10 20 Service 0,35 € / min + prix appel