Bulletin d'estimation du risque d'avalanche

(valable en dehors des pistes balisées et ouvertes)

MASSIF : Capcir Puymorens

Rédigé le mercredi 11 février 2026 à 16h

Estimation des risques pour le : JEUDI 12 FÉVRIER

NEIGE HUMIDE CETTE NUIT, FINE PLAQUES À VENT EN JOURNÉE.

3

3 → 2

N O E S

Indice de risque marqué évoluant en limité.

Départs spontanés : Ce soir et dans la nuit, départs en neige humide encore possibles en pentes raides.

Déclenchements provoqués : Fines plaques à vent en neige récente, dures, déclenchables eventuellement en haut d'un couloir ou sous une crête de haute montagne.

Indices de risque : 5 très fort - 4 fort - 3 marqué - 2 limité - 1 faible -- En noir : les pentes les plus dangereuses

Stabilité du manteau neigeux

Situation avalancheuse typique : neige humide — neige ventée

Départs spontanés : ce mercredi soir et la nuit prochaine, encore des départs de neige humide possibles en tous versants avec l'apport de nouvelles pluies et de la persistance de la couche nuageuse. L'humidification du manteau neigeux se poursuit encore pendant quelques heures, gagnant en profondeur, et pouvant fragiliser certaines sous-couches. Si l'activité attendue est moindre que celle observée mardi, quelques avalanches de taille 2 ou 3 (grande), parfois sous forme d'avalanches de fond jusqu'au sol, peuvent se produire encore dans la nuit jusqu'en haute montagne.
Le risque diminue en journée grâce au refroidissement et au timide regel en surface qui s'amorcera, même si ponctuellement, une avalanche de fond pourra encore se produire, plutôt en dessous de 2000 m.
Observable : Neige pourrie en profondeur, large fissure d'apparition récente en pentes herbeuses ou dalles rocheuses.

Déclenchements provoqués : Dès la moyenne montagne, formation possibles en journée de jeudi de quelques plaques peu épaisses, mais très compactes, le plus souvent en versants Est.
Elles seront déclenchables à l'entrée de quelques couloirs ou pentes sommitales raides chargées par le vent tempétueux.(avalanche de taille1 (petite), très rarement 2 (moyenne)).
Observables : accumulations en neige récente cartonnée, voisinant avec des zones glacées ou en vieille neige regelée, fissures sous les skis.

Qualité de la neige

Enneigement :
Après plusieurs Hivers déficitaires, l'enneigement sur le massif en cette mi-Février demeure légèrement au-dessus des normales et nettement supérieur à ces cinq dernières années.
Malgré le fort redoux très arrosé de ces dernières heures, La limite de skiabilité se situe au plus bas vers 1300/1400 m dans les meilleures configurations et on peut skier plus confortablement vers 1500/1600m

État de la neige :
Au petit matin, un peu de neige récente très ventée saupoudrera les sols dès la moyenne montagne, avec en fin de journée jusqu'à 10/15 cm dans les rares secteurs à l'abri du vent. Lent regel en dessous de ces quelques centimètres de neige fraîche, plus efficace en altitude et dans les zones très exposées eu vent. Au son cœur, le manteau neigeux restera encore souvent imbibé d'eau liquide en dessous de 2000 m.

Aperçu météo pour le jeudi 12 février

Grosses averses en début de nuit, un peu de neige Jeudi.

	nuit	matin	après-midi	soir
Pluie-Neige	2 200 m	1 300 m	1 400 m	
Iso 0 °C	2 700 m	1 800 m	1 900 m	1 900 m
Vent 2000 m	→ 55 km/h	↘ 85 km/h	→ 80 km/h	↘ 60 km/h
Vent 3000 m	→ 90 km/h	↘ 110 km/h	↘ 105 km/h	↘ 85 km/h

Épaisseur de neige hors-piste

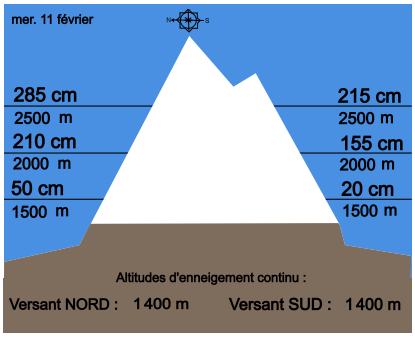

Précipitations à 1800 m

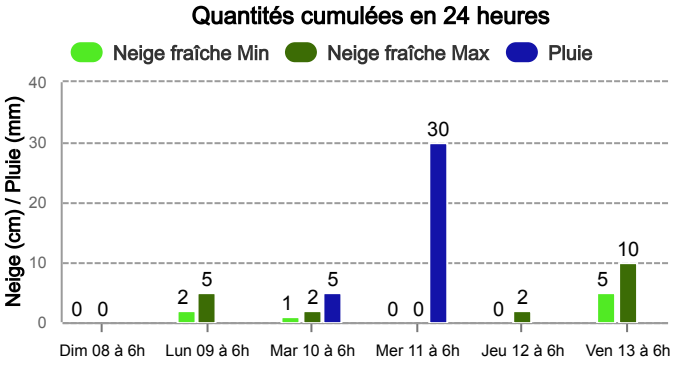

Tendance du vendredi 13 février

2

Indice de risque limité

En baisse pour le risque de départs spontanés. Risque accidentel probablement en hausse à partir de vendredi soir.

Pour consulter la vigilance en cours, veuillez vous rendre sur le site https://vigilance.meteofrance.fr/fr

Météo-France - 73 avenue de Paris, 94165 Saint-Mandé cedex - Contact : contact@meteo.fr

Rédigé par Météo-France avec la contribution des observateurs du réseau nivo-météorologiques. Partenariat : ANMSM (Maires de Stations de Montagne), DSF (Domaines Skiables de France), ADSP (Directeurs de Pistes et de la Sécurité des Stations de Sports d'Hiver) et autres acteurs de la montagne.

Bulletin neige & avalanches par téléphone au 0 892 68 10 20 Service 0,35 € / min + prix appel

RÉPUBLIQUE FRANÇAISE
Liberté Égalité Fraternité

METEO FRANCE
À VOS CÔTÉS, DANS UN CLIMAT QUI CHANGE

Bulletin d'estimation du risque d'avalanche

(valable en dehors des pistes balisées et ouvertes)

MASSIF : Capcir Puymorens

Rédigé le mercredi 11 février 2026 à 16h

Conditions nivo-météo des 7 derniers jours

	jeu. 05/02				ven. 06/02				sam. 07/02				dim. 08/02				lun. 09/02				mar. 10/02				mer. 11/02			
	03h	09h	15h	21h	03h	09h	15h	21h	03h	09h	15h	21h	03h	09h	15h	21h	03h	09h	15h	21h	03h	09h	15h	21h	03h	09h	15h	21h
Météo																												
Vent (km/h)	65	80	75	55	40	25	25	30	30	20	20	50	55	30	55	50	55	40	60	65	70	70	80	85	65	60	55	65
à 3000m	↑	↑	↑	↗	→	→	→	↘	↘	↘	↘	→	↗	↓	↘	↘	↘	→	↘	→	↘	→	→	↘	→	↘	→	↗
Vent (km/h)	45	60	55	40	25	15	15	20	20	15	15	40	45	20	35	35	35	20	30	35	35	40	50	60	50	50	35	45
à 2000m	→	↑	↑	↗	→	→	→	↘	↑	↘	↘	→	↑	↘	↘	↘	↘	↗	↘	↗	↗	→	→	↘	→	↘	→	→

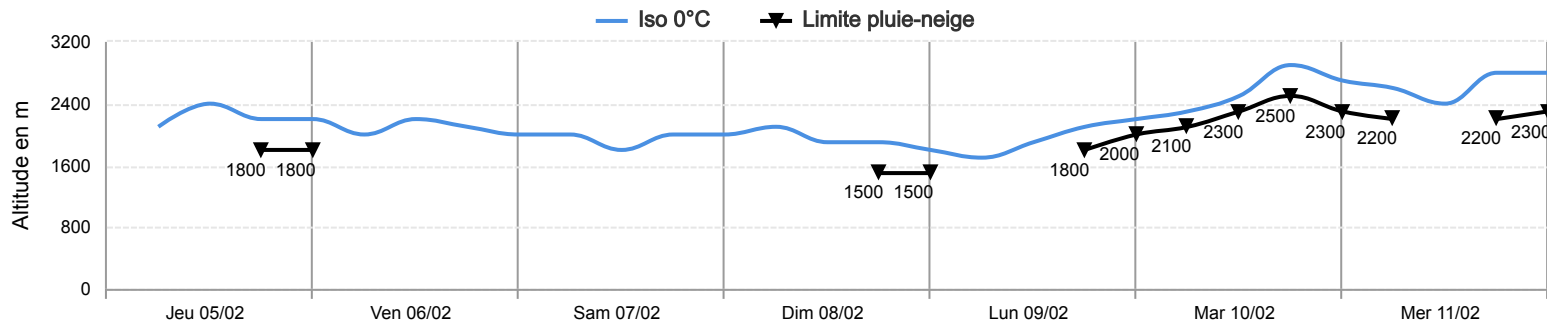

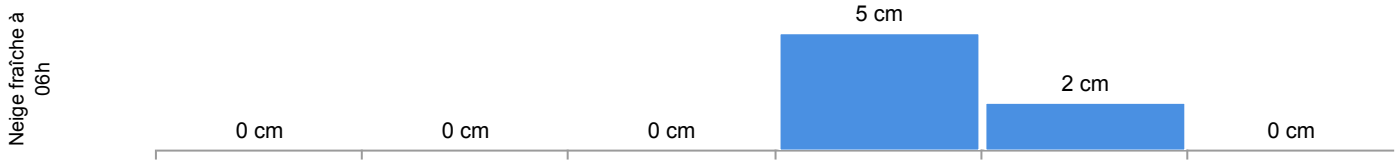

Risque d'avalanche	jeu. 05/02	ven. 06/02	sam. 07/02	dim. 08/02	lun. 09/02	mar. 10/02	mer. 11/02
	3	2	2	2	2	4	4

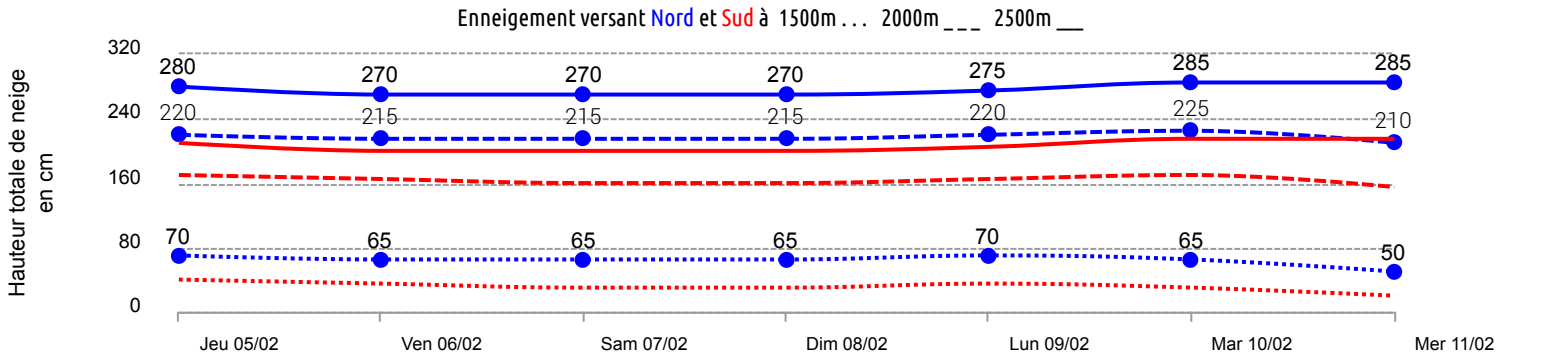

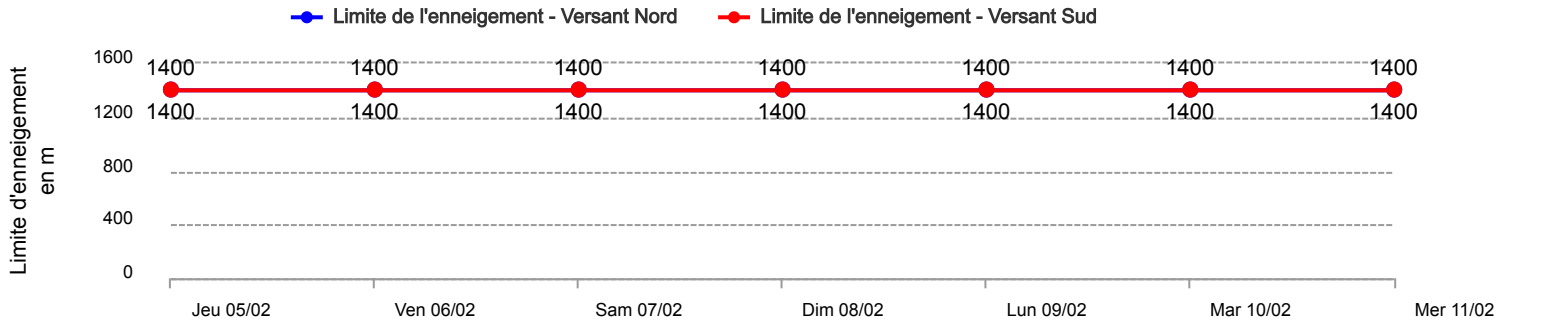

Pour consulter la vigilance en cours, veuillez vous rendre sur le site https://vigilance.meteofrance.fr/fr

Météo-France - 73 avenue de Paris, 94165 Saint-Mandé cedex - Contact : contact@meteo.fr

Bulletin neige & avalanches par téléphone au

0 892 68 10 20 Service 0,35 € / min + prix appel

Rédigé par Météo-France avec la contribution des observateurs du réseau nivo-météorologiques. Partenariat : ANMSM (Maires de Stations de Montagne), DSF (Domaines Skiables de France), ADSP (Directeurs de Pistes et de la Sécurité des Stations de Sports d'Hiver) et autres acteurs de la montagne.