Bulletin d'estimation du risque d'avalanche
(valable en dehors des pistes balisées et ouvertes)
MASSIF : Chartreuse

Rédigé le mercredi 11 février 2026 à 16h

Estimation des risques pour le : JEUDI 12 FÉVRIER

NEIGE FRAICHE S'ÉPAISSISSANT EN ALTITUDE, INSTABILITÉ DEVENANT MARQUÉE EN HAUT DU MASSIF...

3

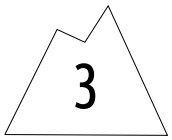

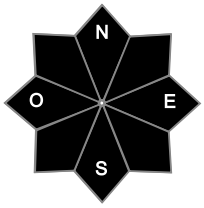

Altitude+ couloirs

Indice de risque marqué.

Départs spontanés : Surtout jeudi en journée, en pentes raides/couloirs d'altitude nombreuses avalanches de taille moyenne, parfois une cassure plus épaisse sous le vent de Nord-Ouest...

Déclenchements provoqués : Nombreuses plaques (instables) en formation jeudi sous le vent d'Ouest puis Nord-Ouest, notamment au dessus de 1600/1700m...

Indices de risque : 5 très fort - 4 fort - 3 marqué - 2 limité - 1 faible -- En noir : les pentes les plus dangereuses

Stabilité du manteau neigeux

Situation avalancheuse typique : neige fraîche avalanches de fond

Nouveau passage pluvieux mercredi soir, puis retour de la neige à partir de 1300m jeudi matin. Cumuls conséquents en altitude (20 puis 40 cm), avec un fort vent de Nord-Ouest.

Départs spontanés : Plus bas que 1500/1700m, quelques avalanches humides ou de fond/glissement peuvent partir, là où le manteau a été humidifié jusqu'à la base par la pluie des derniers jours. En altitude au-dessus de 1700m environ, on attend des avalanches de surface au fil des chutes de neige et du vent, parfois de taille moyenne. Elles seront plus fréquentes en faces Nord à Est, dans les couloirs chargés par le vent de Sud-Ouest puis Nord-Ouest...

Déclenchements provoqués : Au dessus de 1600/1700m environ le risque accidentel devrait s'accentuer jeudi au fil des chutes de neige plus ventées et froides... Formation de plaques instables au passage d'un skieur, parfois dès les sorties de forêt, assez loin des crêtes, en pieds de barres par exemple. Cassures potentielles dépassant 50 cm l''après-midi. En contrebas (sous 1500m environ) neige plus humide, plutôt un risque de coulée ponctuelle sous les skis...

Qualité de la neige

Qualification de l'enneigement : L'enneigement s'est récemment dégradé aux basses altitudes, sous les sapins mais reste correct pour la saison dès la moyenne montagne et dans les combes Nord. Sur le haut du massif, l'enneigement s'améliore de manière hétérogène. Des combes se chargent généreusement, tandis que les pentes exposées au vent sont souvent pelées.

Limites skiables : Vers 1200/1400 m, sur les pistes forestières/clairières...

Qualité de la neige jeudi : La pluie remonte à nouveau temporairement jusqu'à 2000m mercredi soir, avant de s'abaisser vers 1300m en journée de jeudi. Sous 1500 / 1600m environ, neige récente humide, reposant sur une neige détrempée. Plus haut, couche de neige fraîche de plus en plus importante au fil de la journée, avec 30 à 40cm en fin de journée. Neige souvent ventée, certaines pentes sont pelées.

Aperçu météo pour le jeudi 12 février

	nuit	matin	après-midi	soir

Redoux temporaire mercredi soir, jeudi plus frais et très neigeux (20 puis 40 cm)... Forts vents de Sud-Ouest puis Nord-Ouest...

Pluie-Neige	1 600 m	1 200 m	1 300 m	1 100 m
Iso 0 °C	2 100 m	1 600 m	1 600 m	1 500 m
Vent 1500 m	↗ 70 km/h	→ 50 km/h	↘ 45 km/h	↘ 35 km/h
Vent 2000 m	↗ 85 km/h	→ 70 km/h	↘ 70 km/h	↘ 65 km/h

Épaisseur de neige hors-piste

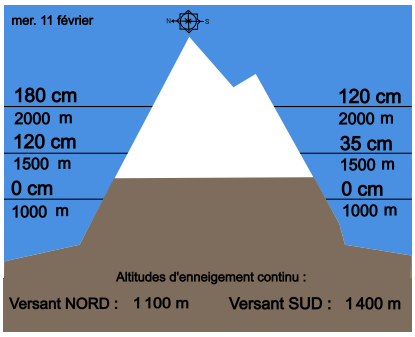

Précipitations à 1800 m

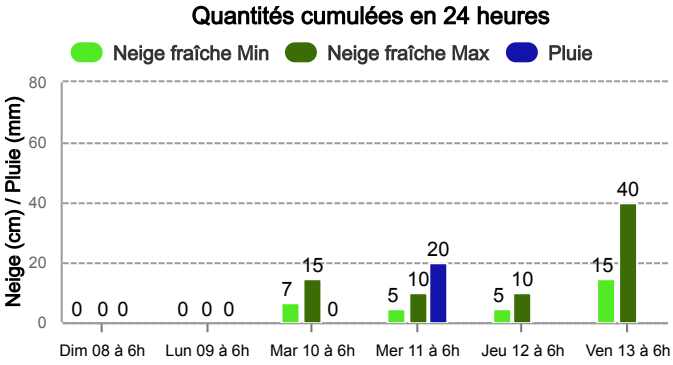

Tendance du vendredi 13 février

3 **Indice de risque marqué**

Vendredi, retour de conditions plus calmes et temporairement sèches.
Risque d'avalanche stationnaire ou en légère baisse
Plaques plus localisées vers les hautes crêtes, au soleil possible coulées/avalanches de neige fraîche...

Pour consulter la vigilance en cours, veuillez vous rendre sur le site https://vigilance.meteofrance.fr/fr

Météo-France - 73 avenue de Paris, 94165 Saint-Mandé cedex - Contact : contact@meteo.fr

Rédigé par Météo-France avec la contribution des observateurs du réseau nivo-météorologiques. Partenariat : ANMSM (Maires de Stations de Montagne), DSF (Domaines Skiables de France), ADSP (Directeurs de Pistes et de la Sécurité des Stations de Sports d'Hiver) et autres acteurs de la montagne.

Bulletin neige & avalanches par téléphone au **0 892 68 10 20** Service 0,35 € / min + prix appel

Bulletin d'estimation du risque d'avalanche

(valable en dehors des pistes balisées et ouvertes)

MASSIF : Chartreuse

Rédigé le mercredi 11 février 2026 à 16h

Conditions nivo-météo des 7 derniers jours

	jeu. 05/02				ven. 06/02				sam. 07/02				dim. 08/02				lun. 09/02				mar. 10/02				mer. 11/02			
	03h	09h	15h	21h	03h	09h	15h	21h	03h	09h	15h	21h	03h	09h	15h	21h	03h	09h	15h	21h	03h	09h	15h	21h	03h	09h	15h	21h
Météo																												
Vent (km/h)	35	45	65	50	60	35	30	20	15	15	5	5	15	20	15	10	15	30	35	35	50	40	50	70	65	65	65	100
à 2000m																												
Vent (km/h)	20	20	40	25	30	20	15	10	10	5	10	10	10	5	5	5	5	10	20	25	40	30	35	50	40	30	35	85
à 1500m																												

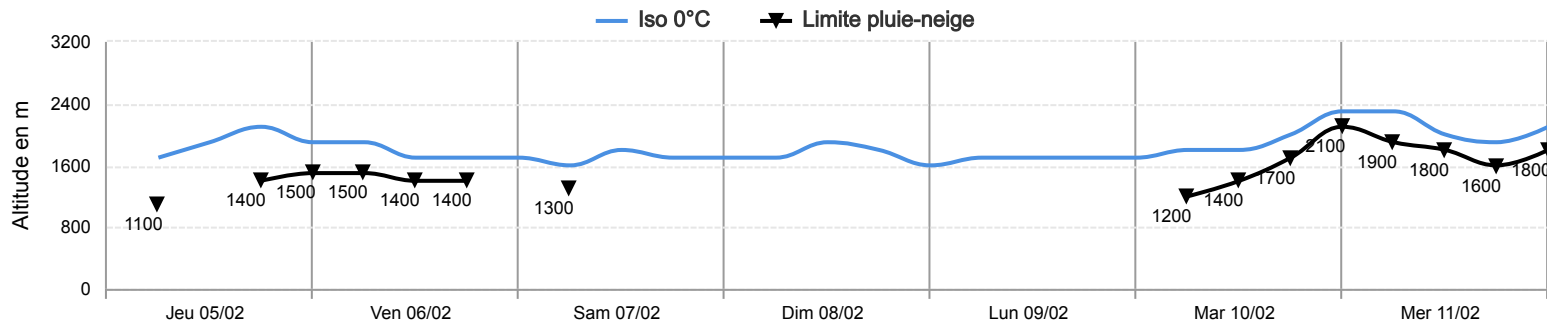

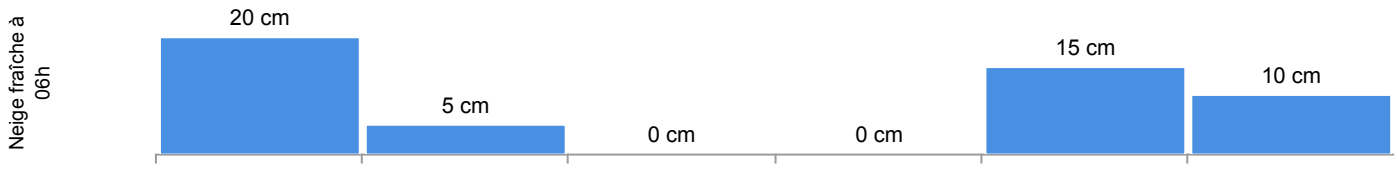

Risque d'avalanche	jeu. 05/02	ven. 06/02	sam. 07/02	dim. 08/02	lun. 09/02	mar. 10/02	mer. 11/02
	3	3	2	2	2	3	3

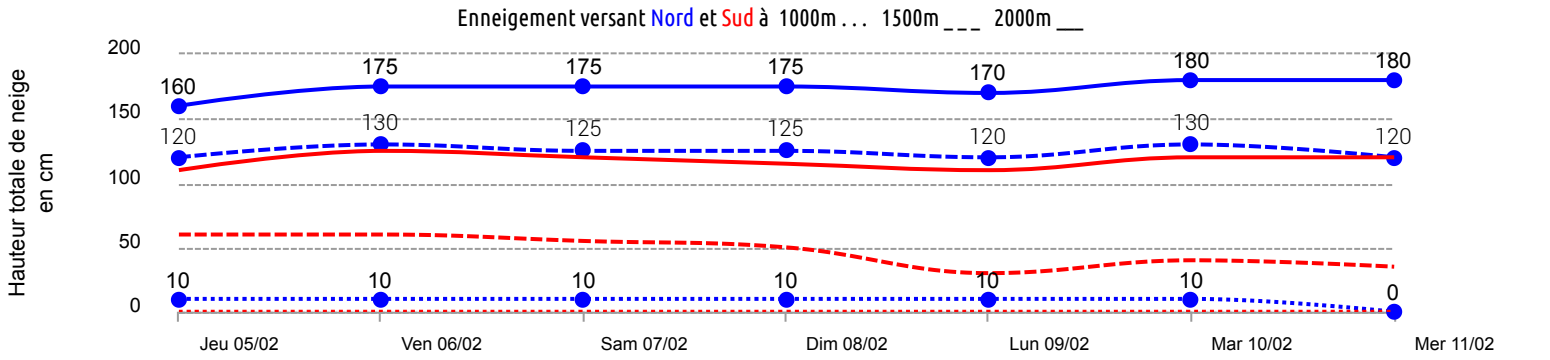

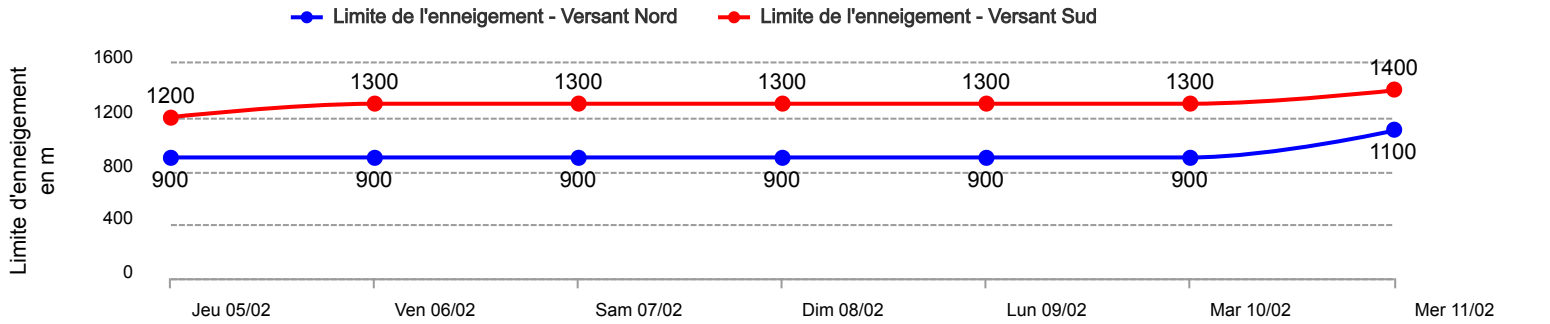

Pour consulter la vigilance en cours, veuillez vous rendre sur le site https://vigilance.meteofrance.fr/fr

Météo-France - 73 avenue de Paris, 94165 Saint-Mandé cedex - Contact : contact@meteo.fr

Bulletin neige & avalanches par téléphone au 0 892 68 10 20 Service 0,35 € / min + prix appel

Rédigé par Météo-France avec la contribution des observateurs du réseau nivo-météorologiques. Partenariat : ANMSM (Maires de Stations de Montagne), DSF (Domaines Skiables de France), ADSP (Directeurs de Pistes et de la Sécurité des Stations de Sports d'Hiver) et autres acteurs de la montagne.