# Bulletin d'estimation du risque d'avalanche

(valable en dehors des pistes balisées et ouvertes)

# MASSIF : Haut-Var Haut-Verdon

Rédigé le mercredi 11 février 2026 à 16h

## Estimation des risques pour le : JEUDI 12 FÉVRIER

**NEIGE PLUS ABONDANTE EN HAUT VERDON, MANTEAU NEIGEUX TRÈS INSTABLE EN ALTITUDE**

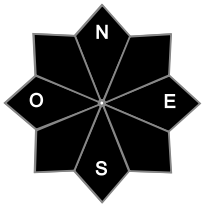


Indice de risque fort à l'ouest du massif, marqué à l'est.

**Départs spontanés :** Nombreuses avalanches au fil des chutes, de grande taille sur le Haut Verdon

**Déclenchements provoqués :** Instabilités faciles à déclencher et parfois très volumineuses sur le Haut Verdon

Indices de risque : 5 très fort - 4 fort - 3 marqué - 2 limité - 1 faible -- En noir : les pentes les plus dangereuses

## Stabilité du manteau neigeux

**Situation avalancheuse typique :** neige fraîche neige ventée

**Déclenchements provoqués** :
**Haut Verdon :** le manteau neigeux est faiblement stabilisé dans la plupart des pentes situées au-dessus de 2000 m d'altitude environ. Les abondantes chutes de neige entre mercredi soir et jeudi mi-journée entretiennent cette forte instabilité. Plaques souvent d'aspect poudreux, déclenchables par un seul skieur, mobilisant la neige tombée depuis mardi. Elles engendrent des avalanches de taille moyenne (taille 2), parfois grande et avec une cassure linéaire (taille 3) dans les zones de plus forte accumulation par le vent. En orientations ouest, nord et est d'altitude supérieure à 2200 m environ, des avalanches de grande taille sont plus probables, et une avalanche de très grande taille (taille 4) n'est pas exclue.
L'épaisse couche de neige récente, fortement travaillée par le vent tempétueux de nord-ouest, repose en effet sur des couches fragiles persistantes, à la base du manteau neigeux.
**Haut Var :** manteau neigeux modérément stabilisé en altitude. Instabilités possibles en toute orientation sous forme de plaques plus souvent d'aspect dur, et identifiables. Elles mobilisent la neige récente fortement ventée et engendrent des avalanches de taille moyenne. Une avalanche de grande taille n'est pas exclue en orientation ouest, nord ou est d'altitude. Les quantités de neige récente sont beaucoup moins importantes que dans le Haut Verdon. Cette neige récente est en outre fortement travaillée par le vent, qui souffle en tempête au passage de la tempête Nils.

**Départs spontanés** : départs de neige fraîche de taille moyenne, parfois grande en altitude dans le Haut Verdon, pendant les chutes et peu après, sous l'effet du vent de nord-ouest. Une avalanche de très grande taille approchant les fonds de vallée n'est pas exclue dans le Haut Verdon. Départs également en neige récente humide sous les éclaircies l'après-midi, mais restant ponctuels et de taille petite à moyenne.

## Qualité de la neige

**Enneigement** abondant, très excédentaire pour un mois de février.
Données observées vers 2000 m en fond de vallon : 150 à 170 cm.

**Enneigement skiable** dès 1400 m, parfois 1200 m.

**État de la neige en surface** : neige fraîche plus abondante sur le Haut Verdon à partir de 1600/1800 m. Elle est néanmoins tombée sur un manteau neigeux humide en surface en tout orientation jusque 2000 m au moins. Cette neige est fortement densifiée par le vent de nord-ouest à haute altitude, notamment dans le Haut Var.

## Aperçu météo pour le jeudi 12 février

| | nuit | matin | après-midi | soir |
|---|---|---|---|---|
| Pluie-Neige | 1 400 m | 1 300 m | 1 300 m | 1 300 m |
| Iso 0 °C | 1 900 m | 1 700 m | 1 800 m | 1 700 m |
| Vent 2000 m | 80 km/h | 90 km/h | 120 km/h | 60 km/h |
| Vent 3000 m | 80 km/h | 100 km/h | 140 km/h | 100 km/h |

Tempête Nils : abondantes chutes de neige jusqu'en mi-journée sur le Haut Verdon, violentes rafales dans le Haut Var, jusqu'à 150 km/h en crêtes

## Épaisseur de neige hors-piste

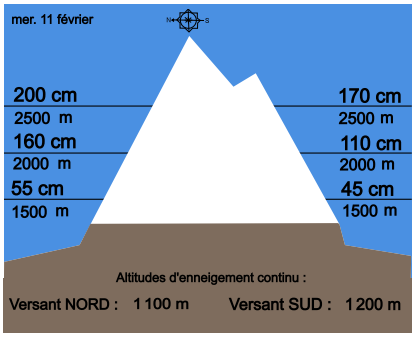


## Précipitations à 1800 m

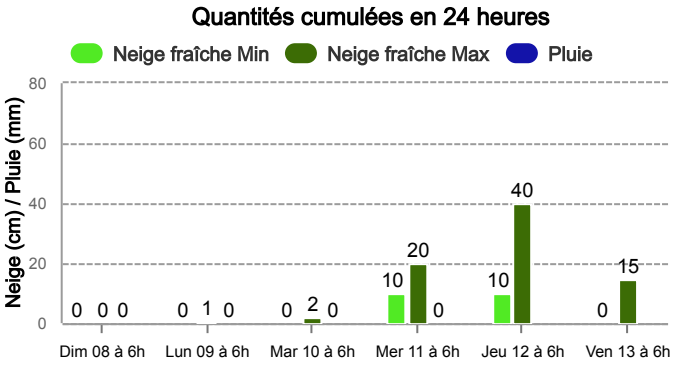


## Tendance du vendredi 13 février

**Indice de risque marqué**

Tendance à la baisse. Risque marqué en altitude

Pour consulter la vigilance en cours, veuillez vous rendre sur le site https://vigilance.meteofrance.fr/fr

Météo-France - 73 avenue de Paris, 94165 Saint-Mandé cedex - Contact : contact@meteo.fr

Rédigé par Météo-France avec la contribution des observateurs du réseau nivo-météorologiques. Partenariat : ANMSM (Maires de Stations de Montagne), DSF (Domaines Skiables de France), ADSP (Directeurs de Pistes et de la Sécurité des Stations de Sports d'Hiver) et autres acteurs de la montagne.

Bulletin neige & avalanches par téléphone au
0 892 68 10 20 Service 0,35 € / min + prix appel

# Bulletin d'estimation du risque d'avalanche

(valable en dehors des pistes balisées et ouvertes)

# MASSIF : Haut-Var Haut-Verdon

Rédigé le mercredi 11 février 2026 à 16h

## Conditions nivo-météo des 7 derniers jours

| | jeu. 05/02 | | | | ven. 06/02 | | | | sam. 07/02 | | | | dim. 08/02 | | | | lun. 09/02 | | | | mar. 10/02 | | | | mer. 11/02 | | | |
|---|---|---|---|---|---|---|---|---|---|---|---|---|---|---|---|---|---|---|---|---|---|---|---|---|---|---|---|---|
| | 03h | 09h | 15h | 21h | 03h | 09h | 15h | 21h | 03h | 09h | 15h | 21h | 03h | 09h | 15h | 21h | 03h | 09h | 15h | 21h | 03h | 09h | 15h | 21h | 03h | 09h | 15h | 21h |
| Météo | | | | | | | | | | | | | | | | | | | | | | | | | | | | |
| Vent (km/h) | 35 | 30 | 40 | 50 | 50 | 45 | 45 | 30 | 35 | 15 | 15 | 10 | 15 | 30 | 30 | 25 | 15 | 15 | 20 | 30 | 30 | 35 | 50 | 65 | 100 | 110 | 60 | 70 |
| à 3000m | | | | | | | | | | | | | | | | | | | | | | | | | | | | |
| Vent (km/h) | 15 | 15 | 20 | 20 | 25 | 35 | 35 | 20 | 20 | 10 | 10 | 10 | 10 | 15 | 20 | 20 | 10 | 5 | 15 | 10 | 10 | 15 | 20 | 20 | 20 | 20 | 30 | 40 |
| à 2000m | | | | | | | | | | | | | | | | | | | | | | | | | | | | |

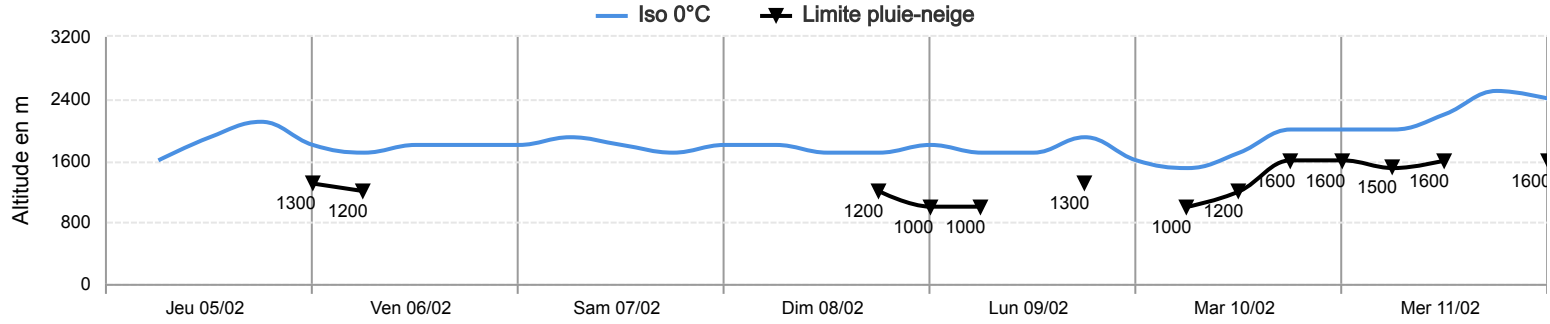





| Risque d'avalanche | jeu. 05/02 | ven. 06/02 | sam. 07/02 | dim. 08/02 | lun. 09/02 | mar. 10/02 | mer. 11/02 |
|---|---|---|---|---|---|---|---|
| | 3 | 4 | 3 | 3 | 3 | 3 | 3 |

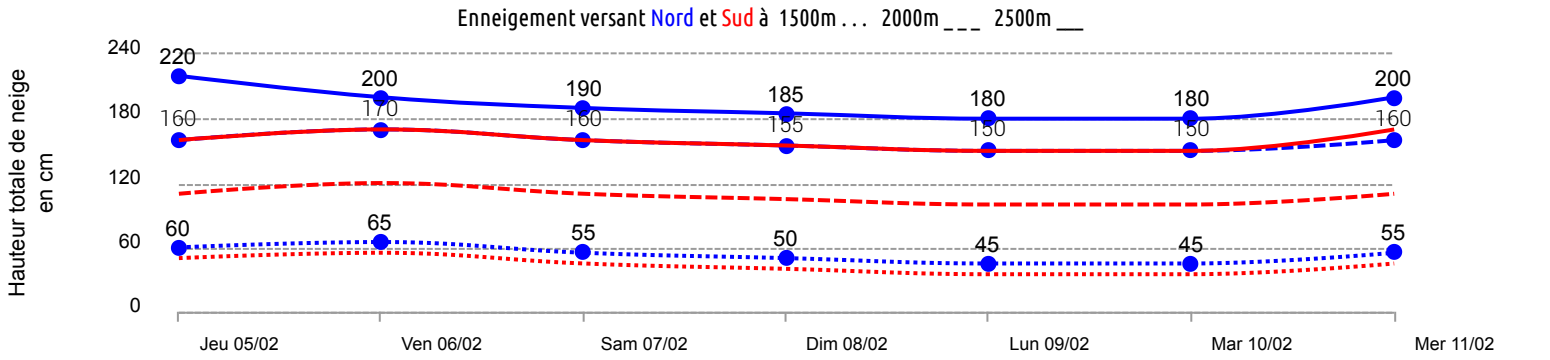


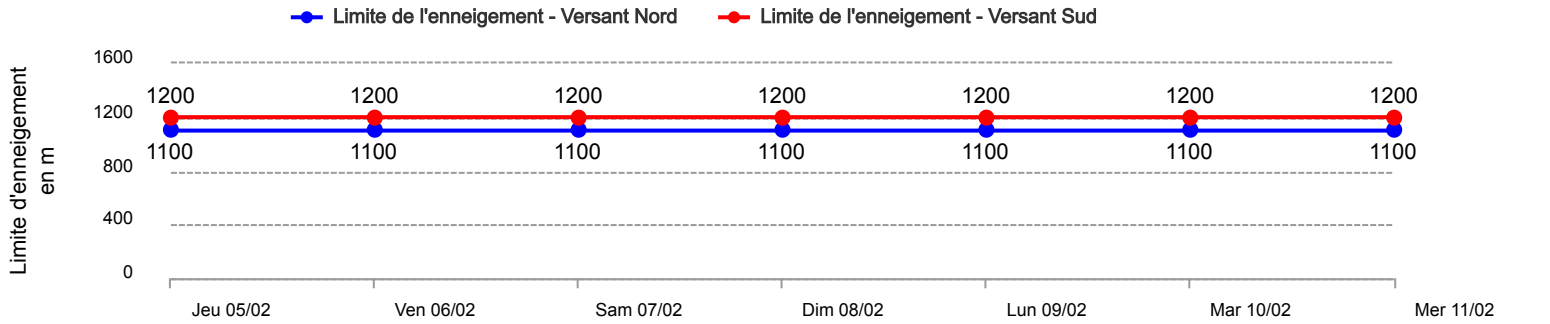


Pour consulter la vigilance en cours, veuillez vous rendre sur le site https://vigilance.meteofrance.fr/fr


Météo-France - 73 avenue de Paris, 94165 Saint-Mandé cedex - Contact : contact@meteo.fr


Bulletin neige & avalanches par téléphone au

0 892 68 10 20 Service 0,35 € / min + prix appel


Rédigé par Météo-France avec la contribution des observateurs du réseau nivo-météorologiques. Partenariat : ANMSM (Maires de Stations de Montagne), DSF (Domaines Skiables de France), ADSP (Directeurs de Pistes et de la Sécurité des Stations de Sports d'Hiver) et autres acteurs de la montagne.