Bulletin d'estimation du risque d'avalanche

(valable en dehors des pistes balisées et ouvertes)

MASSIF : Mercantour

Rédigé le mercredi 11 février 2026 à 16h

Estimation des risques pour le : JEUDI 12 FÉVRIER

MANTEAU NEIGEUX ÉPAIS MAIS PLUTÔT BIEN STABILISÉ

2

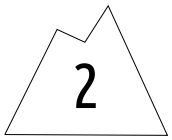

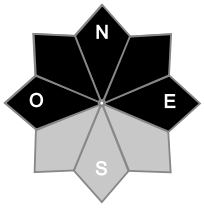

Indice de risque limité.

Départs spontanés : en neige humide, taille petite à moyenne

Déclenchements provoqués : instabilités superficielles dans la neige ventée

Indices de risque : 5 très fort - 4 fort - 3 marqué - 2 limité - 1 faible -- En noir : les pentes les plus dangereuses

Stabilité du manteau neigeux

Situation avalancheuse typique : neige ventée neige humide

Déclenchements provoqués : manteau neigeux encore modérément stabilisé dans de rares pentes d'altitude. Instabilités plus fréquentes dans la Haute Tinée, et parfois déclenchables par un seul skieur. Ces instabilités sont plus fréquentes en orientations ouest, nord et est d'altitude supérieure à 2200 m. Elle se présentent sous forme de plaques dures plutôt bien identifiables, qui ne mobilisent que la neige récente ventée, et engendrent des avalanches de taille petite à moyenne (taille 1 à 2). Une avalanche de très grande taille (taille 3) n'est pas exclue en orientation ouest, nord ou est. Ailleurs, côté Vésubie et Roya, les instabilités sont plus rares.
La tempête Nils favorise un fort transport de neige par le vent, surtout en Haute Tinée. Ces instabilités restent superficielles : les couches fragiles persistantes à la base du manteau neigeux sont généralement bien enfouies, et leur sollicitation peu probable par faible surcharge.

Départs spontanés : départs de neige humide parfois de taille moyenne. Le coup de foehn lié à la tempête Nils favorise une humidification du manteau neigeux, encore particulièrement épais en moyenne montagne.

Qualité de la neige

Enneigement abondant, très excédentaire pour un mois de février.
Données observées récentes : au-dessus de Valdeblore à 2500 m, 210 cm en versant nord, 170 cm en versant sud. Vers Cstérino : 195 cm à 2000 m, 100 cm à 1500 m. Vers Isola 2000 : 133 cm à 1900 m.

Enneigement skiable dès 1200 m sur terrains favorables.

État de la neige en surface : les quelques cm en Haute Tinée sont rapidement densifiés par le vent, comme sur le reste du massif où elle est parfois lustrée par le foehn. Humidification l'après-midi au soleil, localement profonde sous 2000 m.

Aperçu météo pour le jeudi 12 février

	nuit	matin	après-midi	soir

Tempête Nils : violentes rafales en Haute Tinée, jusqu'à 150 km/h sur les crêtes

Pluie-Neige	1 500 m			
Iso 0 °C	1 900 m	1 900 m	1 900 m	2 000 m
Vent 2000 m	↘ 40 km/h	↘ 50 km/h	↘ 55 km/h	↘ 55 km/h
Vent 3000 m	→ 90 km/h	↘ 85 km/h	↘ 80 km/h	↘ 85 km/h

Épaisseur de neige hors-piste

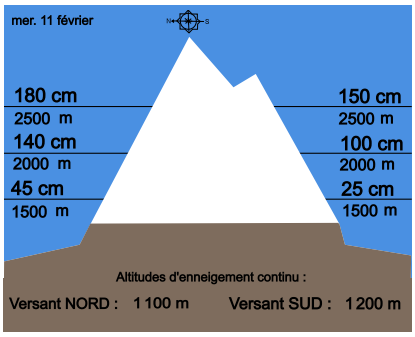

Précipitations à 1800 m

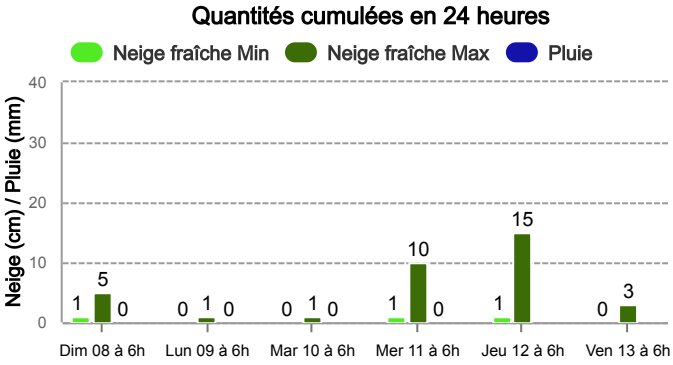

Tendance du vendredi 13 février

2

Indice de risque limité

Peu d'évolution. Maintien d'un risque limité

Pour consulter la vigilance en cours, veuillez vous rendre sur le site https://vigilance.meteofrance.fr/fr

Météo-France - 73 avenue de Paris, 94165 Saint-Mandé cedex - Contact : contact@meteo.fr

Rédigé par Météo-France avec la contribution des observateurs du réseau nivo-météorologiques. Partenariat : ANMSM (Maires de Stations de Montagne), DSF (Domaines Skiables de France), ADSP (Directeurs de Pistes et de la Sécurité des Stations de Sports d'Hiver) et autres acteurs de la montagne.

Bulletin neige & avalanches par téléphone au
0 892 68 10 20 Service 0,35 € / min + prix appel

Bulletin d'estimation du risque d'avalanche

(valable en dehors des pistes balisées et ouvertes)

MASSIF : Mercantour

Rédigé le mercredi 11 février 2026 à 16h

Conditions nivo-météo des 7 derniers jours

	jeu. 05/02				ven. 06/02				sam. 07/02				dim. 08/02				lun. 09/02				mar. 10/02				mer. 11/02			
	03h	09h	15h	21h	03h	09h	15h	21h	03h	09h	15h	21h	03h	09h	15h	21h	03h	09h	15h	21h	03h	09h	15h	21h	03h	09h	15h	21h
Météo																												
Vent (km/h)	35	40	40	45	40	45	40	30	35	15	15	15	20	15	25	25	15	15	25	30	35	40	50	65	80	75	50	75
à 3000m																												
Vent (km/h)	15	15	25	20	35	20	20	15	15	10	15	15	10	10	20	20	30	10	15	10	10	15	20	20	30	40	35	25
à 2000m																												

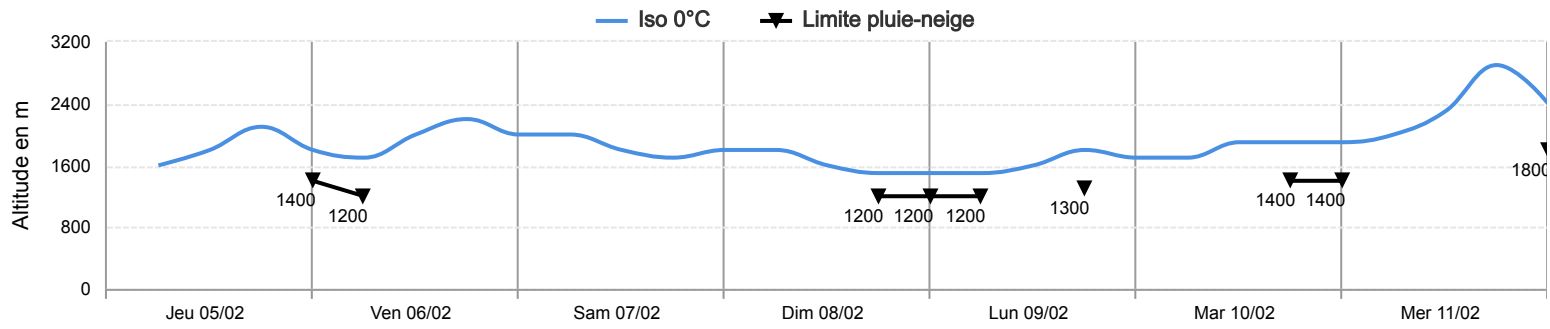

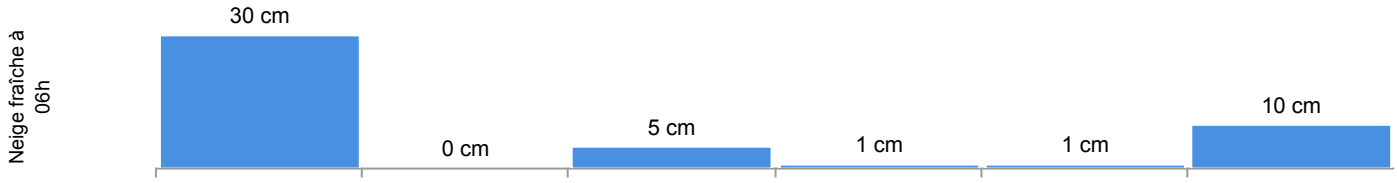

Risque d'avalanche	jeu. 05/02	ven. 06/02	sam. 07/02	dim. 08/02	lun. 09/02	mar. 10/02	mer. 11/02
	3	4	3	3	3	3	3

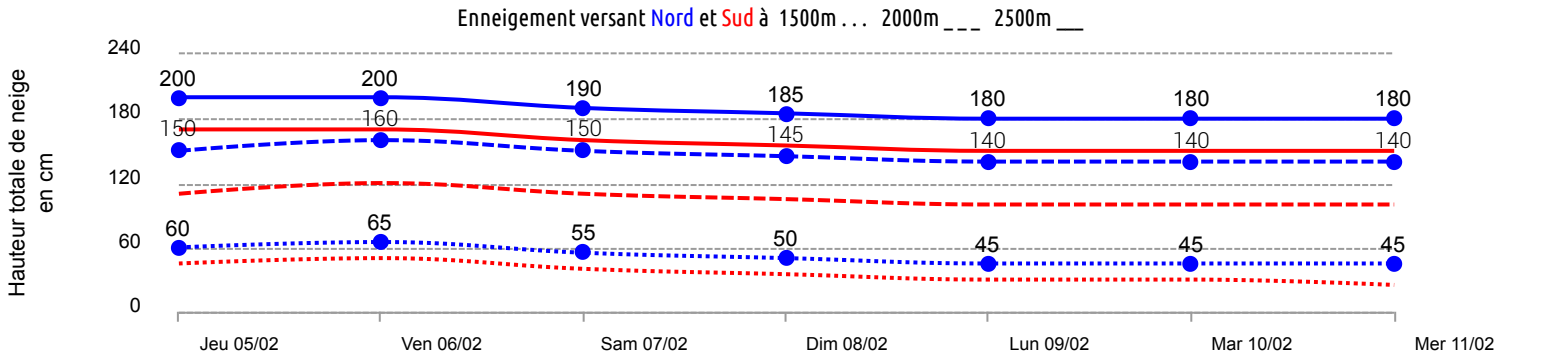

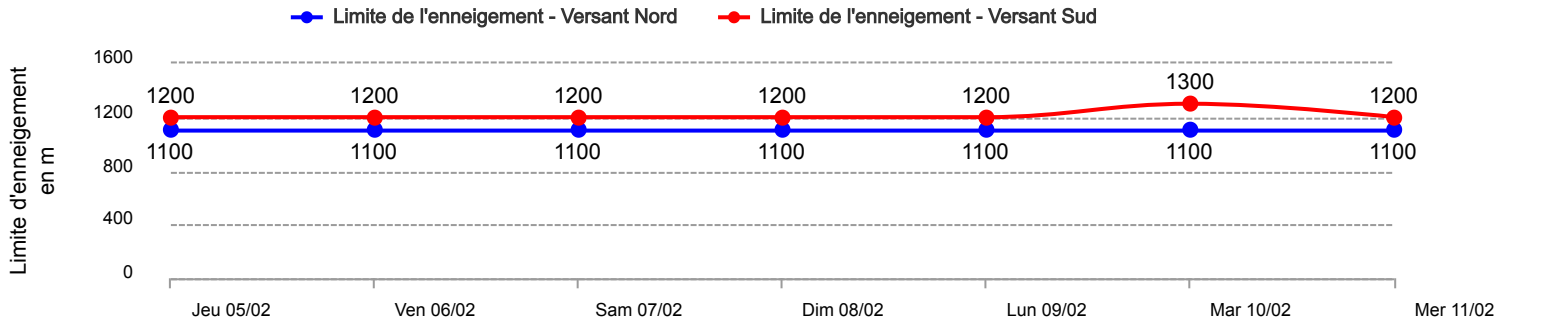

Pour consulter la vigilance en cours, veuillez vous rendre sur le site https://vigilance.meteofrance.fr/fr

Météo-France - 73 avenue de Paris, 94165 Saint-Mandé cedex - Contact : contact@meteo.fr

Bulletin neige & avalanches par téléphone au 0 892 68 10 20 Service 0,35 € / min + prix appel

Rédigé par Météo-France avec la contribution des observateurs du réseau nivo-météorologiques. Partenariat : ANMSM (Maires de Stations de Montagne), DSF (Domaines Skiables de France), ADSP (Directeurs de Pistes et de la Sécurité des Stations de Sports d'Hiver) et autres acteurs de la montagne.