Bulletin d'estimation du risque d'avalanche

(valable en dehors des pistes balisées et ouvertes)

MASSIF : Beaufortain

Rédigé le mercredi 11 février 2026 à 17h

Estimation des risques pour le : JEUDI 12 FÉVRIER

RISQUE MAXIMAL. CUMULS DE NEIGE HORS NORMES. GRANDES A TRÈS GRANDES AVALANCHES.

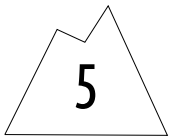

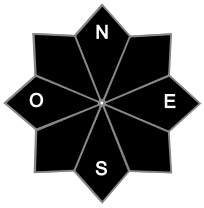

Indice de risque très fort.

Départs spontanés : GRANDES A TRÈS GRANDES AVALANCHES TOUTE LA JOURNÉE.

Déclenchements provoqués : RISQUE MAXIMAL. TOUS LES VERSANTS.

Indices de risque : 5 très fort - 4 fort - 3 marqué - 2 limité - 1 faible -- En noir : les pentes les plus dangereuses

Vigilance orange avalanches en cours ou prévue sur le massif

Stabilité du manteau neigeux

Situation avalancheuse typique :

neige fraîche

couche fragile persistante

SITUATION CRITIQUE. RISQUE MAXIMAL.

Départs spontanés : cumuls de neige fraiche hors normes avec entre 100 et 150 cm accumulés depuis le début de la séquence. Très forte activité naturelle à prévoir, tout au long de la journée. Des grandes à très grandes avalanches sont possibles au départ des pentes d'altitude. **GROS VOLUMES MOBLISÉS, AVALANCHES pouvant atteindre LEUR EMPRISE MAXIMALE CONNUE.**

Déclenchements provoqués : risque accidentel maximal. Instabilités généralisées, fortes propagations, gros volumes mobilisables, même en terrain peu raides.

Qualité de la neige

Enneigement : Un peu en dessous des normales de saison mais les chutes qui débutent ce mardi vont améliorer nettement l'enneigement au dessus de 1600m, en dessous la pluie attendue va bien dégrader le manteau.

Limite skiable : Les versants froids voyant pas ou peu le soleil ont gardé de la neige à basse altitude, skiable sur l'herbe ou sur pistes forestières dès 900/1000m. Sous bois skiables dès 1200m. En versant sud skiable dès 1300/1400m en prairies pas trop raides, 1600/1700m en Sud raide.

Qualité de la neige : en basse montagne, la neige est trempée, en moyenne montagne, la neige est humide jusqu'à ~1800 m. Plus haut, gros cumuls de neige fraîche avec 1/1.5 m atteint d'ici la fin de l'épisode.

Aperçu météo pour le jeudi 12 février

Episode tempétueux remarquable : neige forte continue et vent fort.

	nuit	matin	après-midi	soir
Pluie-Neige	1 400 m	1 200 m	1 300 m	1 100 m
Iso 0 °C	1 900 m	1 600 m	1 500 m	1 500 m
Vent 2000 m	45 km/h	55 km/h	45 km/h	40 km/h
Vent 3000 m	70 km/h	70 km/h	65 km/h	50 km/h

Épaisseur de neige hors-piste

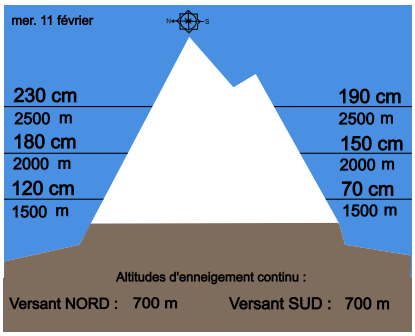

Précipitations à 1800 m

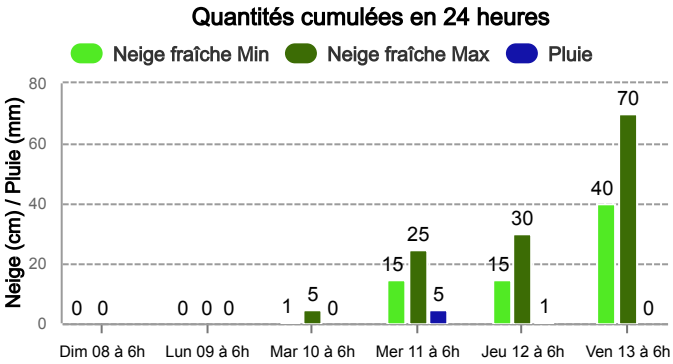

Tendance du vendredi 13 février

Indice de risque fort

Risque accidentel demeurant maximal : l'épaisse couche de neige récente n'est pas stabilisé. Les départs spontanés deviennent plus rares. Grandes avalanches possibles, même à distance.

Pour consulter la vigilance en cours, veuillez vous rendre sur le site https://vigilance.meteofrance.fr/fr

Météo-France - 73 avenue de Paris, 94165 Saint-Mandé cedex - Contact : contact@meteo.fr

Rédigé par Météo-France avec la contribution des observateurs du réseau nivo-météorologiques. Partenariat : ANMSM (Maires de Stations de Montagne), DSF (Domaines Skiables de France), ADSP (Directeurs de Pistes et de la Sécurité des Stations de Sports d'Hiver) et autres acteurs de la montagne.

Bulletin neige & avalanches par téléphone au

0 892 68 10 20 Service 0,35 € / min + prix appel

RÉPUBLIQUE FRANÇAISE
Liberté Égalité Fraternité

METEO FRANCE
À VOS CÔTÉS, DANS UN CLIMAT QUI CHANGE

Bulletin d'estimation du risque d'avalanche
(valable en dehors des pistes balisées et ouvertes)

MASSIF : Beaufortain

Rédigé le mercredi 11 février 2026 à 17h

Conditions nivo-météo des 7 derniers jours

	jeu. 05/02				ven. 06/02				sam. 07/02				dim. 08/02				lun. 09/02				mar. 10/02				mer. 11/02			
	03h	09h	15h	21h	03h	09h	15h	21h	03h	09h	15h	21h	03h	09h	15h	21h	03h	09h	15h	21h	03h	09h	15h	21h	03h	09h	15h	21h
Météo																												
Vent (km/h)	30	25	25	30	40	35	25	20	15	10	5	5	15	20	20	20	20	15	20	25	30	35	45	55	60	55	45	45
à 3000m																												
Vent (km/h)	15	15	15	25	25	20	15	10	5	5	0	0	10	15	10	10	10	10	10	10	15	20	25	35	40	40	30	30
à 2000m																												

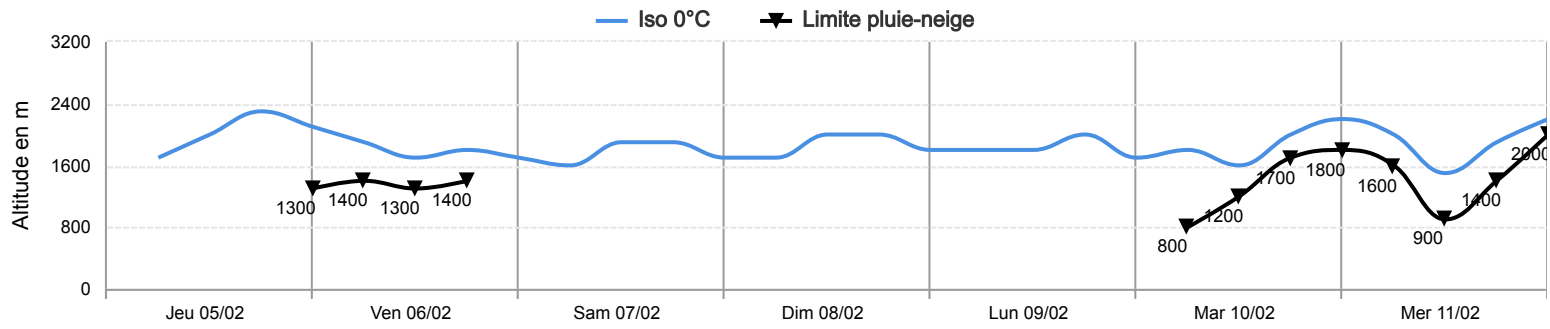

Risque d'avalanche	jeu. 05/02	ven. 06/02	sam. 07/02	dim. 08/02	lun. 09/02	mar. 10/02	mer. 11/02
	2	3	3	2	2	3	4

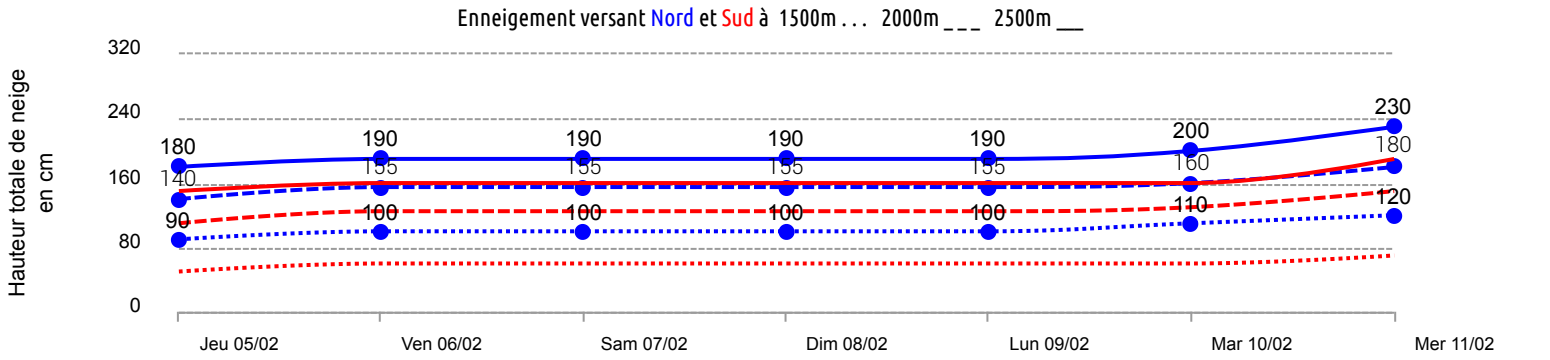

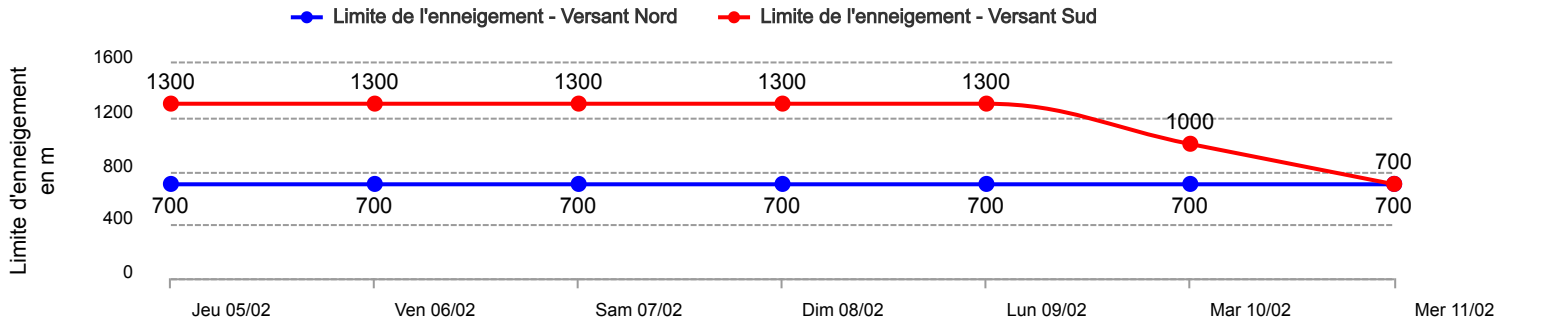

Pour consulter la vigilance en cours, veuillez vous rendre sur le site https://vigilance.meteofrance.fr/fr

Météo-France - 73 avenue de Paris, 94165 Saint-Mandé cedex - Contact : contact@meteo.fr

Rédigé par Météo-France avec la contribution des observateurs du réseau nivo-météorologiques. Partenariat : ANMSM (Maires de Stations de Montagne), DSF (Domaines Skiables de France), ADSP (Directeurs de Pistes et de la Sécurité des Stations de Sports d'Hiver) et autres acteurs de la montagne.

Bulletin neige & avalanches par téléphone au
0 892 68 10 20 Service 0,35 € / min + prix appel