Bulletin d'estimation du risque d'avalanche

(valable en dehors des pistes balisées et ouvertes)

MASSIF : Cinto Rotondo

Rédigé le mercredi 11 février 2026 à 17h

Estimation des risques pour le : JEUDI 12 FÉVRIER

POURSUITE DES CHUTES DE NEIGE, COUCHE RÉCENTE INSTABLE ET FORMATION DE NOUVELLES PLAQUES PAR LE VENT

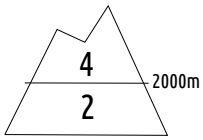

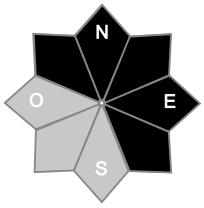

Au-dessus de 2000m indice de risque fort, plus bas indice limité.

Départs spontanés : Avalanches de neige fraîche de taille moyenne à grande au-dessus de 2000 m

Déclenchements provoqués : Formation de nouvelles plaques par le vent en altitude, facilement déclenchables, s'ajoutant aux anciennes instabilités

Indices de risque : 5 très fort - 4 fort - 3 marqué - 2 limité - 1 faible -- En noir : les pentes les plus dangereuses

Stabilité du manteau neigeux

Situation avalancheuse typique : neige ventée

Déclenchements provoqués : Ce jeudi, les nouvelles chutes de neige transportées par le vent fort génèrent de nombreuses plaques au-dessus de 2000 m, souvent loin des crêtes, surtout dans les orientations Est. Elles s'ajoutent aux anciennes plaques, pas toujours bien stabilisées, qui persistent dans les versants Nord (présence de plusieurs couches fragiles plus ou moins enfouies). Localement, les volumes mobilisables peuvent être importants. En altitude, le passage d'un seul skieur suffit à déclencher une plaque. En dessous de 2000 à 2200 m, la vieille neige est bien tassée, les nouvelles plaques en neige fraîche sont peu épaisses et plus difficiles à solliciter.

Départs spontanés : Cette nuit de mercredi à jeudi, la pluie tombe temporairement jusque vers 2200 à 2300 m d'altitude, entrainant des coulées et avalanches de neige humide, généralement de taille moyenne (taille 2), localement de grande taille (taille 3) par humidification d'une sous-couche fragile persistante plus enfouie. Au-dessus de 2200 à 2300 m, les chutes de neige lourde et humide entrainent des coulées et avalanches de neige fraîche de taille moyenne, surtout dans les pentes raides. Pour la journée, la limite pluie-neige s'abaisse et les avalanches de neige fraîche deviennent possibles dès 1700 à 1800 m. De nombreuses avalanches de grande taille (taille 3) sont attendues dans les zones d'accumulation au-dessus de 2000 m.

Autres : Risque de glissade en neige dure ou glacée sur les crêtes et sommets balayés par le vent d'Ouest.

Qualité de la neige

Qualification de l'enneigement : L'enneigement est excellent pour la saison à toutes altitudes. On relève 2m83 sur la Maniccia à 2350 m dans le massif du Rotondo.

Limite d'enneigement skiable : vers 1500 m.

État de la neige : Avec les récentes pluies, la neige est devenue humide jusque vers 2000 à 2200 m environ, généralement portante (parfois soupe à basse altitude). En altitude, elle reste sèche, légère et profonde à l'abri du vent d'Ouest. On trouve localement des accumulations de neige roulée. La neige est très changeante (dure, carton, regelée) dans les secteurs ventés. Corniches et accumulations parfois volumineuses en place. Les crêtes et sommets, balayés par le vent d'Ouest, sont souvent durs et glacés.

Aperçu météo pour le jeudi 12 février

	nuit	matin	après-midi	soir
Pluie-Neige	2 000 m	1 500 m	1 400 m	1 400 m
Iso 0 °C	2 300 m	1 900 m	1 800 m	1 700 m
Vent 1500 m	→ 70 km/h	→ 100 km/h	→ 100 km/h	→ 100 km/h
Vent 3000 m	→ 80 km/h	→ 120 km/h	↘ 80 km/h	→ 80 km/h

Chutes de neige souvent sous forme de neige roulée, à partir de 2200 / 2300 m cette nuit, dès 1400 m en journée de jeudi.

Épaisseur de neige hors-piste

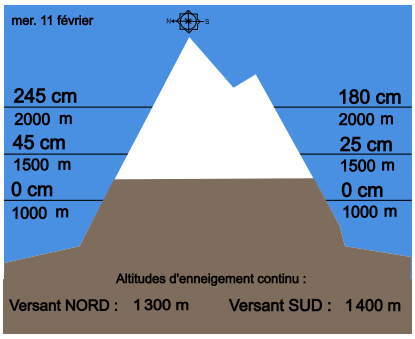

Précipitations à 1800 m

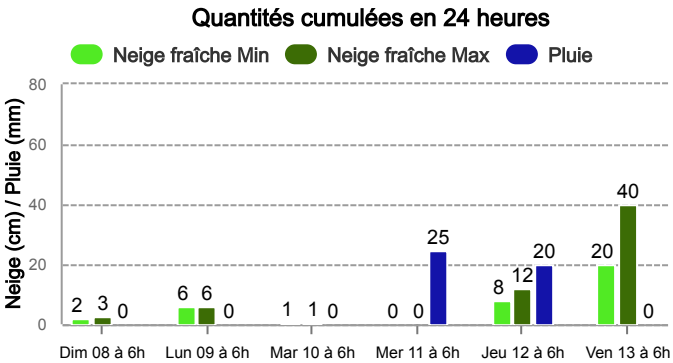

Tendance du vendredi 13 février

Indice de risque marqué

Accalmie temporaire : vent plus modéré et temps sec. Le risque de départ spontané est en nette baisse. Néanmoins, les instabilités persistent dans le manteau neigeux. Possible baisse vers un risque marqué (3/5).

Pour consulter la vigilance en cours, veuillez vous rendre sur le site https://vigilance.meteofrance.fr/fr

Météo-France - 73 avenue de Paris, 94165 Saint-Mandé cedex - Contact : contact@meteo.fr

Rédigé par Météo-France avec la contribution des observateurs du réseau nivo-météorologiques. Partenariat : ANMSM (Maires de Stations de Montagne), DSF (Domaines Skiables de France), ADSP (Directeurs de Pistes et de la Sécurité des Stations de Sports d'Hiver) et autres acteurs de la montagne.

Bulletin neige & avalanches par téléphone au

0 892 68 10 20 Service 0,35 € / min + prix appel

RÉPUBLIQUE FRANÇAISE
Liberté Égalité Fraternité

METEO FRANCE
À VOS CÔTÉS, DANS UN CLIMAT QUI CHANGE

Bulletin d'estimation du risque d'avalanche

(valable en dehors des pistes balisées et ouvertes)

MASSIF : Cinto Rotondo

Rédigé le mercredi 11 février 2026 à 17h

Conditions nivo-météo des 7 derniers jours

	jeu. 05/02				ven. 06/02				sam. 07/02				dim. 08/02				lun. 09/02				mar. 10/02				mer. 11/02			
	03h	09h	15h	21h	03h	09h	15h	21h	03h	09h	15h	21h	03h	09h	15h	21h	03h	09h	15h	21h	03h	09h	15h	21h	03h	09h	15h	21h
Météo																												
Vent (km/h)	35	50	45	65	100	85	80	65	65	45	60	45	65	15	20	20	15	10	15	20	30	25	40	60	80	100	100	90
à 3000m																												
Vent (km/h)	25	35	30	50	80	70	70	55	55	30	45	35	45	10	20	15	10	10	10	10	10	10	20	30	50	90	90	90
à 1500m																												

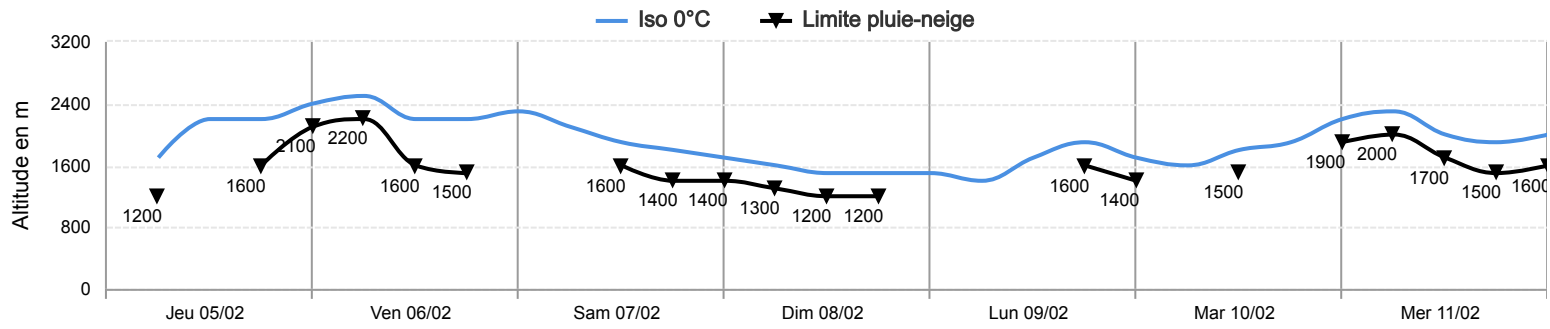

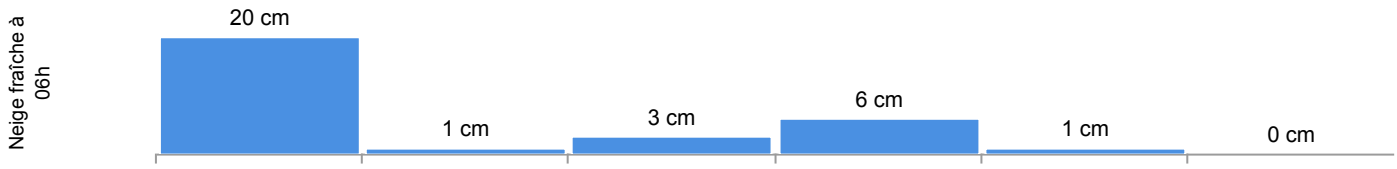

Risque d'avalanche	jeu. 05/02	ven. 06/02	sam. 07/02	dim. 08/02	lun. 09/02	mar. 10/02	mer. 11/02
	3	3	3	3	3	2	3

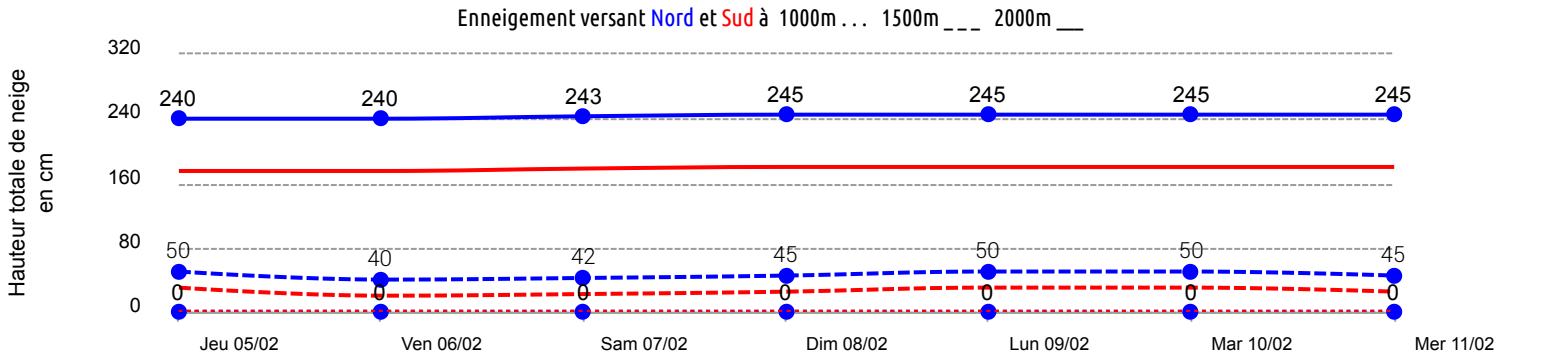

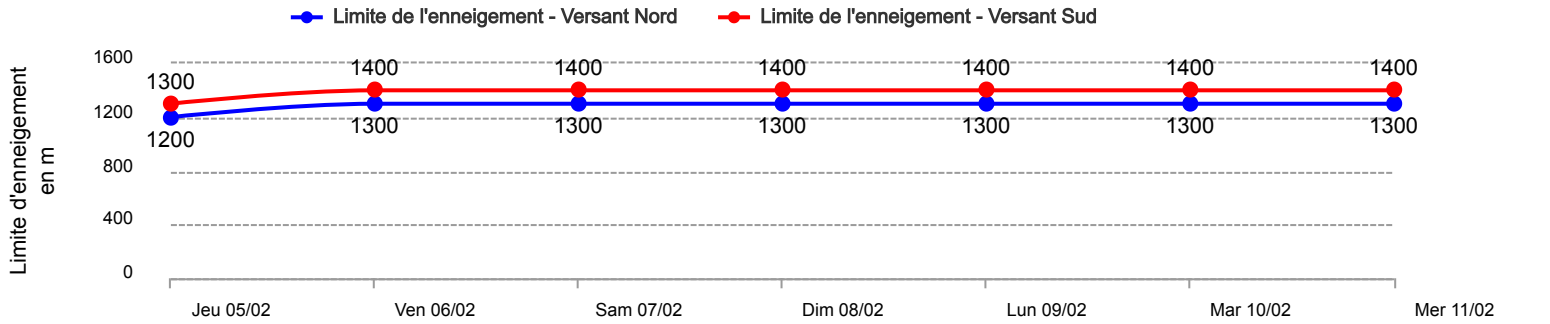

Pour consulter la vigilance en cours, veuillez vous rendre sur le site https://vigilance.meteofrance.fr/fr

Météo-France - 73 avenue de Paris, 94165 Saint-Mandé cedex - Contact : contact@meteo.fr

Rédigé par Météo-France avec la contribution des observateurs du réseau nivo-météorologiques. Partenariat : ANMSM (Maires de Stations de Montagne), DSF (Domaines Skiables de France), ADSP (Directeurs de Pistes et de la Sécurité des Stations de Sports d'Hiver) et autres acteurs de la montagne.

Bulletin neige & avalanches par téléphone au
0 892 68 10 20 Service 0,35 € / min + prix appel