Bulletin d'estimation du risque d'avalanche

(valable en dehors des pistes balisées et ouvertes)

MASSIF : Pelvoux

Rédigé le mercredi 11 février 2026 à 17h

Estimation des risques pour le : JEUDI 12 FÉVRIER

FORTE ACTIVITÉ AVALANCHEUSE NATURELLE - QUELQUES DÉPARTS DE GRANDE AMPLEUR ATTENDUS - VIGILANCE ORANGE AVALANCHES

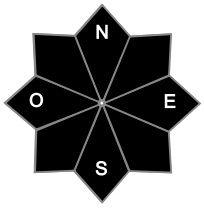

Indices de risque : 5 très fort - 4 fort - 3 marqué - 2 limité - 1 faible -- En noir : les pentes les plus dangereuses

Indice de risque fort.

Départs spontanés : nombreuses avalanches de neige fraîche pendant les chutes, départs parfois linéaires et de grande ampleur.

Déclenchements provoqués : nombreuses plaques épaisses.

Vigilance orange avalanches en cours ou prévue sur le massif

Stabilité du manteau neigeux

Situation avalancheuse typique : neige fraîche — couche fragile persistante

Départs spontanés : forte activité avalancheuse attendue, suite aux nouvelles chutes de neige qui se déposent sur un manteau neigeux encore peu stabilisé. Les avalanches de neige fraîche deviennent de plus en plus nombreuses pendant les chutes, avec des départs en poire ou linéaires emportant l'épaisse couche de neige récente, souvent sur une grande largeur. Avalanches fréquemment de taille moyenne ou grande (taille 2 ou 3). Quelques-unes peuvent être de grande ampleur et menacer certaines routes ou infrastructures de montagne, en particulier au-dessus de 1600/1700 m (très grandes avalanches, taille 4). Ponctuellement, ces très grandes avalanches parcourent un dénivelé important et risquent d'atteindre certains fonds de vallées à plus basse altitude.

Déclenchements provoqués : au-dessus de 1800/2000 m, les très nombreuses plaques dans la neige fraîche peuvent être déclenchées par le passage d'un seul skieur, mobilisant de très importants volumes de neige dans les pentes les plus chargées. Cassures épaisses et sur de grandes largeurs, notamment en cas de sollicitation de la couche fragile persistante enfouie.
Plus bas, le risque de déclencher une plaque est moins fort, car la neige récente est en partie humidifiée.

Qualité de la neige

L'enneigement est excédentaire pour un mois de février, avec les chutes de neige qui s'enchainent.
Hauteurs de neige observées : 231 cm à la Nivôse de Écrins vers 3000 m, 216 cm au Pré de Mme Carle à 1900 m, 145 cm au hameau de Dormillouse à 1730 m.

Limite d'enneigement skiable : la plupart des itinéraires sont skiables dès les fonds de vallées.

État de la neige de surface : en début de journée, neige fraiche en quantité plus ou moins travaillée par le vent, mais plus lourde/ humide sous 1800 m. Elle tombe un peu plus froide ensuite, mais devient fortement soufflée l'après-midi.

Aperçu météo pour le jeudi 12 février

Fortes chutes de neige (40/50 cm à 2000 m) accompagnées d'un vent devenant tempétueux en altitude, notamment l'après-midi.

	nuit	matin	après-midi	soir
Pluie-Neige	1 300 m	1 200 m	1 200 m	1 200 m
Iso 0 °C	1 800 m	1 800 m	1 900 m	1 700 m
Vent 2000 m	↗ 30 km/h	↘ 35 km/h	→ 65 km/h	→ 55 km/h
Vent 3000 m	→ 90 km/h	↘ 80 km/h	↘ 120 km/h	↘ 110 km/h

Épaisseur de neige hors-piste

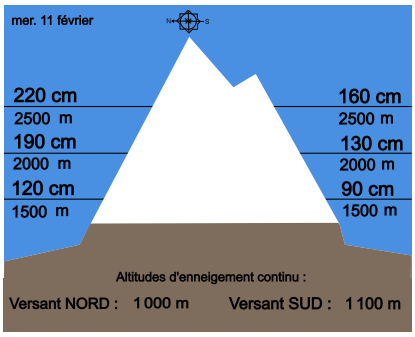

Précipitations à 1800 m

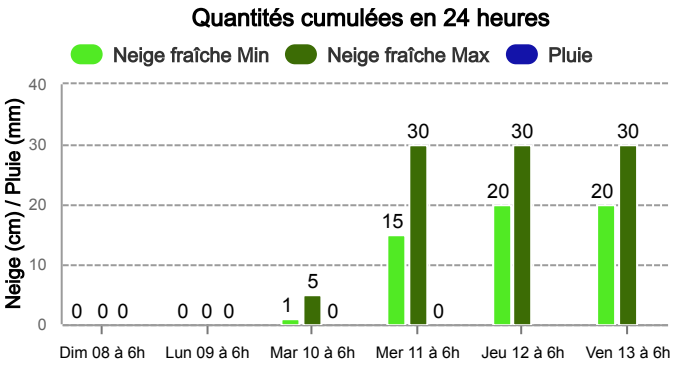

Tendance du vendredi 13 février

Indice de risque fort

Activité naturelle en nette baisse. Maintien d'un risque fort en raison de plaques faciles à déclencher au passage d'un skieur. Cassures épaisses possibles.

Pour consulter la vigilance en cours, veuillez vous rendre sur le site https://vigilance.meteofrance.fr/fr

Météo-France - 73 avenue de Paris, 94165 Saint-Mandé cedex - Contact : contact@meteo.fr

Rédigé par Météo-France avec la contribution des observateurs du réseau nivo-météorologiques. Partenariat : ANMSM (Maires de Stations de Montagne), DSF (Domaines Skiables de France), ADSP (Directeurs de Pistes et de la Sécurité des Stations de Sports d'Hiver) et autres acteurs de la montagne.

Bulletin neige & avalanches par téléphone au **0 892 68 10 20** Service 0,35 € / min + prix appel

Bulletin d'estimation du risque d'avalanche

(valable en dehors des pistes balisées et ouvertes)

MASSIF : Pelvoux

Rédigé le mercredi 11 février 2026 à 17h

Conditions nivo-météo des 7 derniers jours

	jeu. 05/02				ven. 06/02				sam. 07/02				dim. 08/02				lun. 09/02				mar. 10/02				mer. 11/02			
	03h	09h	15h	21h	03h	09h	15h	21h	03h	09h	15h	21h	03h	09h	15h	21h	03h	09h	15h	21h	03h	09h	15h	21h	03h	09h	15h	21h
Météo																												
Vent (km/h)	15	30	45	30	25	30	25	20	20	10	10	10	10	15	20	20	10	15	15	20	30	30	30	80	70	70	50	50
à 3000m																												
Vent (km/h)	10	10	20	20	5	10	15	10	5	5	10	5	5	15	20	20	5	5	10	10	10	15	20	20	20	20	30	25
à 2000m																												

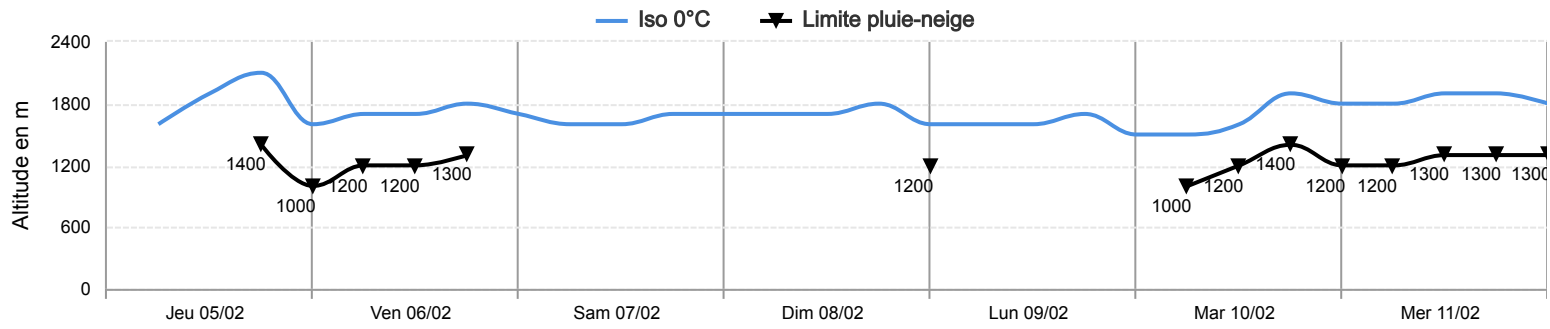

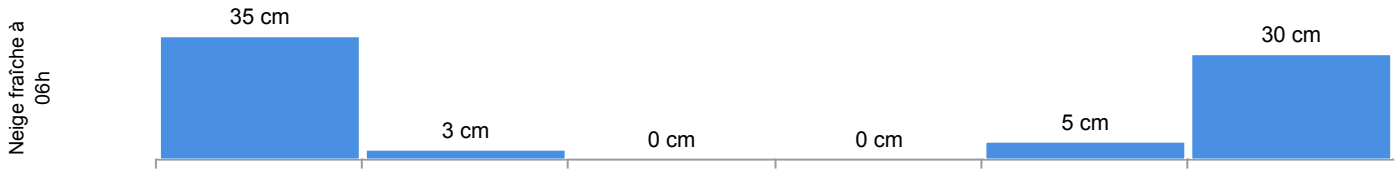

Risque d'avalanche	jeu. 05/02	ven. 06/02	sam. 07/02	dim. 08/02	lun. 09/02	mar. 10/02	mer. 11/02
	3	4	4	3	3	3	4

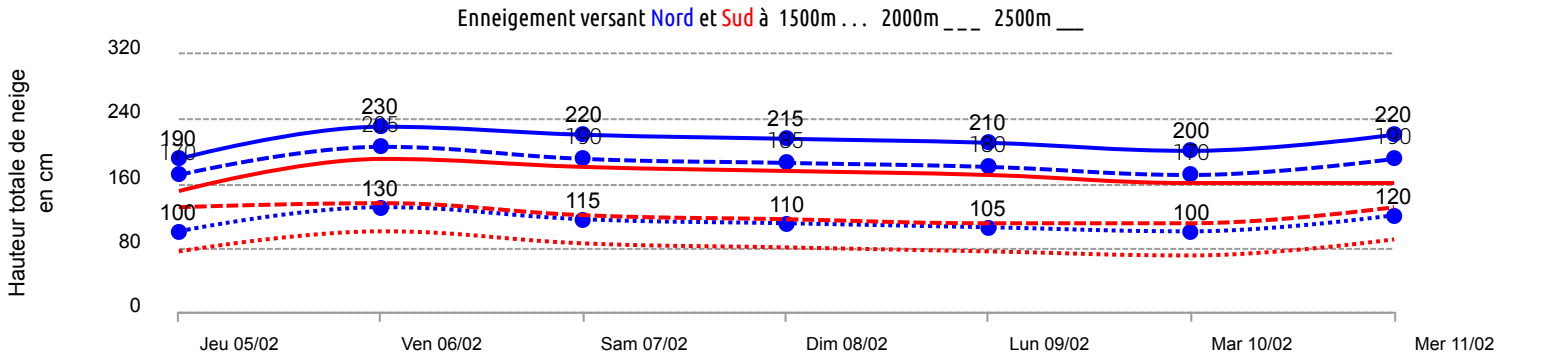

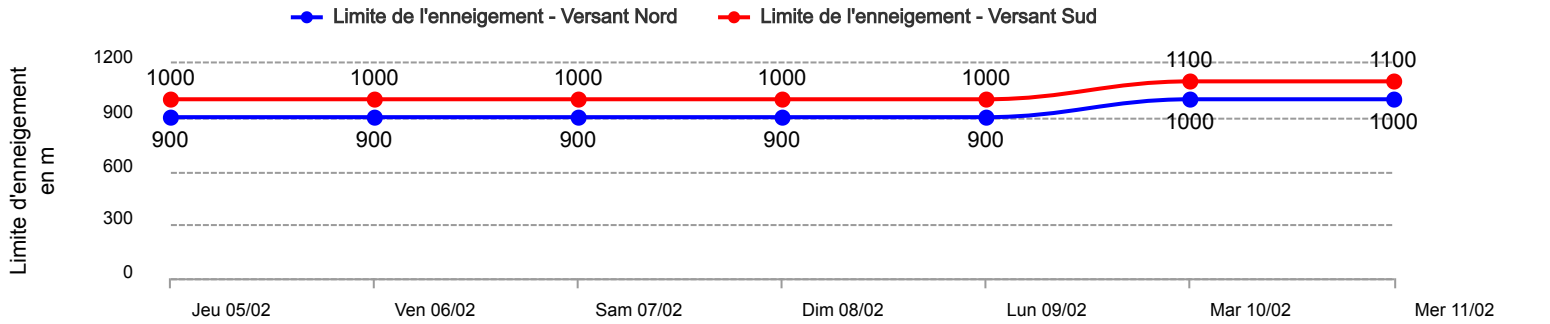

Pour consulter la vigilance en cours, veuillez vous rendre sur le site https://vigilance.meteofrance.fr/fr

Météo-France - 73 avenue de Paris, 94165 Saint-Mandé cedex - Contact : contact@meteo.fr

Rédigé par Météo-France avec la contribution des observateurs du réseau nivo-météorologiques. Partenariat : ANMSM (Maires de Stations de Montagne), DSF (Domaines Skiables de France), ADSP (Directeurs de Pistes et de la Sécurité des Stations de Sports d'Hiver) et autres acteurs de la montagne.

Bulletin neige & avalanches par téléphone au

0 892 68 10 20 Service 0,35 € / min + prix appel