RÉPUBLIQUE FRANÇAISE
Liberté Égalité Fraternité

METEO FRANCE
À VOS CÔTÉS, DANS UN CLIMAT QUI CHANGE

Bulletin d'estimation du risque d'avalanche
(valable en dehors des pistes balisées et ouvertes)

MASSIF : Queyras

Rédigé le mercredi 11 février 2026 à 17h

Estimation des risques pour le : JEUDI 12 FÉVRIER

FORTE INSTABILITÉ PERSISTANTE - PLAQUES PARFOIS ÉPAISSES

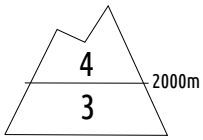

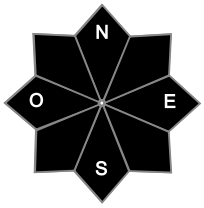

Au-dessus de 2000m indice de risque fort, plus bas indice marqué.

Départs spontanés : avalanches de neige fraîche, départs en poire ou souvent linéaires.

Déclenchements provoqués : nombreuses plaques faciles à déclencher.

Indices de risque : 5 très fort - 4 fort - 3 marqué - 2 limité - 1 faible -- En noir : les pentes les plus dangereuses

Stabilité du manteau neigeux

Situation avalancheuse typique : neige fraîche couche fragile persistante

Déclenchements provoqués : manteau neigeux très instable, surtout au-dessus de 2000 m. Les plaques sont nombreuses et faciles à déclencher dans la neige fraîche ventée. Elles engendrent des avalanches moyennes à grandes (taille 2 à 3), avec souvent de larges cassures.
Dans les ubacs (pentes ouest, nord à est), des départs emportant la totalité du manteau neigeux en place sont envisagés, en cas de rupture sur l'épaisse couche fragile persistante enfouie. Grandes avalanches (taille 3) attendues, une très grande (taille 4) non exclue dans un secteur à la topographie habituellement favorable.
Sous 2000 m, quelques plaques aussi présentes, mais moins généralisées, car la neige fraîche s'est en partie humidifiée.

Départs spontanés : des avalanches de neige fraîche de plus en plus fréquentes à partir de mercredi soir et jeudi matin, puis au retour des quelques éclaircies jeudi après-midi. Départs en poire ou linéaires, mobilisant ponctuellement des volumes de neige importants.

Qualité de la neige

L'enneigement est proche des normales dans les ubacs, voire excédentaire vers le Briançonnais, mais reste un peu déficitaire dans les adrets d'altitude, notamment dans le Haut Guil.
Hauteurs de neige observées : 150 cm en versant nord du col Izoard à 2300 m, 78 cm à la Nivôse du Col Agnel à 2630 m, 60 cm à Ristolas à 1670 m.

Limite d'enneigement skiable : dès 1000/1300 m en ubacs, plutôt 1500/1600 m en adrets avec peu de sous-couche jusqu'à haute altitude, notamment dans le Haut Guil.

État de la neige de surface : en début de journée, neige fraiche plus ou moins travaillée par le vent, mais plus lourde/ humide sous 1800/2000 m. Elle tombe un peu plus froide ensuite, mais devient fortement soufflée l'après-midi.

Aperçu météo pour le jeudi 12 février

	nuit	matin	après-midi	soir
Chutes de neige apportant 20/30 cm vers 2000 m et accompagnées d'un vent devenant tempétueux en altitude, notamment l'après-midi.				
Pluie-Neige	1 300 m	1 200 m	1 200 m	
Iso 0 °C	1 900 m	1 700 m	1 900 m	1 700 m
Vent 2000 m	→ 30 km/h	→ 30 km/h	→ 50 km/h	→ 50 km/h
Vent 3000 m	→ 80 km/h	→ 60 km/h	→ 120 km/h	→ 120 km/h

Épaisseur de neige hors-piste

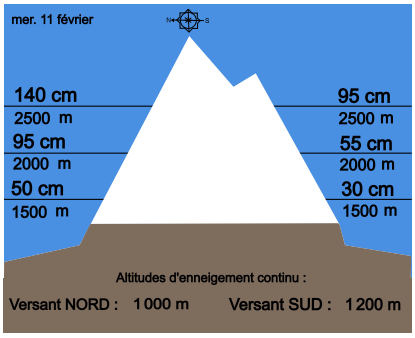

Précipitations à 1800 m

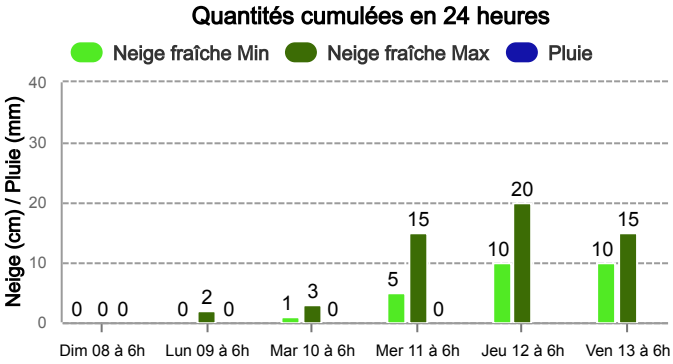

Tendance du vendredi 13 février

Indice de risque fort

Maintien d'un risque fort en raison de plaques faciles à déclencher au passage d'un skieur. Cassures épaisses possibles.

Pour consulter la vigilance en cours, veuillez vous rendre sur le site https://vigilance.meteofrance.fr/fr

Météo-France - 73 avenue de Paris, 94165 Saint-Mandé cedex - Contact : contact@meteo.fr

Rédigé par Météo-France avec la contribution des observateurs du réseau nivo-météorologiques. Partenariat : ANMSM (Maires de Stations de Montagne), DSF (Domaines Skiables de France), ADSP (Directeurs de Pistes et de la Sécurité des Stations de Sports d'Hiver) et autres acteurs de la montagne.

Bulletin neige & avalanches par téléphone au
0 892 68 10 20 Service 0,35 € / min + prix appel

RÉPUBLIQUE FRANÇAISE
Liberté Égalité Fraternité

METEO FRANCE
À VOS CÔTÉS, DANS UN CLIMAT QUI CHANGE

Bulletin d'estimation du risque d'avalanche

(valable en dehors des pistes balisées et ouvertes)

MASSIF : Queyras

Rédigé le mercredi 11 février 2026 à 17h

Conditions nivo-météo des 7 derniers jours

	jeu. 05/02				ven. 06/02				sam. 07/02				dim. 08/02				lun. 09/02				mar. 10/02				mer. 11/02			
	03h	09h	15h	21h	03h	09h	15h	21h	03h	09h	15h	21h	03h	09h	15h	21h	03h	09h	15h	21h	03h	09h	15h	21h	03h	09h	15h	21h
Météo																												
Vent (km/h)	20	25	40	25	35	35	40	25	25	15	15	10	10	20	35	35	15	10	15	20	30	35	40	50	50	50	50	60
à 3000m																												
Vent (km/h)	10	10	10	15	5	15	25	10	10	10	15	5	5	15	30	30	10	10	15	10	10	20	25	25	25	25	30	30
à 2000m																												

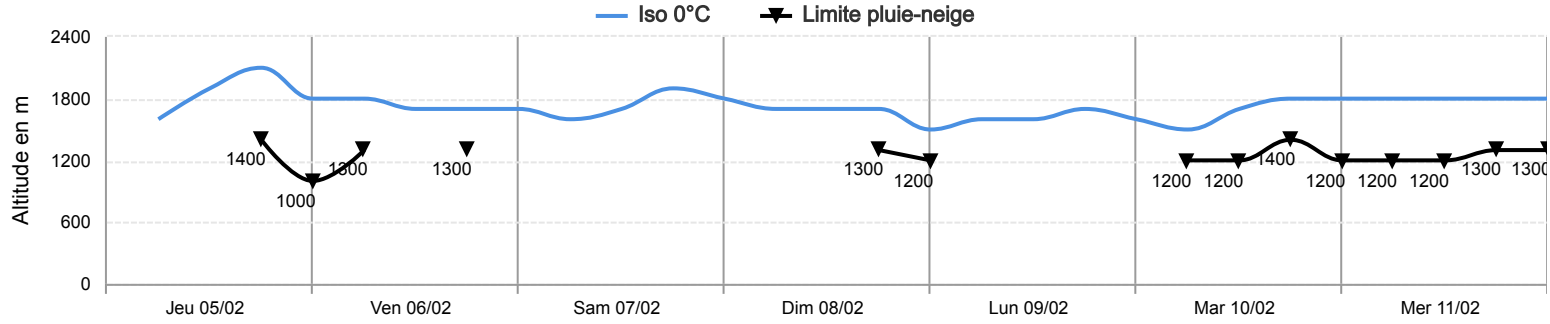

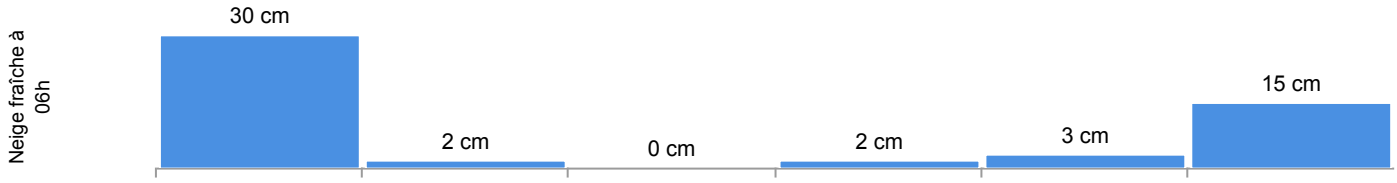

Risque d'avalanche	jeu. 05/02	ven. 06/02	sam. 07/02	dim. 08/02	lun. 09/02	mar. 10/02	mer. 11/02
	3	4	4	3	3	3	4

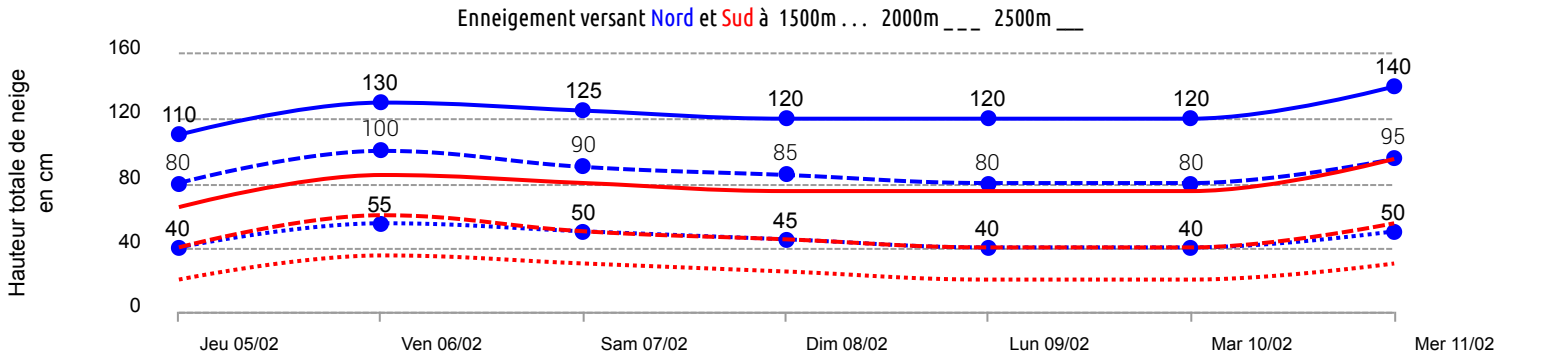

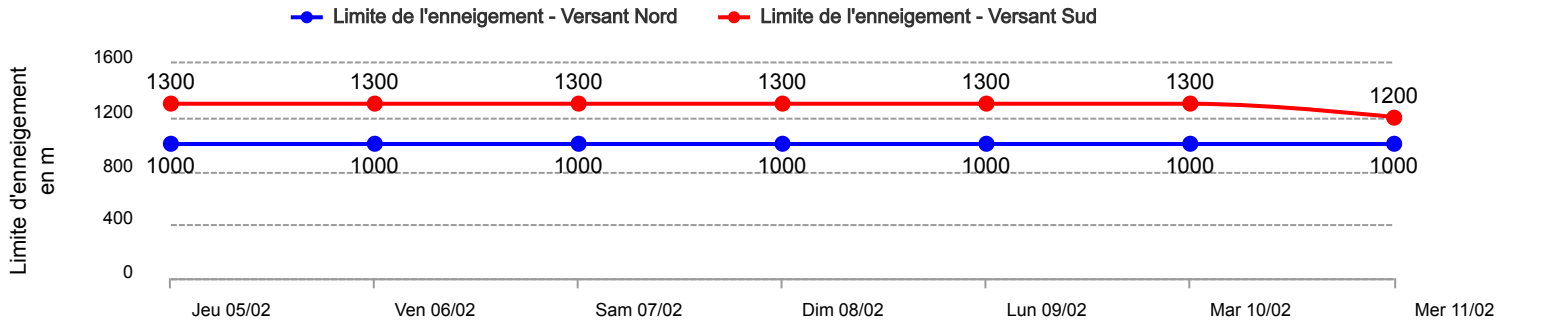

Pour consulter la vigilance en cours, veuillez vous rendre sur le site https://vigilance.meteofrance.fr/fr

Météo-France - 73 avenue de Paris, 94165 Saint-Mandé cedex - Contact : contact@meteo.fr

Bulletin neige & avalanches par téléphone au

0 892 68 10 20 Service 0,35 € / min + prix appel

Rédigé par Météo-France avec la contribution des observateurs du réseau nivo-météorologiques. Partenariat : ANMSM (Maires de Stations de Montagne), DSF (Domaines Skiables de France), ADSP (Directeurs de Pistes et de la Sécurité des Stations de Sports d'Hiver) et autres acteurs de la montagne.