Bulletin d'estimation du risque d'avalanche
(valable en dehors des pistes balisées et ouvertes)

MASSIF : Devoluy

Rédigé le mercredi 11 février 2026 à 19h

Estimation des risques pour le : JEUDI 12 FÉVRIER

MANTEAU NEIGEUX INSTABLE AVEC LES CHUTES DE NEIGE QUI SE SUCCÈDENT

3

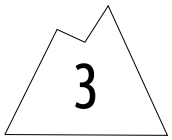

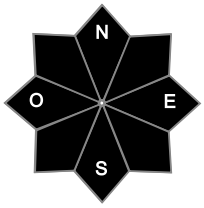

Indice de risque marqué.

Départs spontanés : nombreuses avalanches de neige fraîche, départs en poire ou linéaires.

Déclenchements provoqués : nombreuses plaques dans la neige fraîche.

Indices de risque : 5 très fort - 4 fort - 3 marqué - 2 limité - 1 faible -- En noir : les pentes les plus dangereuses

Stabilité du manteau neigeux

Situation avalancheuse typique : neige fraîche couche fragile persistante

Déclenchements provoqués : manteau neigeux peu stabilisé dans de nombreuses pentes. Les plaques dans la neige fraîche ventée sont fréquentes et faciles à déclencher. Elles engendrent des avalanches moyennes (taille 2), voire grandes (taille 3) quand la topographie est favorable, emportant toute la couche de neige récente des derniers jours. Ponctuellement, une cassure emportant la totalité du manteau neigeux n'est pas exclue, mobilisant alors un important volume de neige.

Départs spontanés : avalanches de neige fraîche de plus en plus nombreuses à partir de mercredi soir et toute la journée de jeudi. Départs en poire ou linéaires, emportant toute la couche de neige récente, parfois sur de grandes largeurs. Avalanches moyennes à grandes (taille 2 à 3). Une très grande avalanche (taille 4) non exclue, en cas de rupture sur une couche fragile persistante enfouie, dans un secteur à la topographie habituellement favorable.

Qualité de la neige

L'enneigement est excédentaire pour un mois de février.
Hauteurs de neige observées : environ 100 cm vers 2000 m d'altitude.

Limite d'enneigement skiable : vers 1200/1300 m sur la plupart des itinéraires en ubacs, 1400/1500 m en adrets.

État de la neige de surface : en début de journée, neige fraiche en quantité plus ou moins travaillée par le vent, mais plus lourde/ humide sous 2000 m environ. Elle tombe un peu plus froide ensuite, mais devient fortement soufflée l'après-midi.

Aperçu météo pour le jeudi 12 février

	nuit	matin	après-midi	soir

Fortes chutes de neige (30/40 cm à 2000/2200 m) accompagnées d'un vent devenant tempétueux en altitude, notamment l'après-midi.

Pluie-Neige	1 500 m	1 300 m	1 200 m	1 200 m
Iso 0 °C	2 000 m	1 700 m	1 700 m	1 600 m
Vent 2000 m	→ 40 km/h	↘ 45 km/h	↘ 60 km/h	↘ 60 km/h
Vent 3000 m	→ 70 km/h	↘ 60 km/h	↘ 100 km/h	↘ 100 km/h

Épaisseur de neige hors-piste

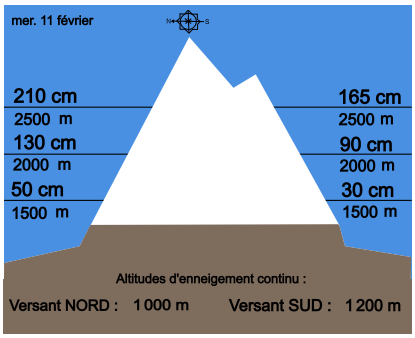

Précipitations à 1800 m

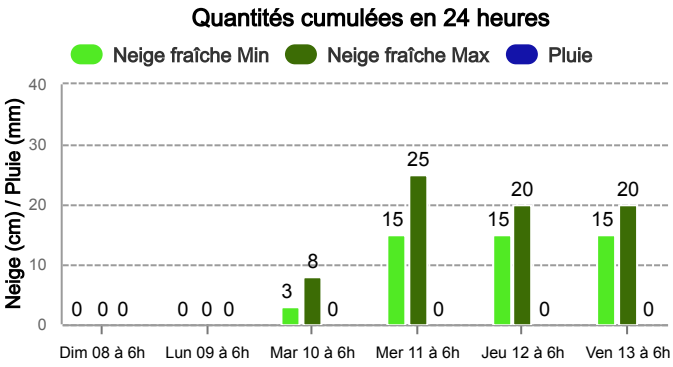

Tendance du vendredi 13 février

3

Indice de risque marqué

Activité naturelle en nette baisse. Maintien d'un risque marqué en raison de plaques faciles à déclencher au passage d'un skieur.

Pour consulter la vigilance en cours, veuillez vous rendre sur le site https://vigilance.meteofrance.fr/fr

Météo-France - 73 avenue de Paris, 94165 Saint-Mandé cedex - Contact : contact@meteo.fr

Rédigé par Météo-France avec la contribution des observateurs du réseau nivo-météorologiques. Partenariat : ANMSM (Maires de Stations de Montagne), DSF (Domaines Skiables de France), ADSP (Directeurs de Pistes et de la Sécurité des Stations de Sports d'Hiver) et autres acteurs de la montagne.

Bulletin neige & avalanches par téléphone au **0 892 68 10 20** Service 0,35 € / min + prix appel

Bulletin d'estimation du risque d'avalanche

(valable en dehors des pistes balisées et ouvertes)

MASSIF : Devoluy

Rédigé le mercredi 11 février 2026 à 19h

Conditions nivo-météo des 7 derniers jours

	jeu. 05/02				ven. 06/02				sam. 07/02				dim. 08/02				lun. 09/02				mar. 10/02				mer. 11/02			
	03h	09h	15h	21h	03h	09h	15h	21h	03h	09h	15h	21h	03h	09h	15h	21h	03h	09h	15h	21h	03h	09h	15h	21h	03h	09h	15h	21h
Météo																												
Vent (km/h)	30	15	60	40	40	45	35	20	15	10	10	5	10	25	25	10	5	15	15	20	30	40	40	60	60	65	55	45
à 3000m																												
Vent (km/h)	10	20	60	10	25	25	25	15	10	10	15	10	10	20	20	10	5	15	15	15	20	15	20	25	30	30	30	25
à 2000m																												

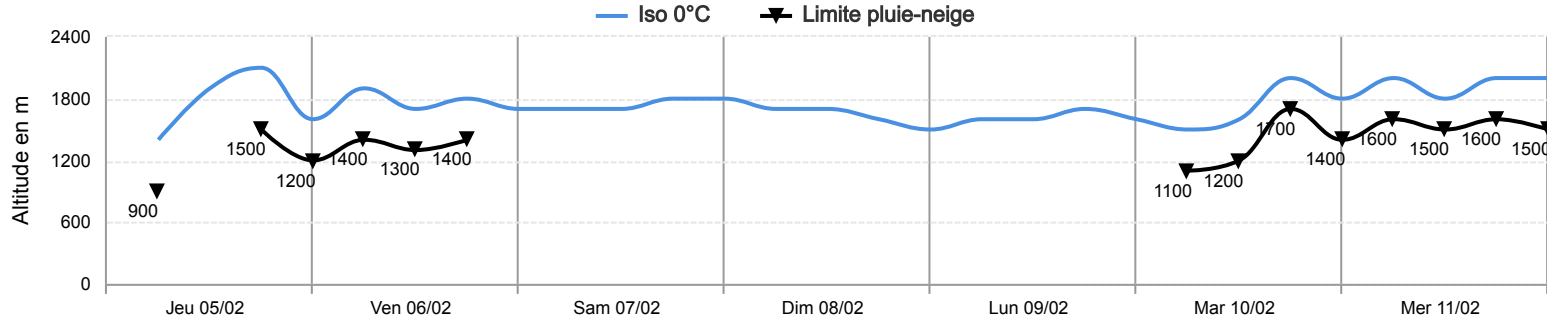

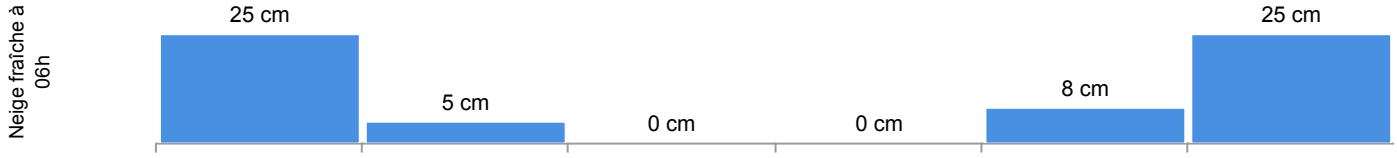

Risque d'avalanche	jeu. 05/02	ven. 06/02	sam. 07/02	dim. 08/02	lun. 09/02	mar. 10/02	mer. 11/02
	3	4	3	3	2	2	3

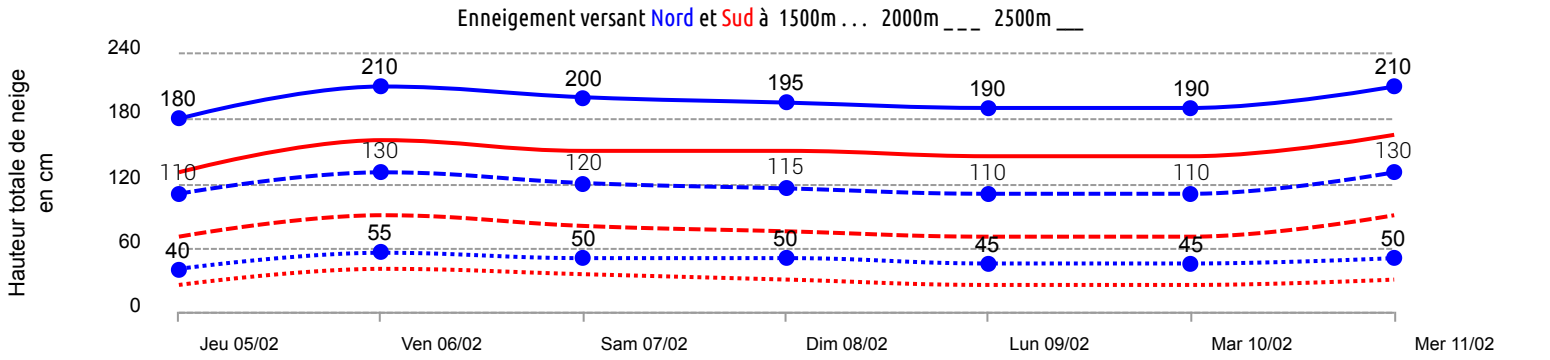

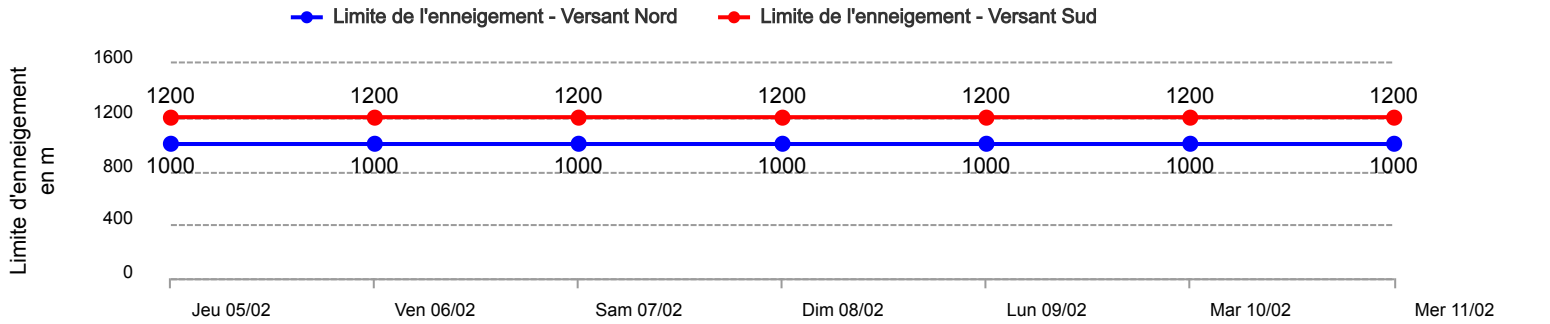

Pour consulter la vigilance en cours, veuillez vous rendre sur le site https://vigilance.meteofrance.fr/fr

Météo-France - 73 avenue de Paris, 94165 Saint-Mandé cedex - Contact : contact@meteo.fr

Bulletin neige & avalanches par téléphone au

0 892 68 10 20 Service 0,35 € / min + prix appel

Rédigé par Météo-France avec la contribution des observateurs du réseau nivo-météorologiques. Partenariat : ANMSM (Maires de Stations de Montagne), DSF (Domaines Skiables de France), ADSP (Directeurs de Pistes et de la Sécurité des Stations de Sports d'Hiver) et autres acteurs de la montagne.