Bulletin d'avalanches jusqu'à mercredi, 11. février 2026

Danger d'avalanche

actualisé le 11.2.2026, 08:00

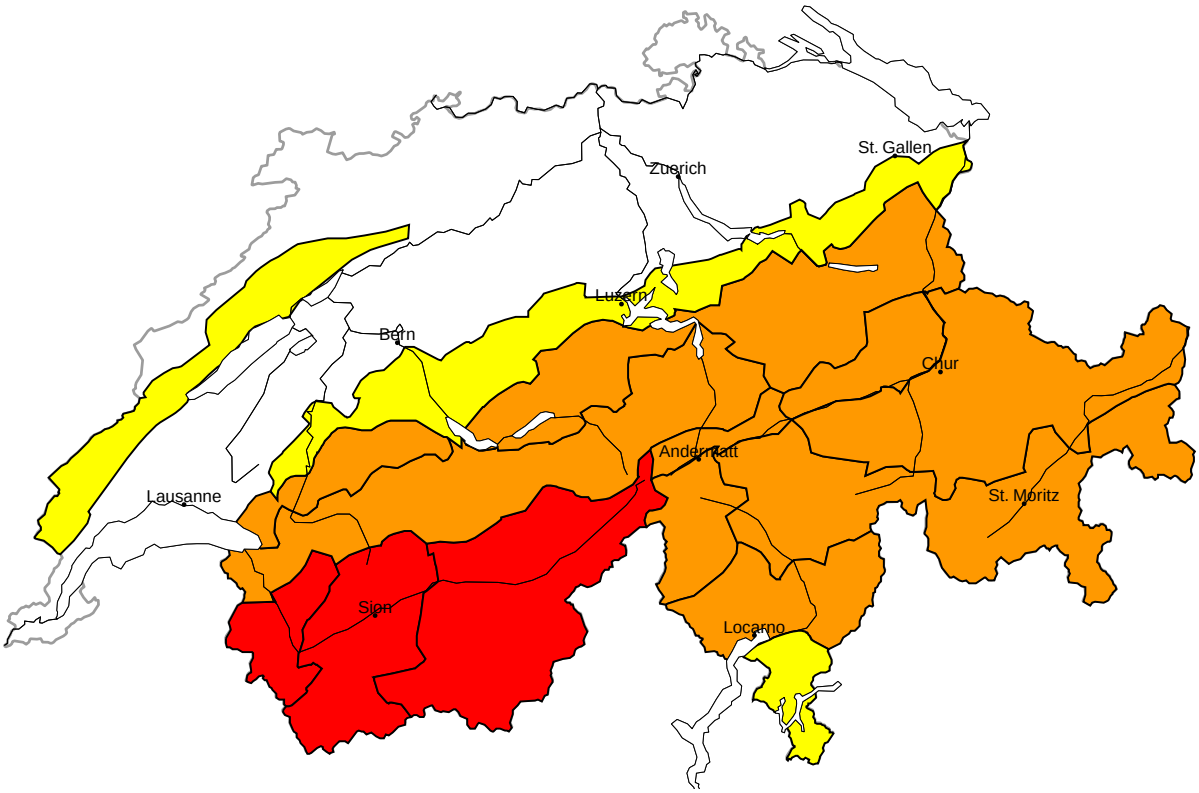

région A

Fort (4=)

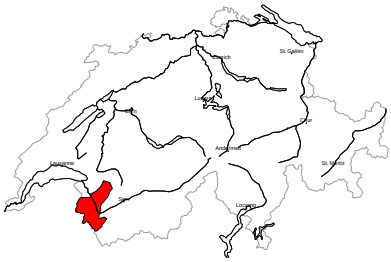

Neige fraîche, Couche fragile persistante

Endroits dangereux

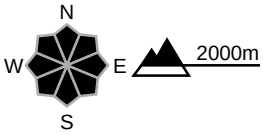

Description des dangers
La neige fraîche abondante et la neige soufflée reposent sur une couche fragile de neige ancienne. Des avalanches peuvent en de nombreux endroits être déclenchées facilement ou se déclencher spontanément. Avec la neige fraîche et le vent fort le danger d'avalanches augmente au sein du degré de danger en cours de journée. Des avalanches de très grande taille sont à attendre. Les tronçons exposés des voies de communication sont menacés. Pour des randonnées et descentes hors-piste en dehors des pistes sécurisées les conditions sont défavorables.

Limité (2)

Neige humide

Endroits dangereux

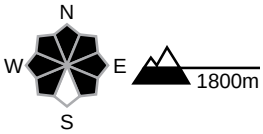

Description des dangers
Des avalanches et coulées mouillées sont à attendre avec la pluie. Celles-ci peuvent atteindre une taille moyenne. Les endroits dangereux se situent dans les combes et couloirs. A côté du danger d'ensevelissement, il faut surtout penser au danger d'être emporté et de chuter.

Degrés de danger 1 faible 2 limité 3 marqué 4 fort 5 très fort

Bulletin d'avalanches jusqu'à mercredi, 11. février 2026

région B — Fort (4=)

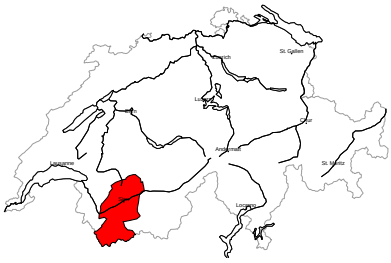

Neige fraîche, Couche fragile persistante

Endroits dangereux

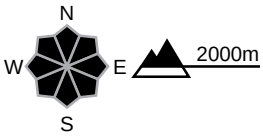

Description des dangers
La neige fraîche abondante et la neige soufflée reposent sur une couche fragile de neige ancienne. Des avalanches peuvent en de nombreux endroits être déclenchées facilement ou se déclencher spontanément. Avec la neige fraîche et le vent fort le danger d'avalanches augmente au sein du degré de danger en cours de journée. Des avalanches de très grande taille sont à attendre. Les tronçons exposés des voies de communication sont menacés. Pour des randonnées et descentes hors-piste en dehors des pistes sécurisées les conditions sont défavorables.

région C — Fort (4-)

Neige fraîche, Couche fragile persistante

Endroits dangereux

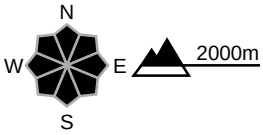

Description des dangers
La neige fraîche abondante et la neige soufflée reposent sur une couche fragile de neige ancienne. Des avalanches peuvent en de nombreux endroits être déclenchées facilement ou se déclencher spontanément. Avec la neige fraîche et le vent fort le danger d'avalanches augmente au sein du degré de danger en cours de journée. Des avalanches de plus en plus nombreuses de très grande taille sont à attendre. Les tronçons exposés des voies de communication sont de plus en plus menacés. Pour des randonnées et descentes hors-piste en dehors des pistes sécurisées les conditions sont défavorables.

région D

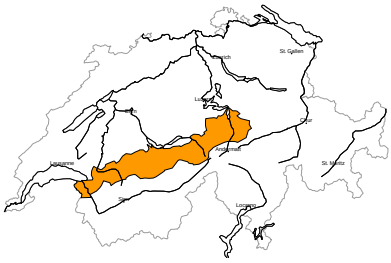

Marqué (3+)

Neige fraîche, Couche fragile persistante

Endroits dangereux

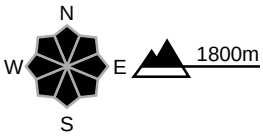

Description des dangers
La neige fraîche abondante et la neige soufflée reposent sur une couche fragile de neige ancienne. Des avalanches peuvent être déclenchées par un seul amateur de sports d'hiver. Elles peuvent parfois entraîner avec elles les couches plus profondes du manteau neigeux. Des avalanches spontanées de plus en plus nombreuses sont possibles. Des avalanches peuvent atteindre une grande taille.
Les randonnées et descentes hors-piste demandent prudence et retenue.

Limité (2)

Neige humide

Endroits dangereux

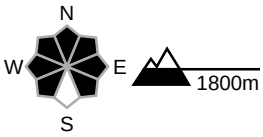

Description des dangers
Des avalanches et coulées mouillées sont à attendre avec la pluie. Celles-ci peuvent atteindre une taille moyenne. Les endroits dangereux se situent dans les combes et couloirs. A côté du danger d'ensevelissement, il faut surtout penser au danger d'être emporté et de chuter.

région E

Marqué (3+)

Neige fraîche, Couche fragile persistante

Endroits dangereux

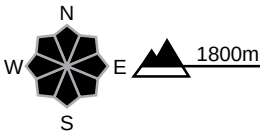

Description des dangers
La neige fraîche abondante et la neige soufflée reposent sur une couche fragile de neige ancienne. Des avalanches peuvent être déclenchées par un seul amateur de sports d'hiver. Elles peuvent parfois entraîner avec elles les couches plus profondes du manteau neigeux. Des avalanches spontanées de plus en plus nombreuses sont possibles. Des avalanches peuvent atteindre une grande taille.
Les randonnées et descentes hors-piste demandent prudence et retenue.

région F — Marqué (3+)

Neige fraîche, Couche fragile persistante

Endroits dangereux

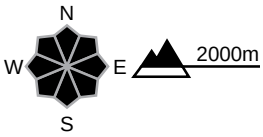

Description des dangers
La neige fraîche et la neige soufflée reposent sur une couche fragile de neige ancienne. Des avalanches peuvent se déclencher dans les couches profondes du manteau neigeux et atteindre une grande taille. Des déclenchements à distance sont possibles. Des bruits sourds et des fissures lors du passage sur le manteau neigeux ainsi que des avalanches récentes attirent l'attention sur le danger.
Les randonnées et descentes hors-piste demandent beaucoup d' expérience dans l'évaluation du danger d'avalanche et de la retenue.

région G — Marqué (3+)

Couche fragile persistante

Endroits dangereux

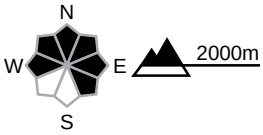

Description des dangers
Des couches fragiles marquées dans la neige ancienne demandent de la prudence. Des avalanches peuvent se déclencher dans les couches profondes du manteau neigeux et atteindre une grande taille de manière isolée. Les endroits dangereux sont fréquents. Des déclenchements à distance sont à attendre. Des bruits sourds et des fissures lors du passage sur le manteau neigeux ainsi que des avalanches récentes attirent l'attention sur le danger.
Les randonnées et descentes hors-piste demandent beaucoup d' expérience dans l'évaluation du danger d'avalanche et de la retenue.

région H

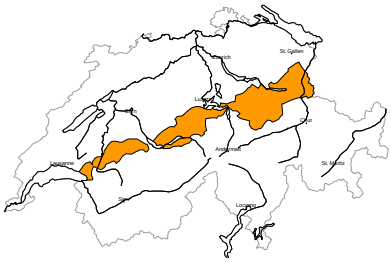

Marqué (3=)

Neige fraîche, Couche fragile persistante

Endroits dangereux

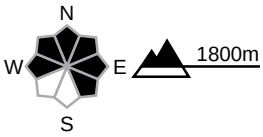

Description des dangers
La neige fraîche et la neige soufflée sont fragiles. Des avalanches peuvent être déclenchées par un seul amateur de sports d'hiver. Elles peuvent parfois entraîner avec elles les couches plus profondes du manteau neigeux et atteindre une grande taille.
Avec la chute de neige le danger augmente encore en cours de journée. Des avalanches spontanées isolées sont possibles.
Les randonnées demandent une expérience dans l'évaluation du danger d'avalanche.

Limité (2)

Neige humide

Endroits dangereux

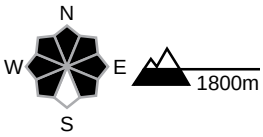

Description des dangers
Des avalanches et coulées mouillées sont à attendre avec la pluie. Celles-ci peuvent atteindre une taille moyenne. Les endroits dangereux se situent dans les combes et couloirs. A côté du danger d'ensevelissement, il faut surtout penser au danger d'être emporté et de chuter.

région I

Marqué (3=)

Neige fraîche, Couche fragile persistante

Endroits dangereux

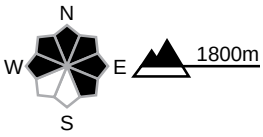

Description des dangers
La neige fraîche et la neige soufflée sont fragiles. Des avalanches peuvent être déclenchées par un seul amateur de sports d'hiver. Elles peuvent parfois entraîner avec elles les couches plus profondes du manteau neigeux et atteindre une grande taille.
Avec la chute de neige le danger augmente encore en cours de journée. Des avalanches spontanées isolées sont possibles.
Les randonnées demandent une expérience dans l'évaluation du danger d'avalanche.

région J — Marqué (3=)

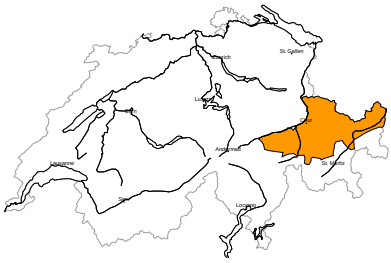

Couche fragile persistante

Endroits dangereux

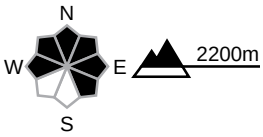

Description des dangers
Des couches fragiles dans la neige ancienne demandent de la prudence. Des adeptes des sports de neige même seuls peuvent déclencher des avalanches. Celles-ci peuvent se déclencher dans les couches profondes du manteau neigeux et atteindre une grande taille de manière isolée. Des déclenchements à distance sont à attendre. Des bruits sourds et des fissures lors du passage sur le manteau neigeux ainsi que des avalanches récentes peuvent attirer l'attention sur le danger.
Les randonnées et descentes hors-piste demandent beaucoup d'expérience dans l'évaluation du danger d'avalanche.

région K — Marqué (3=)

Couche fragile persistante

Endroits dangereux

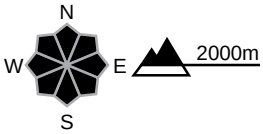

Description des dangers
Des couches fragiles dans la neige ancienne demandent de la prudence. Des adeptes des sports de neige même seuls peuvent déclencher des avalanches. Celles-ci peuvent se déclencher dans les couches profondes du manteau neigeux et atteindre une grande taille de manière isolée. Des déclenchements à distance sont possibles. Des bruits sourds et des fissures lors du passage sur le manteau neigeux ainsi que des avalanches récentes peuvent attirer l'attention sur le danger.
Les randonnées et descentes hors-piste demandent beaucoup d'expérience dans l'évaluation du danger d'avalanche.

région L

Limité (2+)

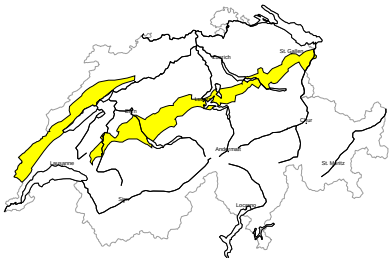

Neige soufflée

Endroits dangereux

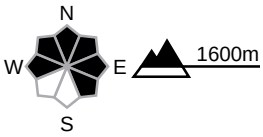

Description des dangers
Des accumulations de neige soufflée en partie fragiles se forment avec la neige fraîche et le vent d'ouest fort. Des avalanches peuvent atteindre une taille moyenne. Les accumulations récentes de neige soufflée devraient être évaluées avec prudence surtout en terrain très raide.

Limité (2)

Neige humide

Endroits dangereux

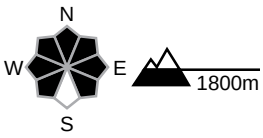

Description des dangers
Des avalanches et coulées mouillées sont à attendre avec la pluie. Celles-ci peuvent atteindre une taille moyenne. Les endroits dangereux se situent dans les combes et couloirs. A côté du danger d'ensevelissement, il faut surtout penser au danger d'être emporté et de chuter.

région M

Limité (2+)

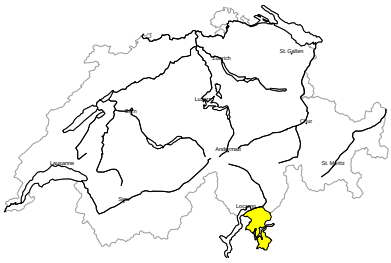

Couche fragile persistante

Endroits dangereux

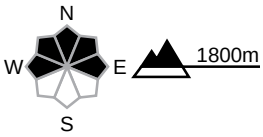

Description des dangers
Dans le manteau neigeux ancien des couches fragiles importantes sont présentes. Des avalanches peuvent par endroits être déclenchées par un seul amateur de sports d'hiver. Des avalanches peuvent se déclencher dans les couches profondes du manteau neigeux et atteindre une taille moyenne.
Les randonnées et descentes hors-piste demandent un choix très prudent d'itinéraires.

Manteau neigeux et météo

actualisé le 10.2.2026, 17:00

Manteau neigeux

Dans toutes les régions, la neige est nettement moins abondante que d'habitude à cette époque de l'année, surtout aux basses et moyennes altitudes. Les forts cumuls de neige fraîche attendus dans l'ouest et le nord au cours des prochains jours tomberont sur un manteau neigeux de constitution généralement défavorable : Les surfaces de la neige ont généralement subi une métamorphose constructive et la neige est meuble. La partie centrale et inférieure du manteau neigeux comprend par ailleurs des couches fragiles et instables marquées, notamment sur les pentes exposées à l'ouest, au nord et à l'est, surtout au sud d'une ligne Rhône-Rhin. Au nord de ces régions, la constitution du manteau neigeux est un peu meilleure, mais dans ces régions également, le manteau neigeux renferme des couches fragiles en profondeur. Avec cette situation initiale, une augmentation rapide et marquée du danger d'avalanches se profile, surtout dans l'ouest et le nord.

Rétrospective météo de ce mardi

Mardi, le temps était couvert. Dans toutes les régions ou presque, il y a eu un peu de précipitation avec une limite pluie-neige comprise entre 1000 et 1500 mètres.

Neige fraîche
Apport de neige jusqu'au lundi après-midi :
- Jura, extrême ouest du Bas-Valais, nord du Bas-Valais, Tessin : de 5 à 15 cm
- Ailleurs : moins de neige fraîche ou temps sec

Température
À la mi-journée à 2000 m, entre -2 °C dans le nord et -4 °C dans le sud

Vent
Vent d'ouest à sud-ouest croissant, l'après-midi :
- Dans le Jura et sur le versant nord des Alpes, modéré à fort
- Ailleurs, faible à modéré

Prévisions météorologiques jusqu'à mercredi

Dans le nord, le temps sera très nuageux avec des précipitations. Elles seront particulièrement intenses dans l'extrême ouest et le nord du Bas-Valais ainsi que dans les Alpes vaudoises. Dans l'ouest, la limite pluie-neige augmentera pendant la nuit de mardi à mercredi vers 2000 m, puis redescendra vers 1300 m. Dans le Valais, elle se situera temporairement plus profondément. Dans le sud, le ciel sera très nuageux pendant la nuit de mardi à mercredi avec quelques précipitations. Pendant la journée, le temps sera assez ensoleillé.

Neige fraîche
Les quantités suivantes de neige tomberont au-dessus de 2200 m :
- Extrême ouest et nord du Bas-Valais, Alpes vaudoises : de 50 à 80 cm
- Reste de l'ouest et du centre du versant nord des Alpes, reste du Valais : de 30 à 50 cm
- Est du versant nord des Alpes, sud de la région du Simplon, nord du Tessin, Surselva et Prättigau : de 15 à 30 cm
- Reste du Tessin et reste des Grisons : de 5 à 15 cm

Température
À la mi-journée à 2000 m, entre -2 °C dans le nord et 0 °C dans le sud

Vent
- Le long des Préalpes, dans l'ouest et le nord en altitude vent fort à tempétueux de secteur ouest à sud-ouest
- Au Tessin et dans les Grisons, vent généralement modéré d'abord de secteur sud-ouest, puis de secteur nord-ouest

Tendance pour jeudi et vendredi

Jeudi
Dans le nord, le ciel restera très nuageux avec des précipitations parfois persistantes et abondantes. Le vent d'ouest continuera de souffler fort à tempétueux, surtout sur le versant nord des Alpes et dans l'ouest. Il faut s'attendre à nouveau à des cumuls de neige fraîche similaires à ceux de la veille. La limite pluie-neige se situera entre 1100 et 1300 m.
Le danger d'avalanches continuera d'augmenter de manière générale, dans les régions concernées par les précipitations principales à l'intérieur du degré 4. Il faut s'y attendre de plus en plus à de très grandes avalanches pouvant s'engouffrer dans les couloirs d'avalanches habituels pour atteindre les vallées et menacer les tronçons exposés des voies de communication.

Vendredi
Pendant la nuit de jeudi à vendredi, de 20 à 40 cm de neige tomberont encore sur le versant nord des Alpes, dans le Bas-Valais et dans le Prättigau, et moins dans le reste du Valais et dans les Grisons. La limite pluie-neige se situera entre 1000 et 1200 m. Sur le versant sud des Alpes, le temps sera sec. Pendant la journée, la nébulosité sera variable sur le versant nord des Alpes et le temps sera généralement ensoleillé dans le Valais et le sud. Le vent d'ouest s'affaiblira nettement.
Le danger d'avalanches augmentera encore un peu pendant la nuit de jeudi à vendredi et pourra également atteindre le degré de danger 4 dans l'est du versant nord des Alpes et dans le nord des Grisons. Sur le versant nord des Alpes, de très grandes avalanches pouvant atteindre les vallées et menacer les tronçons exposés des voies de communication sont possibles. Dans les Grisons, en revanche, le danger concerne surtout les zones de sports de neige alpines.