Bollettino valanghe per mercoledì, 11. febbraio 2026

Pericolo valanghe

aggiornato al 11.2.2026, 08:00

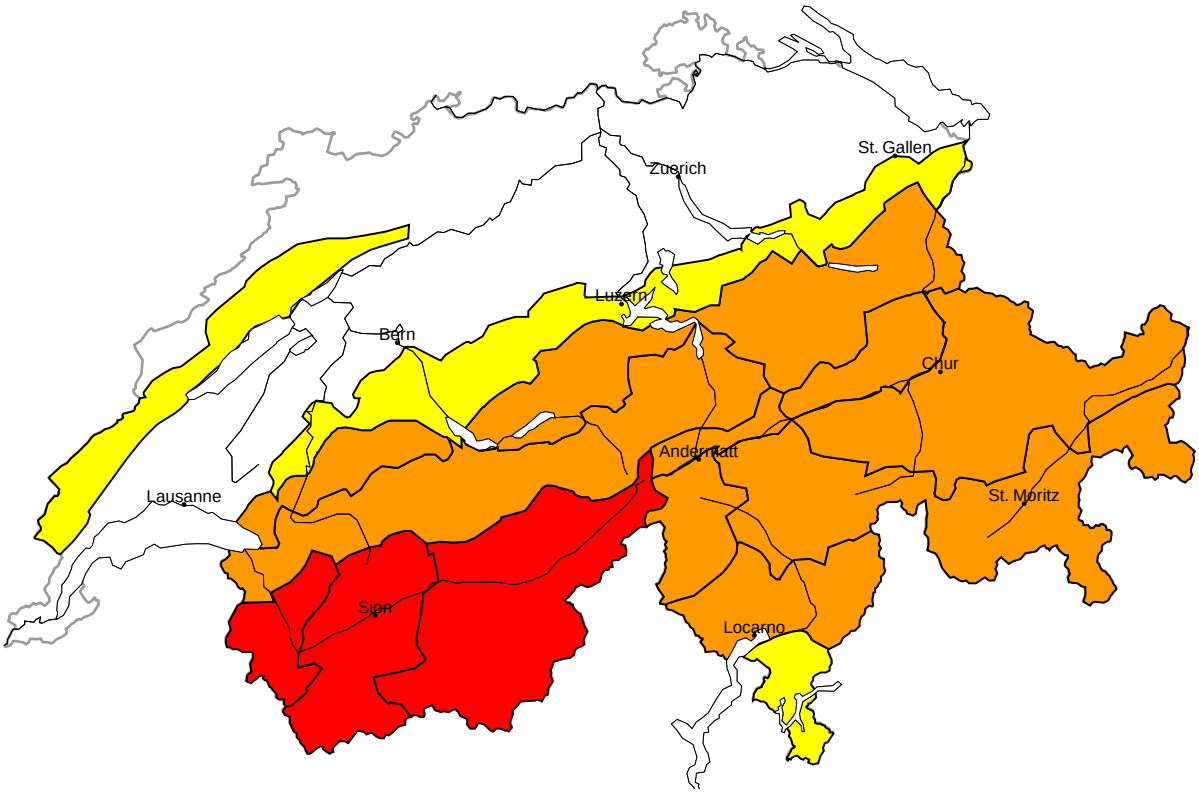

regione A

Forte (4=)

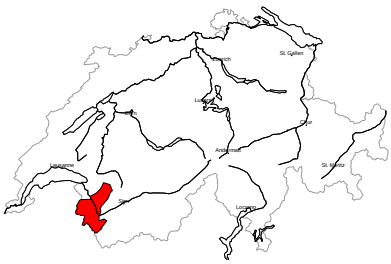

Neve fresca, Strati deboli persistenti

Punti pericolosi

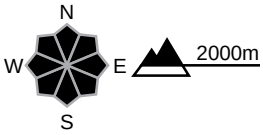

Descrizione del pericolo

Le grandi quantità di neve fresca e neve ventata ricoprono un debole manto di neve vecchia. Le valanghe possono in molti punti distaccarsi facilmente oppure spontaneamente. Con neve fresca e forte vento, nel corso della giornata il pericolo di valanghe aumenterà senza passare di grado. Sono previste valanghe di dimensioni molto grandi. I tratti esposti delle vie di comunicazione saranno in pericolo. Per le escursioni e le discese fuori pista al di fuori delle piste assicurate, le condizioni sono sfavorevoli.

Moderato (2)

Neve bagnata

Punti pericolosi

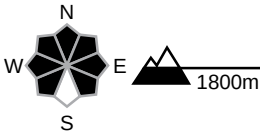

Descrizione del pericolo

Con la pioggia, sono previste colate e valanghe bagnate. Queste ultime possono raggiungere dimensioni medie. I punti pericolosi si trovano nelle conche e nei canaloni. Oltre al pericolo di seppellimento, occorre fare attenzione soprattutto al pericolo di trascinamento e caduta.

Scala del pericolo 1 debole | 2 moderato | 3 marcato | 4 forte | 5 molto forte

regione B — Forte (4=)

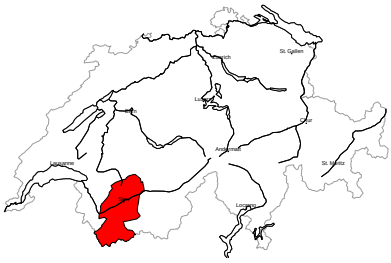

Neve fresca, Strati deboli persistenti

Punti pericolosi

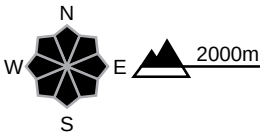

Descrizione del pericolo
Le grandi quantità di neve fresca e neve ventata ricoprono un debole manto di neve vecchia. Le valanghe possono in molti punti distaccarsi facilmente oppure spontaneamente. Con neve fresca e forte vento, nel corso della giornata il pericolo di valanghe aumenterà senza passare di grado. Sono previste valanghe di dimensioni molto grandi. I tratti esposti delle vie di comunicazione saranno in pericolo. Per le escursioni e le discese fuori pista al di fuori delle piste assicurate, le condizioni sono sfavorevoli.

regione C — Forte (4-)

Neve fresca, Strati deboli persistenti

Punti pericolosi

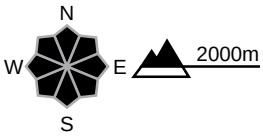

Descrizione del pericolo
Le grandi quantità di neve fresca e neve ventata ricoprono un debole manto di neve vecchia. Le valanghe possono in molti punti distaccarsi facilmente oppure spontaneamente. Con neve fresca e forte vento, nel corso della giornata il pericolo di valanghe aumenterà senza passare di grado. Sono previste sempre più numerose valanghe di dimensioni molto grandi. I tratti esposti delle vie di comunicazione saranno sempre più in pericolo. Per le escursioni e le discese fuori pista al di fuori delle piste assicurate, le condizioni sono sfavorevoli.

regione D

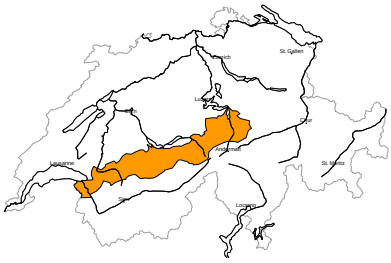

Marcato (3+)

Neve fresca, Strati deboli persistenti

Punti pericolosi

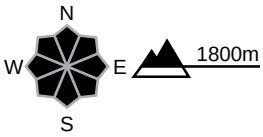

Descrizione del pericolo
Le grandi quantità di neve fresca e neve ventata ricoprono un debole manto di neve vecchia. Le valanghe possono distaccarsi in seguito al passaggio di un singolo appassionato di sport invernali. Esse possono in parte coinvolgere gli strati più profondi. Sono possibili sempre più numerose valanghe spontanee. Le valanghe possono raggiungere grandi dimensioni.
Le escursioni e le discese fuori pista richiedono attenzione e prudenza.

Moderato (2)

Neve bagnata

Punti pericolosi

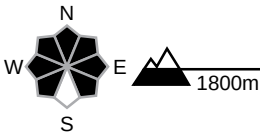

Descrizione del pericolo
Con la pioggia, sono previste colate e valanghe bagnate. Queste ultime possono raggiungere dimensioni medie. I punti pericolosi si trovano nelle conche e nei canaloni. Oltre al pericolo di seppellimento, occorre fare attenzione soprattutto al pericolo di trascinamento e caduta.

regione E

Marcato (3+)

Neve fresca, Strati deboli persistenti

Punti pericolosi

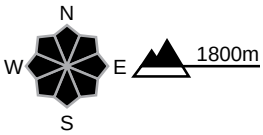

Descrizione del pericolo
Le grandi quantità di neve fresca e neve ventata ricoprono un debole manto di neve vecchia. Le valanghe possono distaccarsi in seguito al passaggio di un singolo appassionato di sport invernali. Esse possono in parte coinvolgere gli strati più profondi. Sono possibili sempre più numerose valanghe spontanee. Le valanghe possono raggiungere grandi dimensioni.
Le escursioni e le discese fuori pista richiedono attenzione e prudenza.

regione F — Marcato (3+)

Neve fresca, Strati deboli persistenti

Punti pericolosi

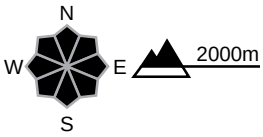

Descrizione del pericolo
La neve fresca e la neve ventata ricoprono un debole manto di neve vecchia. Le valanghe possono distaccarsi negli strati più profondi e raggiungere grandi dimensioni. Sono possibili distacchi a distanza. I rumori di "whum" e la formazione di fessure quando si calpesta la coltre di neve così come nuove valanghe sono segnali da ricondurre a questo pericolo.
Le escursioni e le discese fuori pista richiedono molta esperienza nella valutazione del pericolo di valanghe e cautela.

regione G — Marcato (3+)

Strati deboli persistenti

Punti pericolosi

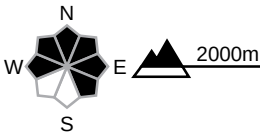

Descrizione del pericolo
Gli strati deboli molto pronunciati presenti nella neve vecchia richiedono attenzione. Le valanghe possono distaccarsi negli strati più profondi e raggiungere grandi dimensioni a livello isolato. I punti pericolosi sono frequenti. Si prevedono distacchi a distanza. I rumori di "whum" e la formazione di fessure quando si calpesta la coltre di neve così come nuove valanghe sono segnali da ricondurre a questo pericolo.
Le escursioni e le discese fuori pista richiedono molta esperienza nella valutazione del pericolo di valanghe e cautela.

regione H

Marcato (3=)

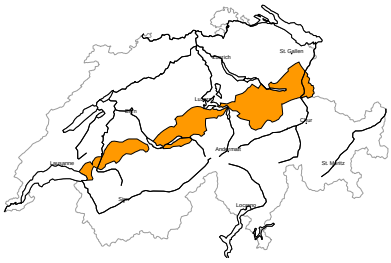

Neve fresca, Strati deboli persistenti

Punti pericolosi

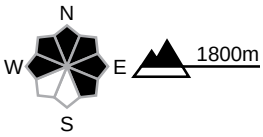

Descrizione del pericolo
La neve fresca e la neve ventata sono instabili. Le valanghe possono distaccarsi in seguito al passaggio di un singolo appassionato di sport invernali. Esse possono in parte coinvolgere gli strati più profondi e raggiungere grandi dimensioni.
Con le nevicate, nel corso della giornata il pericolo aumenterà ulteriormente. Sono possibili isolate valanghe spontanee.
Le escursioni richiedono esperienza nella valutazione del pericolo di valanghe.

Moderato (2)

Neve bagnata

Punti pericolosi

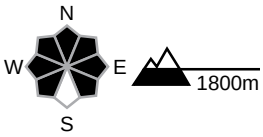

Descrizione del pericolo
Con la pioggia, sono previste colate e valanghe bagnate. Queste ultime possono raggiungere dimensioni medie. I punti pericolosi si trovano nelle conche e nei canaloni. Oltre al pericolo di seppellimento, occorre fare attenzione soprattutto al pericolo di trascinamento e caduta.

regione I

Marcato (3=)

Neve fresca, Strati deboli persistenti

Punti pericolosi

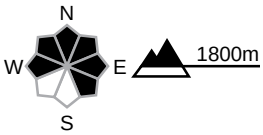

Descrizione del pericolo
La neve fresca e la neve ventata sono instabili. Le valanghe possono distaccarsi in seguito al passaggio di un singolo appassionato di sport invernali. Esse possono in parte coinvolgere gli strati più profondi e raggiungere grandi dimensioni.
Con le nevicate, nel corso della giornata il pericolo aumenterà ulteriormente. Sono possibili isolate valanghe spontanee.
Le escursioni richiedono esperienza nella valutazione del pericolo di valanghe.

regione J — Marcato (3=)

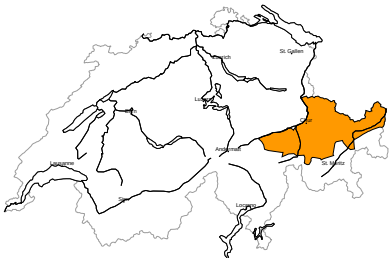

Strati deboli persistenti

Punti pericolosi

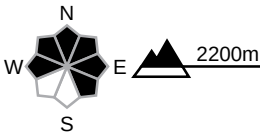

Descrizione del pericolo
Gli strati deboli presenti nella neve vecchia richiedono attenzione. Già un singolo appassionato di sport invernali può provocare il distacco di valanghe. Queste possono distaccarsi negli strati più profondi e raggiungere grandi dimensioni a livello isolato. Si prevedono distacchi a distanza. I rumori di "whum" e la formazione di fessure quando si calpesta la coltre di neve così come nuove valanghe sono possibili segnali di pericolo.
Le escursioni e le discese fuori pista richiedono molta esperienza nella valutazione del pericolo di valanghe.

regione K — Marcato (3=)

Strati deboli persistenti

Punti pericolosi

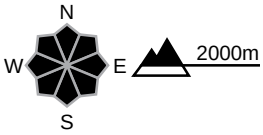

Descrizione del pericolo
Gli strati deboli presenti nella neve vecchia richiedono attenzione. Già un singolo appassionato di sport invernali può provocare il distacco di valanghe. Queste possono distaccarsi negli strati più profondi e raggiungere grandi dimensioni a livello isolato. Sono possibili distacchi a distanza. I rumori di "whum" e la formazione di fessure quando si calpesta la coltre di neve così come nuove valanghe sono possibili segnali di pericolo.
Le escursioni e le discese fuori pista richiedono molta esperienza nella valutazione del pericolo di valanghe.

regione L

Moderato (2+)

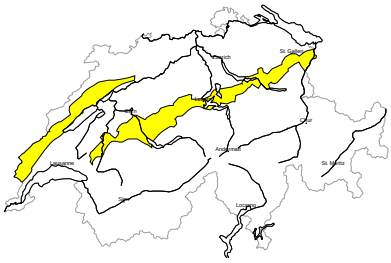

Lastroni da vento

Punti pericolosi

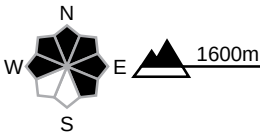

Descrizione del pericolo
Con neve fresca e vento forte proveniente da ovest si formeranno accumuli di neve ventata in parte instabili. Le valanghe possono raggiungere dimensioni medie. I nuovi accumuli di neve ventata dovrebbero essere valutati con attenzione soprattutto sui pendii molto ripidi.

Moderato (2)

Neve bagnata

Punti pericolosi

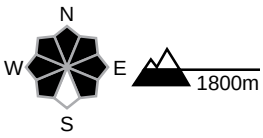

Descrizione del pericolo
Con la pioggia, sono previste colate e valanghe bagnate. Queste ultime possono raggiungere dimensioni medie. I punti pericolosi si trovano nelle conche e nei canaloni. Oltre al pericolo di seppellimento, occorre fare attenzione soprattutto al pericolo di trascinamento e caduta.

regione M

Moderato (2+)

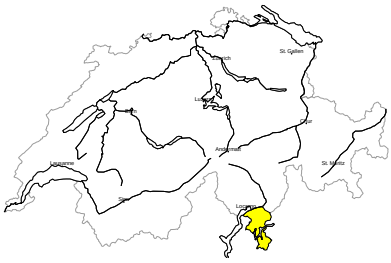

Strati deboli persistenti

Punti pericolosi

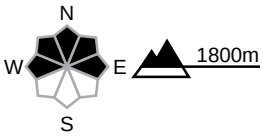

Descrizione del pericolo
All'interno del manto di neve vecchia si trovano pronunciati strati fragili. In alcuni punti, le valanghe possono subire un distacco in seguito al passaggio di un singolo appassionato di sport invernali. Le valanghe possono distaccarsi negli strati più profondi e raggiungere dimensioni medie.
Le escursioni e le discese fuori pista richiedono una prudente scelta dell'itinerario.

Manto nevoso e meteo

aggiornato al 10.2.2026, 17:00

Manto nevoso

In tutte le regioni l'innevamento è nettamente inferiore rispetto al solito in questo periodo, soprattutto alle quote di bassa e media montagna. Gli apporti di neve fresca previsti nei prossimi giorni, che nelle regioni occidentali e settentrionali saranno abbondanti, si depositeranno su un manto nevoso che in molti casi presenta una struttura sfavorevole. In molti punti la superficie del manto nevoso ha subito un metamorfismo costruttivo e risulta scarsamente coesa. Inoltre, specialmente sui pendii esposti a ovest, a nord e a est, nella parte centrale e basale del manto nevoso sono presenti pronunciati strati fragili instabili, in particolare a sud di una linea Rodano-Reno. A nord della stessa, la struttura del manto è leggermente più favorevole, ma anche in queste regioni la parte basale ingloba strati fragili. Data questa situazione di partenza, soprattutto nelle regioni occidentali e settentrionali si prospetta un rapido e pronunciato aumento del pericolo di valanghe.

Retrospettiva meteo fino a martedì

Martedì il cielo è stato coperto. In quasi tutte le regioni ci sono state deboli precipitazioni, con un limite delle nevicate collocato fra i 1000 e i 1500 m.

Neve fresca
Fino a lunedì pomeriggio sono cadute le seguenti quantità di neve:
- Giura, Basso Vallese occidentale estremo, parte settentrionale del Basso Vallese, Ticino: dai 5 ai 15 cm
- Altrove: meno o tempo asciutto

Temperatura
Sul mezzogiorno a 2000 m compresa tra -2 °C nelle regioni settentrionali e -4 °C in quelle meridionali

Vento
In intensificazione, proveniente da ovest a sud ovest, nel pomeriggio:
- nel Giura e sul versante nordalpino da moderato a forte
- altrimenti da debole a moderato

Previsioni meteo fino a mercoledì

Nelle regioni settentrionali il cielo sarà molto nuvoloso con precipitazioni, che saranno più intense nella parte occidentale estrema e settentrionale del Basso Vallese, come pure nelle Alpi Vodesi. Nella notte fra martedì e mercoledì, nelle regioni occidentali il limite delle nevicate salirà fin verso i 2000 m, per poi scendere verso i 1300 m. Nel Vallese si collocherà a tratti anche più in basso. Nella notte fra martedì e mercoledì, nelle regioni meridionali il tempo sarà molto nuvoloso con deboli precipitazioni. Nel corso della giornata il cielo diventerà piuttosto soleggiato.

Neve fresca
Al di sopra dei 2200 m cadranno le seguenti quantità di neve:
- Parte occidentale estrema e settentrionale del Basso Vallese, Alpi Vodesi: dai 50 agli 80 cm
- Resto del versante nordalpino occidentale e centrale, restante Vallese: dai 30 ai 50 cm
- Versante nordalpino orientale, zona del Sempione sud, nord del Ticino, Surselva e Prettigovia: dai 15 ai 30 cm
- Resto del Ticino e resto dei Grigioni: dai 5 ai 15 cm

Temperatura
Sul mezzogiorno a 2000 m compresa tra -2 °C nelle regioni settentrionali e 0 °C in quelle meridionali

Vento
- Lungo le Prealpi, nelle regioni occidentali e settentrionali in quota da forte a tempestoso, proveniente da ovest a sud ovest
- In Ticino e nei Grigioni per lo più moderato, inizialmente proveniente da sud ovest, poi da nord ovest

Tendenza per giovedì e venerdì

Giovedì
Nelle regioni settentrionali il cielo sarà ancora molto nuvoloso, con precipitazioni in parte persistenti e abbondanti. Soprattutto sul versante nordalpino e nelle regioni occidentali il vento proveniente da ovest sarà ancora da forte a tempestoso. Si prevedono ulteriori apporti di neve fresca, simili a quelli del giorno precedente. Il limite delle nevicate si collocherà tra i 1100 e i 1300 m.
In generale, il pericolo di valanghe aumenterà ancora, nelle regioni più colpite dalle precipitazioni all'interno del grado 4. Qui si prevedono sempre più spesso valanghe di dimensioni molto grandi, che potranno avanzare fino a valle lungo i percorsi abituali e minacciare i tratti esposti delle vie di comunicazione.

Venerdì
Nella notte fra giovedì e venerdì, sul versante nordalpino, nel Basso Vallese e in Prettigovia cadranno ancora dai 20 ai 40 cm di neve, nel restante Vallese e nei Grigioni meno. Il limite delle nevicate si collocherà tra i 1000 e i 1200 m. Sul versante sudalpino il tempo sarà asciutto. Nel corso della giornata, sul versante nordalpino il tempo sarà variamente nuvoloso, nel Vallese e nelle regioni meridionali per lo più soleggiato. Il vento proveniente da ovest si attenuerà nettamente.
Nella notte fra giovedì e venerdì il pericolo di valanghe aumenterà ancora leggermente' e potrà raggiungere il grado di pericolo 4 anche sul versante nordalpino orientale e nel nord dei Grigioni. Sul versante nordalpino saranno possibili valanghe di dimensioni molto grandi, che potranno avanzare fino a valle e minacciare i tratti esposti delle vie di comunicazione. Nei Grigioni il pericolo si riferisce invece soprattutto alle zone fuoripista frequentate dagli appassionati di sport invernali.