Freitag 13.02.2026

Veröffentlicht am 12.02.2026 um 17:00

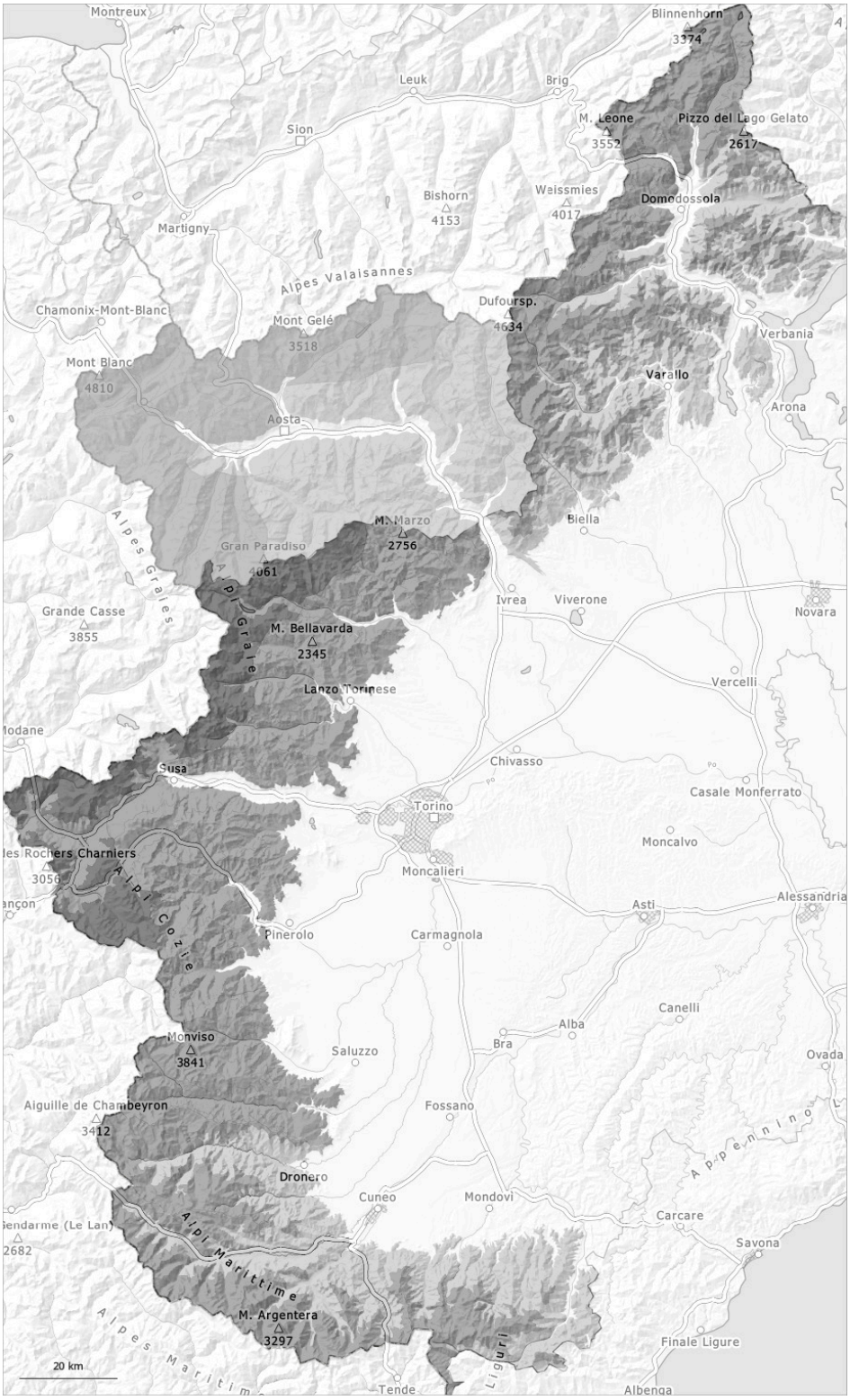

1	2	3	4	5
gering	mäßig	erheblich	groß	sehr groß

Gefahrenstufe 4 - Groß

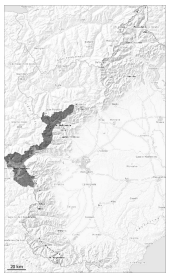

Waldgrenze

Tendenz: Lawinengefahr nimmt ab
am Samstag, den 14.02.2026

Triebschnee

Waldgrenze

Neuschnee

Waldgrenze

Neu- und Triebschnee: Aus hoch gelegenen Einzugsgebieten muss mit spontanen großen Lawinen gerechnet werden.

Mit Neuschnee und Sturm wuchsen die Triebschneeansammlungen stark an. Dies vor allem in Rinnen, Mulden und hinter Geländekanten sowie kammfern oberhalb der Waldgrenze. Entlang der Grenze zu Frankreich sind die Gefahrenstellen häufiger und größer.

Neu- und Triebschnee können an vielen Stellen leicht ausgelöst werden und groß werden. Zudem können Lawinen auch tiefere Schichten der Schneedecke mitreißen und sehr groß werden. Exponierte Teile von Verkehrswegen können dann lokal gefährdet sein.

Schneedecke

Gefahrenmuster gm.6: lockerer schnee und wind

Am Mittwoch fielen oberhalb von rund 1800 m 15 bis 25 cm Schnee. Am Donnerstag fielen oberhalb von rund 2000 m 15 bis 30 cm Schnee, lokal auch mehr. Mit Neuschnee und mäßigem bis starkem Wind aus nordwestlichen Richtungen entstanden vor allem oberhalb der Waldgrenze weitere Triebschneeansammlungen. Neu- und Triebschnee liegen an windgeschützten Schattenhängen auf weichen Schichten.

Mittlere und hohe Lagen: Im unteren Teil der Altschneedecke sind vor allem an Schattenhängen grobkörnige Schwachschichten vorhanden.
Ab dem Nachmittag fällt etwas Schnee.

Tendenz

Die spontane Lawinenaktivität nimmt mit dem Ende der Niederschläge allmählich ab. Entlang der Grenze zu Frankreich und an Triebschneehängen ist die Auslösebereitschaft hoch. Die Lawinen können vor allem aus noch nicht entladenen Einzugsgebieten abgehen.

Gefahrenstufe 3 - Erheblich

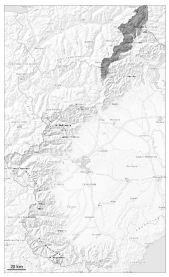

Tendenz: Lawinengefahr bleibt gleich
am Samstag, den 14.02.2026

1700m

Triebschnee

Neuschnee

Neu- und Triebschnee sind die Hauptgefahr. Dies vor allem in den Hauptniederschlagsgebieten.

Mit Neuschnee und starkem Wind aus nordwestlichen Richtungen entstanden verbreitet Triebschneeansammlungen. Dies vor allem in Rinnen, Mulden und hinter Geländekanten besonders oberhalb der Waldgrenze.

Neu- und Triebschnee können schon von einzelnen Wintersportlern ausgelöst werden und groß werden.

Zudem können Lawinen auch in tiefen Schichten ausgelöst werden und v.a. an Schattenhängen vereinzelt sehr groß werden.
Eine überlegte Routenwahl ist nötig. Entlastungsabstände und Einzelabfahrten werden empfohlen.

Schneedecke

Gefahrenmuster gm.6: lockerer schnee und wind

Am Mittwoch fielen oberhalb von rund 1500 m 10 bis 20 cm Schnee. Am Donnerstag fielen oberhalb von rund 1800 m verbreitet 10 bis 20 cm Schnee. Mit Neuschnee und mäßigem bis starkem Wind aus nordwestlichen Richtungen entstanden vor allem oberhalb der Waldgrenze weitere Triebschneeansammlungen. Neu- und Triebschnee liegen an windgeschützten Schattenhängen auf weichen Schichten.

Mittlere und hohe Lagen: Im unteren Teil der Schneedecke sind vor allem an Schattenhängen grobkörnige Schwachschichten vorhanden.
Hohe Lagen und Hochgebirge: Der teilweise starke Wind hat Neu- und Altschnee intensiv verfrachtet. Ab dem Nachmittag fällt etwas Schnee.

Gefahrenstufe 3 - Erheblich

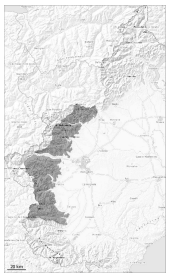

Tendenz: Lawinengefahr bleibt gleich
am Samstag, den 14.02.2026

1800m

Triebschnee

Neuschnee

Neu- und Triebschnee sind die Hauptgefahr. In den an die Gefahrenstufe 4, "groß" angrenzenden Gebieten sind die Gefahrenstellen häufiger.

Der Neuschnee sowie die Triebschneeansammlungen müssen an allen Expositionen oberhalb von rund 1800 m vorsichtig beurteilt werden. Die Gefahrenstellen liegen besonders in Rinnen, Mulden und hinter Geländekanten sowie an Triebschneehängen.
In der Höhe sind diese Gefahrenstellen häufiger.

Neu- und Triebschnee können schon von einzelnen Wintersportlern ausgelöst werden oder spontan abgehen. Zudem können Lawinen auch im Altschnee anbrechen und groß werden.

Eine vorsichtige Routenwahl und Entlastungsabstände werden empfohlen.

Schneedecke

Gefahrenmuster gm.6: lockerer schnee und wind

Am Mittwoch fielen oberhalb von rund 1800 m 5 bis 15 cm Schnee. Am Donnerstag fielen oberhalb von rund 2000 m 5 bis 10 cm Schnee, lokal auch mehr.
Der teilweise stürmische Wind hat den Neuschnee intensiv verfrachtet. Die Triebschneeansammlungen liegen vor allem an Schattenhängen auf weichen Schichten.

Die ungewöhnlichen Wetterbedingungen führen zu einem ungünstigen Aufbau der Schneedecke.
Mittlere und hohe Lagen: Im unteren Teil der Schneedecke sind vor allem an Schattenhängen grobkörnige Schwachschichten vorhanden.
Ab dem Nachmittag fällt Schnee oberhalb von rund 1200 m.

Gefahrenstufe 3 - Erheblich

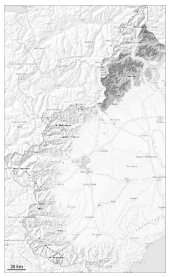

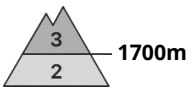

Tendenz: Lawinengefahr bleibt gleich
am Samstag, den 14.02.2026

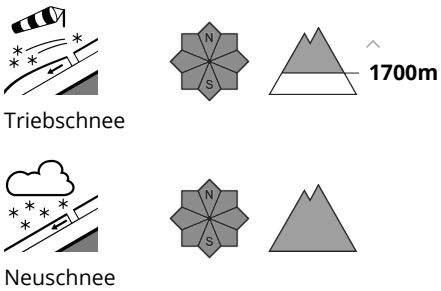

Neu- und Triebschnee sind die Hauptgefahr. In der Höhe erhebliche Lawinengefahr.

Der Neuschnee sowie die Triebschneeansammlungen müssen an allen Expositionen oberhalb von rund 1700 m vorsichtig beurteilt werden. Die Gefahrenstellen liegen besonders in Kammlagen, Rinnen und Mulden sowie an steilen Hängen.
In der Höhe sind diese Gefahrenstellen häufiger.

Neu- und Triebschnee können schon von einzelnen Wintersportlern ausgelöst werden oder spontan abgehen. Zudem können Lawinen auch im Altschnee anbrechen und groß werden.

Eine vorsichtige Routenwahl und Entlastungsabstände werden empfohlen.

Schneedecke

Gefahrenmuster gm.6: lockerer schnee und wind

Am Mittwoch fielen verbreitet oberhalb von rund 1800 m 10 bis 20 cm Schnee. Am Donnerstag fielen 5 bis 10 cm Schnee. Der starke Wind hat den Neuschnee und teilweise auch Altschnee verfrachtet.
Die Triebschneeansammlungen liegen vor allem an Schattenhängen auf weichen Schichten.

Im unteren Teil der Schneedecke sind an Schattenhängen einzelne Schwachschichten vorhanden. Dies vor allem in der Höhe. Ab dem Nachmittag fällt etwas Schnee.

Gefahrenstufe 3 - Erheblich

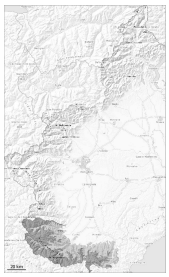

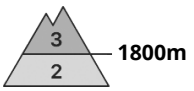

Tendenz: Lawinengefahr steigt
am Samstag, den 14.02.2026

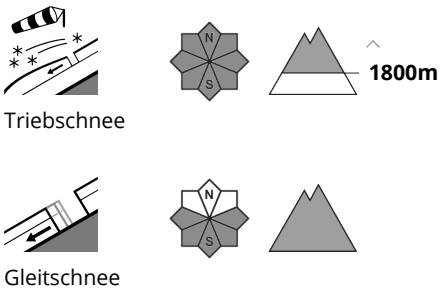

Die Triebschneeansammlungen bleiben in mittleren und hohen Lagen bis auf weiteres störanfällig. Entlang der Grenze zu Frankreich sind die Gefahrenstellen häufiger.

Frischere Triebschneeansammlungen können an allen Expositionen und allgemein in der Höhe von einzelnen Wintersportlern ausgelöst werden. Dies vor allem an steilen Hängen und in Kammlagen, Rinnen und Mulden.
Die Lawinen können in den verschiedenen Neu- und Triebschneeschichten anreißen und groß werden. Zudem sind einzelne Gleitschneelawinen möglich. Dies vor allem an steilen Süd- und Westhängen unterhalb von rund 2200 m an Grashängen.

Eine vorsichtige Routenwahl und Entlastungsabstände werden empfohlen.

Schneedecke

Gefahrenmuster gm.6: lockerer schnee und wind | gm.2: gleitschnee

Mit hohen Temperaturen und Regen bis in mittlere Lagen konnte sich die Schneedecke in den letzten Tagen nicht verfestigen. Der teilweise starke Wind hat Schnee verfrachtet.
Die ungewöhnlichen Wetterbedingungen führten zu einem ungünstigen Aufbau der Schneedecke. Oberhalb von rund 1500 m liegt viel Schnee.