aineva.it

Venerdì 13.02.2026

Pubblicato il 12.02.2026 alle ore 17:00

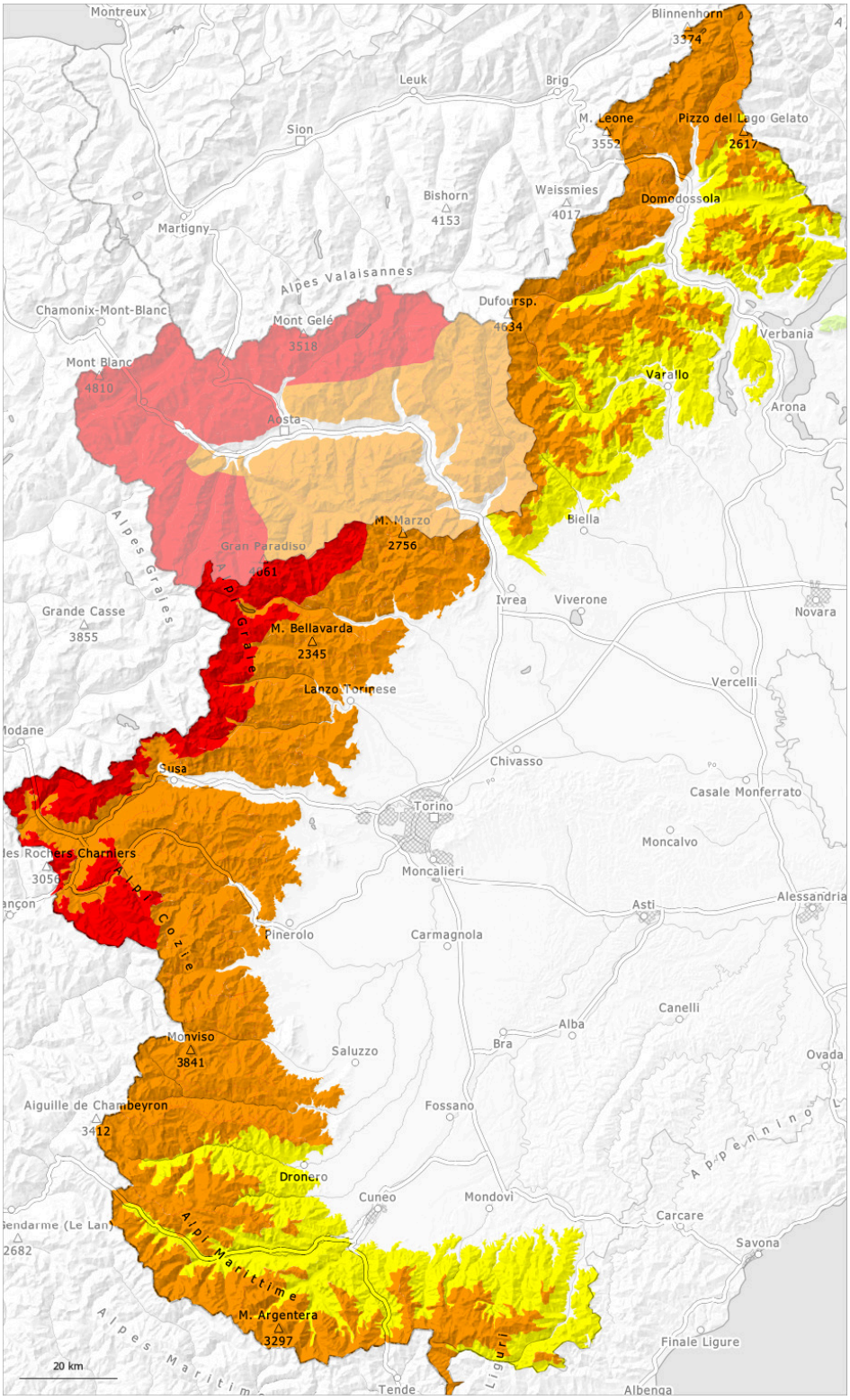

1	2	3	4	5
debole	moderato	marcato	forte	molto forte

Grado di pericolo 4 - Forte

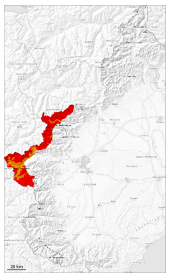

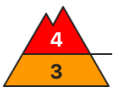

Limite del bosco

Tendenza: pericolo valanghe in diminuzione
per Sabato il 14.02.2026

Lastrone da vento

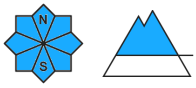

Limite del bosco

Neve fresca

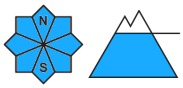

Limite del bosco

Neve fresca e neve ventata: Dai bacini di alimentazione in quota si prevedono valanghe spontanee di grandi dimensioni.

Con neve fresca e vento tempestoso, gli accumuli di neve ventata sono considerevolmente cresciuti. Ciò soprattutto nelle conche, nei canaloni e dietro ai cambi di pendenza, come pure nelle zone lontano dalle creste al di sopra del limite del bosco. Lungo il confine con la Francia i punti pericolosi sono più numerosi e grandi.

La neve fresca e la neve ventata possono in molti punti distaccarsi facilmente e raggiungere grandi dimensioni. Inoltre, le valanghe possono anche trascinare gli strati più profondi del manto nevoso e raggiungere dimensioni molto grandi. In questo caso, i tratti esposti delle vie di comunicazione potranno localmente essere in pericolo.

Manto nevoso

Situazione tipo st.6: neve a debole coesione e vento

Mercoledì sono caduti da 15 a 25 cm di neve al di sopra dei 1800 m circa. Giovedì sono caduti da 15 a 30 cm di neve al di sopra dei 2000 m circa, localmente anche di più. Con neve fresca e vento da moderato a forte proveniente dai quadranti nord occidentali soprattutto al di sopra del limite del bosco si sono formati ulteriori accumuli di neve ventata. La neve fresca e la neve ventata poggiano su strati soffici sui pendii riparati dal vento ombreggiati.

Alle quote medie e alte: Soprattutto sui pendii ombreggiati, nella parte basale del manto di neve vecchia si trovano strati fragili a grani grossi.
A partire dal pomeriggio cadrà un po' di neve.

Tendenza

Con il cessare delle precipitazioni, l'attività di valanghe spontanee diminuirà progressivamente. Lungo il

confine con la Francia e sui pendii carichi di neve ventata la probabilità di distacco è alta. Le valanghe possono distaccarsi soprattutto dai bacini di alimentazione non ancora scaricati.

Grado di pericolo 3 - Marcato

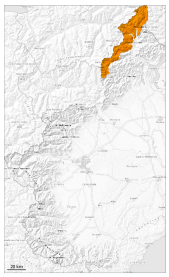

Tendenza: pericolo valanghe stabile
per Sabato il 14.02.2026

Lastrone da vento

1700m

Neve fresca

Neve fresca e neve ventata sono la principale fonte di pericolo. Ciò soprattutto nelle regioni più colpite dalle precipitazioni.

Con neve fresca e vento forte proveniente dai quadranti nord occidentali in molti punti si sono formati accumuli di neve ventata. Ciò soprattutto nelle conche, nei canaloni e dietro ai cambi di pendenza principalmente al di sopra del limite del bosco.

La neve fresca e la neve ventata possono distaccarsi già in seguito al passaggio di un singolo appassionato di sport invernali e raggiungere grandi dimensioni.

Inoltre, le valanghe possono anche subire un distacco negli strati più profondi e, specialmente sui pendii ombreggiati, raggiungere dimensioni molto grandi a livello isolato.
È necessaria un'accurata scelta dell'itinerario. Si raccomandano distanze di scarico e discese singole.

Manto nevoso

Situazione tipo st.6: neve a debole coesione e vento

Mercoledì sono caduti da 10 a 20 cm di neve al di sopra dei 1500 m circa. Giovedì sono caduti diffusamente da 10 a 20 cm di neve al di sopra dei 1800 m circa. Con neve fresca e vento da moderato a forte proveniente dai quadranti nord occidentali soprattutto al di sopra del limite del bosco si sono formati ulteriori accumuli di neve ventata. La neve fresca e la neve ventata poggiano su strati soffici sui pendii riparati dal vento ombreggiati.

Alle quote medie e alte: Soprattutto sui pendii ombreggiati, nella parte basale del manto nevoso si trovano strati fragili a grani grossi.
Ad alta quota e in alta montagna: Il vento a tratti forte ha rimaneggiato intensamente la neve fresca e la neve vecchia. A partire dal pomeriggio cadrà un po' di neve.

Grado di pericolo 3 - Marcato

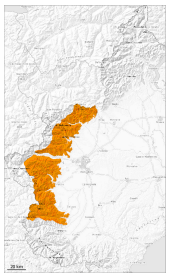

Tendenza: pericolo valanghe stabile
per Sabato il 14.02.2026

Lastrone da vento

1800m

Neve fresca

Neve fresca e neve ventata sono la principale fonte di pericolo. Nelle regioni confinanti con quelle interessate dal grado di pericolo 4 "forte" i punti pericolosi sono più numerosi.

La neve fresca così come gli accumuli di neve ventata devono essere valutati con attenzione a tutte le esposizioni al di sopra dei 1800 m circa. I punti pericolosi si trovano principalmente nelle conche, nei canaloni e dietro ai cambi di pendenza come pure sui pendii carichi di neve ventata.
In quota questi punti pericolosi sono più numerosi.

La neve fresca e la neve ventata possono distaccarsi già in seguito al passaggio di un singolo appassionato di sport invernali oppure spontaneamente. Inoltre, le valanghe possono anche coinvolgere il manto di neve vecchia e raggiungere grandi dimensioni.

Si consiglia una prudente scelta dell'itinerario e di mantenere le distanze di scarico.

Manto nevoso

Situazione tipo st.6: neve a debole coesione e vento

Mercoledì sono caduti da 5 a 15 cm di neve al di sopra dei 1800 m circa. Giovedì sono caduti da 5 a 10 cm di neve al di sopra dei 2000 m circa, localmente anche di più.
Il vento a tratti tempestoso ha rimaneggiato intensamente la neve fresca. Gli accumuli di neve ventata poggiano su strati soffici soprattutto sui pendii ombreggiati.

Le condizioni meteo insolite causeranno una sturttura sfavorevole del manto nevoso.
Alle quote medie e alte: Soprattutto sui pendii ombreggiati, nella parte basale del manto nevoso si trovano strati fragili a grani grossi.
A partire dal pomeriggio cadrà neve al di sopra dei 1200 m circa.

Grado di pericolo 3 - Marcato

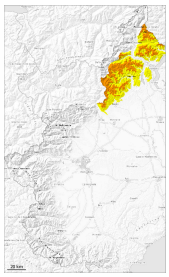

1700m

Tendenza: pericolo valanghe stabile
per Sabato il 14.02.2026

Lastrone da vento

1700m

Neve fresca

Neve fresca e neve ventata sono la principale fonte di pericolo. In quota marcato pericolo di valanghe.

La neve fresca così come gli accumuli di neve ventata devono essere valutati con attenzione a tutte le esposizioni al di sopra dei 1700 m circa. I punti pericolosi si trovano principalmente nelle zone in prossimità delle creste, nelle conche e nei canaloni come pure sui pendii ripidi.
In quota questi punti pericolosi sono più numerosi.

La neve fresca e la neve ventata possono distaccarsi già in seguito al passaggio di un singolo appassionato di sport invernali oppure spontaneamente. Inoltre, le valanghe possono anche coinvolgere il manto di neve vecchia e raggiungere grandi dimensioni.

Si consiglia una prudente scelta dell'itinerario e di mantenere le distanze di scarico.

Manto nevoso

Situazione tipo st.6: neve a debole coesione e vento

In molte regioni mercoledì sono caduti da 10 a 20 cm di neve al di sopra dei 1800 m circa. Giovedì sono caduti da 5 a 10 cm di neve. Il forte vento ha causato il trasporto della neve fresca e, in parte, anche della neve vecchia.
Gli accumuli di neve ventata poggiano su strati soffici soprattutto sui pendii ombreggiati.

Sui pendii ombreggiati, nella parte basale del manto nevoso si trovano isolati strati fragili. Ciò soprattutto in quota. A partire dal pomeriggio cadrà un po' di neve.

Grado di pericolo 3 - Marcato

Tendenza: pericolo valanghe in aumento
per Sabato il 14.02.2026

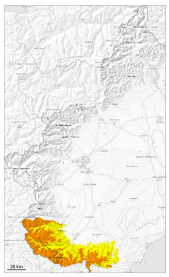

Lastrone da vento

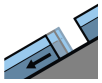

Valanghe di slittamento

Gli accumuli di neve ventata rimangono ancora instabili alle quote medie e alte. Lungo il confine con la Francia i punti pericolosi sono più numerosi.

Gli ultimi accumuli di neve ventata possono subire un distacco in seguito al passaggio di un singolo appassionato di sport invernali a tutte le esposizioni e per lo più in quota. Ciò soprattutto sui pendii ripidi e nelle zone in prossimità delle creste, nelle conche e nei canaloni.
Le valanghe possono coinvolgere i vari strati di neve fresca e ventata e raggiungere grandi dimensioni. Inoltre sono possibili isolate valanghe per scivolamento di neve. Ciò soprattutto sui pendii ripidi esposti a sud e ovest al di sotto dei 2200 m circa sui pendii erbosi.

Si consiglia una prudente scelta dell'itinerario e di mantenere le distanze di scarico.

Manto nevoso

Situazione tipo st.6: neve a debole coesione e vento | st.2: neve da slittamento

Con le alte temperature e la pioggia fino alle quote di media montagna, negli ultimi giorni il manto nevoso non è riuscito a consolidarsi. Il vento a tratti forte ha causato il trasporto della neve.
Le condizioni meteo insolite hanno causato una sturttura sfavorevole del manto nevoso.
Al di sopra dei 1500 m circa è presente molta neve.