ICGC Institut Cartogràfic i Geològic de Catalunya

Servei Meteorològic de Catalunya meteo.cat

Boletín de peligro de aludes para el Pirineo de Catalunya
Del 12/02/2026 al 13/02/2026

(Válido fuera pistas de esquí y zonas no controladas)

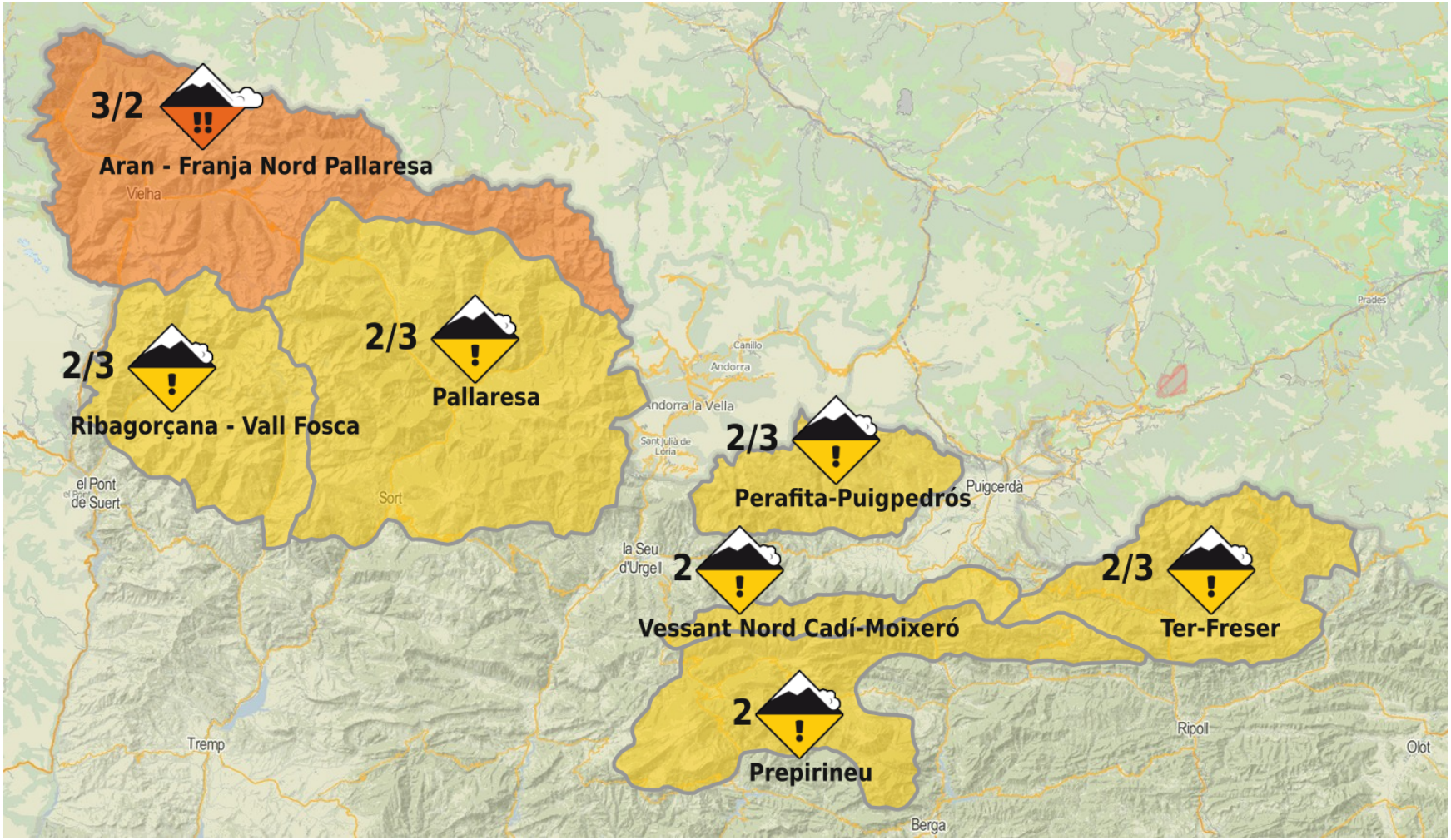

5 MUY FUERTE	4 FUERTE	3 NOTABLE	2 LIMITADO	1 DÉBIL

ICGC Institut Cartogràfic i Geològic de Catalunya

meteo.cat Servei Meteorològic de Catalunya

Boletín de peligro de aludes Aran - Franja Nord Pallaresa Del 12/02/2026 al 13/02/2026

(Válido fuera pistas de esquí y zonas no controladas)

NOTABLE (3), por encima del límite del bosque. LIMITADO (2), en el resto.

Situación primaria

Nieve venteada

Distribución

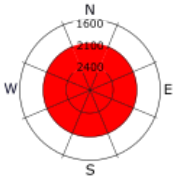

Tamaño

Origen

Tendencia

Situación secundaria

Deslizamientos basales

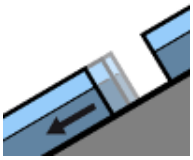

Distribución

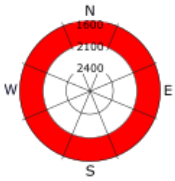

Tamaño

Origen

Tendencia

Estado del manto nivoso

El fuerte viento ha deflactado las vertientes orientadas a Oeste. En superficie, encontramos costras resbaladizas, vidriosas, y partículas muy fragmentadas y algo de nieve granulada. Aparecen surcos, por la lluvia y el calor del pasado martes, entre los 1.800 m y los 2.200 m. Para el viernes, con los chubascos y el viento fuerte del SW y del NW previstos se formarán nuevas placas de viento. Estas placas las encontraremos por encima del límite del bosque, bajo collados y cordales, en cualquier orientación, preferentemente, en Nordeste, Este y Sudeste. Podrán caer de forma natural o romperse fácilmente con el paso de un montañero y generar aludes de hasta tamaño medio, con capacidad de enterrar a una persona. No se descarta algún deslizamiento basal de hasta tamaño medio, por debajo de los 2.100 m. Vigile con los resbalones por la presencia de costras vidriosas en la superficie del manto. Lleve el material de seguridad habitual (pala, DVA y sonda), además del casco, crampones y piolet.

Distribución del manto nivoso

Hay nieve en el suelo a 1.400 m en Norte. El manto es esquiable por encima de unos 1.500 m en umbrías y a partir de los 1.800 m en solanas. Los espesores a unos 2.200 m rondan los 110-140 cm en el norte de Arán y 140-190 cm en la Franja Norte Pallaresa y en el sur de Aran, y son superiores a los normales por estas fechas.

Tendencia para las próximas 48-72h

El fuerte viento del Norte y las nuevas nevadas harán aumentar los aludes de placa de viento y nieve reciente seca. Peligro EN ASCENSO.

El próximo boletín será emitido el día 2026-02-13

5 MUY FUERTE	4 FUERTE	3 NOTABLE	2 LIMITADO	1 DÉBIL

EAWS EUROPEAN AVALANCHE WARNING SERVICES

ICGC Institut Cartogràfic i Geològic de Catalunya

Servei Meteorològic de Catalunya

Boletín de peligro de aludes Ribagorçana - Vall Fosca Del 12/02/2026 al 13/02/2026

(Válido fuera pistas de esquí y zonas no controladas)

LIMITADO (2), debajo de los 2.200 m. NOTABLE (3), por encima, a partir de la tarde.

Situación primaria

Nieve venteada

Distribución

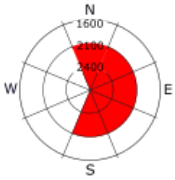

Tamaño

Origen

Tendencia

Estado del manto nivoso

El manto, superficialmente, se muestra bastante endurecido, con la presencia de costras duras, en muchos casos vidriosas y resbaladizas. Por debajo seguimos encontrando costras que se alternan con grano fino y formas mixtas. En altura se ha observado transporte de la nieve más seca, con la formación de nuevas placas. Además, con la leve nevada y el viento fuerte previstos, el viernes encontraremos nuevas placas de viento. Estas placas se habrán formado por encima del límite del bosque y, al romperse al paso de un montañero, podrán generar aludes, de hasta tamaño medio (con capacidad de enterrar a una persona). Las placas se formarán, en especial en vertiente E, NE y SE, bajo collados y cordales. Hay que vigilar con los resbalones por la presencia de costras vidriosas en la superficie del manto. Lleve el material de seguridad habitual (pala, DVA y sonda), además del casco, crampones y el piolet.

Distribución del manto nivoso

Hay nieve en el suelo a 1.500 m. El manto es esquiable por encima de unos 1500-1600 m. Los grosores alcanzan los 130-160 cm. Estos valores son muy superiores a los normales en la época.

Tendencia para las próximas 48-72h

Con el fuerte viento y las nuevas nevadas previstas, durante el fin de semana, seguirá el problema por placa de viento. Peligro EN ASCENSO.

El próximo boletín será emitido el día 2026-02-13

5 MUY FUERTE	4 FUERTE	3 NOTABLE	2 LIMITADO	1 DÉBIL

EAWS EUROPEAN AVALANCHE WARNING SERVICES

ICGC Institut Cartogràfic i Geològic de Catalunya

Servei Meteorològic de Catalunya meteo.cat

Boletín de peligro de aludes Pallaresa
Del 12/02/2026 al 13/02/2026

(Válido fuera pistas de esquí y zonas no controladas)

LIMITADO(2), debajo de los 2.300 m. NOTABLE (3), por encima, a partir de la tarde.

Situación primaria

Nieve venteada

Distribución

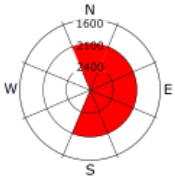

Tamaño

Origen

Tendencia

Estado del manto nivoso

El manto, superficialmente, se muestra bastante endurecido, con la presencia de costras duras, en muchos casos vidriosas y resbaladizas. Por debajo seguimos encontrando costras que se alternan con grano fino y formas mixtas. En altura se ha observado transporte de la nieve más seca, con la formación de nuevas placas. Además, con la leve nevada y el viento fuerte previstos, el viernes encontraremos nuevas placas de viento. Estas placas se habrán formado por encima del límite del bosque y, al romperse al paso de un montañero, podrán generar aludes, de hasta tamaño medio (con capacidad de enterrar a una persona). Las placas se formarán, en especial en vertiente E, NE y SE, bajo collados y cordales. Hay que vigilar con los resbalones por la presencia de costras vidriosas en la superficie del manto. Lleve el material de seguridad habitual (pala, DVA y sonda), además del casco, crampones y el piolet.

Distribución del manto nivoso

Hay nieve desde los 1600 m. Los espesores en cotas altas y medias superan los 140-150 cm. Estos valores son superiores a los normales para la época.

Tendencia para las próximas 48-72h

Con el fuerte viento y las nuevas nevadas previstas, durante el fin de semana, seguirá el problema por placa de viento. Peligro EN ASCENSO.

El próximo boletín será emitido el día 2026-02-13

5 MUY FUERTE	4 FUERTE	3 NOTABLE	2 LIMITADO	1 DÉBIL

EAWS EUROPEAN AVALANCHE WARNING SERVICES

ICGC Institut Cartogràfic i Geològic de Catalunya

Servei Meteorològic de Catalunya

Boletín de peligro de aludes Perafita-Puigpedrós Del 12/02/2026 al 13/02/2026

(Válido fuera pistas de esquí y zonas no controladas)

LIMITADO (2), debajo de los 2.300 m. NOTABLE (3), por encima, a partir de la tarde.

Situación primaria

Nieve venteada

Distribución

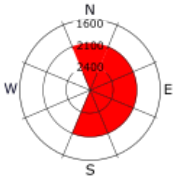

Tamaño

Origen

Tendencia

Estado del manto nivoso

El manto, superficialmente, se muestra bastante endurecido, con la presencia de costras duras. Por debajo seguimos encontrando costras que se alternan con grano fino y formas mixtas. En altura se ha observado transporte de la nieve más seca, con la formación de nuevas placas. Además, con la leve nevada y el viento fuerte previstos, el viernes encontraremos nuevas placas de viento. Estas placas se habrán formado por encima de los 2.300 my, al romperse al paso de un montañero, podrán generar aludes, de hasta tamaño medio (con capacidad de enterrar a una persona). Las placas se formarán, en especial en vertiente E, NE y SE, bajo collados y cordales. Hay que vigilar con los resbalones por la presencia de costras vidriosas en la superficie del manto. Lleve el material de seguridad habitual (pala, DVA y sonda), además del casco, crampones y el piolet.

Distribución del manto nivoso

Hay nieve en el suelo por encima de 1.400-1500 m. Sin embargo, el manto es esquiable por encima de 1.500-1.600 m. Los grosores alcanzan los 130-150 cm a 2.200 m. Son grosores muy por encima de los habituales por la época.

Tendencia para las próximas 48-72h

Con el fuerte viento y las nuevas nevadas previstas, durante el fin de semana, seguirá el problema por placa de viento. Peligro EN ASCENSO.

El próximo boletín será emitido el día 2026-02-13

5 MUY FUERTE	4 FUERTE	3 NOTABLE	2 LIMITADO	1 DÉBIL

EAWS EUROPEAN AVALANCHE WARNING SERVICES

ICGC Institut Cartogràfic i Geològic de Catalunya

Servei Meteorològic de Catalunya

Boletín de peligro de aludes
Vessant Nord Cadí-Moixeró
Del 12/02/2026 al 13/02/2026

(Válido fuera pistas de esquí y zonas no controladas)

LIMITADO (2).

Situación primaria

Nieve venteada

Distribución

Tamaño

Origen

Tendencia

Estado del manto nivoso

El manto se muestra endurecido, superficialmente, con una corteza de lluvia, dura, y por debajo aparece grano fino y formas mixtas, intercaladas con más costras. El patrón principal será el de la placa de viento y nieve más seca, con el descenso térmico previsto. Con los chubascos y el fuerte viento previsto podremos encontrar alguna placa nueva, pequeña, con mayor probabilidad en lo alto de las Canales del Cadí o bajo collados y crestas elevadas del Moixeró. Por lo general, las encontraremos en vertientes Este, Norte y Sur. Si se rompen las placas, al paso de un montañero, podrán generar aludes de pequeño tamaño, sin capacidad para enterrar a una persona. De manera local, allí donde haya más acumulación, podrá caer un alud de tamaño medio (que podría enterrar a un montañero), sobre todo en terreno trampa. Vilgile con los resbalones por la presencia de costras vidriosas. Lleve el material de seguridad habitual (pala, DVA y sonda), además del casco, crampones y el piolet.

Distribución del manto nivoso

Hay nieve desde 1.300 m. en Norte y desde 1.400 a 1500 m. en Sur, esquiable por encima de unos 1.500 m. Los grosores están alrededor de 150-170 cm a 2.200 m. Estos valores son muy excedentarios para la época del año.

Tendencia para las próximas 48-72h

Nuevos chubascos y viento fuerte mantendrán el problema por placa de viento durante todo el fin de semana. Peligro EN LEVE ASCENSO.

El próximo boletín será emitido el día 2026-02-13

5 MUY FUERTE	4 FUERTE	3 NOTABLE	2 LIMITADO	1 DÉBIL

EAWS EUROPEAN AVALANCHE WARNING SERVICES

ICGC Institut Cartogràfic i Geològic de Catalunya

meteo.cat Servei Meteorològic de Catalunya

Boletín de peligro de aludes Prepirineu
Del 12/02/2026 al 13/02/2026

(Válido fuera pistas de esquí y zonas no controladas)

LIMITADO (2).

Situación primaria

Nieve venteada

Distribución

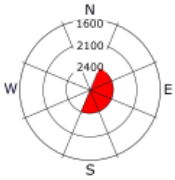

Tamaño

Origen

Tendencia

Estado del manto nivoso

El viento del noroeste ha hecho aflorar las costras de lluvia, vidriosas y muy duras. El manto, por tanto, superficialmente, se muestra bastante endurecido, aunque en solanas, en cotas medias, se transforma con la radiación solar. Aparecen surcos por la lluvia caída el pasado martes. En altura se ha observado transporte de la nieve más seca, con la probable formación de nuevas placas. Además, el viento fuerte previsto, el viernes, encontraremos nuevas placas de viento, en general, pequeñas y restringidas bajo collados y cordales. Estas placas, al romperse al paso de un montañero, podrán generar aludes, de pequeño tamaño, sin capacidad para enterrar a una persona. Localmente, los aludes podrán llegar hasta tamaño medio (con capacidad de enterrar a una persona). Las placas se formarán, en especial en vertiente E y SE. Vigile con los resbalones por la presencia de costras vidriosas. Lleve el material de seguridad habitual (pala, DVA y sonda), además del casco, crampones y el piolet.

Distribución del manto nivoso

Hay nieve desde 1400-1500 m. El manto es esquiable a partir de 1600 m. Los grosores están alrededor de 110-130 cm a unos 2.200 m y son superiores a los habituales.

Tendencia para las próximas 48-72h

Con el fuerte viento del NW y los nuevos chubascos previstos seguirá el problema por placa de viento. Peligro EN LEVE ASCENSO.

El próximo boletín será emitido el día 2026-02-13

5 MUY FUERTE	4 FUERTE	3 NOTABLE	2 LIMITADO	1 DÉBIL

EAWS EUROPEAN AVALANCHE WARNING SERVICES

ICGC Institut Cartogràfic i Geològic de Catalunya

Servei Meteorològic de Catalunya

Boletín de peligro de aludes Ter-Freser
Del 12/02/2026 al 13/02/2026

(Válido fuera pistas de esquí y zonas no controladas)

LIMITADO (2), debajo de los 2.300 m.
NOTABLE (3), por encima, a partir de la tarde.

Situación primaria

Nieve venteada

Distribución

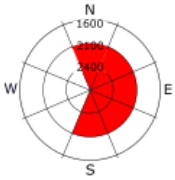

Tamaño

Origen

Tendencia

Estado del manto nivoso

El fuerte viento del noroeste ha hecho aflorar las costras de lluvia, vidriosas en algunos casos. El manto, por tanto, superficialmente, se muestra bastante endurecido. Por debajo seguimos encontrando costras que se alternan con grano fino y formas mixtas. En altura se ha observado transporte de la nieve más seca, con la formación de nuevas placas. Además, con la leve nevada y el viento fuerte previstos, el viernes encontraremos nuevas placas de viento. Estas placas se habrán formado por encima de los 2.300 m y, al romperse al paso de un montañero, podrán generar aludes, de hasta tamaño medio (con capacidad de enterrar a una persona). Las placas se formarán, en especial en vertiente E y SE, bajo collados y cordales. Hay que vigilar con los resbalones por la presencia de costras vidriosas en la superficie del manto. Lleve el material de seguridad habitual (pala, DVA y sonda), además del casco, crampones y el piolet.

Distribución del manto nivoso

El manto nivoso presenta grosores muy excedentarios para la época del año. En lugares no afectados por el viento, los espesores oscilan entre 100-140 cm a unos 2.000 m, siendo esquiable a partir de unos 1.500 m.

Tendencia para las próximas 48-72h

Con el fuerte viento del NW y las nuevas nevadas previstas seguirá el problema por placa de viento. Peligro EN ASCENSO.

El próximo boletín será emitido el día 2026-02-13

5 MUY FUERTE	4 FUERTE	3 NOTABLE	2 LIMITADO	1 DÉBIL

EAWS EUROPEAN AVALANCHE WARNING SERVICES