BUTLLETÍ DEL PERILL D'ALLAUS DEL PRINCIPAT D'ANDORRA

Elaborado el 12/02/2026 16:00
Proxima actualización 13/02/2026 a las 16h

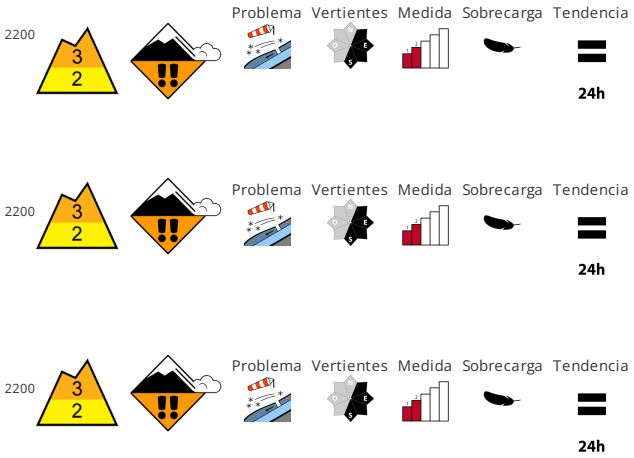

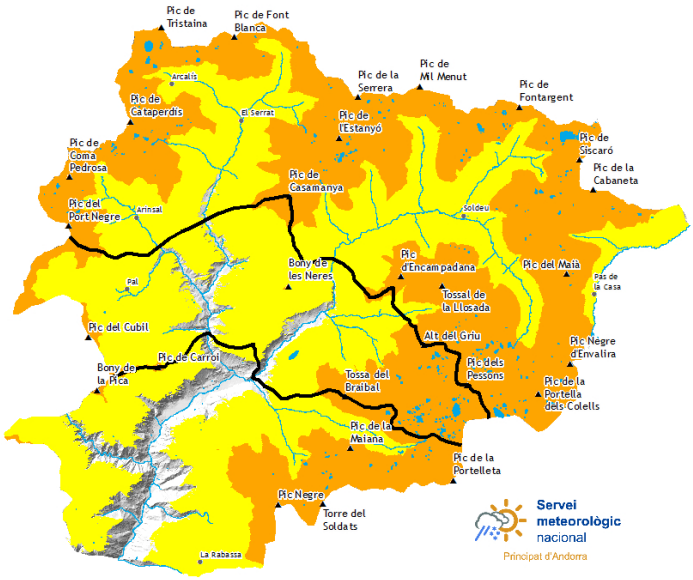

CALIDAD DE LA NIEVE

El viento con rachas fuertes transportará intensamente la nieve reciente. Especialmente cerca de las cumbres las placas de viento, hasta ahora pequeñas, aumentarán de tamaño. En las laderas cerca de los cordales orientadas a nordeste, este y sudeste son son posibles aludes naturales de tamaño pequeño a mediano. En cotas bajas y medias :. Debido a la superficie dura del manto de nieve hay el peligro de resbalar y caer incluso en laderas moderadamente inclinadas. Las excursiones de montaña y las actividades fuera pista requieren experiencia en la evaluación del peligro de aludes y una cuidadosa elección del itinerario. Se recomienda mantener la distancia de seguridad entre los miembros del grupo. Los lugares peligrosos son resultan difíciles de reconocer con poca visibilidad.

ESTABILIDAD DEL MANTO NIVOSO

El jueves el viento ha soplado en muchos sectores de fuerte a muy fuerte. Durante la noche caerá nieve por encima de los 1300 m aproximadamente. En cotas altas y en las laderas orientadas a nordeste, este y sudeste :. Con la nieve reciente y el viento las placas de viento aumentarán de tamaño. En cotas bajas :. La superficie del manto de nieve se volverá a helar para formar una costra portante.

ESPESORES DEL MANTO NIVOSO FUERA DE PISTA

Zona norte		Espesor nieve		
Manto Nival		1500m	2000m	2500m
N	1300 m	50 cm	150 cm	200 cm
S	1400 m	30 cm	100 cm	150 cm

zona centro		Espesor nieve		
Manto Nival		1500m	2000m	2500m
N	1300 m	30 cm	150 cm	200 cm
S	1400 m	10 cm	100 cm	150 cm

Zona sur		Espesor nieve		
Manto Nival		1500m	2000m	2500m
N	1300 m	30 cm	120 cm	150 cm
S	1400 m	10 cm	60 cm	100 cm

Govern d'Andorra

EAWS EUROPEAN AVALANCHE WARNING SERVICES

Aquest butlletí ha estat elaborat seguint les normes i recomanacions de l'**European Avalanche Warning Services**, del qual el **Servei meteorològic Nacional** n'és membre

Información detallada por espacios naturales protegidos

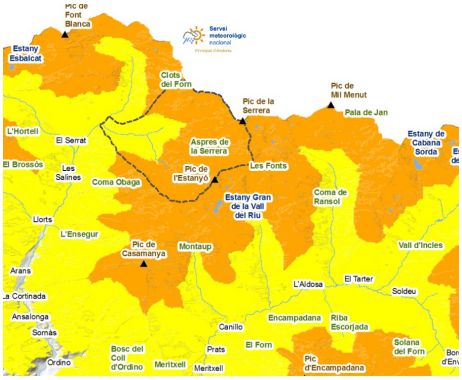

SORTENY

Con la nieve cayendo y el viento aún moderado las placas de viento aumentarán de tamaño. Habrá que tener cuidado con lugares de componente este, ya que pueden esconder placas de viento. Debido a este viento, la superficie de la nieve tiene texturas muy diferentes. , , , , ,

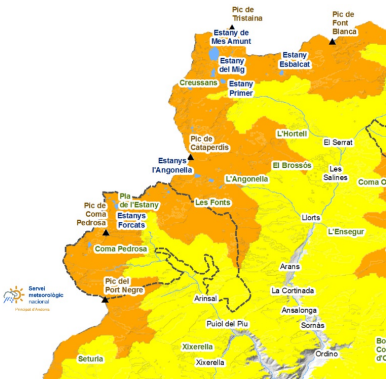

COMAPEDROSA

Sobre la nieve dura se han formado placas de viento que pueden ser sensibles a las sobrecargas en las laderas orientales. En cotas más bajas, cerca de Arinsal, la nieve está más helada. , , ,

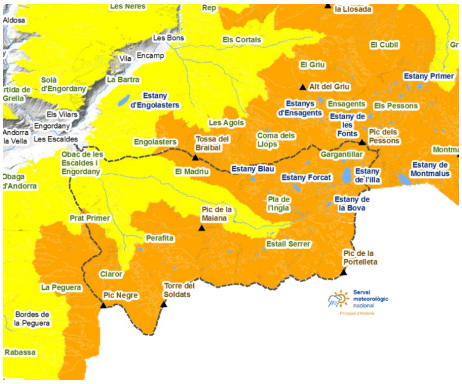

MADRIU-PERAFITA-CLAROR

La nieve húmeda del fondo del valle se regelará y acentuará el peligro de resbalón, incluso en terreno moderadamente inclinado. Como en todo el país, cerca de las cimas el viento creará nuevas acumulaciones en las vertientes con orientación a este.

BUTLLETÍ DEL PERILL D'ALLAUS DEL PRINCIPAT D'ANDORRA

Servei meteorològic nacional
Principat d'Andorra

Espesores de nieve nueva de los últimos días (de las ultimas 24h mesurado a las 06:00h UTC)

	08/02/2026	09/02/2026	10/02/2026	11/02/2026
FEDA (Central)	0 cm	0 cm	0 cm	0 cm
Engolasters - FEDA	0 cm	0 cm	0 cm	0 cm
Bony de les Neres	0 cm	11 cm	0 cm	0 cm
Sorteny	2 cm	22 cm	0 cm	17 cm
Les Fonts d'Arinsal	10 cm	15 cm	12 cm	9 cm
Perafita	0 cm	8 cm	0 cm	0 cm
Tossa Espiolets	4 cm	5 cm	0 cm	0 cm
Grau Roig - FEDA	0 cm	13 cm	0 cm	9 cm
Fontverd	0 cm	7 cm	0 cm	0 cm
Ransol - FEDA	0 cm	4 cm	0 cm	0 cm
Setúria	6 cm	12 cm	0 cm	0 cm
Caborreu	0 cm	6 cm	0 cm	9 cm
Envalira Antenes	4 cm	18 cm	0 cm	0 cm
Vall del Riu FEDA	0 cm	7 cm	7 cm	0 cm