MINISTERO DELLA DIFESA

meteomont
Servizio Nazionale di previsione neve e valanghe

EAWS EUROPEAN AVALANCHE WARNING SERVICES

CARABINIERI

AERONAUTICA MILITARE SERVIZIO METEOROLOGICO

ALPI GIULIE

Bollettino Valanghe N. 344/2026 del 12/02/2026 ore 14.00
Validità 48 ore prossima emissione 13/02/2026

A cura del Servizio METEOMONT dell'ARMA dei CARABINIERI
In collaborazione con Servizio Meteorologico dell'Aeronautica militare

SITUAZIONE alle 14:00 del 12/02/2026

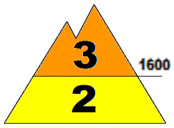

SITUAZIONE TIPO: neve a debole coesione e vento.

SITUAZIONE TIPO: pioggia su neve.

Quota neve (mslm)	Nord	Sud
	800 - 1000	900 - 1400

Altezza Neve (cm)	Neve al suolo	Neve Fresca	Quota (mslm)
	115	00	1750
	50	00	875

VALANGHE OSSERVATE: Nessuna valanga.

PREVISIONI 13/02/2026

GRADO DI PERICOLO: MARCATO 3

SITUAZIONE TIPO: neve a debole coesione e vento.

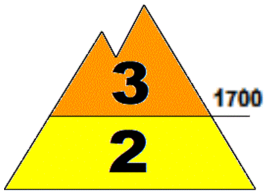

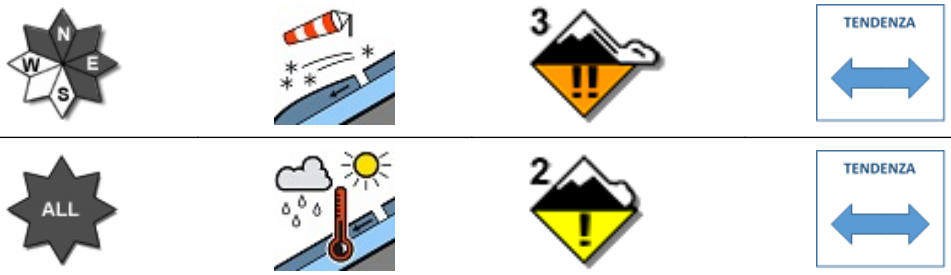

SITUAZIONE TIPO: situazione primaverile.

MANTO NEVOSO: La stabilità del manto nevoso è scarsa su molti punti (aree) per versanti da nord ovest a sud est compresi al di sopra di 1700 mslm, possibili valanghe di dimensioni medie.
La stabilità del manto nevoso è scarsa su alcuni punti (aree) per tutte le esposizioni al di sotto di 1700 mslm, possibili valanghe di dimensioni medie.

AVVERTENZE

A seguito dell'attività eolica registrata sono da evitare le zone di accumulo, conche, canaloni, cambi di pendenza e pendii sotto vento in genere.

SCALA EUROPEA DEL GRADO DI PERICOLO VALANGHE

LEGENDA PROBLEMA

Bollettino realizzato su scala sinottica-regionale (standard EAWS). La sua valutazione non può escludere in alcun modo la necessità di una seria e capace valutazione locale del pericolo (singolo pendio) che può essere anche sensibilmente diverso. Le previsioni meteorologiche sono relative all'orario UTC (per l'Italia +1 in inverno e +2 in estate).

MINISTERO DELLA DIFESA

meteomont
Servizio Nazionale di previsione neve e valanghe

EAWS EUROPEAN AVALANCHE WARNING SERVICES

CARABINIERI

ALPI GIULIE

PREVISIONE METEO

Quota		13/02/2026 h6:00	13/02/2026 h12:00	13/02/2026 h18:00
1000	Venti	01 Nodi da Ovest	01 Nodi da S-Ovest	02 Nodi da Sud
	Temperature	+03 °C	+02 °C	+00 °C
	Temp.percepita	3 °C	2 °C	0 °C
2000	Venti	03 nodi da Ovest	03 Nodi da Ovest	03 Nodi da Sud
	Temperature	-02 °C	-02 °C	-01 °C
	Temp.percepita	-4 °C	-4 °C	-3 °C
3000	Venti	06 nodi da N-Ovest	07 Nodi da Ovest	10 Nodi da Ovest
	Temperature	-10 °C	-10 °C	-08 °C
	Temp.percepita	-16 °C	-16 °C	-15 °C
Zero termico		0800-1000 m.	1400-1600 m.	1200-1400 m.
Fenomeno		—	—	—
Stato del cielo				

LEGENDA FENOMENI

— Assenza Fenomeni · Nebbia · Foschia · Pioggia debole · Pioggia moderata · Pioggia forte · Temporali

Nevicata debole · Nevicata moderata · Nevicata forte

STATO DEL CIELO

Sereno · Poco nuvoloso · Nuvoloso · Molto nuvoloso · Coperto

Parametri meteonivometrici registrati presso i campi di rilevamento il 12/02/2026.

Località	Comune	Quota (m.s.l.m.)	Altezza neve (cm)	Neve caduta nelle 24 ore (cm)	Temp. Min (°C)	Temp. Max (°C)	Condizioni del tempo
MALBORGHETTO - VAL SAISERA	Tarvisio (UD)	875	50	0	N.P.	+8	Assenza di precipitazioni
PASSO PRAMOLLO	Pontebba (UD)	1530	123	1	0	+1	Nevicata debole intermittente
MONTE LUSSARI	Tarvisio (UD)	1750	115	0	-2	+6	Assenza di precipitazioni
PASSO PREDIL	Tarvisio (UD)	1130	78	0	0	+2	Assenza di precipitazioni

(*) Rilievi fuori campo

L'INFORMAZIONE E' PREVENZIONE - LEGGI L'ATTUALE GRADO DI PERICOLO VALANGHE!

IL CAPO DEL CENTRO NAZIONALE METEOMONT
(Ten. Col. RFI Emanuela Gini)
FIRMA AUTOGRAFA OMESSA AI SENSI
DELL'ART.3 DEL D.LGS N.39/1993

Bollettino realizzato su scala sinottica-regionale (standard EAWS). La sua valutazione non può escludere in alcun modo la necessità di una seria e capace valutazione locale del pericolo (singolo pendio) che può essere anche sensibilmente diverso. Le previsioni meteorologiche sono relative all'orario UTC (per l'Italia +1 in inverno e +2 in estate).