MINISTERO DELLA DIFESA

meteomont
Servizio Nazionale di previsione neve e valanghe

EAWS EUROPEAN AVALANCHE WARNING SERVICES

CARABINIERI

ALPI RETICHE

Bollettino Valanghe N. 344/2026 del 11/02/2026 ore 14.00
Validità 48 ore prossima emissione 12/02/2026

A cura del Servizio METEOMONT dell'ARMA dei CARABINIERI
In collaborazione con Servizio Meteorologico dell'Aeronautica militare

SITUAZIONE alle 14:00 del 11/02/2026

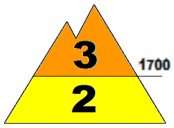

SITUAZIONE TIPO: strato debole persistente basale.

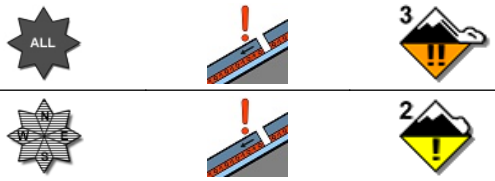

SITUAZIONE TIPO: passaggio da poca a molta neve.

Quota neve (mslm)	Nord	Sud
	1100 - 1200	1200 - 1300

Altezza Neve (cm)	Neve al suolo	Neve Fresca	Quota (mslm)
	59	001	2582
	39	003	1580

VALANGHE OSSERVATE: Nessuna valanga.

PREVISIONI 12/02/2026

GRADO DI PERICOLO: MARCATO 3

SITUAZIONE TIPO: strato debole persistente basale.

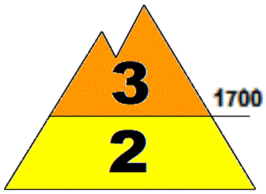



SITUAZIONE TIPO: pioggia su neve.

MANTO NEVOSO: La stabilità del manto nevoso è scarsa su molti punti (aree) per tutte le esposizioni al di sopra di 1700 mslm, possibili valanghe di dimensioni medie.
La stabilità del manto nevoso è discreta su alcuni punti (aree) per isolati pendii al di sotto di 1700 mslm, possibili valanghe di dimensioni medie.

AVVERTENZE

In considerazione delle avverse condizioni meteorologiche previste, e della scarsa visibilità, risulterà difficoltosa l'individuazione dell'itinerario e della valutazione del singolo pendio.

SCALA EUROPEA DEL GRADO DI PERICOLO VALANGHE

LEGENDA PROBLEMA

Bollettino realizzato su scala sinottica-regionale (standard EAWS). La sua valutazione non può escludere in alcun modo la necessità di una seria e capace valutazione locale del pericolo (singolo pendio) che può essere anche sensibilmente diverso. Le previsioni meteorologiche sono relative all'orario UTC (per l'Italia +1 in inverno e +2 in estate).

MINISTERO DELLA DIFESA

meteomont
Servizio Nazionale di previsione neve e valanghe

EAWS EUROPEAN AVALANCHE WARNING SERVICES

CARABINIERI

ALPI RETICHE

PREVISIONE METEO

Quota		12/02/2026 h6:00	12/02/2026 h12:00	12/02/2026 h18:00
1000	Venti	01 Nodi da N-Est	00 Calma	03 nodi da N-Ovest
	Temperature	-04 °C	-03 °C	-02 °C
	Temp.percepita	-4 °C	-3 °C	-4 °C
2000	Venti	01 Nodi da N-Est	00 Calma	03 nodi da N-Ovest
	Temperature	-04 °C	-03 °C	-02 °C
	Temp.percepita	-4 °C	-3 °C	-4 °C
3000	Venti	03 nodi da N-Ovest	09 nodi da N-Ovest	23 nodi da N-Ovest
	Temperature	-09 °C	-09 °C	-09 °C
	Temp.percepita	-12 °C	-16 °C	-20 °C
Zero termico		1300-1500 m.	1400-1600 m.	1600-1800 m.
Fenomeno				—
Stato del cielo				

LEGENDA FENOMENI

— Assenza Fenomeni · Nebbia · Foschia · Pioggia debole · Pioggia moderata · Pioggia forte · Temporali

Nevicata debole · Nevicata moderata · Nevicata forte

STATO DEL CIELO

Sereno · Poco nuvoloso · Nuvoloso · Molto nuvoloso · Coperto

Parametri meteonivometrici registrati presso i campi di rilevamento il 11/02/2026.

Località	Comune	Quota (m.s.l.m.)	Altezza neve (cm)	Neve caduta nelle 24 ore (cm)	Temp. Min (°C)	Temp. Max (°C)	Condizioni del tempo
SPONDA	Livigno (SO)	2150	52	2	-6	-1	Assenza di precipitazioni
BORMIO2000-LECCIONA	Valdisotto (SO)	2050	57	2	-3	-1	Assenza di precipitazioni
DOSSO DEL VALLONE	Valfurva (SO)	2582	59	1	-6	-2	Assenza di precipitazioni
SANTA APOLLONIA	Vezza d'Oglio (BS)	1599	27	2	N.P.	N.P.	Assenza di precipitazioni
ALPE PALU'	Chiesa in Valmalenco (SO)	2010	78	7	-4	-1	Assenza di precipitazioni
PREDA	Edolo (BS)	1580	39	3	-5	+4	Assenza di precipitazioni
COLONIA VIGILI	Ponte di Legno (BS)	1640	60	2	-2	+3	Assenza di precipitazioni
PISTA STELVIO *	Valdisotto (SO)	2181	59	2	N.P.	N.P.	Assenza di precipitazioni
MONTE PAGANO *	Monno (BS)	2300	79	2	N.P.	N.P.	Assenza di precipitazioni

(*) Rilievi fuori campo

L'INFORMAZIONE E' PREVENZIONE - LEGGI L'ATTUALE GRADO DI PERICOLO VALANGHE!

IL CAPO DEL CENTRO NAZIONALE METEOMONT
(Ten. Col. RFI Emanuela Gini)
FIRMA AUTOGRAFA OMESSA AI SENSI
DELL'ART.3 DEL D.LGS N.39/1993

Bollettino realizzato su scala sinottica-regionale (standard EAWS). La sua valutazione non può escludere in alcun modo la necessità di una seria e capace valutazione locale del pericolo (singolo pendio) che può essere anche sensibilmente diverso. Le previsioni meteorologiche sono relative all'orario UTC (per l'Italia +1 in inverno e +2 in estate).