MINISTERO DELLA DIFESA

meteomont
Servizio Nazionale di previsione neve e valanghe

EAWS EUROPEAN AVALANCHE WARNING SERVICES

CARABINIERI

AERONAUTICA MILITARE SERVIZIO METEOROLOGICO

ALPI RETICHE

Bollettino Valanghe N. 345/2026 del 12/02/2026 ore 14.00
Validità 48 ore prossima emissione 13/02/2026

A cura del Servizio METEOMONT dell'ARMA dei CARABINIERI
In collaborazione con Servizio Meteorologico dell'Aeronautica militare

SITUAZIONE alle 14:00 del 12/02/2026

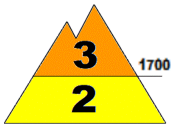

SITUAZIONE TIPO: strato debole persistente basale.



SITUAZIONE TIPO: situazione primaverile.

Quota neve (mslm)	Nord	Sud
	1100 - 1300	1200 - 1600

Altezza Neve (cm)	Neve al suolo	Neve Fresca	Quota (mslm)
	59	0	2400
	39	0	1580

VALANGHE OSSERVATE: Alcune valanghe di medie dimensioni, Valanghe di neve a debole coesione di superficie.

PREVISIONI 13/02/2026

GRADO DI PERICOLO: MARCATO 3

SITUAZIONE TIPO: strato debole persistente basale.

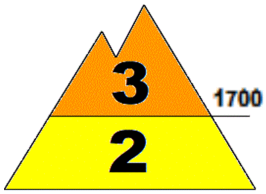

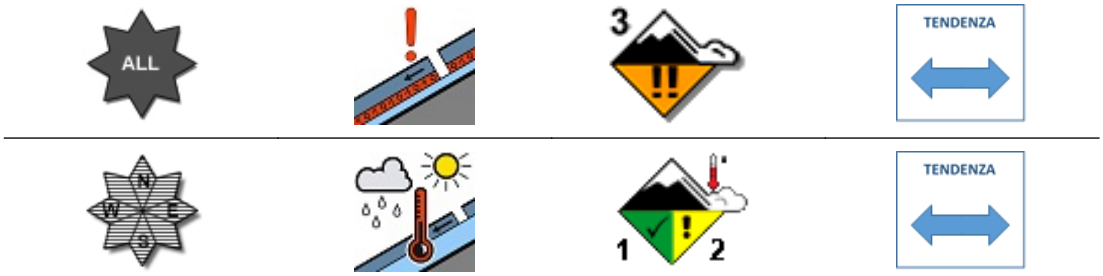

SITUAZIONE TIPO: situazione primaverile.

MANTO NEVOSO: La stabilità del manto nevoso è scarsa su molti punti (aree) per tutte le esposizioni al di sopra di 1700 mslm, possibili valanghe di dimensioni medie.
La stabilità del manto nevoso è molto scarsa su pochi punti (aree) per isolati pendii al di sotto di 1700 mslm, possibili valanghe di dimensioni medie.

AVVERTENZE

A seguito dell'attività eolica prevista sono da evitare le zone di accumulo, conche, canaloni, cambi di pendenza e pendii sotto vento in genere.

SCALA EUROPEA DEL GRADO DI PERICOLO VALANGHE

5 - MOLTO FORTE | 4 - FORTE | 3 - MARCATO | 2 - MODERATO | 1 - DEBOLE | NO NEVE | NO INFO

LEGENDA PROBLEMA

NEVE FRESCA | LASTRONI DA VENTO | STRATI DEBOLI PERSISTENTI | NEVE BAGNATA | SLITTAMENTO | CORNICI | NESSUN PROBLEMA VALANGHIVO EVIDENTE | NO_INFO

Bollettino realizzato su scala sinottica-regionale (standard EAWS). La sua valutazione non può escludere in alcun modo la necessità di una seria e capace valutazione locale del pericolo (singolo pendio) che può essere anche sensibilmente diverso. Le previsioni meteorologiche sono relative all'orario UTC (per l'Italia +1 in inverno e +2 in estate).

ALPI RETICHE

PREVISIONE METEO

Quota		13/02/2026 h6:00	13/02/2026 h12:00	13/02/2026 h18:00
1000	Venti	02 nodi da N-Ovest	01 Nodi da N-Est	01 Nodi da N-Est
	Temperature	-04 °C	-02 °C	-03 °C
	Temp.percepita	-4 °C	-2 °C	-3 °C
2000	Venti	02 nodi da N-Ovest	01 Nodi da N-Est	01 Nodi da N-Est
	Temperature	-04 °C	-02 °C	-03 °C
	Temp.percepita	-4 °C	-2 °C	-3 °C
3000	Venti	12 nodi da N-Ovest	03 Nodi da S-Ovest	07 Nodi da S-Ovest
	Temperature	-11 °C	-09 °C	-08 °C
	Temp.percepita	-20 °C	-12 °C	-14 °C
Zero termico		1200-1400 m.	1400-1600 m.	1400-1600 m.
Fenomeno		—	—	—
Stato del cielo				

LEGENDA FENOMENI

— Assenza Fenomeni · Nebbia · Foschia · Pioggia debole · Pioggia moderata · Pioggia forte · Temporali

Nevicata debole · Nevicata moderata · Nevicata forte

STATO DEL CIELO

Sereno · Poco nuvoloso · Nuvoloso · Molto nuvoloso · Coperto

Parametri meteonivometrici registrati presso i campi di rilevamento il 12/02/2026.

Località	Comune	Quota (m.s.l.m.)	Altezza neve (cm)	Neve caduta nelle 24 ore (cm)	Temp. Min (°C)	Temp. Max (°C)	Condizioni del tempo
SPONDA	Livigno (SO)	2150	50	0	-6	+7	Assenza di precipitazioni
BORMIO2000-LECCIONA	Valdisotto (SO)	2050	54	0	-4	+3	Assenza di precipitazioni
DOSSO DEL VALLONE	Valfurva (SO)	2582	59	0	-9	-3	Assenza di precipitazioni
ALPE PALU'	Chiesa in Valmalenco (SO)	2010	73	0	-4	+3	Assenza di precipitazioni
PREDA	Edolo (BS)	1580	39	0	-1	+4	Assenza di precipitazioni
PISTA STELVIO *	Valdisotto (SO)	2280	66	Tracce di neve	N.P.	N.P.	Assenza di precipitazioni
VALLONE *	Valdisotto (SO)	2407	59	0	N.P.	N.P.	Assenza di precipitazioni

(*) Rilievi fuori campo

L'INFORMAZIONE E' PREVENZIONE - LEGGI L'ATTUALE GRADO DI PERICOLO VALANGHE!

IL CAPO DEL CENTRO NAZIONALE METEOMONT
(Ten. Col. RFI Emanuela Gini)
FIRMA AUTOGRAFA OMESSA AI SENSI
DELL'ART.3 DEL D.LGS N.39/1993

Bollettino realizzato su scala sinottica-regionale (standard EAWS). La sua valutazione non può escludere in alcun modo la necessità di una seria e capace valutazione locale del pericolo (singolo pendio) che può essere anche sensibilmente diverso. Le previsioni meteorologiche sono relative all'orario UTC (per l'Italia +1 in inverno e +2 in estate).