MINISTERO DELLA DIFESA

meteomont
Servizio Nazionale di previsione neve e valanghe

EAWS EUROPEAN AVALANCHE WARNING SERVICES

CARABINIERI

AERONAUTICA MILITARE SERVIZIO METEOROLOGICO

ALPI OROBICHE

Bollettino Valanghe N. 343/2026 del 12/02/2026 ore 14.00
Validità 48 ore prossima emissione 13/02/2026

A cura del Servizio METEOMONT dell'ARMA dei CARABINIERI
In collaborazione con Servizio Meteorologico dell'Aeronautica militare

SITUAZIONE alle 14:00 del 12/02/2026

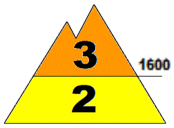

SITUAZIONE TIPO: strato debole persistente basale.



SITUAZIONE TIPO: situazione primaverile.

Quota neve (mslm)	Nord	Sud
	1300 - 1400	1300 - 1500

Altezza Neve (cm)	Neve al suolo	Neve Fresca	Quota (mslm)
	065	0	1750
	015	0	1300

VALANGHE OSSERVATE: Nessuna valanga.

PREVISIONI 13/02/2026

GRADO DI PERICOLO: MARCATO 3

SITUAZIONE TIPO: strato debole persistente basale.

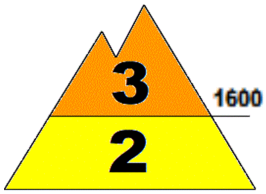

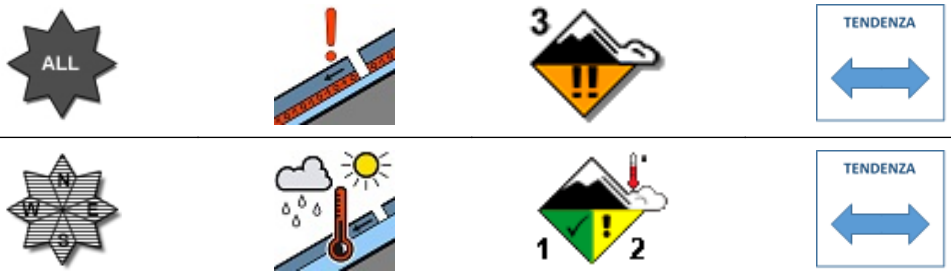

SITUAZIONE TIPO: situazione primaverile.

MANTO NEVOSO: La stabilità del manto nevoso è scarsa su molti punti (aree) per tutte le esposizioni al di sopra di 1600 mslm, possibili valanghe di dimensioni medie.
La stabilità del manto nevoso è molto scarsa su pochi punti (aree) per isolati pendii al di sotto di 1600 mslm, possibili valanghe di dimensioni medie.

AVVERTENZE

A seguito dell'attività eolica prevista sono da evitare le zone di accumulo, conche, canaloni, cambi di pendenza e pendii sotto vento in genere.

SCALA EUROPEA DEL GRADO DI PERICOLO VALANGHE

LEGENDA PROBLEMA

Bollettino realizzato su scala sinottica-regionale (standard EAWS). La sua valutazione non può escludere in alcun modo la necessità di una seria e capace valutazione locale del pericolo (singolo pendio) che può essere anche sensibilmente diverso. Le previsioni meteorologiche sono relative all'orario UTC (per l'Italia +1 in inverno e +2 in estate).

MINISTERO DELLA DIFESA

meteomont
Servizio Nazionale di previsione neve e valanghe

EAWS EUROPEAN AVALANCHE WARNING SERVICES

CARABINIERI

ALPI OROBICHE

PREVISIONE METEO

Quota		13/02/2026 h6:00	13/02/2026 h12:00	13/02/2026 h18:00
1000	Venti	03 Nodi da Nord	00 Calma	00 Calma
	Temperature	-04 °C	+00 °C	+00 °C
	Temp.percepita	-6 °C	0 °C	0 °C
2000	Venti	04 Nodi da Nord	02 Nodi da Sud	02 Nodi da Sud
	Temperature	-03 °C	-01 °C	-01 °C
	Temp.percepita	-6 °C	-1 °C	-1 °C
3000	Venti	11 nodi da N-Ovest	06 Nodi da Ovest	09 Nodi da S-Ovest
	Temperature	-10 °C	-08 °C	-08 °C
	Temp.percepita	-18 °C	-13 °C	-15 °C
Zero termico		1100-1300 m.	1500-1700 m.	1200-1400 m.
Fenomeno		—	—	—
Stato del cielo				

LEGENDA FENOMENI

— Assenza Fenomeni · Nebbia · Foschia · Pioggia debole · Pioggia moderata · Pioggia forte · Temporali

Nevicata debole · Nevicata moderata · Nevicata forte

STATO DEL CIELO

Sereno · Poco nuvoloso · Nuvoloso · Molto nuvoloso · Coperto

Parametri meteonivometrici registrati presso i campi di rilevamento il 12/02/2026.

Località	Comune	Quota (m.s.l.m.)	Altezza neve (cm)	Neve caduta nelle 24 ore (cm)	Temp. Min (°C)	Temp. Max (°C)	Condizioni del tempo
VODALA	Gromo (BG)	1635	68	0	-1	+2	Assenza di precipitazioni
QUARTA BAITA	Foppolo (BG)	1760	65	0	0	+5	Assenza di precipitazioni
PASSO DELLA PRESOLANA *	Castione della Presolana (BG)	1290	15	0	N.P.	N.P.	Pioggia debole intermittente
P.SSO VAL CERVIA *	Foppolo (BG)	2426	80	1	N.P.	N.P.	Assenza di precipitazioni
PUNTO PESCIOLA *	Ponte in Valtellina (SO)	2340	107	0	N.P.	N.P.	Assenza di precipitazioni

(*) Rilievi fuori campo

L'INFORMAZIONE E' PREVENZIONE - LEGGI L'ATTUALE GRADO DI PERICOLO VALANGHE!

IL CAPO DEL CENTRO NAZIONALE METEOMONT
(Ten. Col. RFI Emanuela Gini)
FIRMA AUTOGRAFA OMESSA AI SENSI
DELL'ART.3 DEL D.LGS N.39/1993

Bollettino realizzato su scala sinottica-regionale (standard EAWS). La sua valutazione non può escludere in alcun modo la necessità di una seria e capace valutazione locale del pericolo (singolo pendio) che può essere anche sensibilmente diverso. Le previsioni meteorologiche sono relative all'orario UTC (per l'Italia +1 in inverno e +2 in estate).