MAJELLA

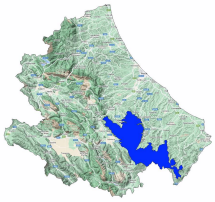

Bollettino Valanghe N. 331/2026 del 12/02/2026 ore 14.00
Validità 48 ore prossima emissione 13/02/2026
A cura del Servizio METEOMONT dell'ARMA dei CARABINIERI
In collaborazione con Servizio Meteorologico dell'Aeronautica militare

SITUAZIONE alle 14:00 del 12/02/2026

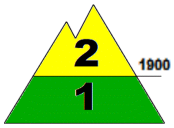

SITUAZIONE TIPO: neve a debole coesione e vento.



SITUAZIONE TIPO: pioggia su neve.

Quota neve (mslm)	Nord	Sud
	1500 - 1600	1800 - 1900

Altezza Neve (cm)	Neve al suolo	Neve Fresca	Quota (mslm)
	011	000	1650
	000	000	1270

VALANGHE OSSERVATE: Nessuna valanga.

PREVISIONI 13/02/2026

GRADO DI PERICOLO: MODERATO 2

SITUAZIONE TIPO: neve a debole coesione e vento.

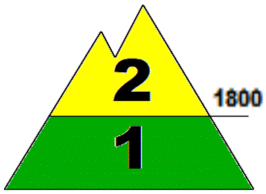

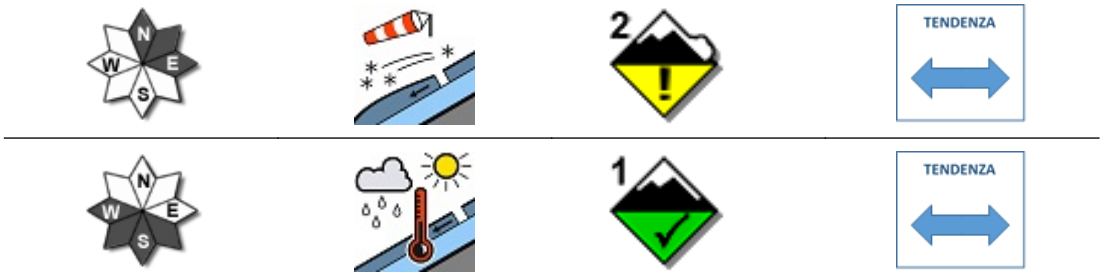

SITUAZIONE TIPO: situazione primaverile.

MANTO NEVOSO: La stabilità del manto nevoso è discreta su alcuni punti (aree) per versanti nord orientali al di sopra di 1800 mslm, possibili valanghe di dimensioni medie.
La stabilità del manto nevoso è discreta su molti punti (aree) per versanti al sole al di sotto di 1800 mslm, possibili valanghe di dimensioni piccole.

AVVERTENZE

In considerazione delle avverse condizioni meteorologiche in atto, le attività al di fuori delle piste battute e segnalate sono sconsigliate.

SCALA EUROPEA DEL GRADO DI PERICOLO VALANGHE

5 - MOLTO FORTE | 4 - FORTE | 3 - MARCATO | 2 - MODERATO | 1 - DEBOLE | NO NEVE | NO INFO

LEGENDA PROBLEMA

NEVE FRESCA | LASTRONI DA VENTO | STRATI DEBOLI PERSISTENTI | NEVE BAGNATA | SLITTAMENTO | CORNICI | NESSUN PROBLEMA VALANGHIVO EVIDENTE | NO_INFO

Bollettino realizzato su scala sinottica-regionale (standard EAWS). La sua valutazione non può escludere in alcun modo la necessità di una seria e capace valutazione locale del pericolo (singolo pendio) che può essere anche sensibilmente diverso. Le previsioni meteorologiche sono relative all'orario UTC (per l'Italia +1 in inverno e +2 in estate).

MINISTERO DELLA DIFESA

meteomont
Servizio Nazionale di previsione neve e valanghe

EAWS EUROPEAN AVALANCHE WARNING SERVICES

CARABINIERI

MAJELLA

PREVISIONE METEO

Quota		13/02/2026 h6:00	13/02/2026 h12:00	13/02/2026 h18:00
1000	Venti	04 nodi da N-Ovest	02 nodi da Ovest	03 Nodi da S-Ovest
	Temperature	+00 °C	+02 °C	+02 °C
	Temp.percepita	-3 °C	2 °C	0 °C
2000	Venti	11 nodi da N-Ovest	04 Nodi da Ovest	05 Nodi da S-Ovest
	Temperature	-01 °C	+00 °C	+02 °C
	Temp.percepita	-7 °C	-3 °C	-1 °C
3000	Venti	19 nodi da N-Ovest	10 nodi da N-Ovest	06 nodi da Ovest
	Temperature	-08 °C	-07 °C	-04 °C
	Temp.percepita	-18 °C	-14 °C	-8 °C
Zero termico		1700-1900 m.	1900-2100 m.	2200-2400 m.
Fenomeno		—	—	—
Stato del cielo				

LEGENDA FENOMENI

— Assenza Fenomeni · Nebbia · Foschia · Pioggia debole · Pioggia moderata · Pioggia forte · Temporali

Nevicata debole · Nevicata moderata · Nevicata forte

STATO DEL CIELO

Sereno · Poco nuvoloso · Nuvoloso · Molto nuvoloso · Coperto

Parametri meteonivometrici registrati presso i campi di rilevamento il 12/02/2026.

Località	Comune	Quota (m.s.l.m.)	Altezza neve (cm)	Neve caduta nelle 24 ore (cm)	Temp. Min (°C)	Temp. Max (°C)	Condizioni del tempo
QUARTARANA	Campo di Giove (AQ)	1200	0	0	+2	+6	Pioggia moderata
PASSOLANCIANO	Lettomanoppello (PE)	1300	0	0	+2	+6	Pioggia moderata
VALICO DELLA FORCHETTA	Palena (CH)	1270	0	0	0	+6	Pioggia debole continua
VALLE DEL SOLE	Pizzoferrato (CH)	1440	0	0	0	+5	Pioggia debole continua
MAIELETTA MAMMA ROSA	Pretoro (CH)	1650	11	Tracce di neve	-1	+4	Pioggia mista a neve
PASSO SAN LEONARDO	Sant'Eufemia a Maiella (PE)	1145	0	0	+3	+9	Pioggia debole continua

(*) Rilievi fuori campo

L'INFORMAZIONE E' PREVENZIONE - LEGGI L'ATTUALE GRADO DI PERICOLO VALANGHE!

IL CAPO DEL CENTRO NAZIONALE METEOMONT
(Ten. Col. RFI Emanuela Gini)
FIRMA AUTOGRAFA OMESSA AI SENSI
DELL'ART.3 DEL D.LGS N.39/1993

Bollettino realizzato su scala sinottica-regionale (standard EAWS). La sua valutazione non può escludere in alcun modo la necessità di una seria e capace valutazione locale del pericolo (singolo pendio) che può essere anche sensibilmente diverso. Le previsioni meteorologiche sono relative all'orario UTC (per l'Italia +1 in inverno e +2 in estate).