Bulletin d'estimation du risque d'avalanche

(valable en dehors des pistes balisées et ouvertes)

MASSIF : Grandes-Rousses

Rédigé le jeudi 12 février 2026 à 10h

Estimation des risques pour le : JEUDI 12 FÉVRIER

FORTES CHUTES DE NEIGE ATTENDUES EN JOURNEE DE JEUDI... DE NOMBREUSES GRANDES VOIRE TRES GRANDES AVALANCHES, ARRIVANT PARFOIS EN MOYENNE MONTAGNE...

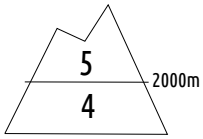

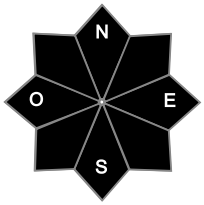

Altitude/ couloirs

Indices de risque : 5 très fort - 4 fort - 3 marqué - 2 limité - 1 faible -- En noir : les pentes les plus dangereuses

Au-dessus de 2000m indice de risque très fort, plus bas indice fort.

Départs spontanés : Vers de nombreuses grandes avalanches/cassures de plaques en altitude, atteignant parfois la moyenne montagne. Très grande avalanche non exclue...

Déclenchements provoqués : Très faciles en altitude, puis sous 2000m en journée de jeudi

Vigilance orange avalanches en cours ou prévue sur le massif

Stabilité du manteau neigeux

Situation avalancheuse typique : neige fraîche couche fragile persistante

Conditions très perturbées, ventées, neigeuses en altitude puis en moyenne montagne... Situation nivologique évoluant défavorablement, particulièrement à haute altitude et dans tous les couloirs. Vers 3000m, on attend jusqu'à 1m/1m30 de neige récente ventée...
Ces derniers jours la neige a été légèrement humidifiée/tassée, seulement sous 2000m. On observe des sous couches sans cohésion (bien enfouies) en versants froids d'altitude...

Départs spontanés :

Ce jeudi en journée, l'épaisseur de neige récente atteindra 40 puis 70 cm vers 2000m (versant Vaujany, Alpe d'Huez) et plus d'1m/1m20 vers 2500m avec du vent d'Ouest puis Nord-Ouest.... De nombreuses grandes avalanches sont attendues, parfois de très grandes.... balayant couloirs et pentes raides. Celles ci peuvent parfois arriver en moyenne montagne en dépôts plus humides (route de Vaujany ou Clavans par exemple ?).
En haute montagne, la présence de sous couche fragile persistante pourrait faciliter quelques avalanches d'ampleur et de trajectoires peu habituelles... Cassures potentielles très larges dépassant 1m50/2m...

Déclenchements provoqués :

Haute montagne infréquentable. Ruptures très faciles au passage du moindre skieur. Sous 2000/2200m, risque accidentel marqué puis fort même loin des crêtes, vu l'intensité de la chute de neige et le vent sensible à fort...
En moyenne montagne, éviter bas de couloirs et clairières raides (risque de grosses coulées humides).

Qualité de la neige

Qualification de l'enneigement : L'enneigement s'améliore encore en haute-montagne, dans les combes, où il devient excellent pour la saison. Il est en revanche médiocre plus bas que 1400m...
Limites skiables : vers 1200/1400 m...
Qualité de la neige jeudi : Plus bas que 1300m, neige dense très humide. Entre 1300 et 1600m neige fraîche collante... Au dessus couche de neige de plus en plus importante au fil des heures, bien ventée en altitude.
Grosses épaisseurs au dessus de 2200/2500m environ avec plus d'1m de neige récente vers 2500m, de très grosses congères/corniches, des secteurs plus dégarnis...

Aperçu météo pour le jeudi 12 février

Redoux temporaire mercredi soir, jeudi plus froid et très neigeux (40/60 cm possibles en 24h). Forts vents d'Ouest à Nord-Ouest...

	nuit	matin	après-midi	soir
Pluie-Neige	1 600 m	1 300 m	1 300 m	1 200 m
Iso 0 °C	2 100 m	1 700 m	1 600 m	1 500 m
Vent 2000 m	↘ 50 km/h	↘ 50 km/h	↘ 55 km/h	↘ 45 km/h
Vent 3000 m	→ 100 km/h	↘ 100 km/h	↘ 90 km/h	↘ 75 km/h

Épaisseur de neige hors-piste

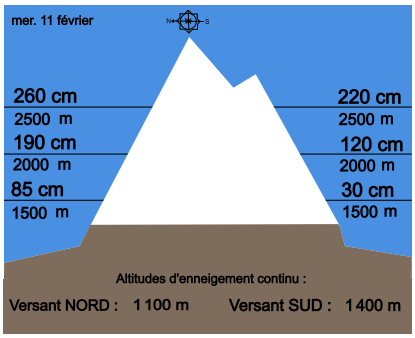

Précipitations à 1800 m

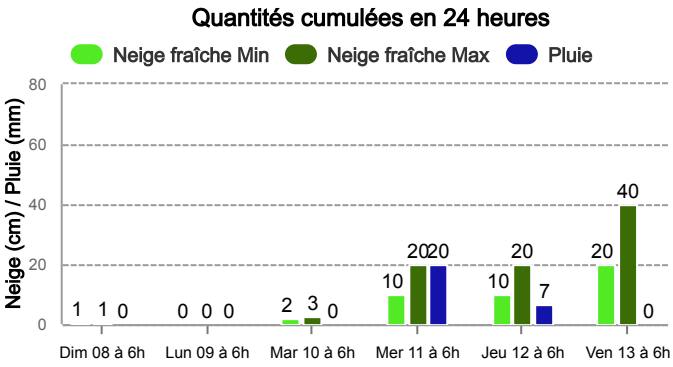

Tendance du vendredi 13 février

Indice de risque fort

Risque d'avalanche stationnaire ou en très légère baisse ? (fin de la "crue" avalancheuse)
Vendredi temporairement plus calme et sec, des éclaircies.
Au soleil/près des rochers des avalanches de neige récente ; en altitude risque accidentel de plaque encore marqué, voire fort ...

Pour consulter la vigilance en cours, veuillez vous rendre sur le site https://vigilance.meteofrance.fr/fr

Météo-France - 73 avenue de Paris, 94165 Saint-Mandé cedex - Contact : contact@meteo.fr

Bulletin neige & avalanches par téléphone au 0 892 68 10 20 Service 0,35 € / min + prix appel

Rédigé par Météo-France avec la contribution des observateurs du réseau nivo-météorologiques. Partenariat : ANMSM (Maires de Stations de Montagne), DSF (Domaines Skiables de France), ADSP (Directeurs de Pistes et de la Sécurité des Stations de Sports d'Hiver) et autres acteurs de la montagne.

RÉPUBLIQUE FRANÇAISE
Liberté Égalité Fraternité

METEO FRANCE
À VOS CÔTÉS, DANS UN CLIMAT QUI CHANGE

Bulletin d'estimation du risque d'avalanche
(valable en dehors des pistes balisées et ouvertes)
MASSIF : Grandes-Rousses

Rédigé le jeudi 12 février 2026 à 10h

Conditions nivo-météo des 7 derniers jours

	jeu. 05/02				ven. 06/02				sam. 07/02				dim. 08/02				lun. 09/02				mar. 10/02				mer. 11/02			
	03h	09h	15h	21h	03h	09h	15h	21h	03h	09h	15h	21h	03h	09h	15h	21h	03h	09h	15h	21h	03h	09h	15h	21h	03h	09h	15h	21h
Météo																												
Vent (km/h)	25	45	45	45	45	30	25	20	20	10	10	10	15	20	25	25	30	15	15	25	35	35	50	60	100	85	85	100
à 3000m																												
Vent (km/h)	15	30	30	30	20	20	20	10	5	10	10	5	10	15	15	20	20	10	15	10	15	20	30	40	80	65	50	50
à 2000m																												

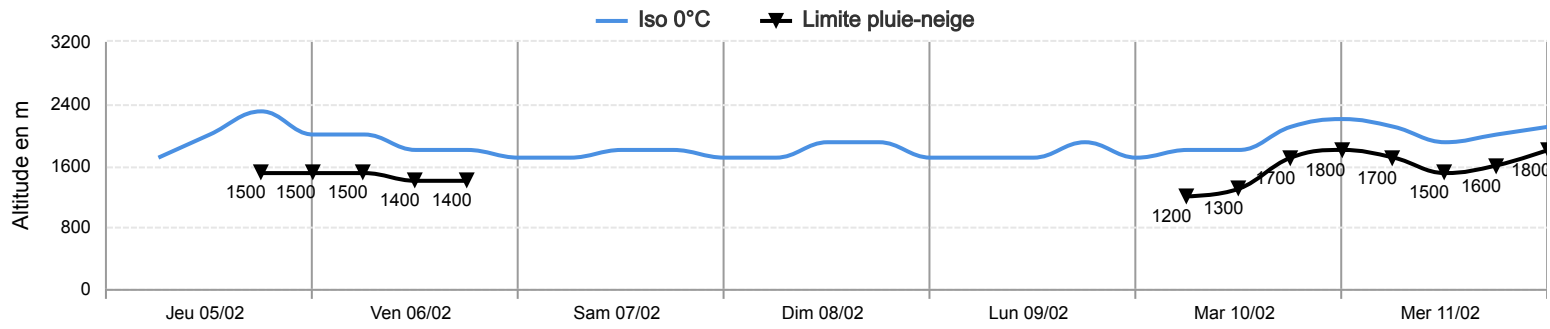

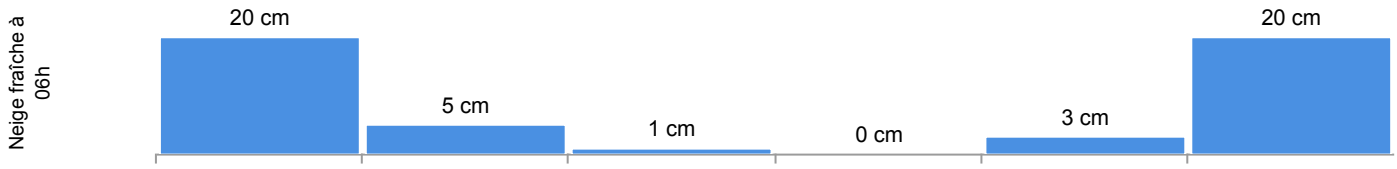

Risque d'avalanche	jeu. 05/02	ven. 06/02	sam. 07/02	dim. 08/02	lun. 09/02	mar. 10/02	mer. 11/02
		3	3	3	3	3	4

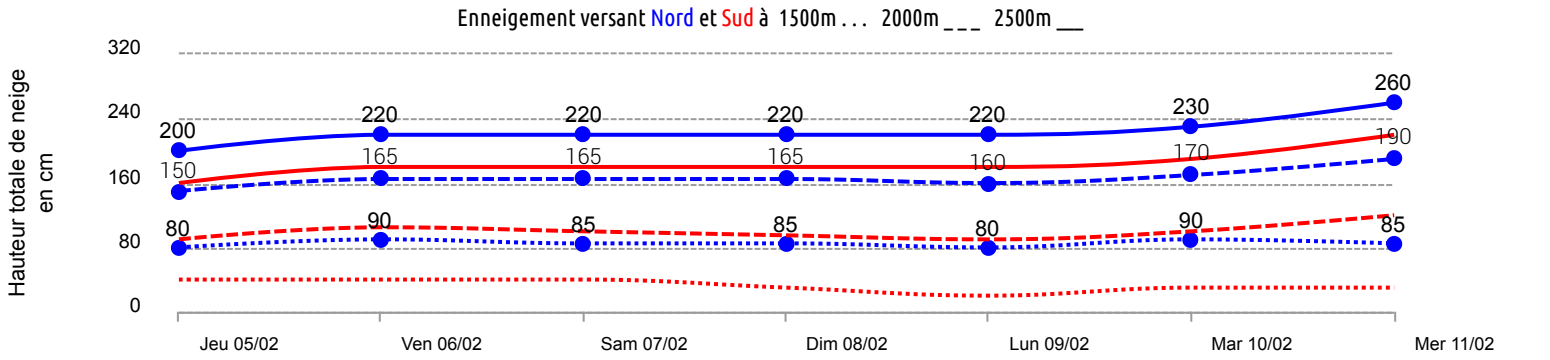

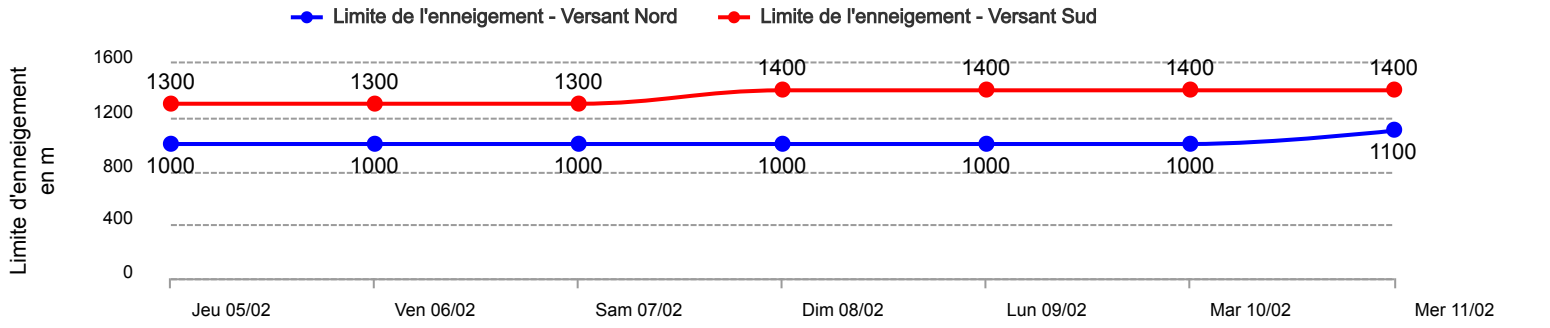

Pour consulter la vigilance en cours, veuillez vous rendre sur le site https://vigilance.meteofrance.fr/fr

Météo-France - 73 avenue de Paris, 94165 Saint-Mandé cedex - Contact : contact@meteo.fr

Rédigé par Météo-France avec la contribution des observateurs du réseau nivo-météorologiques. Partenariat : ANMSM (Maires de Stations de Montagne), DSF (Domaines Skiables de France), ADSP (Directeurs de Pistes et de la Sécurité des Stations de Sports d'Hiver) et autres acteurs de la montagne.

Bulletin neige & avalanches par téléphone au

0 892 68 10 20 Service 0,35 € / min + prix appel