Bulletin d'estimation du risque d'avalanche

(valable en dehors des pistes balisées et ouvertes)

MASSIF : Cinto Rotondo

Rédigé le jeudi 12 février 2026 à 15h

Estimation des risques pour le : VENDREDI 13 FÉVRIER

POURSUITE DES CHUTES DE NEIGE EN COURS DE NUIT, COUCHE RÉCENTE INSTABLE ET FORMATION DE NOUVELLES PLAQUES PAR LE VENT

3

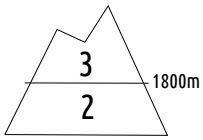

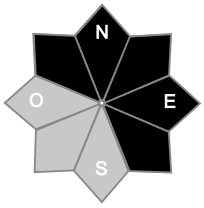

Au-dessus de 1800m indice de risque marqué, plus bas indice limité.

Départs spontanés : Coulées et avalanches de neige fraîche surtout au-dessus de 1800 m

Déclenchements provoqués : Formation de nouvelles plaques par le vent en altitude, facilement déclenchables, s'ajoutant aux anciennes instabilités

Indices de risque : 5 très fort - 4 fort - 3 marqué - 2 limité - 1 faible -- En noir : les pentes les plus dangereuses

Stabilité du manteau neigeux

Situation avalancheuse typique : neige ventée

Déclenchements provoqués : Cette nuit de jeudi à vendredi, les nouvelles chutes de neige transportées par le vent fort génèrent de nombreuses plaques au-dessus de 1800 à 2000 m, souvent loin des crêtes, surtout dans les orientations Est. Elles s'ajoutent aux anciennes plaques, pas toujours bien stabilisées, qui persistent dans les versants Nord (présence de plusieurs couches fragiles plus ou moins enfouies). Localement, les volumes mobilisables peuvent être importants. En altitude, le passage d'un seul skieur suffit à déclencher une plaque. En dessous de 1800 m, la vieille neige est bien tassée, les nouvelles plaques en neige humide sont peu épaisses et plus difficiles à solliciter.
Départs spontanés : Cette nuit de jeudi à vendredi, au-dessus de 1700 à 1800 m, les chutes de neige entrainent des coulées et avalanches de neige fraîche de taille moyenne, surtout dans les pentes raides. Quelques avalanches de grande taille (taille 3) sont attendues dans les zones d'accumulation au-dessus de 1800 m. En journée de vendredi, le risque de départ spontané est plus faible.
Autres : Risque de glissade en neige dure ou glacée sur les crêtes et sommets balayés par le vent d'Ouest.

Qualité de la neige

Qualification de l'enneigement : L'enneigement est excellent pour la saison à toutes altitudes. On relève 2m82 sur la Maniccia à 2350 m dans le massif du Rotondo.
Limite d'enneigement skiable : vers 1500 m.
État de la neige : Avec les récentes pluies, la neige est devenue humide jusque vers 2000 à 2200 m environ, généralement portante (parfois soupe à basse altitude). En altitude, elle reste sèche, légère et profonde à l'abri du vent d'Ouest. On trouve localement des accumulations de neige roulée. La neige est très changeante (dure, carton, regelée) dans les secteurs ventés. Corniches et accumulations parfois volumineuses en place. Les crêtes et sommets, balayés par le vent d'Ouest, sont souvent durs et glacés.

Aperçu météo pour le vendredi 13 février

	nuit	matin	après-midi	soir
	Temps ensoleillé le matin se couvrant l'après-midi, nouvelles chutes de neige en soirée			
Pluie-Neige				1700 m
Iso 0 °C	1900 m	2300 m	2100 m	2100 m
Vent 1500 m	→ 50 km/h	↗ 40 km/h	↗ 30 km/h	↖ 35 km/h
Vent 3000 m	→ 60 km/h	→ 55 km/h	↗ 35 km/h	↖ 45 km/h

Épaisseur de neige hors-piste

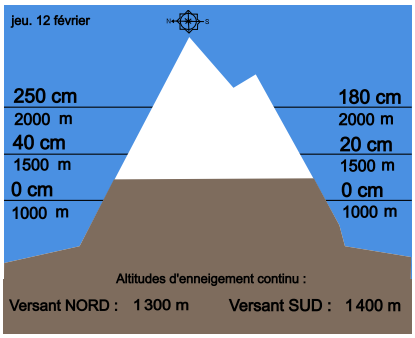

Précipitations à 1800 m

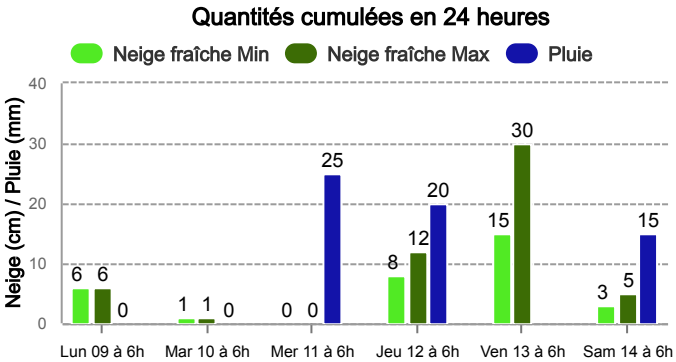

Tendance du samedi 14 février

3 **Indice de risque marqué**

Temps couvert accompagné d'averses localisées. Plaques non stabilisées. Persistance d'un risque marqué.

Pour consulter la vigilance en cours, veuillez vous rendre sur le site https://vigilance.meteofrance.fr/fr

Météo-France - 73 avenue de Paris, 94165 Saint-Mandé cedex - Contact : contact@meteo.fr

Rédigé par Météo-France avec la contribution des observateurs du réseau nivo-météorologiques. Partenariat : ANMSM (Maires de Stations de Montagne), DSF (Domaines Skiables de France), ADSP (Directeurs de Pistes et de la Sécurité des Stations de Sports d'Hiver) et autres acteurs de la montagne.

Bulletin neige & avalanches par téléphone au 0 892 68 10 20 Service 0,35 € / min + prix appel

Bulletin d'estimation du risque d'avalanche

(valable en dehors des pistes balisées et ouvertes)

MASSIF : Cinto Rotondo

Rédigé le jeudi 12 février 2026 à 15h

Conditions nivo-météo des 7 derniers jours

	ven. 06/02				sam. 07/02				dim. 08/02				lun. 09/02				mar. 10/02				mer. 11/02				jeu. 12/02			
	03h	09h	15h	21h	03h	09h	15h	21h	03h	09h	15h	21h	03h	09h	15h	21h	03h	09h	15h	21h	03h	09h	15h	21h	03h	09h	15h	21h
Météo																												
Vent (km/h)	100	85	80	65	65	45	60	45	65	15	20	20	15	10	15	20	30	25	40	60	80	100	100	90	80	120	100	100
à 3000m																												
Vent (km/h)	80	70	70	55	55	30	45	35	45	10	20	15	10	10	10	10	10	10	20	30	50	90	90	90	70	80	80	70
à 1500m																												

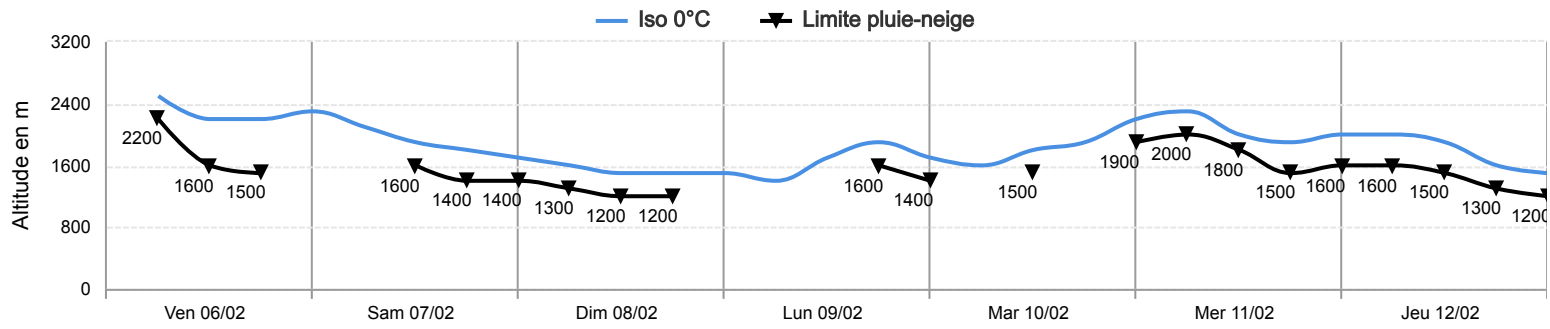

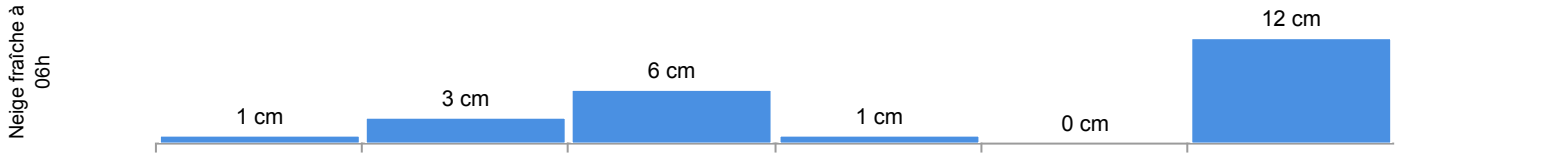

Risque d'avalanche	ven. 06/02	sam. 07/02	dim. 08/02	lun. 09/02	mar. 10/02	mer. 11/02	jeu. 12/02
	3	3	3	3	2	3	4

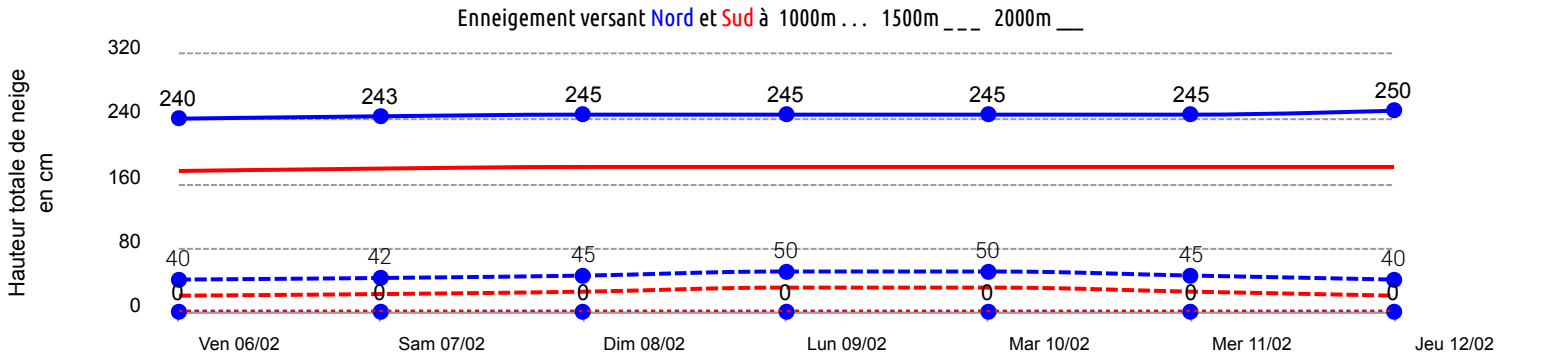

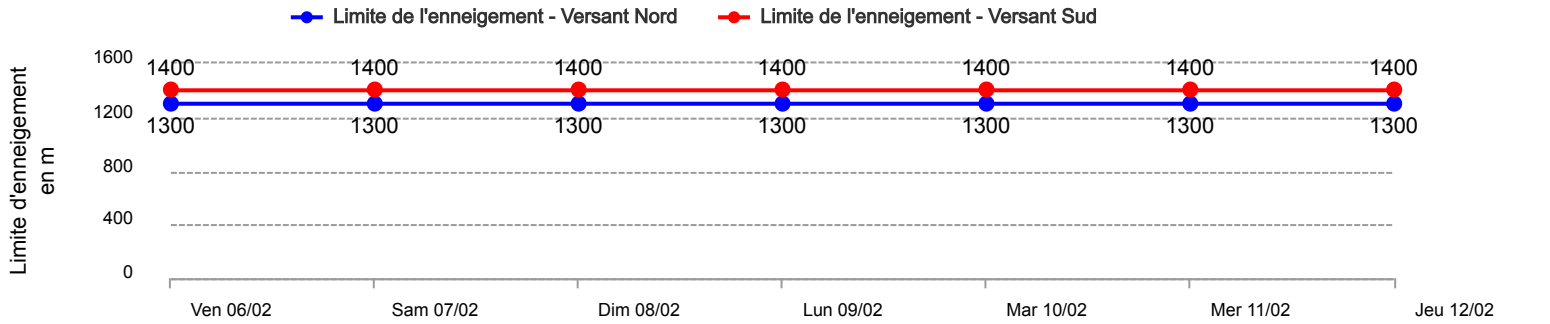

Pour consulter la vigilance en cours, veuillez vous rendre sur le site https://vigilance.meteofrance.fr/fr

Météo-France - 73 avenue de Paris, 94165 Saint-Mandé cedex - Contact : contact@meteo.fr

Rédigé par Météo-France avec la contribution des observateurs du réseau nivo-météorologiques. Partenariat : ANMSM (Maires de Stations de Montagne), DSF (Domaines Skiables de France), ADSP (Directeurs de Pistes et de la Sécurité des Stations de Sports d'Hiver) et autres acteurs de la montagne.

Bulletin neige & avalanches par téléphone au 0 892 68 10 20 Service 0,35 € / min + prix appel