Bulletin d'estimation du risque d'avalanche

(valable en dehors des pistes balisées et ouvertes)

MASSIF : Bauges

Rédigé le jeudi 12 février 2026 à 16h

Estimation des risques pour le : VENDREDI 13 FÉVRIER

FIN D'UN GROS ÉPISODE NEIGEUX

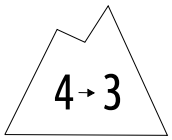

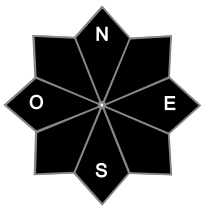

Indices de risque : 5 très fort - 4 fort - 3 marqué - 2 limité - 1 faible -- En noir : les pentes les plus dangereuses

Indice de risque fort évoluant en marqué.

Départs spontanés : très grandes avalanches pouvant parcourir de grande dénivellation jeudi soir

Déclenchements provoqués : risque maximal

Vigilance orange avalanches en cours ou prévue sur le massif

Stabilité du manteau neigeux

Situation avalancheuse typique : neige fraîche

Départs spontanés :

* **très nombreuses avalanches de neige fraîche, risque fort encore en soirée de jeudi .** Taille 2 à 3 (moyenne à grande), rarement 4 (très grande). Ces très grandes avalanches pourraient parcourir d'importante dénivellation.
* **En journée de vendredi, l'activité spontanée est en nette baisse**. Quelques départs dans les pentes raides dans les versants ensoleillés et sous 2000 m tous versants. Taille 1 à 2 (petite à moyenne). Au-dessus de 1800/2000 m : une grande avalanche est possible avec une chute de corniche ou en départ en cascade. Taille 3.

Déclenchements provoqués :

* **nombreuses plaques friables** encore présentes dans la neige fraîche. **Très facilement déclenchables**. **Généralisées à toutes les pentes**. Taille 2 à 3 (moyenne à grande), plus rarement 4 (très grande) proche des plus hauts sommets.

Qualité de la neige

Enneigement : Pour la saison, l'enneigement est dans la normale. On peut chausser les skis vers 1300/1400 m. Nombreuses congères et grosses corniches.

Qualité de la neige ce vendredi matin :
Au-dessus de 1500 m : neige fraiche, par endroit très ventée. En dessous, la neige est très humide. En journée, elle s'humidifie en surface sous 2000 m.

Aperçu météo pour le vendredi 13 février

Nuit : averses de neige, ventées. Journée: éclaircie et remontée de l'iso 0°C, baisse du vent.

	nuit	matin	après-midi	soir
Pluie-Neige	1 100 m			1 300 m
Iso 0 °C	1 300 m	1 700 m	1 900 m	1 700 m
Vent 1500 m	→ 20 km/h	↗ 20 km/h	↗ 20 km/h	↑ 10 km/h
Vent 2000 m	→ 40 km/h	↗ 25 km/h	↗ 30 km/h	↑ 25 km/h

Épaisseur de neige hors-piste

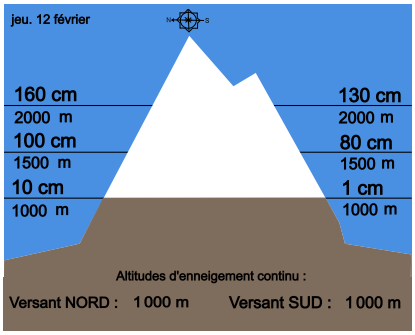

Précipitations à 1800 m

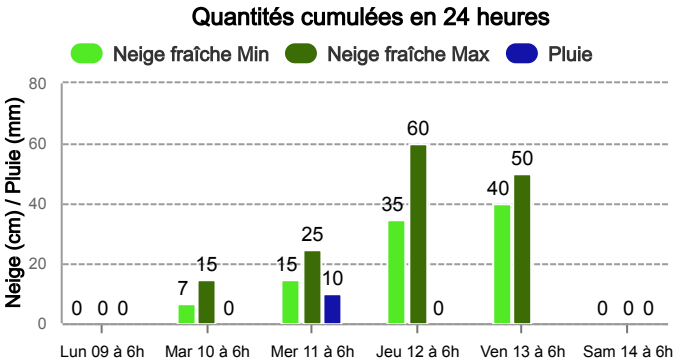

Tendance du samedi 14 février

Indice de risque marqué

Stabilisation du manteau neigeux en cours.

Pour consulter la vigilance en cours, veuillez vous rendre sur le site https://vigilance.meteofrance.fr/fr

Météo-France - 73 avenue de Paris, 94165 Saint-Mandé cedex - Contact : contact@meteo.fr

Rédigé par Météo-France avec la contribution des observateurs du réseau nivo-météorologiques. Partenariat : ANMSM (Maires de Stations de Montagne), DSF (Domaines Skiables de France), ADSP (Directeurs de Pistes et de la Sécurité des Stations de Sports d'Hiver) et autres acteurs de la montagne.

Bulletin neige & avalanches par téléphone au **0 892 68 10 20** Service 0,35 € / min + prix appel

RÉPUBLIQUE FRANÇAISE
Liberté Égalité Fraternité

METEO FRANCE
À VOS CÔTÉS, DANS UN CLIMAT QUI CHANGE

Bulletin d'estimation du risque d'avalanche

(valable en dehors des pistes balisées et ouvertes)

MASSIF : Bauges

Rédigé le jeudi 12 février 2026 à 16h

Conditions nivo-météo des 7 derniers jours

	ven. 06/02				sam. 07/02				dim. 08/02				lun. 09/02				mar. 10/02				mer. 11/02				jeu. 12/02			
	03h	09h	15h	21h	03h	09h	15h	21h	03h	09h	15h	21h	03h	09h	15h	21h	03h	09h	15h	21h	03h	09h	15h	21h	03h	09h	15h	21h
Météo																												
Vent (km/h)	30	30	25	20	20	10	10	10	10	10	15	10	10	15	25	45	45	55	40	50	65	50	45	65	50	60	50	80
à 2000m																												
Vent (km/h)	25	25	20	10	10	5	5	5	5	5	10	5	5	10	15	35	35	40	30	40	50	40	35	55	45	40	40	50
à 1500m																												

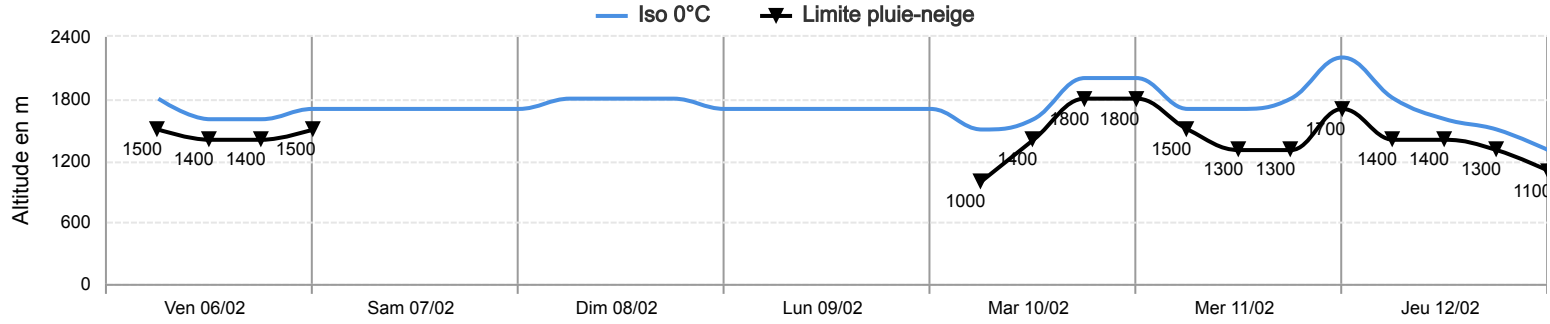

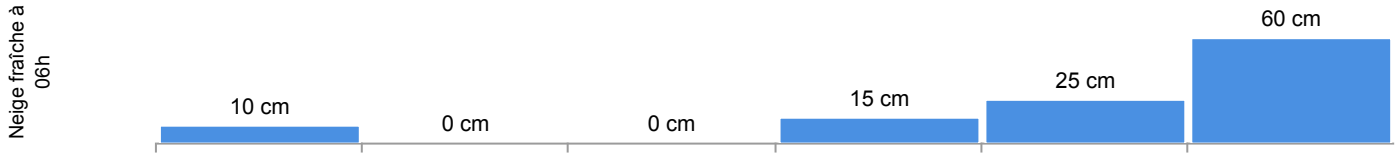

Risque d'avalanche							
	ven. 06/02	sam. 07/02	dim. 08/02	lun. 09/02	mar. 10/02	mer. 11/02	jeu. 12/02

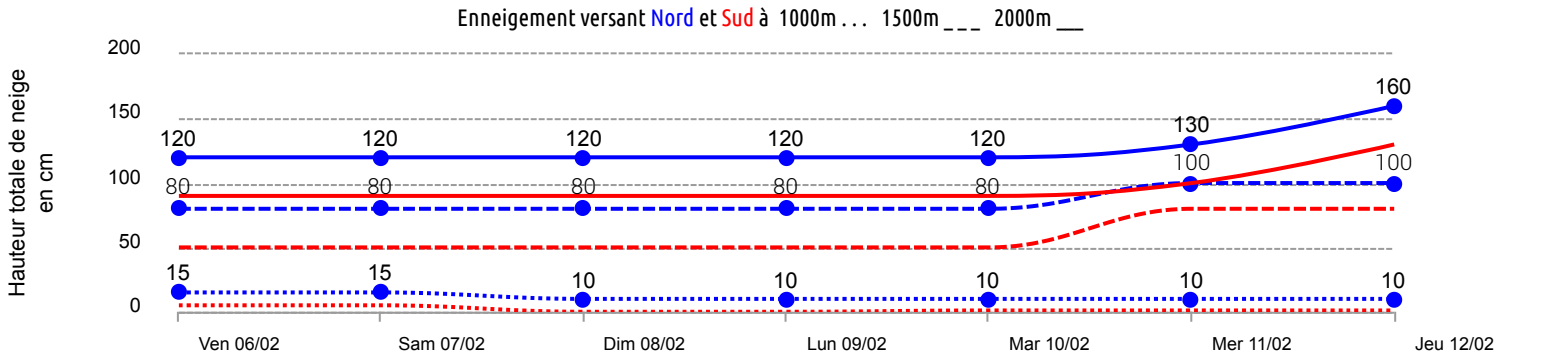

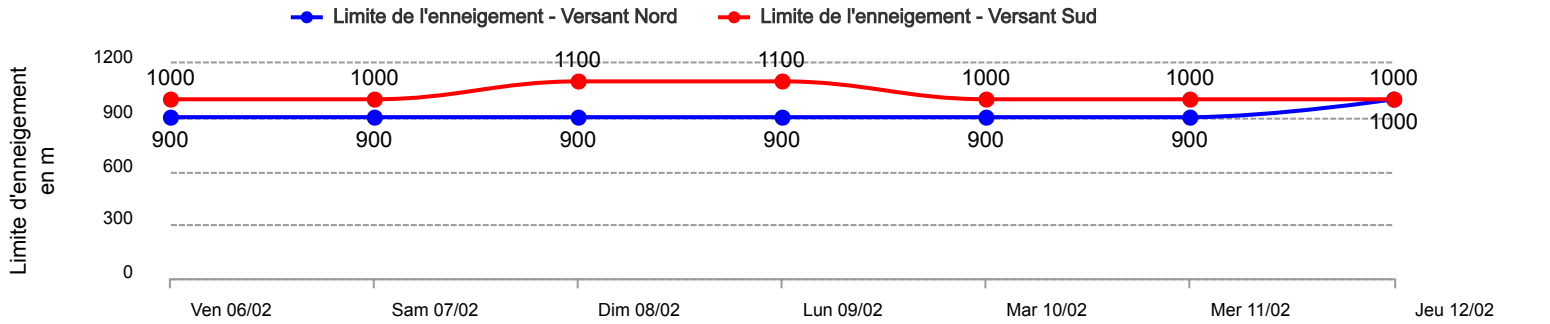

Pour consulter la vigilance en cours, veuillez vous rendre sur le site https://vigilance.meteofrance.fr/fr

Météo-France - 73 avenue de Paris, 94165 Saint-Mandé cedex - Contact : contact@meteo.fr

Rédigé par Météo-France avec la contribution des observateurs du réseau nivo-météorologiques. Partenariat : ANMSM (Maires de Stations de Montagne), DSF (Domaines Skiables de France), ADSP (Directeurs de Pistes et de la Sécurité des Stations de Sports d'Hiver) et autres acteurs de la montagne.

Bulletin neige & avalanches par téléphone au
0 892 68 10 20 Service 0,35 € / min + prix appel