Bulletin d'estimation du risque d'avalanche
(valable en dehors des pistes balisées et ouvertes)
MASSIF : Chartreuse

Rédigé le jeudi 12 février 2026 à 16h

Estimation des risques pour le : VENDREDI 13 FÉVRIER

IMPORTANTES QUANTITES DE NEIGE FRAICHE SOUFFLEE EN ALTITUDE, ENCORE BIEN INSTABLE JEUDI SOIR... VENDREDI ENCORE UN RISQUE DE PLAQUES VERS LES CRETES...

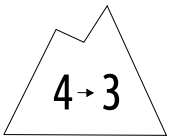

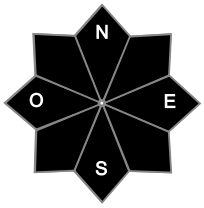

Surtout jeudi soir

Indice de risque fort évoluant en marqué.

Départs spontanés : Jeudi soir/début de nuit, encore quelques avalanches possibles sous le vent de Nord-Ouest (parfois grandes). Vendredi moins d'activité ou des avalanches plus superficielles/près des rochers. En pentes herbeuses rare départ de fond...

Déclenchements provoqués : Risque accidentel encore localement marqué vers les hautes crêtes et sommets. Accumulations sous le vent de Nord-Ouest, puis vendredi après-midi un peu de vent de Sud...

Indices de risque : 5 très fort - 4 fort - 3 marqué - 2 limité - 1 faible -- En noir : les pentes les plus dangereuses

Stabilité du manteau neigeux

Situation avalancheuse typique : neige fraîche avalanches de fond

Jeudi soir encore neigeux sous le vent de Nord-Ouest, quelques grandes avalanches possibles en altitude. Vendredi plus calme et sec, mais risque accidentel de plaque encore localement marqué à l'abord des crêtes et sommets...

Départs spontanés :

Jeudi en soirée/début de nuit, encore des chutes de neige sous le vent de Nord-Ouest avec jusque 40/60 cm de fraîche en altitude. On attend quelques avalanches spontanées en pentes/couloirs d'altitude, parfois de taille moyenne à grandes (ruptures linéaires).

Vendredi a priori moins d'activité. Néanmoins lors de brèves éclaircies on s'attend à des avalanches de surface en pentes "réchauffées", près des rochers...

Noter qu'en pentes herbeuses raides (sous 1600 voire 1800m), la neige est assez humide en profondeur, on s'attend à quelques avalanches de fond avec glissement possible jusqu'au terrain.

Déclenchements provoqués : Vendredi, encore un risque accidentel de plaques, notamment à proximité des crêtes et sommets, parfois en pieds de barres.

Un seul skieur peut parfois déclencher une plaque assez conséquente. (Sous couche plus poudreuse représentant une couche fragile temporaire)... A modeste altitude, en neige plus humide, plutôt un risque de coulée ponctuelle sous les skis...

Qualité de la neige

Qualification de l'enneigement : L'enneigement s'est récemment dégradé aux basses altitudes, sous les sapins mais il est bon pour la saison dès la moyenne montagne et dans les combes sommitales... Crêtes parfois dégarnies/ congères et corniches...

Limites skiables : Vers 1200/1400 m, sur les pistes forestières/clairières...

Qualité de la neige vendredi : A basse altitude, regel au matin, plaques de glace... dès la moyenne montagne neige poudreuse, plus conséquente au dessus de 1500/1700m : 40/60 cm environ. Souvent ventée vers les hautes crêtes et sommets/ durcie, sculptée parfois. Lors de timides éclaircies, neige s'humidifiant au soleil, plutôt sous 1500/1800m...

Aperçu météo pour le vendredi 13 février

	nuit	matin	après-midi	soir

Jeudi soir averses de neige. Vendredi matin plus sec, calme. L'après-midi temps couvert en altitude, 2 flocons, un peu de vent de Sud...

Pluie-Neige	1 100 m		1 300 m	1 300 m
Iso 0 °C	1 400 m	1 900 m	1 700 m	1 700 m
Vent 1500 m	↘ 25 km/h	↑ 15 km/h	↗ 25 km/h	↖ 10 km/h
Vent 2000 m	↘ 70 km/h	↗ 35 km/h	↑ 35 km/h	↑ 25 km/h

Épaisseur de neige hors-piste

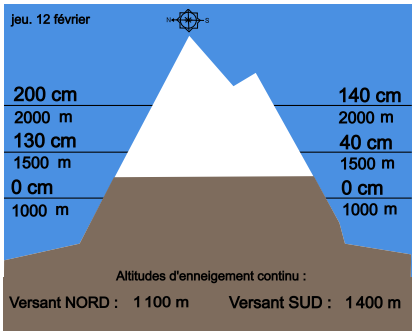

Précipitations à 1800 m

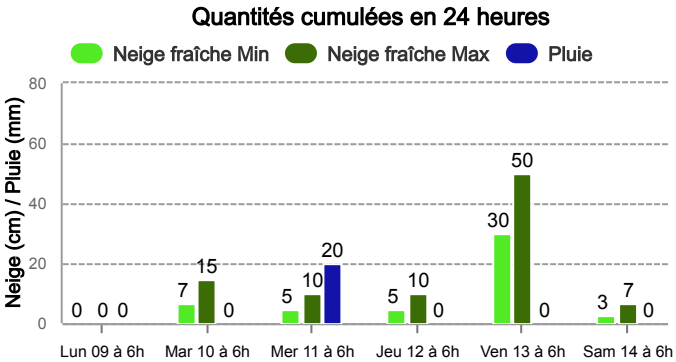

Tendance du samedi 14 février

Indice de risque marqué

Peu d'évolution. Vent de Nord se renforçant l'après-midi/le soir avec des giboulées de neige en vue jusqu'à assez basse altitude (Ouest Chartreuse notamment). Risque de plaques marqué à l'approche des crêtes.

Pour consulter la vigilance en cours, veuillez vous rendre sur le site https://vigilance.meteofrance.fr/fr

Météo-France - 73 avenue de Paris, 94165 Saint-Mandé cedex - Contact : contact@meteo.fr

Rédigé par Météo-France avec la contribution des observateurs du réseau nivo-météorologiques. Partenariat : ANMSM (Maires de Stations de Montagne), DSF (Domaines Skiables de France), ADSP (Directeurs de Pistes et de la Sécurité des Stations de Sports d'Hiver) et autres acteurs de la montagne.

Bulletin neige & avalanches par téléphone au 0 892 68 10 20 Service 0,35 € / min + prix appel

Bulletin d'estimation du risque d'avalanche

(valable en dehors des pistes balisées et ouvertes)

MASSIF : Chartreuse

Rédigé le jeudi 12 février 2026 à 16h

Conditions nivo-météo des 7 derniers jours

	ven. 06/02				sam. 07/02				dim. 08/02				lun. 09/02				mar. 10/02				mer. 11/02				jeu. 12/02			
	03h	09h	15h	21h	03h	09h	15h	21h	03h	09h	15h	21h	03h	09h	15h	21h	03h	09h	15h	21h	03h	09h	15h	21h	03h	09h	15h	21h
Météo																												
Vent (km/h)	60	35	30	20	15	15	5	5	15	20	15	10	15	30	35	35	50	40	50	70	65	65	65	100	85	70	70	65
à 2000m																												
Vent (km/h)	30	20	15	10	10	5	10	10	10	5	5	5	5	10	20	25	40	30	35	50	40	30	35	85	70	50	45	35
à 1500m																												

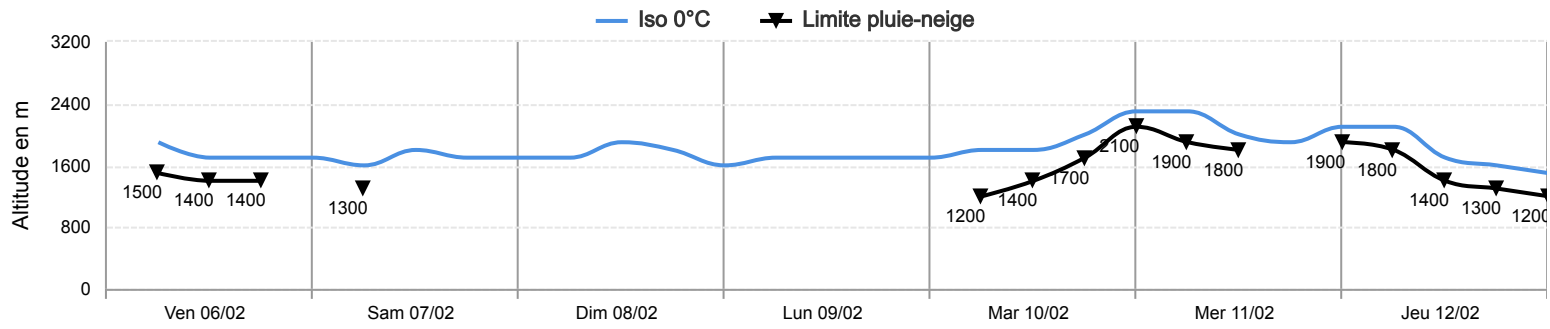

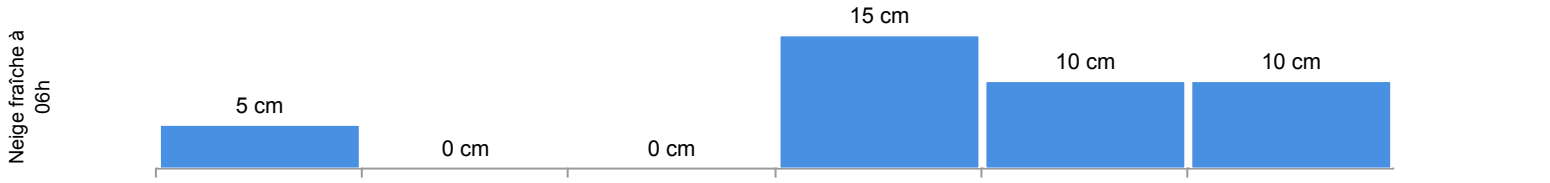

Risque d'avalanche	ven. 06/02	sam. 07/02	dim. 08/02	lun. 09/02	mar. 10/02	mer. 11/02	jeu. 12/02
	3	2	2	2	3	3	3

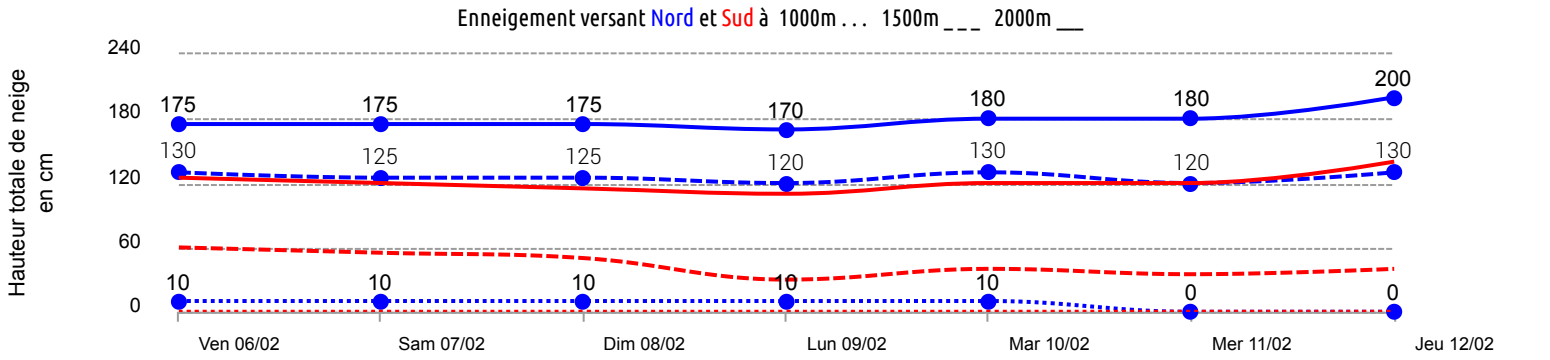

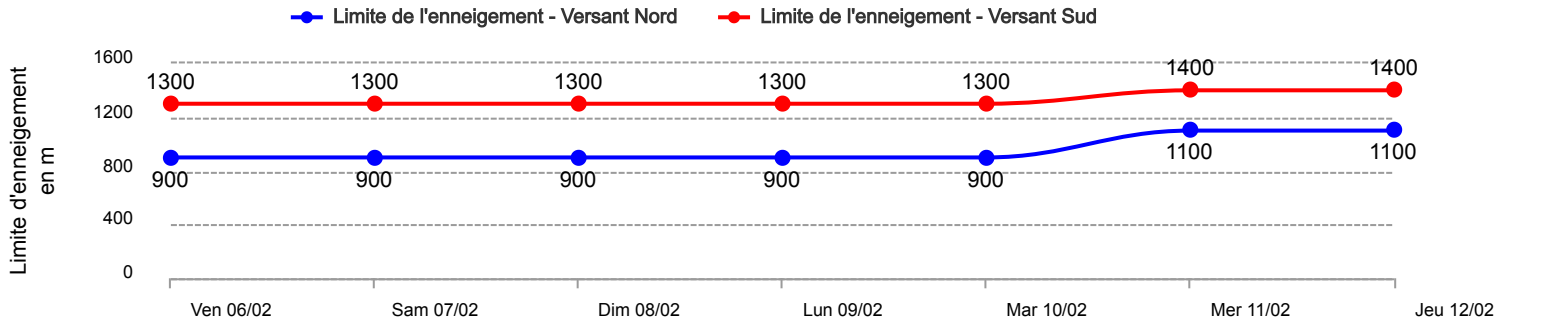

Pour consulter la vigilance en cours, veuillez vous rendre sur le site https://vigilance.meteofrance.fr/fr

Météo-France - 73 avenue de Paris, 94165 Saint-Mandé cedex - Contact : contact@meteo.fr

Bulletin neige & avalanches par téléphone au

0 892 68 10 20 Service 0,35 € / min + prix appel

Rédigé par Météo-France avec la contribution des observateurs du réseau nivo-météorologiques. Partenariat : ANMSM (Maires de Stations de Montagne), DSF (Domaines Skiables de France), ADSP (Directeurs de Pistes et de la Sécurité des Stations de Sports d'Hiver) et autres acteurs de la montagne.