Bulletin d'estimation du risque d'avalanche

(valable en dehors des pistes balisées et ouvertes)

MASSIF : Couserans

Rédigé le jeudi 12 février 2026 à 16h

Estimation des risques pour le : VENDREDI 13 FÉVRIER

PLAQUES EN ALTITUDE ET POURSUITE DE L'HUMIDIFICATION DU MANTEAU DE 2000M

2

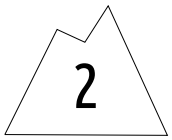

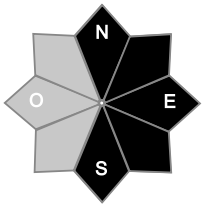

Indice de risque limité.

Départs spontanés : Dans la neige humide

Déclenchements provoqués : Fines plaques à vent en altitude

Indices de risque : 5 très fort - 4 fort - 3 marqué - 2 limité - 1 faible -- En noir : les pentes les plus dangereuses

Stabilité du manteau neigeux

Situation avalancheuse typique : neige ventée avalanches de fond

Déclenchements provoqués :

*En altitude, des structures de plaques dures, encore facilement déclenchables sont présentes et continueront de se former avec le vent et les précipitations dans un large secteur Est (du nord au sud en passant par l'est). Elles sont généralement fines, un peu plus épaisses proche de la crête frontalière où les précipitations débuteront plus tôt dans la journée. Elles donneront des avalanches de taille 1 à 2 (petites à moyennes).
Observables : accumulations en neige récente cartonnée, voisinant avec des zones glacées ou en vieille neige regelée, fissures sous les skis.

Départs spontanés :

*En dessous de 2000m environ, des avalanches de fond peuvent encore se produire en toutes orientations et à toute heure (l'humidification gagnant encore un peu en profondeur dans le manteau neigeux). Elle pourront générer des avalanches de taille 1 à 3 (petites à moyennes).
Observable : Neige pourrie en profondeur, large fissure d'apparition récente en pentes herbeuses / dalles rocheuses.
*Les chutes de neige des dernières 24h vont s'humidifier en journée à la faveur des éclaircies et pourront générer de petites avalanches à départ ponctuels dans les pentes raides, pouvant déstabiliser un skieur.
Observables : Boulettes/escargots

Autre :

Présence en altitude de zones de glace dure, lustrées par le vent, sur lesquelles l'adhérence est limitée.

Qualité de la neige

Enneigement :

Après plusieurs hivers déficitaires, l'enneigement sur le massif en cette mi-Février demeure légèrement au-dessus des normales et nettement supérieur à celui des cinq dernières années.
Malgré le fort redoux très arrosé du début de semaine, la limite de skiabilité se situe encore au plus bas vers 1300/1400 m dans les meilleures configurations. On peut skier plus confortablement vers 1500/1600m

État de la neige :

Au petit matin, un peu de neige récente très ventée recouvrira en dessous de 2000m une neige croutée plus ou moins portante. En altitude, on trouvera une neige souvent dure et travaillée par le vent, pas forcément agréable à skier. Au son cœur, le manteau neigeux restera encore souvent imbibé d'eau liquide en dessous de 2000 m et les skis pourront coller quand en surface ils auront rencontré une neige plus froide.

Aperçu météo pour le vendredi 13 février

Chutes de neige en secteur frontalier, se généralisant en fin de journée

	nuit	matin	après-midi	soir
Pluie-Neige	1 500 m	1 600 m	1 500 m	1 100 m
Iso 0 °C	2 000 m	2 100 m	1 900 m	1 500 m
Vent 2000 m	↑ 40 km/h	↑ 65 km/h	→ 35 km/h	↘ 65 km/h
Vent 3000 m	↘ 75 km/h	↑ 80 km/h	↑ 70 km/h	↓ 80 km/h

Pour consulter la vigilance en cours, veuillez vous rendre sur le site https://vigilance.meteofrance.fr/fr

Météo-France - 73 avenue de Paris, 94165 Saint-Mandé cedex - Contact : contact@meteo.fr

Rédigé par Météo-France avec la contribution des observateurs du réseau nivo-météorologiques. Partenariat : ANMSM (Maires de Stations de Montagne), DSF (Domaines Skiables de France), ADSP (Directeurs de Pistes et de la Sécurité des Stations de Sports d'Hiver) et autres acteurs de la montagne.

Bulletin neige & avalanches par téléphone au 0 892 68 10 20 Service 0,35 € / min + prix appel

Bulletin d'estimation du risque d'avalanche

(valable en dehors des pistes balisées et ouvertes)

MASSIF : Couserans

Rédigé le jeudi 12 février 2026 à 16h

Épaisseur de neige hors-piste

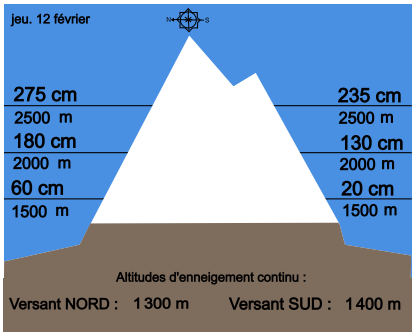

Précipitations à 1800 m

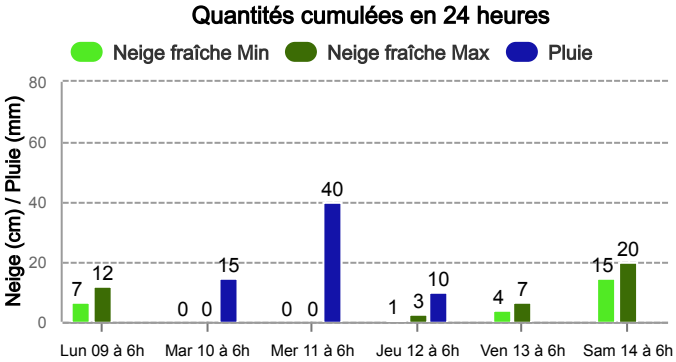

Tendance du samedi 14 février

Indice de risque marqué

Risque naturel et accidentel en hausse avec de nouvelles chutes de neige ventée prévues.

Pour consulter la vigilance en cours, veuillez vous rendre sur le site https://vigilance.meteofrance.fr/fr

Météo-France - 73 avenue de Paris, 94165 Saint-Mandé cedex - Contact : contact@meteo.fr

Rédigé par Météo-France avec la contribution des observateurs du réseau nivo-météorologiques. Partenariat : ANMSM (Maires de Stations de Montagne), DSF (Domaines Skiables de France), ADSP (Directeurs de Pistes et de la Sécurité des Stations de Sports d'Hiver) et autres acteurs de la montagne.

Bulletin neige & avalanches par téléphone au

0 892 68 10 20 Service 0,35 € / min + prix appel

RÉPUBLIQUE FRANÇAISE
Liberté Égalité Fraternité

METEO FRANCE
À VOS CÔTÉS, DANS UN CLIMAT QUI CHANGE

Bulletin d'estimation du risque d'avalanche

(valable en dehors des pistes balisées et ouvertes)

MASSIF : Couserans

Rédigé le jeudi 12 février 2026 à 16h

Conditions nivo-météo des 7 derniers jours

	ven. 06/02				sam. 07/02				dim. 08/02				lun. 09/02				mar. 10/02				mer. 11/02				jeu. 12/02			
	03h	09h	15h	21h	03h	09h	15h	21h	03h	09h	15h	21h	03h	09h	15h	21h	03h	09h	15h	21h	03h	09h	15h	21h	03h	09h	15h	21h
Météo																												
Vent (km/h)	40	25	25	30	30	20	20	55	55	25	50	45	40	40	60	50	40	45	50	65	70	60	65	70	95	100	90	70
à 3000m	→	→	→	↘	↘	↘	↘	→	↑	↘	↘	→	→	→	→	→	↘	→	↗	↓	↘	↘	↗	→	↘	↘	↘	↘
Vent (km/h)	25	15	15	20	20	15	15	40	45	10	45	40	35	25	50	30	30	30	40	45	50	35	40	55	65	80	75	40
à 2000m	→	→	→	↘	↑	↘	↘	→	↑	↘	→	→	→	→	→	→	↗	→	→	→	→	→	↗	→	↗	↘	↘	→

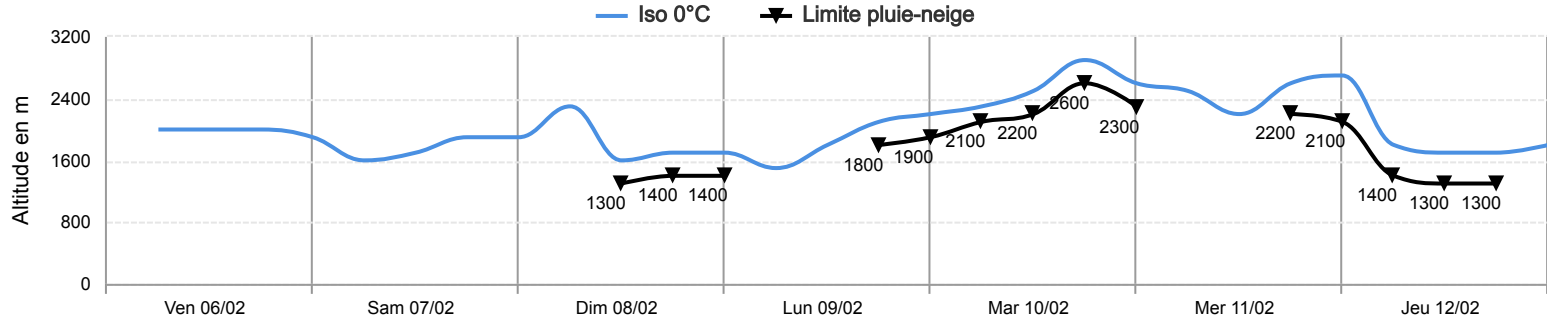

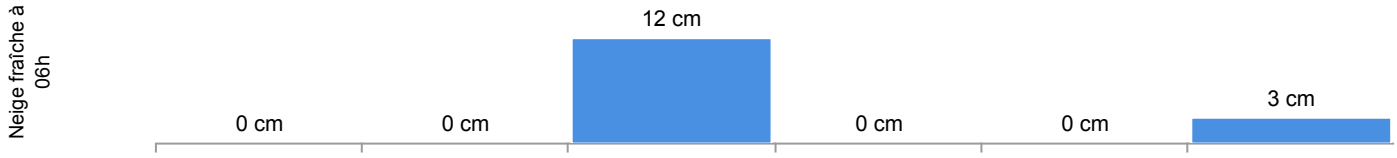

Risque d'avalanche	ven. 06/02	sam. 07/02	dim. 08/02	lun. 09/02	mar. 10/02	mer. 11/02	jeu. 12/02
	2	2	2	2	4	4	3

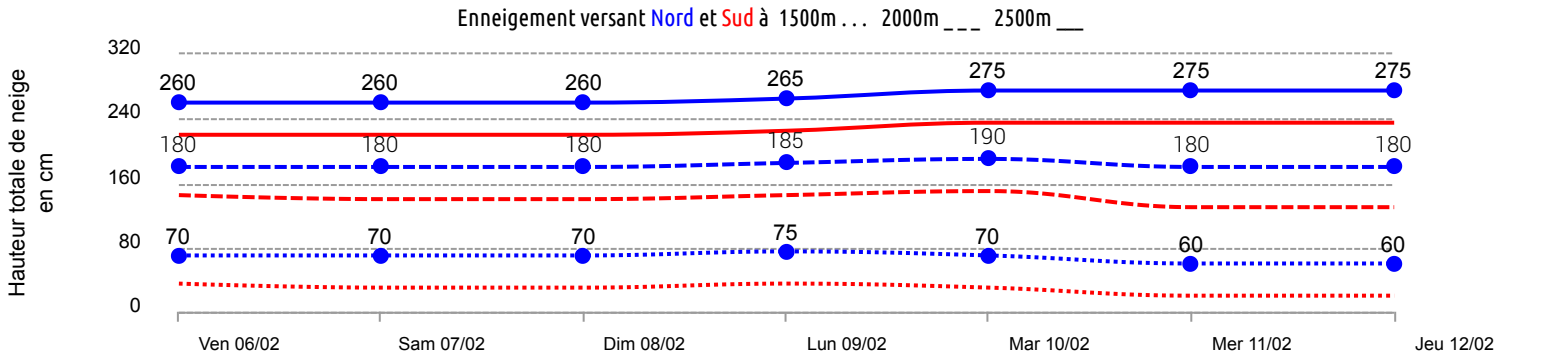

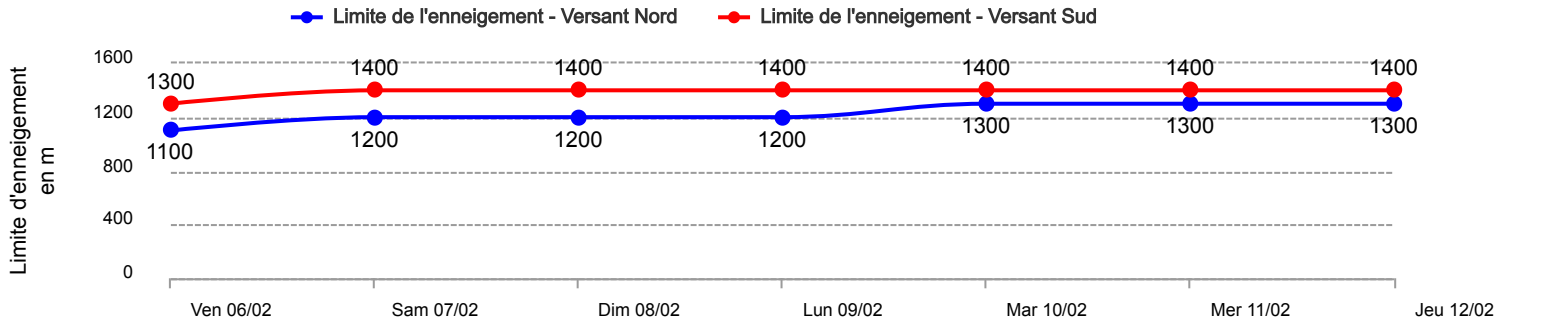

Pour consulter la vigilance en cours, veuillez vous rendre sur le site https://vigilance.meteofrance.fr/fr

Météo-France - 73 avenue de Paris, 94165 Saint-Mandé cedex - Contact : contact@meteo.fr

Rédigé par Météo-France avec la contribution des observateurs du réseau nivo-météorologiques. Partenariat : ANMSM (Maires de Stations de Montagne), DSF (Domaines Skiables de France), ADSP (Directeurs de Pistes et de la Sécurité des Stations de Sports d'Hiver) et autres acteurs de la montagne.

Bulletin neige & avalanches par téléphone au
0 892 68 10 20 Service 0,35 € / min + prix appel