Bulletin d'estimation du risque d'avalanche

(valable en dehors des pistes balisées et ouvertes)

MASSIF : Devoluy

Rédigé le jeudi 12 février 2026 à 16h

Estimation des risques pour le : VENDREDI 13 FÉVRIER

MANTEAU NEIGEUX RESTANT INSTABLE

3

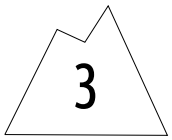

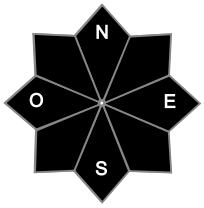

Indice de risque marqué.

Départs spontanés : départs ponctuels ou en plaque de neige fraîche dans de nombreuses pentes.

Déclenchements provoqués : plaques dans de nombreuses pentes, faciles à déclencher.

Indices de risque : 5 très fort - 4 fort - 3 marqué - 2 limité - 1 faible -- En noir : les pentes les plus dangereuses

Stabilité du manteau neigeux

Situation avalancheuse typique : neige fraîche couche fragile persistante

Déclenchements provoqués : manteau neigeux encore peu stabilisé dans de nombreuses pentes. Fréquentes plaques dans la neige fraîche ventée, faciles à déclencher. Elles engendrent des avalanches moyennes (taille 2), voire grandes (taille 3) quand la topographie est favorable, emportant toute la couche de neige récente des derniers jours. Ponctuellement, une cassure emportant la totalité du manteau neigeux n'est pas exclue, mobilisant alors un important volume de neige.

Départs spontanés : jusqu'en seconde partie de nuit de jeudi à vendredi, avalanches de neige fraîche. Départs en poire ou linéaires, emportant toute la couche de neige récente, parfois sur de grandes largeurs. Avalanches moyennes à grandes (taille 2 à 3). Une très grande avalanche (taille 4) non exclue, en cas de rupture sur une couche fragile persistante enfouie, dans un secteur à la topographie habituellement favorable.

Vendredi, en pente raide, de nouvelles avalanches de neige fraîche s'humidifiant avec le soleil / redoux temporaire. Départs en poire ou linéaires, de taille petite à moyenne, grande non exclue.

Qualité de la neige

L'enneigement est excédentaire pour un mois de février.
Hauteurs de neige observées : environ 100 cm vers 2000 m d'altitude.

Limite d'enneigement skiable : vers 1200/1300 m sur la plupart des itinéraires en ubacs, 1400/1500 m en adrets.

État de la neige de surface : en début de journée, neige fraiche en quantité plus ou moins travaillée par le vent, mais plus lourde/ humide sous 2000 m environ. Elle tombe un peu plus froide ensuite, mais devient fortement soufflée l'après-midi.

Aperçu météo pour le vendredi 13 février

	nuit	matin	après-midi	soir

Retour d'un temps sec et calme en 2nd partie de nuit de jeudi à vendredi. Nouvelle perturbation de faible activité dès vendredi après-midi.

Pluie-Neige	1 100 m		1 200 m	1 200 m
Iso 0 °C	1 500 m	1 900 m	2 000 m	1 500 m
Vent 2000 m	↘ 50 km/h	↑ 15 km/h	↑ 35 km/h	↖ 25 km/h
Vent 3000 m	↘ 60 km/h	↗ 20 km/h	↖ 40 km/h	↖ 25 km/h

Épaisseur de neige hors-piste

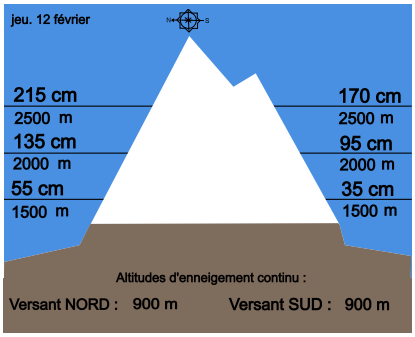

Précipitations à 1800 m

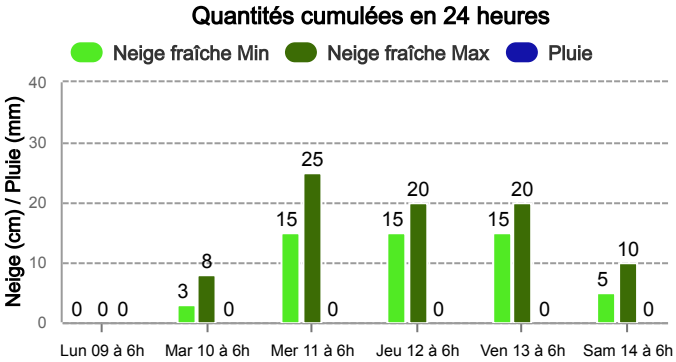

Tendance du samedi 14 février

3

Indice de risque marqué

Maintien d'un risque marqué avec des plaques encore faciles à déclencher au passage d'un skieur dans la neige récente.

Pour consulter la vigilance en cours, veuillez vous rendre sur le site https://vigilance.meteofrance.fr/fr

Météo-France - 73 avenue de Paris, 94165 Saint-Mandé cedex - Contact : contact@meteo.fr

Rédigé par Météo-France avec la contribution des observateurs du réseau nivo-météorologiques. Partenariat : ANMSM (Maires de Stations de Montagne), DSF (Domaines Skiables de France), ADSP (Directeurs de Pistes et de la Sécurité des Stations de Sports d'Hiver) et autres acteurs de la montagne.

Bulletin neige & avalanches par téléphone au **0 892 68 10 20** Service 0,35 € / min + prix appel

RÉPUBLIQUE FRANÇAISE
Liberté Égalité Fraternité

METEO FRANCE
À VOS CÔTÉS, DANS UN CLIMAT QUI CHANGE

Bulletin d'estimation du risque d'avalanche

(valable en dehors des pistes balisées et ouvertes)

MASSIF : Devoluy

Rédigé le jeudi 12 février 2026 à 16h

Conditions nivo-météo des 7 derniers jours

	ven. 06/02				sam. 07/02				dim. 08/02				lun. 09/02				mar. 10/02				mer. 11/02				jeu. 12/02			
	03h	09h	15h	21h	03h	09h	15h	21h	03h	09h	15h	21h	03h	09h	15h	21h	03h	09h	15h	21h	03h	09h	15h	21h	03h	09h	15h	21h
Météo																												
Vent (km/h)	40	45	35	20	15	10	10	5	10	25	25	10	5	15	15	20	30	40	40	60	60	65	55	45	70	60	100	100
à 3000m																												
Vent (km/h)	25	25	25	15	10	10	15	10	10	20	20	10	5	15	15	15	20	15	20	25	30	30	30	25	40	45	60	60
à 2000m																												

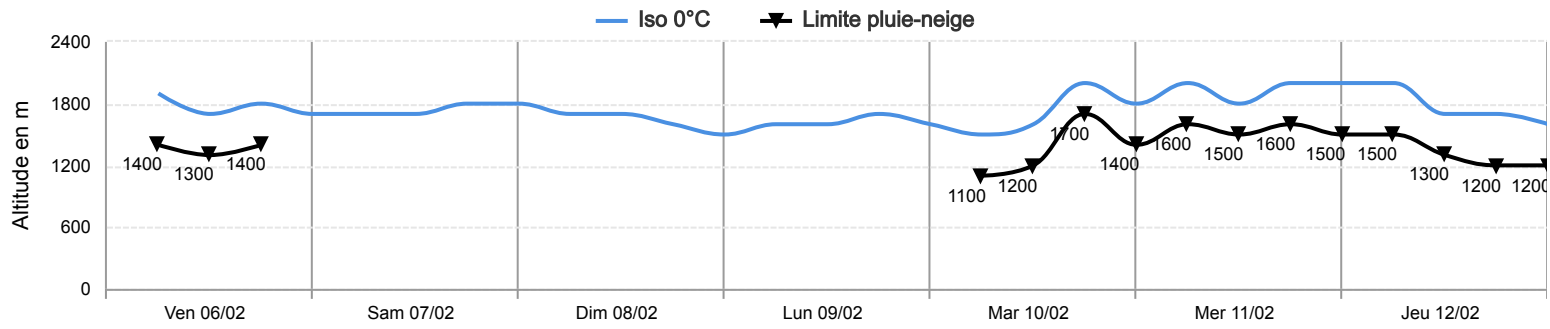

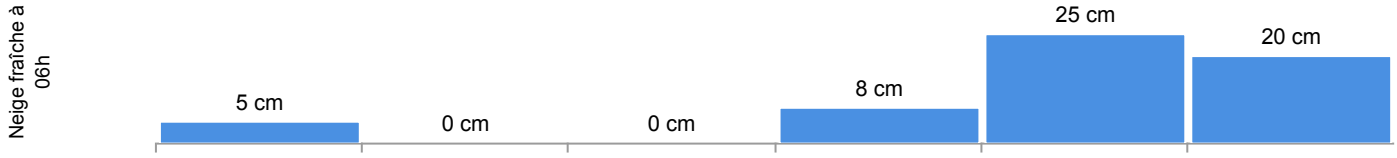

Risque d'avalanche	ven. 06/02	sam. 07/02	dim. 08/02	lun. 09/02	mar. 10/02	mer. 11/02	jeu. 12/02
	4	3	3	2	2	3	3

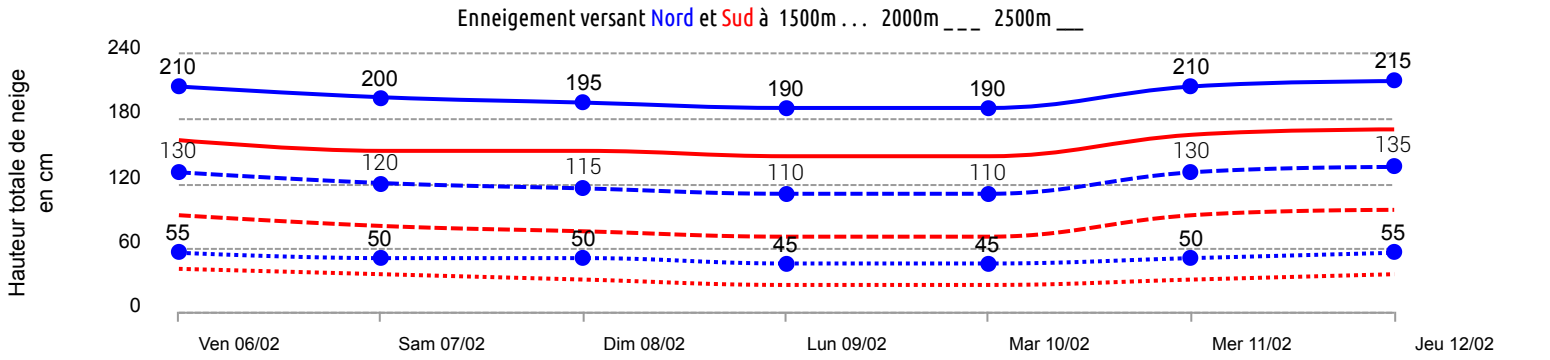

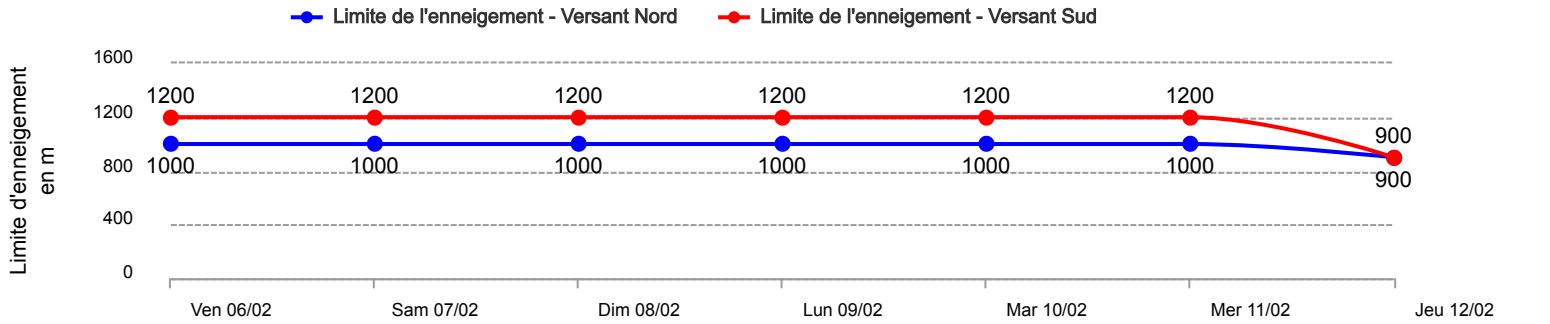

Pour consulter la vigilance en cours, veuillez vous rendre sur le site https://vigilance.meteofrance.fr/fr

Météo-France - 73 avenue de Paris, 94165 Saint-Mandé cedex - Contact : contact@meteo.fr

Rédigé par Météo-France avec la contribution des observateurs du réseau nivo-météorologiques. Partenariat : ANMSM (Maires de Stations de Montagne), DSF (Domaines Skiables de France), ADSP (Directeurs de Pistes et de la Sécurité des Stations de Sports d'Hiver) et autres acteurs de la montagne.

Bulletin neige & avalanches par téléphone au
0 892 68 10 20 Service 0,35 € / min + prix appel