RÉPUBLIQUE FRANÇAISE
Liberté Égalité Fraternité

METEO FRANCE
À VOS CÔTÉS, DANS UN CLIMAT QUI CHANGE

Bulletin d'estimation du risque d'avalanche
(valable en dehors des pistes balisées et ouvertes)
MASSIF : Embrunais Parpaillon

Rédigé le jeudi 12 février 2026 à 16h

Estimation des risques pour le : VENDREDI 13 FÉVRIER

FORTE INSTABILITÉ PERSISTANTE - PLAQUES PARFOIS ÉPAISSES

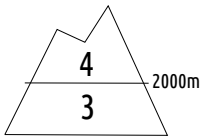

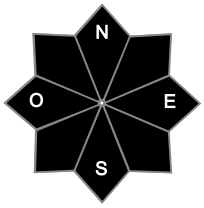

Au-dessus de 2000m indice de risque fort, plus bas indice marqué.

Départs spontanés : avalanches de neige fraîche, départs en poire ou souvent linéaires.

Déclenchements provoqués : nombreuses plaques faciles à déclencher.

Indices de risque : 5 très fort - 4 fort - 3 marqué - 2 limité - 1 faible -- En noir : les pentes les plus dangereuses

Stabilité du manteau neigeux

Situation avalancheuse typique : neige fraîche — couche fragile persistante

Invitation à la prudence en montagne (émission d'un communiqué spécial avalanche)

Déclenchements provoqués : manteau neigeux restant très instable, surtout au-dessus de 2000 m. Nombreuses plaques, faciles à déclencher dans la neige fraîche ventée. Elles engendrent des avalanches de taille moyenne à grande (taille 2 à 3), avec souvent de larges cassures. Dans les ubacs (pentes ouest, nord à est), des départs emportant la totalité du manteau neigeux en place restent possibles, en cas de rupture sur l'épaisse couche fragile persistante enfouie. Grandes avalanches (taille 3) attendues, une très grande (taille 4) non exclue dans un secteur à la topographie habituellement favorable.
Sous 2000 m, quelques plaques aussi présentes, mais moins généralisées, car la neige fraîche s'est en partie humidifiée.

Départs spontanés : quelques avalanches de neige fraîche. Départs en poire ou linéaires, de taille petite à moyenne, plus rarement grande. En effet, maintien du transport de neige par le vent jusqu'en seconde partie de nuit, puis vendredi avec le soleil / redoux temporaire.

Qualité de la neige

L'enneigement est plutôt excédentaire pour un mois de février.
Hauteurs de neige observées : 86 cm à la Nivôse du Parpaillon à 2550 m, secteur soufflé par le vent.

Limite d'enneigement skiable : dès 1200/1400 m en ubacs sur la plupart des itinéraires, plutôt 1400/1500 m en adrets.

État de la neige de surface : neige fraiche abondante souvent travaillée par le vent en altitude. Plus humide et lourde sous 1800/2000 m.

Aperçu météo pour le vendredi 13 février

Retour de conditions sèches et calmes en 2nd partie de nuit de jeudi à vendredi. Nouvelle pertrubation de faible activité dès vendredi après-midi.

	nuit	matin	après-midi	soir
Pluie-Neige			1 200 m	1 200 m
Iso 0 °C	1 500 m	2 000 m	2 000 m	1 700 m
Vent 2000 m	20 km/h	10 km/h	15 km/h	20 km/h
Vent 3000 m	50 km/h	30 km/h	30 km/h	25 km/h

Épaisseur de neige hors-piste

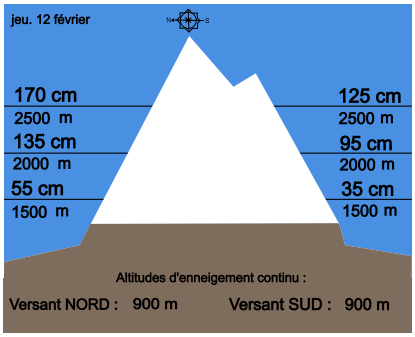

Précipitations à 1800 m

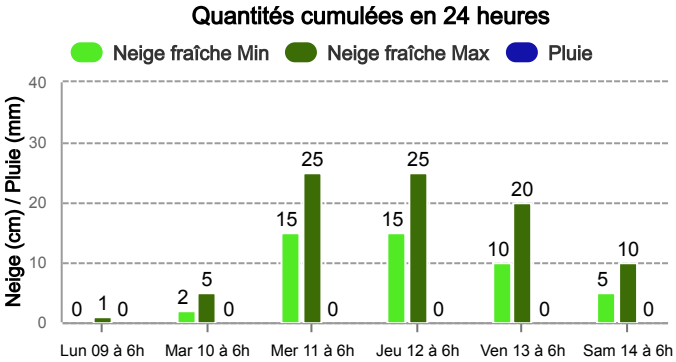

Tendance du samedi 14 février

Indice de risque fort

Maintien d'un risque fort en raison de plaques faciles à déclencher au passage d'un skieur. Cassures épaisses possibles.

Pour consulter la vigilance en cours, veuillez vous rendre sur le site https://vigilance.meteofrance.fr/fr

Météo-France - 73 avenue de Paris, 94165 Saint-Mandé cedex - Contact : contact@meteo.fr

Rédigé par Météo-France avec la contribution des observateurs du réseau nivo-météorologiques. Partenariat : ANMSM (Maires de Stations de Montagne), DSF (Domaines Skiables de France), ADSP (Directeurs de Pistes et de la Sécurité des Stations de Sports d'Hiver) et autres acteurs de la montagne.

Bulletin neige & avalanches par téléphone au
0 892 68 10 20 Service 0,35 € / min + prix appel

RÉPUBLIQUE FRANÇAISE
Liberté Égalité Fraternité

METEO FRANCE
À VOS CÔTÉS, DANS UN CLIMAT QUI CHANGE

Bulletin d'estimation du risque d'avalanche

(valable en dehors des pistes balisées et ouvertes)

MASSIF : Embrunais Parpaillon

Rédigé le jeudi 12 février 2026 à 16h

Conditions nivo-météo des 7 derniers jours

	ven. 06/02				sam. 07/02				dim. 08/02				lun. 09/02				mar. 10/02				mer. 11/02				jeu. 12/02			
	03h	09h	15h	21h	03h	09h	15h	21h	03h	09h	15h	21h	03h	09h	15h	21h	03h	09h	15h	21h	03h	09h	15h	21h	03h	09h	15h	21h
Météo																												
Vent (km/h)	40	35	35	20	20	10	5	5	15	15	30	30	10	15	20	20	30	45	50	60	70	65	60	40	90	70	90	60
à 3000m																												
Vent (km/h)	15	15	20	10	10	5	10	10	10	10	20	20	10	5	15	10	10	15	15	15	20	25	30	25	30	35	45	35
à 2000m																												

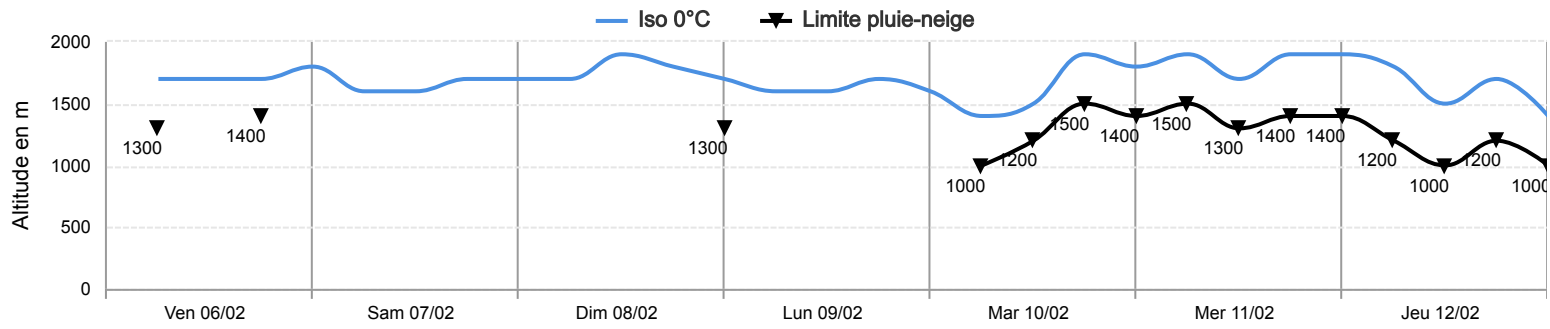

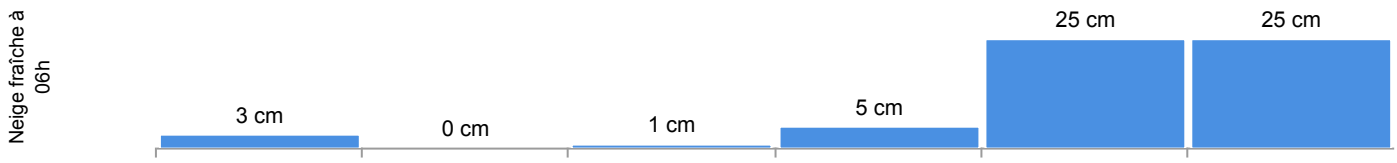

Risque d'avalanche	ven. 06/02	sam. 07/02	dim. 08/02	lun. 09/02	mar. 10/02	mer. 11/02	jeu. 12/02
	4	4	3	3	3	4	4

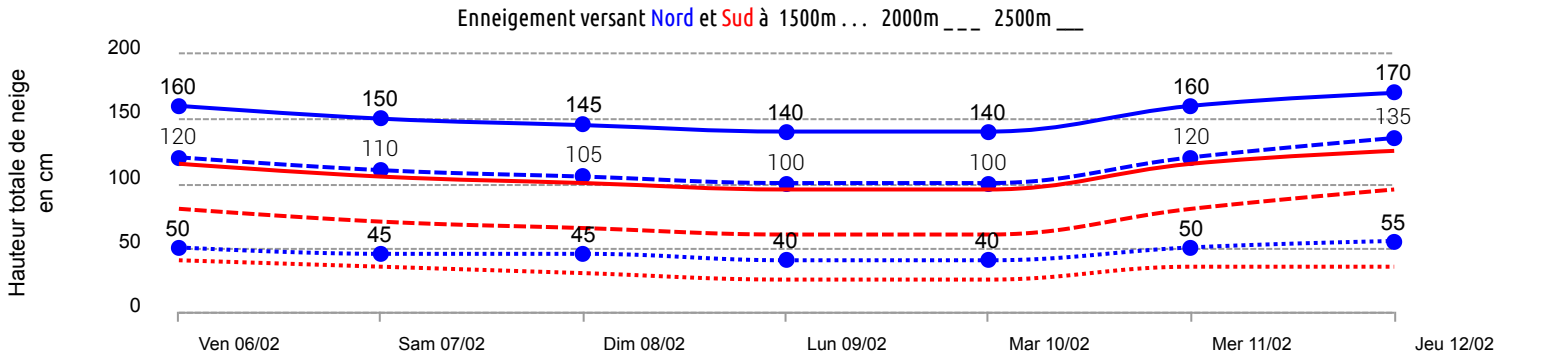

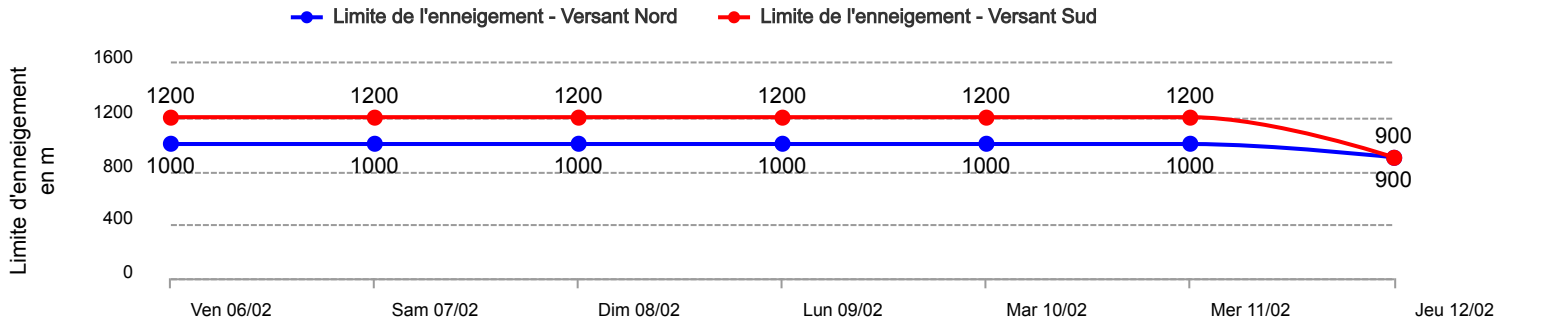

Pour consulter la vigilance en cours, veuillez vous rendre sur le site https://vigilance.meteofrance.fr/fr

Météo-France - 73 avenue de Paris, 94165 Saint-Mandé cedex - Contact : contact@meteo.fr

Rédigé par Météo-France avec la contribution des observateurs du réseau nivo-météorologiques. Partenariat : ANMSM (Maires de Stations de Montagne), DSF (Domaines Skiables de France), ADSP (Directeurs de Pistes et de la Sécurité des Stations de Sports d'Hiver) et autres acteurs de la montagne.

Bulletin neige & avalanches par téléphone au
0 892 68 10 20 Service 0,35 € / min + prix appel