Bulletin d'estimation du risque d'avalanche

(valable en dehors des pistes balisées et ouvertes)

MASSIF : Haut-Var Haut-Verdon

Rédigé le jeudi 12 février 2026 à 16h

Estimation des risques pour le : VENDREDI 13 FÉVRIER

NOMBREUSES INSTABILITÉS EN ALTITUDE EN HAUT VERDON, FACILES À DÉCLENCHER ; MOINS INSTABLE EN HAUT VAR

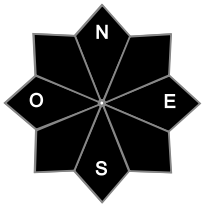

Indice de risque fort à l'ouest du massif, marqué à l'est.

Départs spontanés : avalanches de grande taille encore possibles sous l'effet du vent jeudi soir en Haut Verdon ; nombreux au soleil en journée, moins volumineux

Déclenchements provoqués : nombreuses instabilités dans la neige récente ventée, parfois très volumineuses en Haut Verdon

Indices de risque : 5 très fort - 4 fort - 3 marqué - 2 limité - 1 faible -- En noir : les pentes les plus dangereuses

Stabilité du manteau neigeux

Situation avalancheuse typique : neige fraîche neige ventée

Communiqué spécial avalanches : invitation à la prudence en montagne

Déclenchements provoqués :
Haut Verdon : le manteau neigeux est faiblement stabilisé dans de nombreuses pentes d'altitude supérieure à 2000 m environ. Instabilités sous forme de plaques, possibles en toute orientation. Elles sont déclenchables par un seul skieur, et de taille moyenne (taille 2), parfois grande (taille 3) avec cassure linéaire, dans les zones de forte accumulation par le vent. En orientations ouest, nord et est d'altitude supérieure à 2200 m environ, le déclenchement d'une avalanche de très grande taille (taille 4) n'est pas exclue.
L'épaisse couche de neige récente a été fortement travaillée par le vent tempétueux de nord-ouest ; elle repose par ailleurs sur une couche fragile persistante homogène à la base du manteau neigeux, devenue cependant plus difficilement sollicitable, car bien enfouie.
Haut Var : manteau neigeux modérément stabilisé au-dessus de 2000 m d'altitude environ. Instabilités possibles en toute orientation sous forme de plaques plus souvent d'aspect dur, et identifiables. Elles mobilisent la neige récente fortement ventée et engendrent des avalanches de taille moyenne. Une avalanche de grande taille n'est pas exclue en orientation ouest, nord ou est. Il est tombé beaucoup moins de neige récente dans le Haut Verdon.

Départs spontanés : grandes avalanches possibles sous forme de plaques à vent jeudi soir, beaucoup plus rares en Haut Var. Exceptionnellement, une avalanche de très grande taille approchant les fonds de vallée du Haut Verdon n'est pas exclue. Cette activité s'atténue nettement en deuxième partie de nuit. En journée, départs en neige récente humide au soleil, restant ponctuels et généralement de taille petite à moyenne, bien qu'une grande avalanche ne soit pas exclue

Qualité de la neige

Enneigement abondant, très excédentaire pour un mois de février.
Données observées vers 2000 m en fond de vallon : 160 à 190 cm.

Enneigement skiable dès 1400 m, parfois 1200 m.

État de la neige en surface : neige récente, tombée plus épaisse sur le Haut Verdon à partir de 1600/1800 m, qui s'humidifie au soleil jusque 2000/2200 m environ.. En altitude, et notamment au-dessus de 2200 m, cette neige récente a été fortement travaillée par le vent tempétueux de nord-ouest. Dans le Haut Var où les cumuls de neige récente sont plus faibles, les surfaces sont plus souvent fortement durcies, même loin des crêtes.

Aperçu météo pour le vendredi 13 février

	nuit	matin	après-midi	soir
Courte fenêtre météo le matin. Devenant couvert l'après-midi, faiblement neigeux en fin de journée et nuit suivante				
Pluie-Neige	1 100 m		1 300 m	1 200 m
Iso 0 °C	1 700 m	2 300 m	1 700 m	1 600 m
Vent 2000 m	↘ 60 km/h	↑ 20 km/h	↑ 20 km/h	← 25 km/h
Vent 3000 m	↘ 90 km/h	↘ 20 km/h	↑ 40 km/h	← 60 km/h

Épaisseur de neige hors-piste

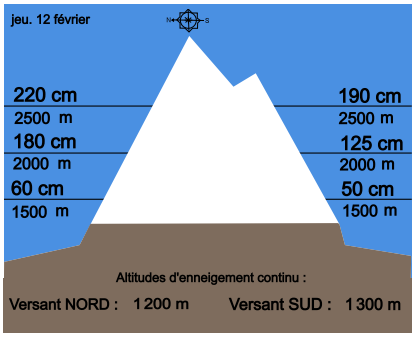

Précipitations à 1800 m

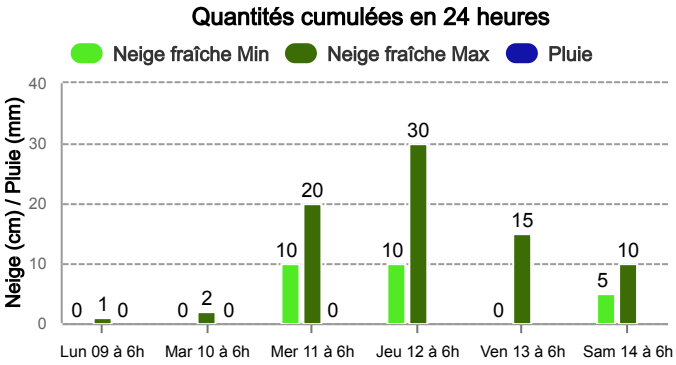

Tendance du samedi 14 février

Indice de risque marqué

Tendance à la stabilisation. Risque restant marqué en altitude.

Pour consulter la vigilance en cours, veuillez vous rendre sur le site https://vigilance.meteofrance.fr/fr

Météo-France - 73 avenue de Paris, 94165 Saint-Mandé cedex - Contact : contact@meteo.fr

Rédigé par Météo-France avec la contribution des observateurs du réseau nivo-météorologiques. Partenariat : ANMSM (Maires de Stations de Montagne), DSF (Domaines Skiables de France), ADSP (Directeurs de Pistes et de la Sécurité des Stations de Sports d'Hiver) et autres acteurs de la montagne.

Bulletin neige & avalanches par téléphone au

0 892 68 10 20 Service 0,35 € / min + prix appel

RÉPUBLIQUE FRANÇAISE
Liberté Égalité Fraternité

METEO FRANCE
À VOS CÔTÉS, DANS UN CLIMAT QUI CHANGE

Bulletin d'estimation du risque d'avalanche

(valable en dehors des pistes balisées et ouvertes)

MASSIF : Haut-Var Haut-Verdon

Rédigé le jeudi 12 février 2026 à 16h

Conditions nivo-météo des 7 derniers jours

	ven. 06/02				sam. 07/02				dim. 08/02				lun. 09/02				mar. 10/02				mer. 11/02				jeu. 12/02			
	03h	09h	15h	21h	03h	09h	15h	21h	03h	09h	15h	21h	03h	09h	15h	21h	03h	09h	15h	21h	03h	09h	15h	21h	03h	09h	15h	21h
Météo																												
Vent (km/h)	50	45	45	30	35	15	15	10	15	30	30	25	15	15	20	30	30	35	50	65	100	110	60	70	80	100	140	130
à 3000m																												
Vent (km/h)	25	35	35	20	20	10	10	10	10	15	20	20	10	5	15	10	10	15	20	20	20	20	30	40	80	90	120	115
à 2000m																												

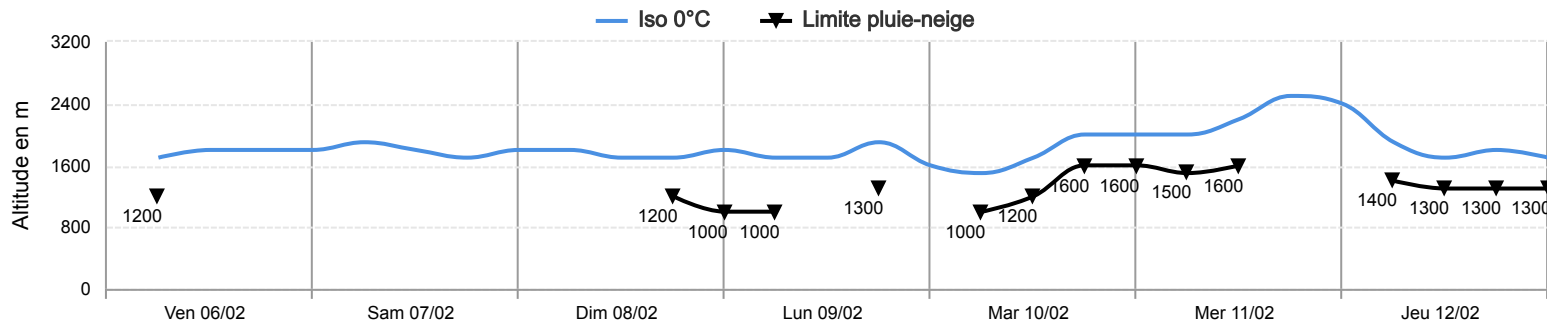

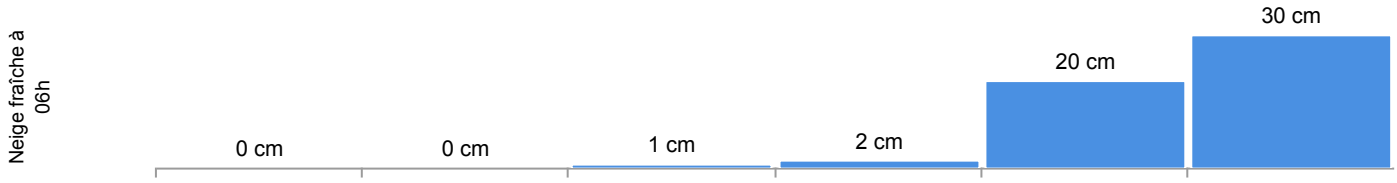

Risque d'avalanche	ven. 06/02	sam. 07/02	dim. 08/02	lun. 09/02	mar. 10/02	mer. 11/02	jeu. 12/02
	4	3	3	3	3	3	4

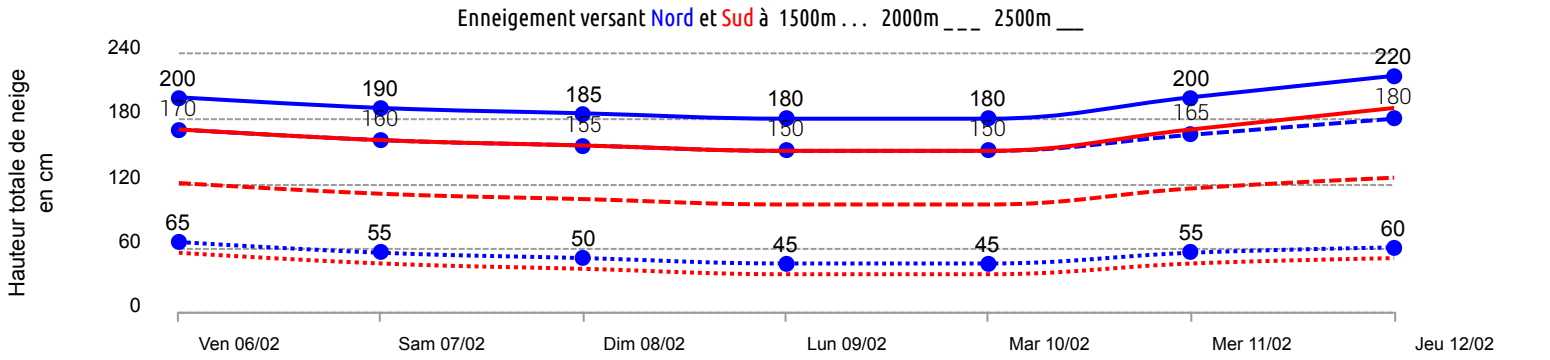

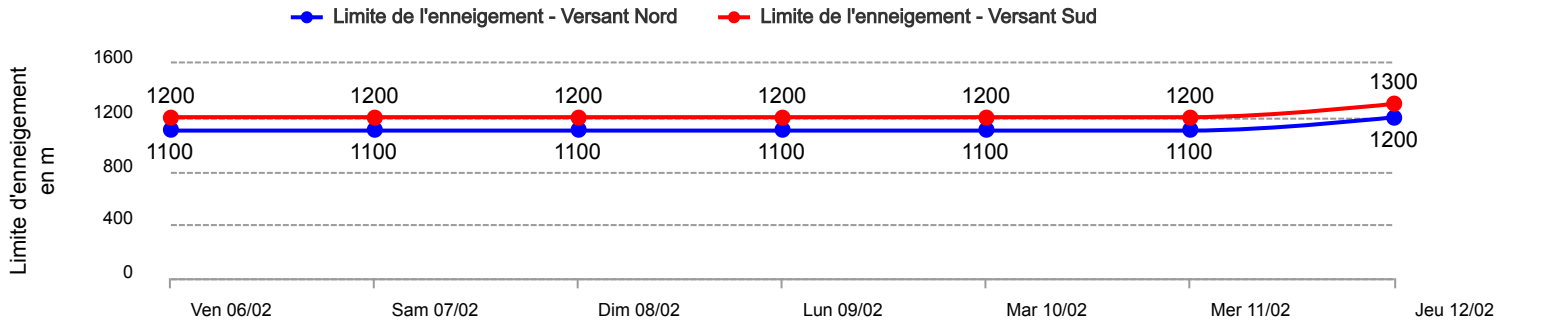

Pour consulter la vigilance en cours, veuillez vous rendre sur le site https://vigilance.meteofrance.fr/fr

Météo-France - 73 avenue de Paris, 94165 Saint-Mandé cedex - Contact : contact@meteo.fr

Rédigé par Météo-France avec la contribution des observateurs du réseau nivo-météorologiques. Partenariat : ANMSM (Maires de Stations de Montagne), DSF (Domaines Skiables de France), ADSP (Directeurs de Pistes et de la Sécurité des Stations de Sports d'Hiver) et autres acteurs de la montagne.

Bulletin neige & avalanches par téléphone au
0 892 68 10 20 Service 0,35 € / min + prix appel