Bulletin d'estimation du risque d'avalanche

(valable en dehors des pistes balisées et ouvertes)

MASSIF : Pelvoux

Rédigé le jeudi 12 février 2026 à 16h

Estimation des risques pour le : VENDREDI 13 FÉVRIER

FORTE INSTABILITÉ DANS LA NEIGE FRAICHE - QUELQUES DÉPARTS NATURELS DE GRANDE AMPLEUR ATTENDUS JUSQU'EN SECONDE PARTIE DE NUIT DE JEUDI A VENDREDI

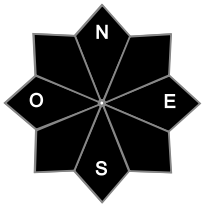

Indices de risque : 5 très fort - 4 fort - 3 marqué - 2 limité - 1 faible -- En noir : les pentes les plus dangereuses

Indice de risque fort.

Départs spontanés : départs ponctuels ou en plaque de neige fraîche dans de nombreuses pentes. Jusqu'en seconde partie de nuit de jeudi à vendredi, possiblement de grande ampleur.

Déclenchements provoqués : nombreuses plaques souvent épaisses, faciles à déclencher

Vigilance orange avalanches en cours ou prévue sur le massif

Stabilité du manteau neigeux

Situation avalancheuse typique : neige fraîche — couche fragile persistante

Invitation à la prudence en montagne (émission d'un communiqué spécial avalanche)

Départs spontanés : jusqu'en cours de seconde partie de nuit de jeudi à vendredi, le risque de forte activité avalancheuse se maintient avec la poursuite des chutes de neige et le vent. Avalanches de neige fraiche avec des départs en poire ou linéaires emportant l'épaisse couche de neige récente ou tout le manteau neigeux en place, souvent sur une grande largeur. Avalanches fréquemment de grande taille (taille 3). Quelques-unes peuvent être d'ampleur plus importante, avec aérosol, et menacer certaines routes ou infrastructures de montagne, en particulier au-dessus de 1600/1700 m (très grandes avalanches, taille 4). Ponctuellement, ces très grandes avalanches parcourent un dénivelé important et risquent d'atteindre certains fonds de vallées à plus basse altitude.

Vendredi, l'activité naturelle est en baisse. Mais en pente raide, de nouvelles avalanches de neige fraîche s'humidifiant avec le soleil / redoux temporaire. Départs en poire ou linéaires, de taille petite à moyenne, plus rarement grande.

Déclenchements provoqués : au-dessus de 1800/2000 m, nombreuses plaques dans la neige fraîche. Faciles à déclencher par le passage d'un seul skieur, mobilisant de très importants volumes de neige dans les pentes les plus chargées. Cassures épaisses et sur de grandes largeurs, notamment en cas de sollicitation de la couche fragile persistante enfouie.
Plus bas, le risque de déclencher une plaque est moins fort, car la neige récente est en partie humidifiée.

Qualité de la neige

L'enneigement est excédentaire pour un mois de février, avec les chutes de neige qui s'enchainent.
Hauteurs de neige observées : 253 cm à la Nivôse de Écrins vers 3000 m, 227 cm au Pré de Mme Carle à 1900 m, 150 cm au hameau de Dormillouse à 1730 m.

Limite d'enneigement skiable : la plupart des itinéraires sont skiables dès les fonds de vallées.

État de la neige de surface : neige fraiche abondante souvent travaillée par le vent en altitude. Plus humide et lourde sous 1800/2000 m.

Aperçu météo pour le vendredi 13 février

Retour d'un temps sec et calme en 2nd partie de nuit de jeudi à vendredi. Nouvelle perturbation de faible activité dès vendredi après-midi.

	nuit	matin	après-midi	soir
Pluie-Neige	900 m		1 400 m	1 200 m
Iso 0 °C	1 600 m	2 000 m	1 800 m	1 500 m
Vent 2000 m	35 km/h	15 km/h	20 km/h	15 km/h
Vent 3000 m	65 km/h	25 km/h	25 km/h	20 km/h

Épaisseur de neige hors-piste

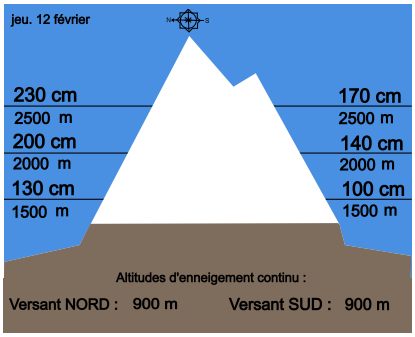

Précipitations à 1800 m

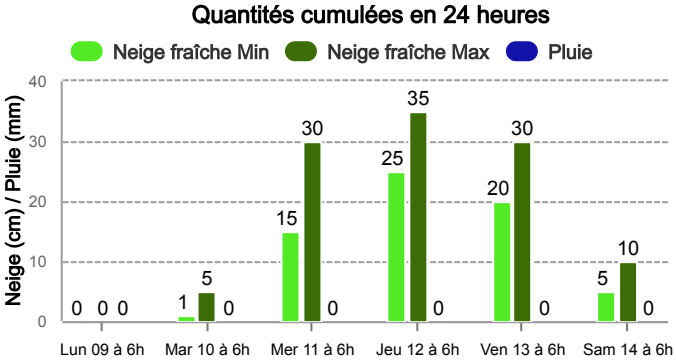

Tendance du samedi 14 février

3 **Indice de risque marqué**

Risque marqué avec des plaques encore faciles à déclencher au passage d'un skieur dans la neige récente.

Pour consulter la vigilance en cours, veuillez vous rendre sur le site https://vigilance.meteofrance.fr/fr

Météo-France - 73 avenue de Paris, 94165 Saint-Mandé cedex - Contact : contact@meteo.fr

Rédigé par Météo-France avec la contribution des observateurs du réseau nivo-météorologiques. Partenariat : ANMSM (Maires de Stations de Montagne), DSF (Domaines Skiables de France), ADSP (Directeurs de Pistes et de la Sécurité des Stations de Sports d'Hiver) et autres acteurs de la montagne.

Bulletin neige & avalanches par téléphone au **0 892 68 10 20** Service 0,35 € / min + prix appel

RÉPUBLIQUE FRANÇAISE
Liberté Égalité Fraternité

METEO FRANCE
À VOS CÔTÉS, DANS UN CLIMAT QUI CHANGE

Bulletin d'estimation du risque d'avalanche
(valable en dehors des pistes balisées et ouvertes)

MASSIF : Pelvoux

Rédigé le jeudi 12 février 2026 à 16h

Conditions nivo-météo des 7 derniers jours

	ven. 06/02				sam. 07/02				dim. 08/02				lun. 09/02				mar. 10/02				mer. 11/02				jeu. 12/02			
	03h	09h	15h	21h	03h	09h	15h	21h	03h	09h	15h	21h	03h	09h	15h	21h	03h	09h	15h	21h	03h	09h	15h	21h	03h	09h	15h	21h
Météo																												
Vent (km/h)	25	30	25	20	20	10	10	10	10	15	20	20	10	15	15	20	30	30	30	80	70	70	50	50	90	80	120	110
à 3000m																												
Vent (km/h)	5	10	15	10	5	5	10	5	5	15	20	20	5	5	10	10	10	15	20	20	20	20	30	25	30	35	65	55
à 2000m																												

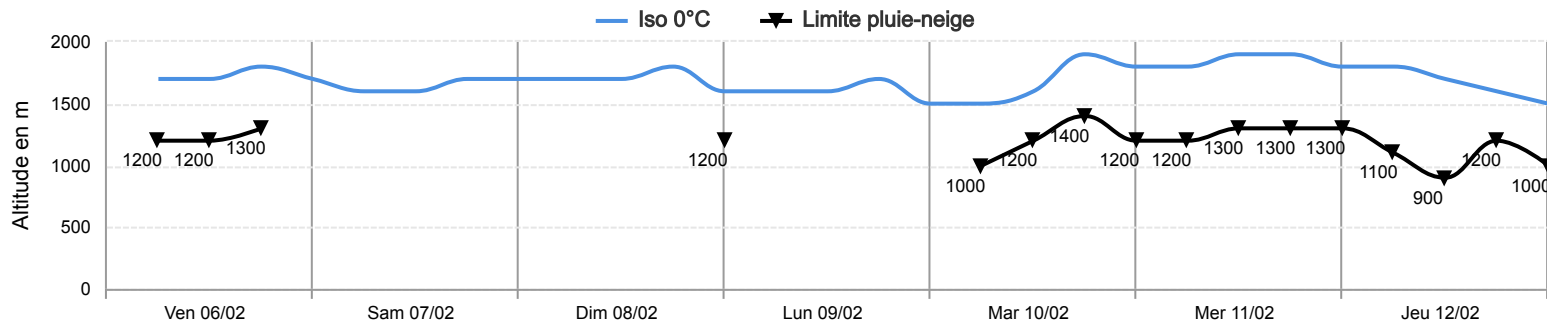

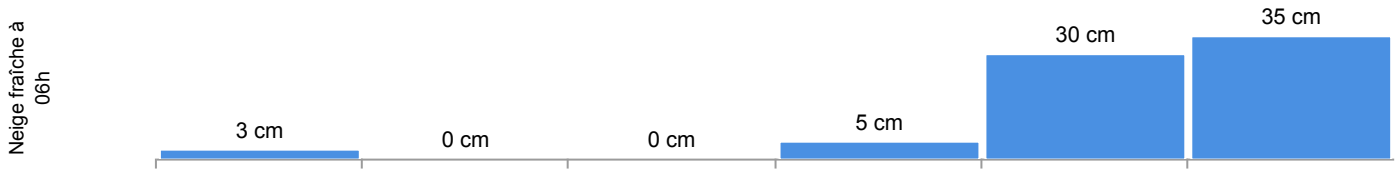

Risque d'avalanche							
	ven. 06/02	sam. 07/02	dim. 08/02	lun. 09/02	mar. 10/02	mer. 11/02	jeu. 12/02

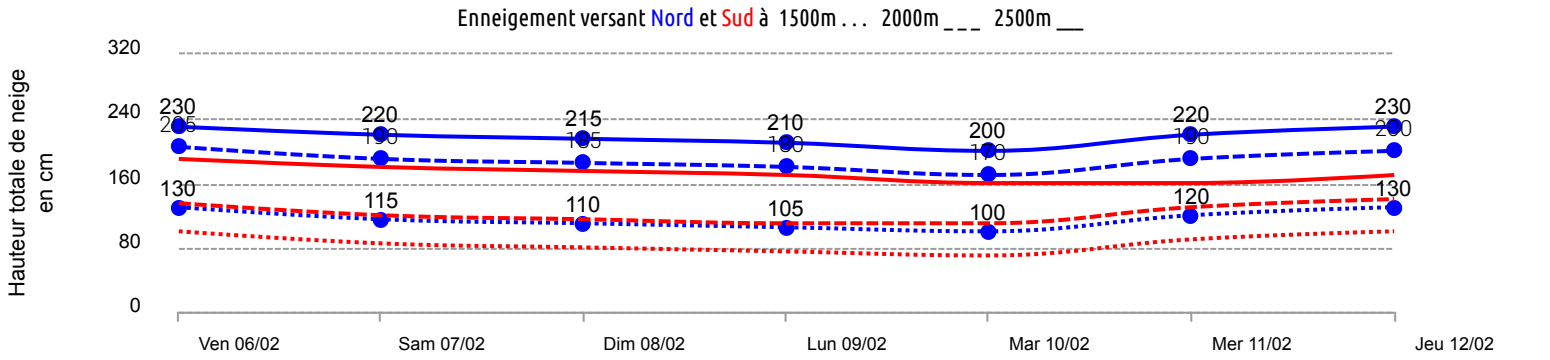

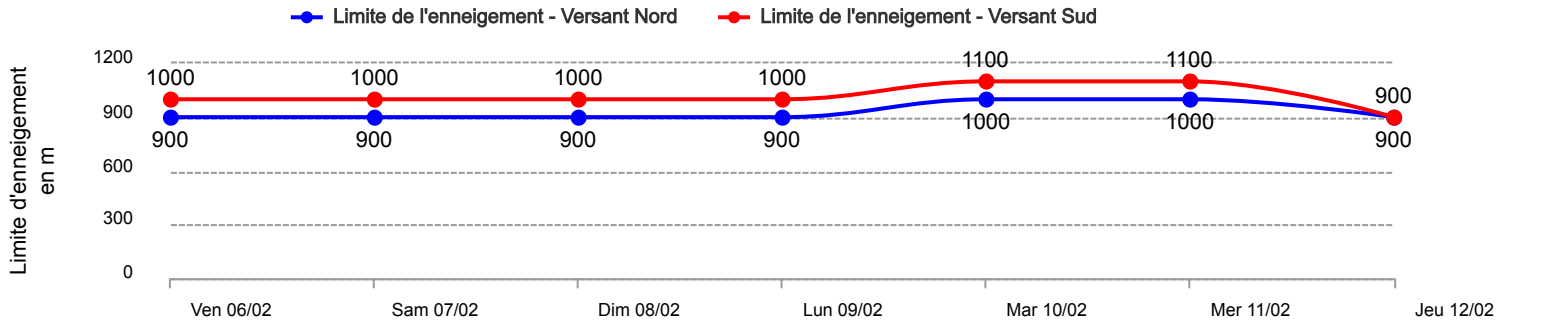

Pour consulter la vigilance en cours, veuillez vous rendre sur le site https://vigilance.meteofrance.fr/fr

Météo-France - 73 avenue de Paris, 94165 Saint-Mandé cedex - Contact : contact@meteo.fr

Rédigé par Météo-France avec la contribution des observateurs du réseau nivo-météorologiques. Partenariat : ANMSM (Maires de Stations de Montagne), DSF (Domaines Skiables de France), ADSP (Directeurs de Pistes et de la Sécurité des Stations de Sports d'Hiver) et autres acteurs de la montagne.

Bulletin neige & avalanches par téléphone au
0 892 68 10 20 Service 0,35 € / min + prix appel