# Bulletin d'estimation du risque d'avalanche
(valable en dehors des pistes balisées et ouvertes)

# MASSIF : Pays-Basque

Rédigé le jeudi 12 février 2026 à 17h

## Estimation des risques pour le : VENDREDI 13 FÉVRIER

**FINES PLAQUES A VENT SUR UN MANTEAU STABLE**

2

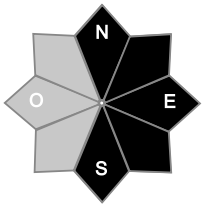


Fines plaques

Indice de risque limité.

**Départs spontanés :** En neige humide de petite taille en général

**Déclenchements provoqués :** Fines plaques à vent au plus haut du massif

Indices de risque : 5 très fort - 4 fort - 3 marqué - 2 limité - 1 faible -- En noir : les pentes les plus dangereuses

## Stabilité du manteau neigeux

**Situation avalancheuse typique :** neige ventée — avalanches de fond

**Déclenchements provoqués :**
De fines plaques à vent se forment en journée à proximité de la frontière plutôt dans un large secteur nord-est au-dessus de 1800m, puis, en fin d'après-midi, dans un large secteur est sur l'ensemble du massif un peu plus bas Elles peuvent être facilement mais restent d'épaisseur modeste, ne suffisant pas en général à emporter un pratiquant.

**Départs spontanés** : En journée, dans une ambiance un peu plus douce que la veille, petits départs ponctuels de neige fraîche s'humidifiant (tous versants possibles), plus rarement une avalanche de fond de taille moyenne possible, plutôt sur les pentes nord à est d'altitude encore assez bien enneigées.

**Autres :** Expositions ouest lustrées par le vent, glace vive affleurant en surface.

## Qualité de la neige

**Enneigement** : L'enneigement a bien diminué avec le dernier redoux. Les crêtes, cols et sommets en expositions ouest sont souvent pelés, ou en glace. De petites accumulations sont présentes dans un large secteur Est.
**Limites skiables** : Manteau neigeux skiable à partir de 1600 m.
**État de la neige** : Le manteau neigeux est bien humidifié jusqu'en profondeur, avec un regel de quelques cm en surface, s'humidifiant en journée. Les quelques cm de la veille s'humidifient aussi.

## Aperçu météo pour le vendredi 13 février

Faibles chutes de neige proches de la frontière, se généralisant l'après-midi. Début d'un blocage de nord-ouest en soirée.

| | nuit | matin | après-midi | soir |
|---|---|---|---|---|
| **Pluie-Neige** | 1 500 m | 1 600 m | 1 300 m | 1 100 m |
| **Iso 0 °C** | 1 800 m | 1 900 m | 1 600 m | 1 300 m |
| **Vent 1000 m** | 50 km/h | 65 km/h | 40 km/h | 60 km/h |
| **Vent 2000 m** | 85 km/h | 90 km/h | 65 km/h | 70 km/h |

## Épaisseur de neige hors-piste

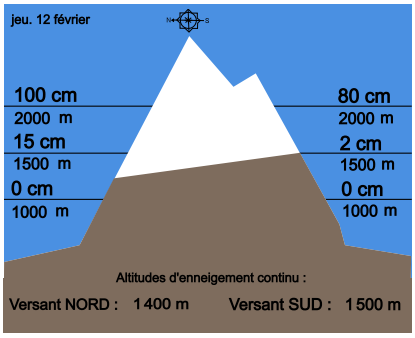


## Précipitations à 1800 m

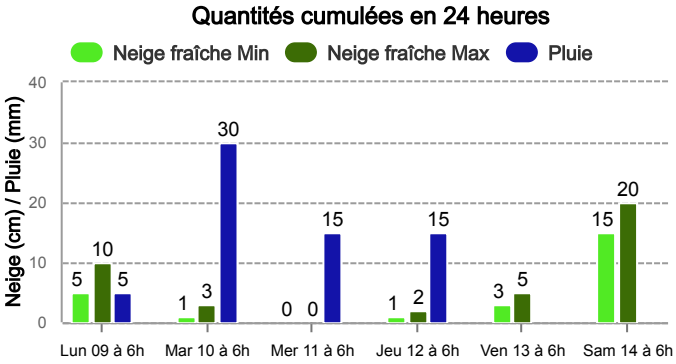


## Tendance du samedi 14 février

3

**Indice de risque marqué**

Risque en hausse, quantités conséquentes de neige fraîche.

Pour consulter la vigilance en cours, veuillez vous rendre sur le site https://vigilance.meteofrance.fr/fr

Météo-France - 73 avenue de Paris, 94165 Saint-Mandé cedex - Contact : contact@meteo.fr

Rédigé par Météo-France avec la contribution des observateurs du réseau nivo-météorologiques. Partenariat : ANMSM (Maires de Stations de Montagne), DSF (Domaines Skiables de France), ADSP (Directeurs de Pistes et de la Sécurité des Stations de Sports d'Hiver) et autres acteurs de la montagne.

Bulletin neige & avalanches par téléphone au 0 892 68 10 20 Service 0,35 € / min + prix appel

RÉPUBLIQUE FRANÇAISE
*Liberté Égalité Fraternité*

METEO FRANCE
À VOS CÔTÉS, DANS UN CLIMAT QUI CHANGE

# Bulletin d'estimation du risque d'avalanche
## (valable en dehors des pistes balisées et ouvertes)

# MASSIF : Pays-Basque

Rédigé le jeudi 12 février 2026 à 17h

## Conditions nivo-météo des 7 derniers jours

| | ven. 06/02 | | | | sam. 07/02 | | | | dim. 08/02 | | | | lun. 09/02 | | | | mar. 10/02 | | | | mer. 11/02 | | | | jeu. 12/02 | | | |
|---|---|---|---|---|---|---|---|---|---|---|---|---|---|---|---|---|---|---|---|---|---|---|---|---|---|---|---|---|
| | 03h | 09h | 15h | 21h | 03h | 09h | 15h | 21h | 03h | 09h | 15h | 21h | 03h | 09h | 15h | 21h | 03h | 09h | 15h | 21h | 03h | 09h | 15h | 21h | 03h | 09h | 15h | 21h |
| Météo | | | | | | | | | | | | | | | | | | | | | | | | | | | | |
| Vent (km/h) | 95 | 95 | 80 | 70 | 70 | 70 | 80 | 90 | 90 | 40 | 45 | 30 | 60 | 50 | 50 | 60 | 70 | 90 | 90 | 80 | 70 | 80 | 100 | 120 | 120 | 110 | 80 | 50 |
| à 2000m | ↗ | ↗ | ↗ | ↗ | ↗ | ↗ | ↑ | ↑ | ↑ | ↘ | ↘ | ↑ | ↗ | ↗ | ↗ | ↗ | ↗ | ↗ | ↗ | ↗ | ↗ | ↗ | ↗ | ↗ | ↗ | → | ↘ | ↗ |
| Vent (km/h) | 75 | 70 | 60 | 50 | 55 | 55 | 60 | 65 | 60 | 25 | 35 | 20 | 30 | 40 | 30 | 40 | 50 | 60 | 65 | 50 | 40 | 50 | 70 | 80 | 80 | 70 | 40 | 20 |
| à 1000m | ↗ | ↗ | ↑ | ↑ | ↗ | ↗ | ↑ | ↑ | ↑ | ↗ | → | ↑ | ↑ | ↑ | ↑ | ↑ | ↗ | ↗ | ↗ | → | → | ↑ | ↑ | ↗ | ↗ | → | ↘ | ↗ |

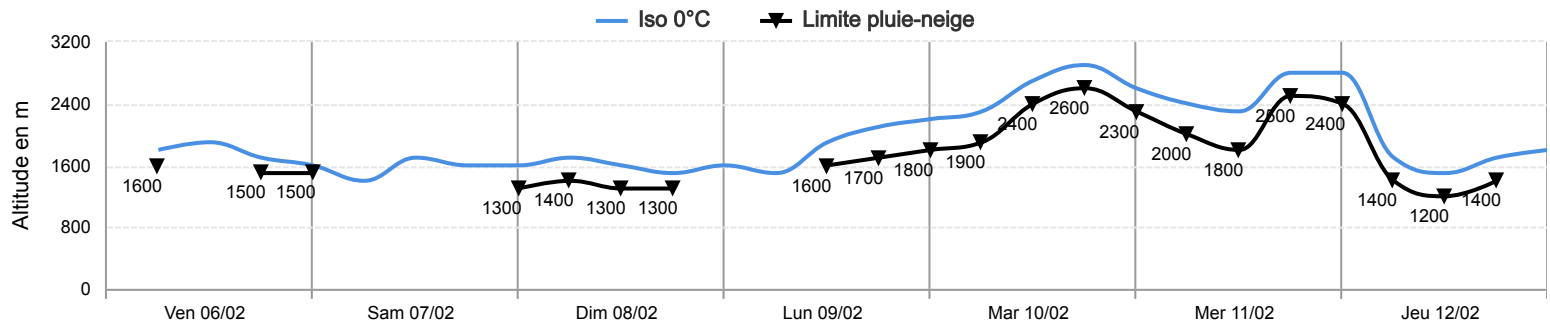


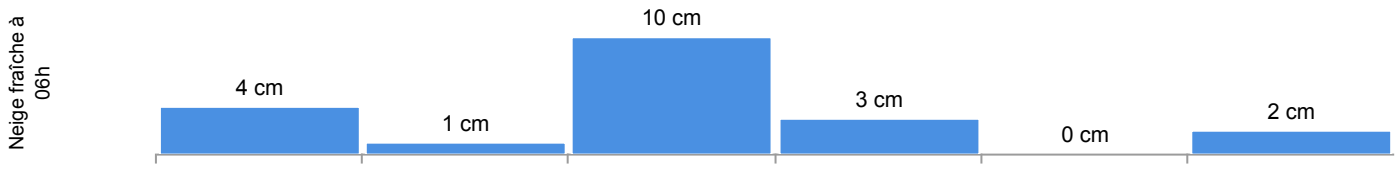


| Risque d'avalanche | ven. 06/02 | sam. 07/02 | dim. 08/02 | lun. 09/02 | mar. 10/02 | mer. 11/02 | jeu. 12/02 |
|---|---|---|---|---|---|---|---|
| | 2 | 2 | 2 | 2 | 3 | 3 | 2 |

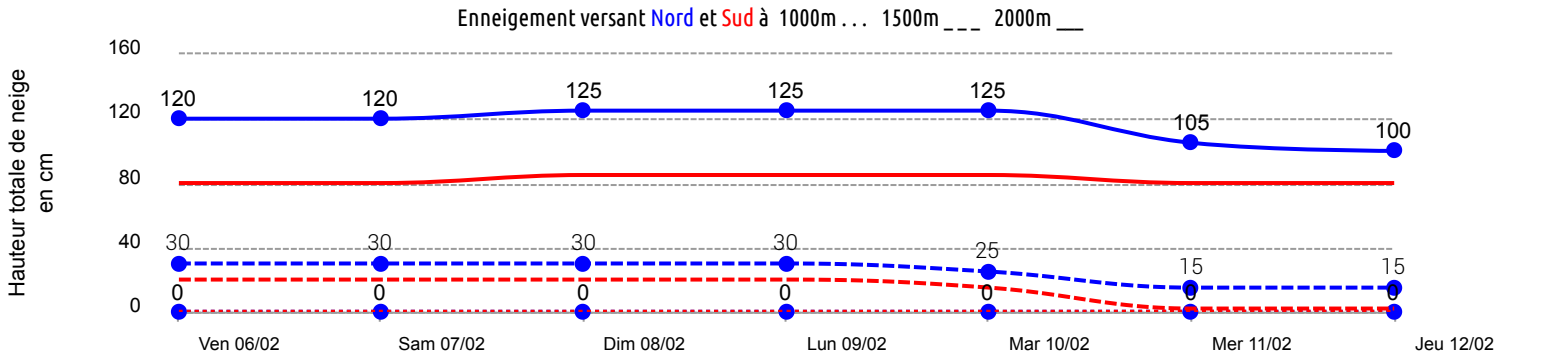


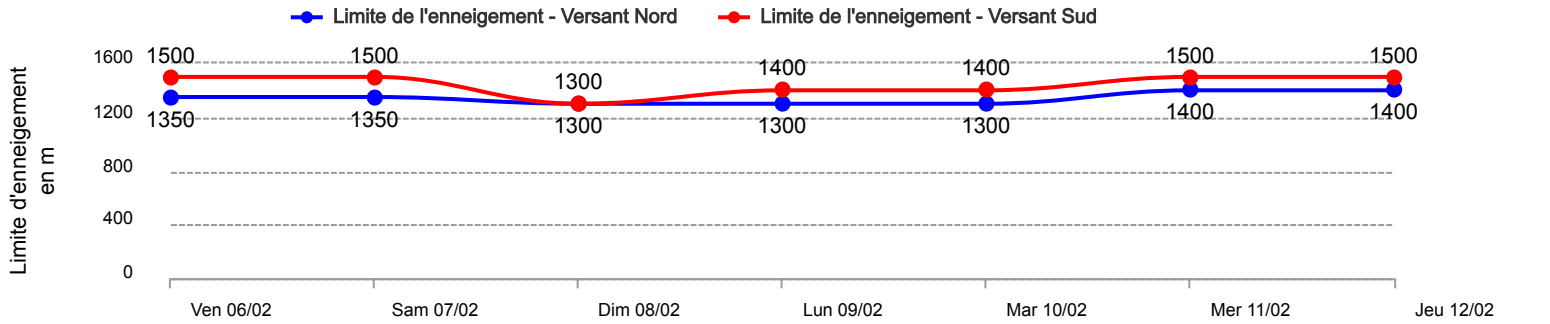


Pour consulter la vigilance en cours, veuillez vous rendre sur le site https://vigilance.meteofrance.fr/fr


Météo-France - 73 avenue de Paris, 94165 Saint-Mandé cedex - Contact : contact@meteo.fr


Bulletin neige & avalanches par téléphone au **0 892 68 10 20** Service 0,35 € / min + prix appel


Rédigé par Météo-France avec la contribution des observateurs du réseau nivo-météorologiques. Partenariat : ANMSM (Maires de Stations de Montagne), DSF (Domaines Skiables de France), ADSP (Directeurs de Pistes et de la Sécurité des Stations de Sports d'Hiver) et autres acteurs de la montagne.