GOBIERNO DE ESPAÑA
VICEPRESIDENCIA TERCERA DEL GOBIERNO
MINISTERIO PARA LA TRANSICIÓN ECOLÓGICA Y EL RETO DEMOGRÁFICO

# Boletín de información nivológica y de peligro de aludes

# Pirineo Catalán

aemet Agencia Estatal de Meteorología

## viernes, 13 de febrero de 2026

## Pronóstico hasta las 24 horas del sábado, día 14 de febrero

(Válido fuera de pistas de esquí balizadas y abiertas)

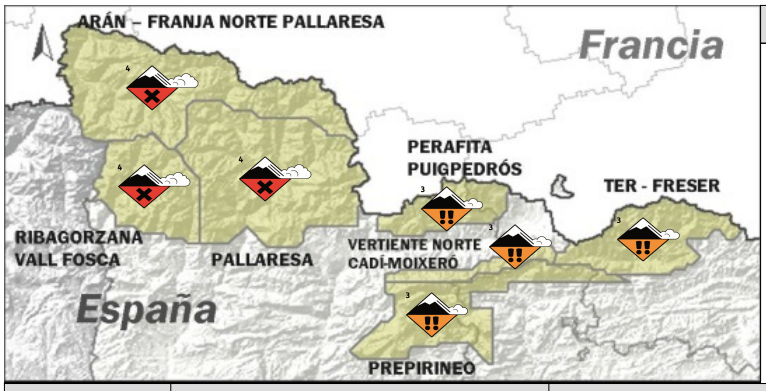


### Problemas de aludes

Placas de viento

Nieve reciente

| Macizo | Peligro | Problemas de aludes, cota, orientación, tamaño | Innivación observada (m) |
|---|---|---|---|
| Arán - Franja norte Pallaresa | 4 Fuerte | Placas de viento: 1800; N O E S; 3<br>Nieve reciente: N O E S; 3 | 2026-02-13<br>N S<br>Cotas bajas |
| Ribagorzana - Vall Fosca | 4 Fuerte | Placas de viento: 1800; N O E S; 3<br>Nieve reciente: N O E S; 3 | 2026-02-13<br>N S<br>Cotas bajas |
| Pallaresa | 4 Fuerte | Placas de viento: 1800; N O E S; 3<br>Nieve reciente: N O E S; 3 | 2026-02-13<br>N S<br>Cotas bajas |

Boletín de información nivológica y de peligro de aludes

# Pirineo Catalán



| | | | |
|---|---|---|---|
| **Perafita - Puigpedrós** | 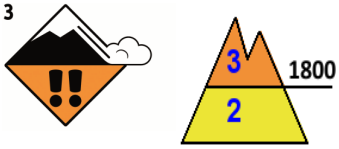  **Notable** | **Placas de viento** **Nieve reciente** 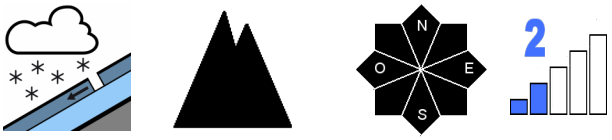  | 2026-02-13 Cotas bajas |
| **Ter - Freser** | 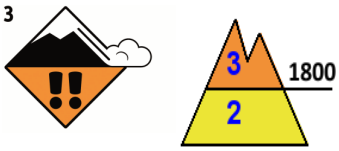  **Notable** | **Placas de viento** 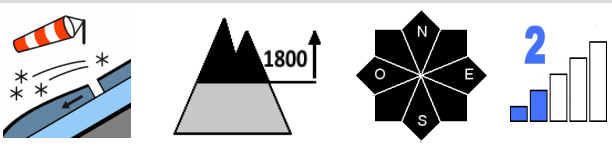  **Nieve reciente** 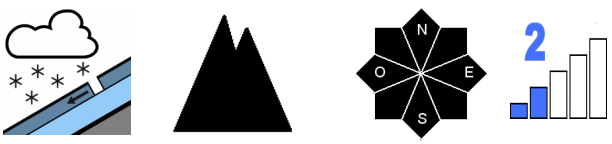  | 2026-02-13 Cotas bajas |
| **Vertiente norte Cadí - Moixeró** | 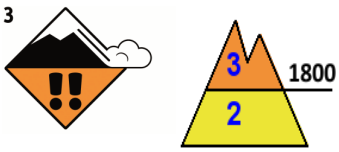  **Notable** | **Placas de viento** 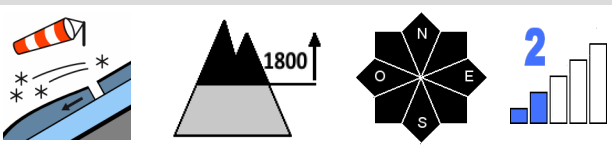  **Nieve reciente** 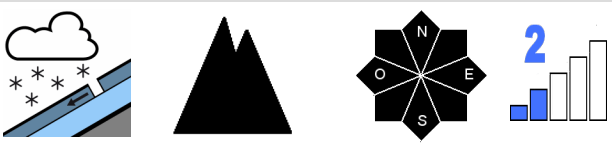  | 2026-02-13 Cotas bajas |
| **Prepirineo** | 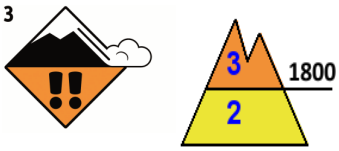  **Notable** | **Placas de viento** 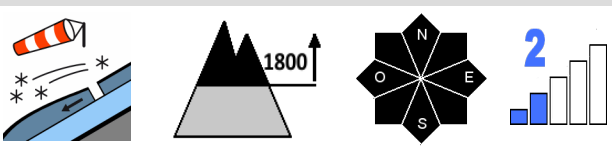  **Nieve reciente**   | 2026-02-13 Cotas bajas |

## Estado del manto y observaciones recientes

Después de un día de transición, que dio lugar a costra de rehielo generalizada en superficie, con la génesis de la nueva borrasca Oriana da comienzo un nuevo episodio de copiosas nevadas desde cotas bajas.

Una capa de nieve reciente está ganando espesor progresivamente al tiempo que se aposenta sobre esta costra de rehielo, que está presente hasta cotas altas. En cotas medias y bajas, la costra posee un grosor significativo y el manto se ha humedecido hasta la base. En


AEMET. Se autoriza la reproducción de su contenido citando la fuente.

cotas altas, la costra es más fina y la humidificación se ha quedado en niveles más superficiales. En la alta montaña, la nieve nueva se está depositando sobre la antigua nieve seca y venteada. Además, las capas débiles persistentes pueden seguir presentes en las umbrías, aunque serán más difíciles de activar en las zonas donde se formó costra superficial.

El manto se muestra continuo desde cotas bajas con espesores que se van incrementando conforme ascendemos, de manera que en la mayor parte de la cordillera se encuentran en máximos, muy por encima de lo que cabría esperar a estas alturas de la temporada, superándose los 150 a 200 cm por encima de 2.200 metros en numerosas áreas, aún más en ventisqueros, hoyas y otras zonas propensas a la acumulación.

## Evolución del manto y peligro de aludes para el sábado, día 14

Problemas de placas de viento y nieve reciente.

Los vientos girarán a componente norte y se intensificarán aún más. Las nevadas se harán más intensas y persistentes, dando como resultado acumulados muy importantes, sobre todo en el sector del Arán-F.N.Pallaresa, donde se superarán fácilmente los 60 cm en 48 horas, y también en Ribagorzana-Vall Fosca y Pallaresa, donde localmente se podrán superar los 40 cm.

Se formarán numerosas placas de viento en cotas altas de todas las orientaciones, aunque con predominio del sector sur. Podrán hacerlo alejadas de crestas y cordales y también en cotas medias. Además, en la alta montaña, estas se aposentarán sobre la antigua nieve seca y venteada. Las placas serán susceptibles de colapsar ante sobrecargas débiles y dar lugar a aludes de tamaño mediano o grande según la zona, sin descartar localmente alguno mayor en el Arán-F.N.Pallaresa.

Serán frecuentes las purgas de nieve reciente en laderas lo suficientemente inclinadas. Estas podrán alcanzar el tamaño grande en las zonas con mayor acumulación.

## Predicción meteorológica para el sábado, día 14

Muy nuboso o cubierto, tendiendo a abrir algunos claros en la mayoría de zonas salvo en el Arán y resto de la divisoria fronteriza. Visibilidad localmente reducida. En el valle de Arán y norte de la Pallaresa, se esperan precipitaciones moderadas y persistentes, a veces en forma de chubascos, con tendencia a remitir a últimas horas. En el resto de zonas, serán menos intensas y frecuentes. Cota de nieve bajando de 1300 a 300-500 metros aproximadamente. Temperaturas en ligero o moderado descenso, salvo en el Prepirineo y zonas próximas, donde las máximas irán en ligero o moderado ascenso. Heladas débiles o moderadas, fuertes y persistentes en cotas altas. Ambiente gélido. Viento fuerte de componente norte, con rachas muy fuertes, huracanadas en cotas altas y otras zonas expuestas.

Datos en la atmósfera libre:

Altitud de la isoterma de 0 ºC: 1400 m
Altitud de la isoterma de -10 ºC: 3000 m

Viento a 1500 m: N 60 km/h
Viento a 3000 m: N 110 km/h


AEMET. Se autoriza la reproducción de su contenido citando la fuente.

## Evolución para el domingo día 15

Nivel de peligro con pocos cambios.

Escala europea de peligro de aludes

Débil | Limitado | Notable | Fuerte | Muy Fuerte

Problemas de aludes

Nieve reciente | Placas de viento | Capas débiles persistentes | Nieve húmeda | Deslizamientos basales | Sin problema evidente

Nota1: Se recuerda que, siempre que haya nieve, la ausencia total de peligro no existe. Hay que tener presente que en circunstancias desfavorables, con aludes de tamaño 1 (alud pequeño o colada) y tamaño 2 (alud mediano), se pueden sufrir severos daños personales.

Nota2: Los BPA se elaboran en base a información meteorológica así como al estado del manto nivoso a través de sondeos puntuales. Se advierte a los usuarios de la variabilidad de esta información al extrapolarla a zonas extensas de montaña. Por ello, AEMET no se hace responsable de su uso para la toma de decisiones que conciernen a la seguridad personal, ni de los riesgos físicos o materiales de ellas derivadas.


AEMET. Se autoriza la reproducción de su contenido citando la fuente.