GOBIERNO DE ESPAÑA
VICEPRESIDENCIA TERCERA DEL GOBIERNO
MINISTERIO PARA LA TRANSICIÓN ECOLÓGICA Y EL RETO DEMOGRÁFICO

Boletín de información nivológica y de peligro de aludes

Pirineo Navarro y Aragonés

aemet Agencia Estatal de Meteorología

viernes, 13 de febrero de 2026

Pronóstico hasta las 24 horas del sábado, día 14 de febrero

(Válido fuera de pistas de esquí balizadas y abiertas)

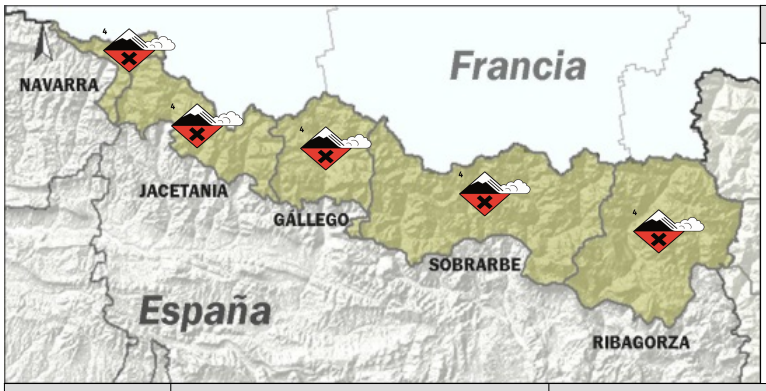

Problemas de aludes

Placas de viento

Nieve reciente

Macizo	Peligro	Problemas de aludes, cota, orientación, tamaño	Innivación observada (m)
Navarra	4 Fuerte	**Placas de viento**: 1800, N O E S, 3 **Nieve reciente**: N O E S, 3	2026-02-13 N S Cotas bajas
Jacetania	4 Fuerte	**Placas de viento**: 1800, N O E S, 3 **Nieve reciente**: N O E S, 3	2026-02-13 N S Cotas bajas
Gállego	4 Fuerte	**Placas de viento**: 1800, N O E S, 3 **Nieve reciente**: N O E S, 3	2026-02-13 N S Cotas bajas

AEMET. Se autoriza la reproducción de su contenido citando la fuente.

Boletín de información nivológica y de peligro de aludes

Pirineo Navarro y Aragonés

Sobrarbe	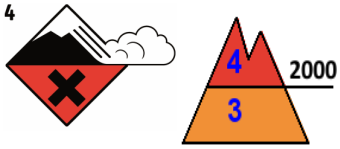 **Fuerte**	**Placas de viento** **Nieve reciente** 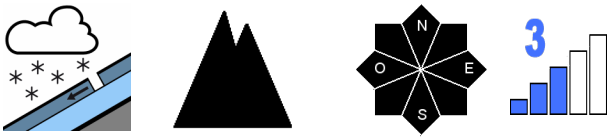	2026-02-13
Ribagorza	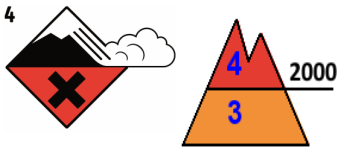 **Fuerte**	**Placas de viento** 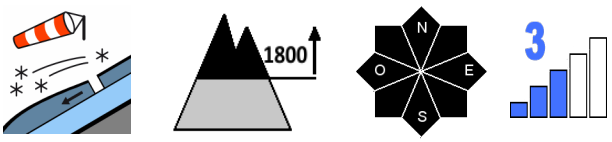 **Nieve reciente** 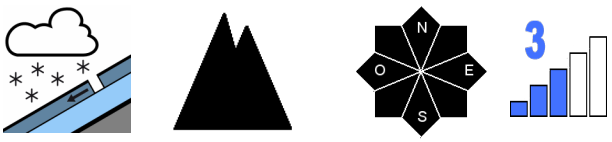	2026-02-13

Estado del manto y observaciones recientes

Después de un día de transición, que dio lugar a costra de rehielo generalizada en superficie, con la génesis de la nueva borrasca Oriana da comienzo un nuevo episodio de copiosas nevadas desde cotas bajas.

Una capa de nieve reciente está ganando espesor progresivamente al tiempo que se aposenta sobre esta costra de rehielo, que está presente hasta unos 2600-2800 metros. Localmente, se podría encontrar una delgada capa de nieve granulada entre ambas. En cotas medias y bajas, la costra posee un grosor significativo y el manto se ha humedecido hasta la base. En cotas altas, la costra es más fina y la humidificación se ha quedado en niveles más superficiales. Por encima de 2800 metros, la nieve nueva se está depositando sobre la antigua nieve seca y venteada. Además, las capas débiles persistentes siguen presentes en las umbrías, aunque serán más difíciles de activar por debajo de los 2800 metros.

El manto se mantiene continuo desde cotas bajas, con espesores que se van incrementando conforme ascendemos, de manera que en torno a 2.100 metros se superan fácilmente los 180 a 200 cm, aún más en ventisqueros, hoyas y otras zonas propensas a la acumulación. Estos valores siguen siendo muy superiores a lo que se considera normal para la época.

Evolución del manto y peligro de aludes para el sábado, día 14

Problemas de placas de viento y nieve reciente.

Los vientos girarán a componente norte y se intensificarán aún más. Las nevadas se harán más intensas y persistentes, dando como resultado acumulados muy importantes en Navarra, Jacetania y Alto Gállego, y también en el entorno de la divisoria fronteriza del Sobrarbe y la Ribagorza, zonas en las que se superarán fácilmente los 50 cm en 48 horas.

AEMET. Se autoriza la reproducción de su contenido citando la fuente.

Se formarán numerosas placas de viento en cotas altas de todas las orientaciones, aunque con predominio del sector sur. Podrán hacerlo alejadas de crestas y cordales y también en cotas medias. Además, por encima de 2800, estas se aposentarán sobre la antigua nieve seca y venteada. Las placas serán susceptibles de colapsar ante sobrecargas débiles y dar lugar a aludes de tamaño grande, sin descartar localmente alguno mayor.

Serán frecuentes las purgas de nieve reciente en laderas lo suficientemente inclinadas. Estas podrán alcanzar el tamaño grande en las zonas con mayor acumulación.

Predicción meteorológica para el sábado, día 14

Pirineo navarro:
Muy nuboso o cubierto. Visibilidad localmente reducida. Precipitaciones débiles o moderadas, a veces en forma de chubascos, que podrían ser localmente persistentes y tenderán a remitir al final del día. Cota de nieve bajando de 1200 a 700 metros aproximadamente. No se descarta alguna tormenta ocasional durante la primera mitad del día. Temperaturas en ligero o moderado descenso. Heladas débiles o moderadas, localmente fuertes y persistentes en cotas altas. Viento fuerte del norte y noroeste, con rachas muy fuertes, que podrán superar los 100 km/h en cotas altas y zonas expuestas.

Pirineo aragonés:
Muy nuboso o cubierto, tendiendo a abrir algunos claros al sur de la divisoria fronteriza. Visibilidad localmente reducida. Precipitaciones débiles o moderadas, a veces en forma de chubascos, que podrán ser persistentes en la divisoria con Francia y zonas próximas, con tendencia a remitir a últimas horas. Cota de nieve bajando de unos 1200 a 400-600 metros aproximadamente. Temperaturas en ligero o moderado descenso, salvo en el Prepirineo y zonas próximas donde las máximas irán en ligero o moderado ascenso. Heladas débiles o moderadas, fuertes y persistentes en cotas altas. Ambiente gélido. Viento fuerte de componente norte, con rachas muy fuertes, huracanadas en cotas altas y otras zonas expuestas.

Datos en la atmósfera libre:

Altitud de la isoterma de 0 ºC: 1400 m
Altitud de la isoterma de -10 ºC: 3000 m

Viento a 1500 m: N 50 km/h
Viento a 3000 m: N 120 km/h

Evolución para el domingo día 15

Nivel de peligro con pocos cambios.

(Información elaborada a partir de los datos recibidos de los refugios de Linza, Lizara, Panticosa, Bachimaña, Góriz, Pineta, Estós, Angel Orús, Cap de Llauset y Belagua, de las estaciones de esquí de Candanchú, Astún, Formigal y Panticosa (lagos), de la estación de esquí de fondo de Llanos del Hospital y de Ordesa Pradera)

Escala europea de peligro de aludes

Débil | Limitado | Notable | Fuerte | Muy Fuerte

Problemas de aludes

Nieve reciente | Placas de viento | Capas débiles persistentes | Nieve húmeda | Deslizamientos basales | Sin problema evidente

AEMET. Se autoriza la reproducción de su contenido citando la fuente.

Nota1: Se recuerda que, siempre que haya nieve, la ausencia total de peligro no existe. Hay que tener presente que en circunstancias desfavorables, con aludes de tamaño 1 (alud pequeño o colada) y tamaño 2 (alud mediano), se pueden sufrir severos daños personales.

Nota2: Los BPA se elaboran en base a información meteorológica así como al estado del manto nivoso a través de sondeos puntuales. Se advierte a los usuarios de la variabilidad de esta información al extrapolarla a zonas extensas de montaña. Por ello, AEMET no se hace responsable de su uso para la toma de decisiones que conciernen a la seguridad personal, ni de los riesgos físicos o materiales de ellas derivadas.

AEMET. Se autoriza la reproducción de su contenido citando la fuente.